GOBIERNO DE ESPAÑA
VICEPRESIDENCIA TERCERA DEL GOBIERNO
MINISTERIO PARA LA TRANSICIÓN ECOLÓGICA Y EL RETO DEMOGRÁFICO

Boletín de información nivológica y de peligro de aludes

Pirineo Catalán

aemet Agencia Estatal de Meteorología

viernes, 20 de febrero de 2026

Pronóstico hasta las 24 horas del sábado, día 21 de febrero

(Válido fuera de pistas de esquí balizadas y abiertas)

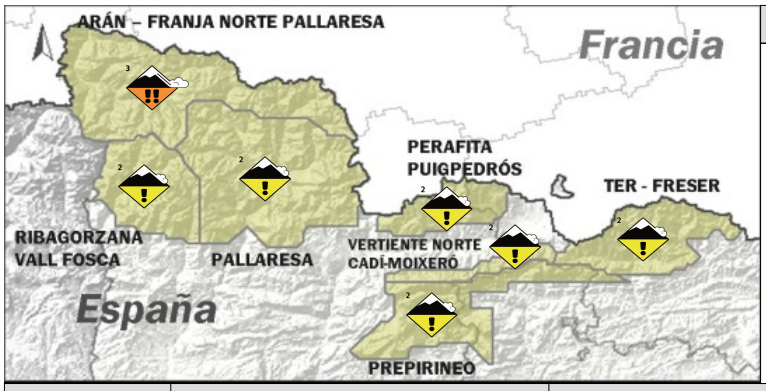

Problemas de aludes

Placas de viento

Nieve húmeda

Macizo	Peligro	Problemas de aludes, cota, orientación, tamaño	Innivación observada (m)
Arán - Franja norte Pallaresa	3 (Durante el día: 3 / 2→3, 2000) **Notable**	**Placas de viento** 2000, N O E S, 2 **Nieve húmeda** 2100, N O E S, 2	2026-02-20 N S Cotas bajas
Ribagorzana - Vall Fosca	2 **Limitado**	**Placas de viento** 2000, N O E S, 2 **Nieve húmeda** 2100, N O E S, 2	2026-02-20 N S Cotas bajas
Pallaresa	2 **Limitado**	**Placas de viento** 2000, N O E S, 2 **Nieve húmeda** 2100, N O E S, 2	2026-02-20 N S Cotas bajas

AEMET. Se autoriza la reproducción de su contenido citando la fuente.

Boletín de información nivológica y de peligro de aludes

Pirineo Catalán

Perafita - Puigpedrós	2 **Limitado**	**Placas de viento** 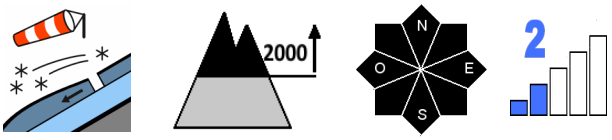 **Nieve húmeda** 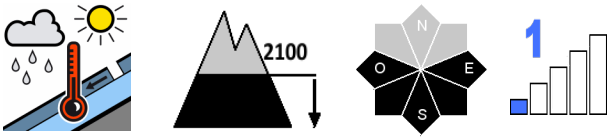	2026-02-20 Cotas bajas
Ter - Freser	2 **Limitado**	**Placas de viento** 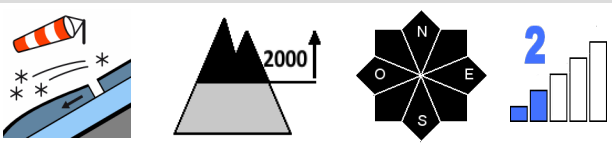 **Nieve húmeda**	2026-02-20 Cotas bajas
Vertiente norte Cadí - Moixeró	2 **Limitado**	**Placas de viento** 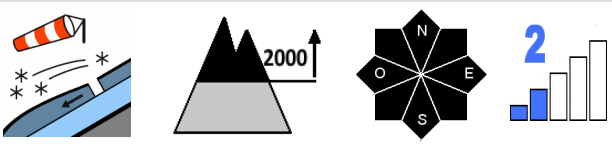 **Nieve húmeda**	2026-02-20 Cotas bajas
Prepirineo	2 **Limitado**	**Placas de viento** 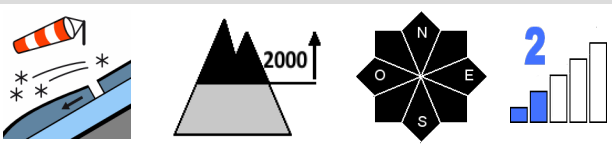 **Nieve húmeda**	2026-02-20 Cotas bajas

Estado del manto y observaciones recientes

Desde la tarde del miércoles se han venido produciendo precipitaciones en la cordillera, que han sido más frecuentes en el Arán y Pallaresa, donde se han acumulado en torno a 5-15 l/m2 en 48 horas, localmente más. En las demás zonas los registros han sido mucho más discretos, solo localmente en el entorno de la divisoria han rondado los 10 l/m2. Acompañando a las nevadas han soplado fuertes vientos del norte y noroeste, que han levantado ventiscas y redistribuido la nieve reciente. Por este motivo, aunque el grosor del manto se ha incrementado en algunas zonas durante el episodio, también se han producido deflaciones de

AEMET. Se autoriza la reproducción de su contenido citando la fuente.

algunos centímetros, sobre todo en la mitad oriental.

El manto es continuo desde cotas bajas, con espesores que en su mayoría se encuentran en máximos, muy por encima de lo que cabría esperar a estas alturas de la temporada. Por encima de unos 2200 metros se superan los 200 cm en muchas zonas de los macizos occidentales, y los 100-150 cm en los orientales.

En cotas medias y bajas el manto se ha humidificado en los últimos días, gracias a las lluvias y al ambiente más templado. En cotas altas la nieve se mantiene más seca y se han formado numerosas placas en muchas orientaciones, las más recientes en vertientes este y sur. Además, en las altas umbrías, todavía pueden persistir algunas capas débiles en el interior del manto.

Evolución del manto y peligro de aludes para el sábado, día 21

Problema de nieve húmeda. Problema de placas de viento en cotas altas.

En la madrugada del sábado podrán formarse costras de rehielo, que estabilizarían el manto a primeras horas, si bien estas se irán debilitando conforme transcurra la mañana, gracias a la abundante insolación y al acusado ascenso térmico previsto. Con estas condiciones serán frecuentes los aludes de nieve húmeda en cotas medias y bajas, con mayor probabilidad en las solanas, por lo general de tamaño pequeño (riesgo de caída) o mediano (capaz de enterrar a una persona), aunque no se descarta alguno de mayores dimensiones, sobre todo en el caso de que se produzcan deslizamientos basales.

En cotas altas existen placas de viento en muchas orientaciones, las más recientes en vertientes este y sur, que a pesar del calentamiento esperado todavía se mantendrán inestables, pudiendo colapsar ante una sobrecarga débil (paso de un solo esquiador), ocasionando aludes de dimensión 1 o 2, aunque si se implica parte del manto subyacente podrían alcanzar tamaño suficiente como para enterrar a un grupo de personas, siendo esto más probable en umbrías del Arán, especialmente en las zonas de poco espesor, donde todavía las capas débiles persistentes podrían ser reactivas.

Predicción meteorológica para el sábado, día 21

Poco nuboso o despejado con algunas nubes altas, así como algún banco aislado de nubes bajas a primeras horas. Temperaturas mínimas sin cambios o en ligero descenso. Máximas en ascenso, con frecuencia notable. Heladas débiles o moderadas en cotas altas, sin descartarlas en algún fondo de valle, que podrían ser localmente fuertes en el entorno de los tresmiles. Viento moderado del noroeste y norte en cotas altas, aflojando al final del día. En el resto soplará del norte al inicio, flojo con algún intervalo moderado, tendiendo a flojo de dirección variable por la mañana, pero fijándose la componente oeste a últimas horas.

Datos en la atmósfera libre:

Altitud de la isoterma de 0 ºC: 3000 m
Altitud de la isoterma de -10 ºC: 4500 m

Viento a 1500 m: VRB 10 km/h
Viento a 3000 m: NW 30 km/h

AEMET. Se autoriza la reproducción de su contenido citando la fuente.

Evolución para el domingo día 22

Las placas de viento tenderán a ganar estabilidad. El problema de nieve húmeda se intensificará.

Escala europea de peligro de aludes

Débil | Limitado | Notable | Fuerte | Muy Fuerte

Problemas de aludes

Nieve reciente | Placas de viento | Capas débiles persistentes | Nieve húmeda | Deslizamientos basales | Sin problema evidente

Nota1: Se recuerda que, siempre que haya nieve, la ausencia total de peligro no existe. Hay que tener presente que en circunstancias desfavorables, con aludes de tamaño 1 (alud pequeño o colada) y tamaño 2 (alud mediano), se pueden sufrir severos daños personales.

Nota2: Los BPA se elaboran en base a información meteorológica así como al estado del manto nivoso a través de sondeos puntuales. Se advierte a los usuarios de la variabilidad de esta información al extrapolarla a zonas extensas de montaña. Por ello, AEMET no se hace responsable de su uso para la toma de decisiones que conciernen a la seguridad personal, ni de los riesgos físicos o materiales de ellas derivadas.

AEMET. Se autoriza la reproducción de su contenido citando la fuente.