GOBIERNO DE ESPAÑA
VICEPRESIDENCIA TERCERA DEL GOBIERNO
MINISTERIO PARA LA TRANSICIÓN ECOLÓGICA Y EL RETO DEMOGRÁFICO

Boletín de información nivológica y de peligro de aludes

Pirineo Navarro y Aragonés

aemet Agencia Estatal de Meteorología

viernes, 20 de febrero de 2026

Pronóstico hasta las 24 horas del sábado, día 21 de febrero

(Válido fuera de pistas de esquí balizadas y abiertas)

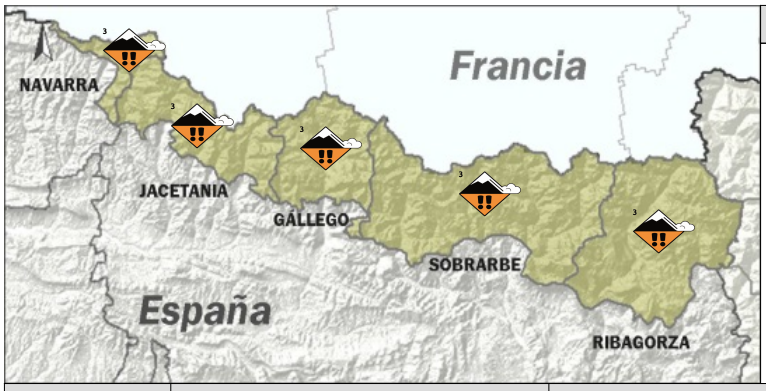

Problemas de aludes

Placas de viento

Nieve húmeda

Macizo	Peligro	Problemas de aludes, cota, orientación, tamaño	Innivación observada (m)
Navarra	3 — 3 / 2→3 — 2000 — Durante el día — **Notable**	**Placas de viento** — 2000 — N, E, S, O — 2 **Nieve húmeda** — 2100 — N, E, S, O — 2	2026-02-20 N / S — Cotas bajas
Jacetania	3 — 3 / 2→3 — 2000 — Durante el día — **Notable**	**Placas de viento** — 2000 — N, E, S, O — 2 **Nieve húmeda** — 2100 — N, E, S, O — 2	2026-02-20 N / S — Cotas bajas
Gállego	3 — 3 / 2→3 — 2000 — Durante el día — **Notable**	**Placas de viento** — 2000 — N, E, S, O — 2 **Nieve húmeda** — 2100 — N, E, S, O — 2	2026-02-20 N / S — Cotas bajas

AEMET. Se autoriza la reproducción de su contenido citando la fuente.

Boletín de información nivológica y de peligro de aludes

Pirineo Navarro y Aragonés

Sobrarbe	**Notable**	**Placas de viento** 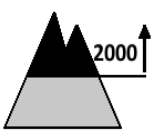  **Nieve húmeda** 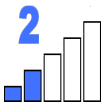	2026-02-20 Cotas bajas
Ribagorza	**Notable**	**Placas de viento** 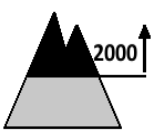 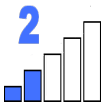 **Nieve húmeda** 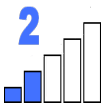	2026-02-20 Cotas bajas

Estado del manto y observaciones recientes

Desde la tarde del miércoles se han venido produciendo precipitaciones en la cordillera, que han sido más frecuentes y persistentes en los macizos occidentales, donde se han acumulado en torno a 20-40 l/m2 en 48 horas, localmente más. Conforme nos desplazamos hacia el este los registros van disminuyendo, de manera que en la Ribagorza solo han alcanzado unos 5-10 l/m2. Acompañando a las nevadas han soplado fuertes vientos del norte y noroeste, que han levantado ventiscas y redistribuido la nieve reciente. Por este motivo, aunque por lo general el grosor del manto se ha incrementado en unos 5-30 cm durante el episodio, dependiendo de macizos, también se han producido deflaciones de algunos centímetros en diversas zonas.

El manto es continuo desde fondos de valle y presenta espesores muy por encima de lo que sería habitual a estas alturas de la temporada. En torno a 2100 metros se superan fácilmente los 150-200 cm, aún más en ventisqueros, hoyas y otras zonas propensas a la acumulación.

En cotas medias y bajas el manto se ha humidificado en los últimos días, gracias a las lluvias y al ambiente más templado. En cotas altas la nieve está más seca y se han formado numerosas placas en muchas orientaciones, las más recientes en vertientes este y sur. Estas estructuras se mantienen muy frágiles, como así se detecta en el último test realizado ayer, jueves, a 2300 metros de altitud y orientación sureste, donde se produjo y se propagó la fractura en el primer golpe. Además, en las altas umbrías, todavía pueden persistir algunas capas débiles en el interior del manto, que todavía podrían ser reactivas, especialmente en zonas de poco grosor.

En las últimas 24 horas se han reportado varios aludes pequeños, raramente medianos, coladas o de placa friable, con distintas altitudes de salida que van desde 1500 hasta 2500 metros, en su mayoría en orientación sur y sureste, y también algunos disparos positivos.

AEMET. Se autoriza la reproducción de su contenido citando la fuente.

Evolución del manto y peligro de aludes para el sábado, día 21

Problema de nieve húmeda. Problema de placas de viento en cotas altas.

En la madrugada del sábado podrán formarse costras de rehielo, que estabilizarían el manto a primeras horas, si bien estas se irán debilitando conforme transcurra la mañana, gracias a la abundante insolación y al acusado ascenso térmico previsto. Con estas condiciones serán frecuentes los aludes de nieve húmeda en cotas medias y bajas, con mayor probabilidad en las solanas, por lo general de tamaño pequeño (riesgo de caída) o mediano (capaz de enterrar a una persona), aunque no se descarta alguno de mayores dimensiones, sobre todo en el caso de que se produzcan deslizamientos basales.

En cotas altas existen placas de viento en muchas orientaciones, las más recientes en vertientes este y sur, que a pesar del calentamiento esperado todavía se mantendrán inestables, pudiendo colapsar ante una sobrecarga débil (paso de un solo esquiador), ocasionando aludes de dimensión 1 o 2, aunque si se implica parte del manto subyacente podrían alcanzar tamaño suficiente como para enterrar a un grupo de personas, siendo esto más probable en umbrías, especialmente en las zonas de poco espesor, donde todavía las capas débiles persistentes pueden ser reactivas.

Predicción meteorológica para el sábado, día 21

Pirineo navarro:

Poco nuboso o despejado con intervalos de nubes altas, así como algunos bancos de nubes bajas a primeras horas. Temperaturas mínimas sin cambios o en ligero descenso. Máximas en ascenso, con frecuencia notable. Heladas débiles en cotas altas, sin descartarlas en algún fondo de valle. Viento de componentes norte y oeste en cotas altas, flojo o moderado. En el resto soplará moderado del norte al inicio, tendiendo a flojo de dirección variable.

Pirineo aragonés:

Poco nuboso o despejado con intervalos de nubes altas, así como algún banco aislado de nubes bajas a primeras horas. Temperaturas mínimas sin cambios o en ligero descenso. Máximas en ascenso, localmente notable en Jacetania y resto de la divisoria. Heladas débiles o moderadas en cotas altas, sin descartarlas en algún fondo de valle, que podrían ser localmente fuertes en el entorno de los tresmiles. Viento del noroeste y norte en cotas altas, flojo o moderado. En el resto soplará flojo de dirección variable, tendiendo a fijarse la componente oeste al final del día.

Datos en la atmósfera libre:

Altitud de la isoterma de 0 ºC: 3100 m
Altitud de la isoterma de -10 ºC: 4600 m

Viento a 1500 m: SE 10 km/h
Viento a 3000 m: NW 10 km/h

AEMET. Se autoriza la reproducción de su contenido citando la fuente.

Evolución para el domingo día 22

Las placas de viento tenderán a ganar estabilidad. El problema de nieve húmeda se intensificará.

(Información elaborada a partir de los datos recibidos de los refugios de Linza, Lizara, Panticosa, Bachimaña, Góriz, Pineta, Estós, Angel Orús, La Renclusa, Cap de Llauset y Belagua, de las estaciones de esquí de Candanchú, Astún, Formigal y Panticosa (lagos), de la estación de esquí de fondo de Llanos del Hospital y de Ordesa Pradera)

Escala europea de peligro de aludes

Débil | Limitado | Notable | Fuerte | Muy Fuerte

Problemas de aludes

Nieve reciente | Placas de viento | Capas débiles persistentes | Nieve húmeda | Deslizamientos basales | Sin problema evidente

Nota1: Se recuerda que, siempre que haya nieve, la ausencia total de peligro no existe. Hay que tener presente que en circunstancias desfavorables, con aludes de tamaño 1 (alud pequeño o colada) y tamaño 2 (alud mediano), se pueden sufrir severos daños personales.

Nota2: Los BPA se elaboran en base a información meteorológica así como al estado del manto nivoso a través de sondeos puntuales. Se advierte a los usuarios de la variabilidad de esta información al extrapolarla a zonas extensas de montaña. Por ello, AEMET no se hace responsable de su uso para la toma de decisiones que conciernen a la seguridad personal, ni de los riesgos físicos o materiales de ellas derivadas.

AEMET. Se autoriza la reproducción de su contenido citando la fuente.