aineva.it

Samstag 21.02.2026

Veröffentlicht am 20.02.2026 um 17:00

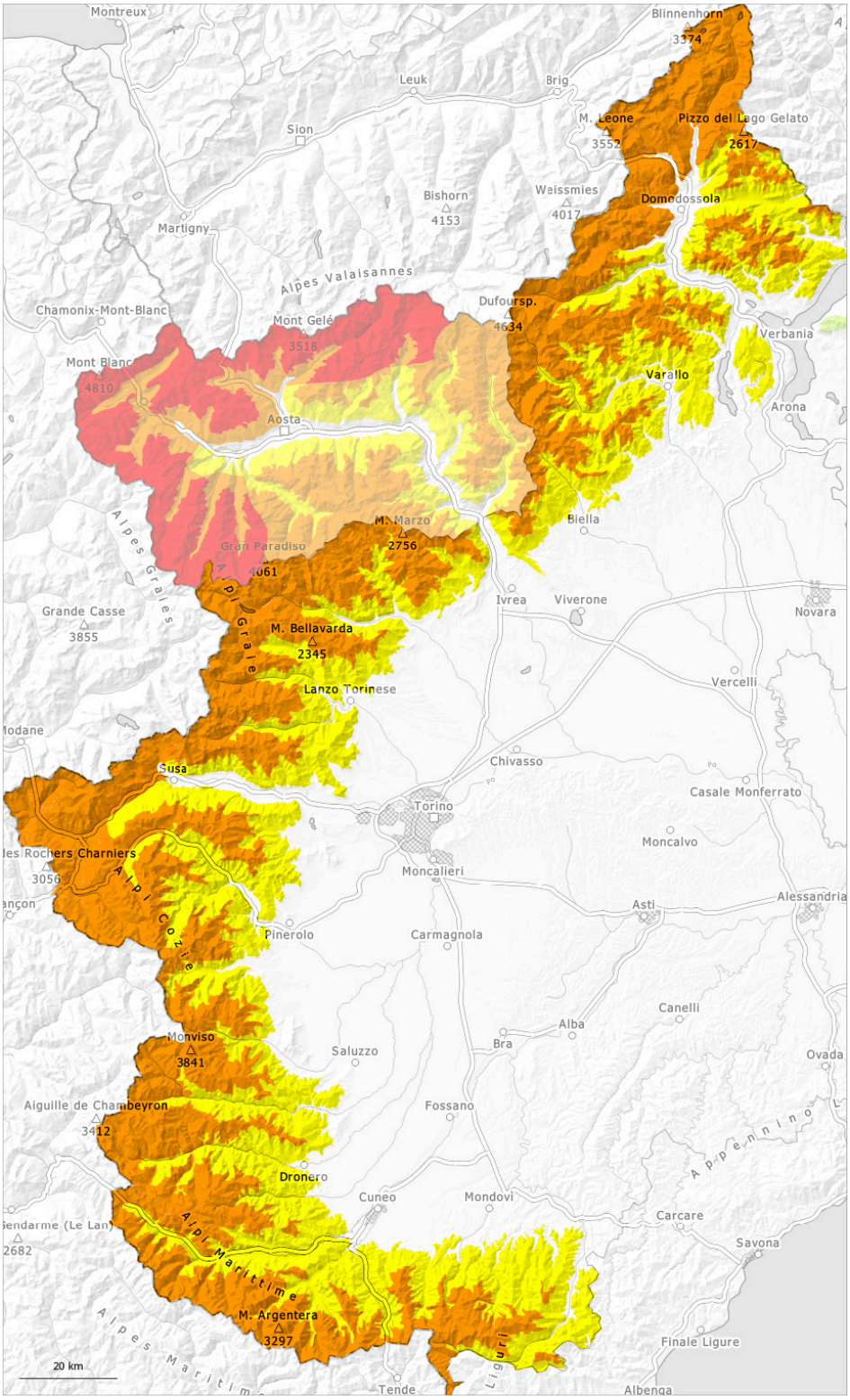

1	2	3	4	5
gering	mäßig	erheblich	groß	sehr groß

Gefahrenstufe 3 - Erheblich

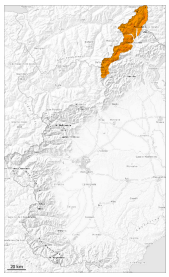

Tendenz: Lawinengefahr steigt
am Sonntag, den 22.02.2026

Triebschnee

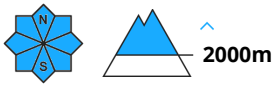

Nassschnee

Triebschnee ist die Hauptgefahr. Allmählicher Anstieg der Gefahr von trockenen und feuchten Lawinen mit der tageszeitlichen Erwärmung und der Sonneneinstrahlung.

Am Samstag fällt lokal etwas Schnee. Mit Schneefall und teils stürmischem Nordwestwind entstanden in den letzten Tagen frische Triebschneeansammlungen. Dies vor allem in den Föhngebieten oberhalb der Waldgrenze sowie in Rinnen, Mulden und hinter Geländekanten.
Die störanfälligen Triebschneeansammlungen können schon von einzelnen Wintersportlern leicht ausgelöst werden.

Tagesverlauf: An Triebschneehängen und aus noch nicht entladenen Einzugsgebieten sind mit der Erwärmung mittlere und große trockene und feuchte Lawinen möglich.

Schneedecke

Gefahrenmuster gm.6: lockerer schnee und wind | gm.10: frühjahrssituation

Seit Montag fielen gebietsweise verbreitet 40 bis 80 cm Schnee, lokal auch mehr.
Der teilweise stürmische Wind hat viel Schnee verfrachtet.
In Gipfellagen liegen je nach Windeinfluss sehr unterschiedliche Schneehöhen.
In der Altschneedecke sind vor allem an steilen Nordwest-, Nord- und Osthängen störanfällige Schwachschichten vorhanden.
Verschiedene Triebschneeschichten liegen stellenweise auf grobkörnigem Altschnee.

Tendenz

Es ist mild. Mittag und Nachmittag: Markanter Anstieg der Gefahr von trockenen und feuchten Lawinen mit der tageszeitlichen Erwärmung und der Sonneneinstrahlung.

Gefahrenstufe 3 - Erheblich

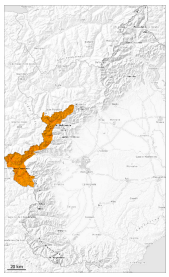

Tendenz: Lawinengefahr steigt
am Sonntag, den 22.02.2026

Triebschnee

2200m

Nassschnee

2300m

An Triebschneehängen weiterhin gefährliche Lawinensituation. Die Gefahr von trockenen und feuchten Lawinen steigt im Tagesverlauf an.

Mit Schneefall und teils stürmischem Nordwestwind entstanden in den letzten Tagen frische Triebschneeansammlungen. Dies vor allem in den Föhngebieten oberhalb der Waldgrenze und in Kammlagen, Rinnen und Mulden.
Die störanfälligen Triebschneeansammlungen können schon von einzelnen Wintersportlern ausgelöst werden.
Entlang der Grenze zu Frankreich sind die Gefahrenstellen weiter verbreitet und die Gefahr höher.

An Triebschneehängen und aus noch nicht entladenen Einzugsgebieten sind mit der tageszeitlichen Erwärmung und der Sonneneinstrahlung mittlere und mehrfach große Staublawinen möglich.

Schneedecke

Gefahrenmuster gm.6: lockerer schnee und wind | gm.10: frühjahrssituation

Seit Montag fielen gebietsweise oberhalb von rund 1800 m 70 bis 120 cm Schnee, lokal auch mehr. Dort liegt für die Jahreszeit viel Schnee.
Der teilweise stürmische Wind hat viel Schnee verfrachtet.
In Gipfellagen liegen je nach Windeinfluss sehr unterschiedliche Schneehöhen.
Der Neuschnee der letzten Woche liegt oberhalb der Waldgrenze teilweise auf Oberflächenreif.
Verschiedene Triebschneeschichten liegen stellenweise auf einer weichen Altschneeoberfläche.
Die durchgeführten ECTs und Beobachtungen im Gelände bestätigten den schwachen Schneedeckenaufbau.

Tendenz

Es ist mild. Mittag und Nachmittag: Markanter Anstieg der Gefahr von trockenen und feuchten Lawinen mit der tageszeitlichen Erwärmung und der Sonneneinstrahlung.

Gefahrenstufe 3 - Erheblich

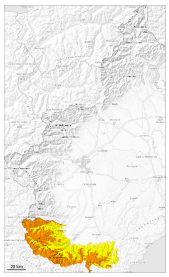

Tendenz: Lawinengefahr steigt
am Sonntag, den 22.02.2026

Triebschnee

Nassschnee

Vorsicht vor Triebschnee. Mit der Sonneneinstrahlung steigt die Auslösebereitschaft von trockenen und feuchten Lawinen vor allem an Sonnenhängen an.

Mit starkem Nordwestwind entstanden in den letzten Tagen frische Triebschneeansammlungen.
Vor allem mittlere und hohe Lagen sowie in windgeschützten Lagen: Weiche Triebschneeansammlungen können im Bereich der Waldgrenze von einzelnen Wintersportlern ausgelöst werden. Die Triebschneeansammlungen sind gut erkennbar.
Vor allem steile Sonnenhänge und Felswandfüße: Mit der Erwärmung sind mittlere und vereinzelt große trockene und feuchte Lawinen möglich.

Schneedecke

Gefahrenmuster gm.6: lockerer schnee und wind | gm.10: frühjahrssituation

Am Donnerstag fielen in allen Höhenlagen verbreitet 15 bis 25 cm Schnee. Der starke Wind hat Neu- und Altschnee verfrachtet.
V.a. in Gipfellagen liegen je nach Windeinfluss sehr unterschiedliche Schneehöhen. Schattenhänge: Die Schneedecke ist trocken, mit einer lockeren Oberfläche.
Sonnenhänge: Die Sonneneinstrahlung führt im Tagesverlauf unterhalb von rund 2200 m zu einer zunehmenden Anfeuchtung der Schneedecke.

Tendenz

Morgen: Schneebrettlawinen sind die Hauptgefahr.
An Sonnenhängen und im felsdurchsetzten Steilgelände steigt die Auslösebereitschaft von trockenen und nassen Lawinen im Tagesverlauf an.

Gefahrenstufe 3 - Erheblich

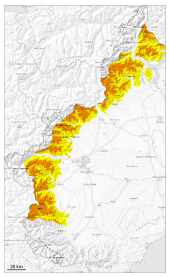

Tendenz: Lawinengefahr bleibt gleich
am Sonntag, den 22.02.2026

Triebschnee

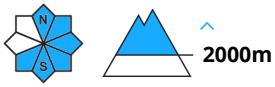

Nassschnee

Schneebrettlawinen sind die Hauptgefahr. Allmählicher Anstieg der Gefahr von trockenen und feuchten Lawinen mit der tageszeitlichen Erwärmung und der Sonneneinstrahlung.

Der teilweise starke Wind hat den Neuschnee intensiv verfrachtet. Mit starkem Nordwestwind entstanden in den letzten Tagen frische Triebschneeansammlungen.
Vor allem mittlere und hohe Lagen sowie in windgeschützten Lagen: Weiche Triebschneeansammlungen können oberhalb der Waldgrenze von einzelnen Wintersportlern ausgelöst werden. Die Triebschneeansammlungen sind gut erkennbar.
Vor allem steile Sonnenhänge und Felswandfüße: Mit der Erwärmung sind mittlere und vereinzelt große trockene und feuchte Lawinen möglich.

Schneedecke

Gefahrenmuster gm.6: lockerer schnee und wind

Am Donnerstag fielen in allen Höhenlagen verbreitet 15 bis 25 cm Schnee. In diesen Gebieten oberhalb von rund 1200 m liegt für die Jahreszeit viel Schnee.
Der starke Wind hat Neu- und Altschnee verfrachtet.
In Gipfellagen liegen je nach Windeinfluss sehr unterschiedliche Schneehöhen.
Schattenhänge: Die Schneedecke ist trocken, mit einer lockeren Oberfläche.
Sonnenhänge unterhalb von rund 2200 m: Die Sonneneinstrahlung führt im Tagesverlauf zu einer zunehmenden Anfeuchtung der Schneedecke.

Tendenz

Es ist mild. Mittag und Nachmittag: Allmählicher Anstieg der Gefahr von trockenen und feuchten Lawinen mit der tageszeitlichen Erwärmung und der Sonneneinstrahlung.