# Sabato 21.02.2026

Pubblicato il 20.02.2026 alle ore 17:00

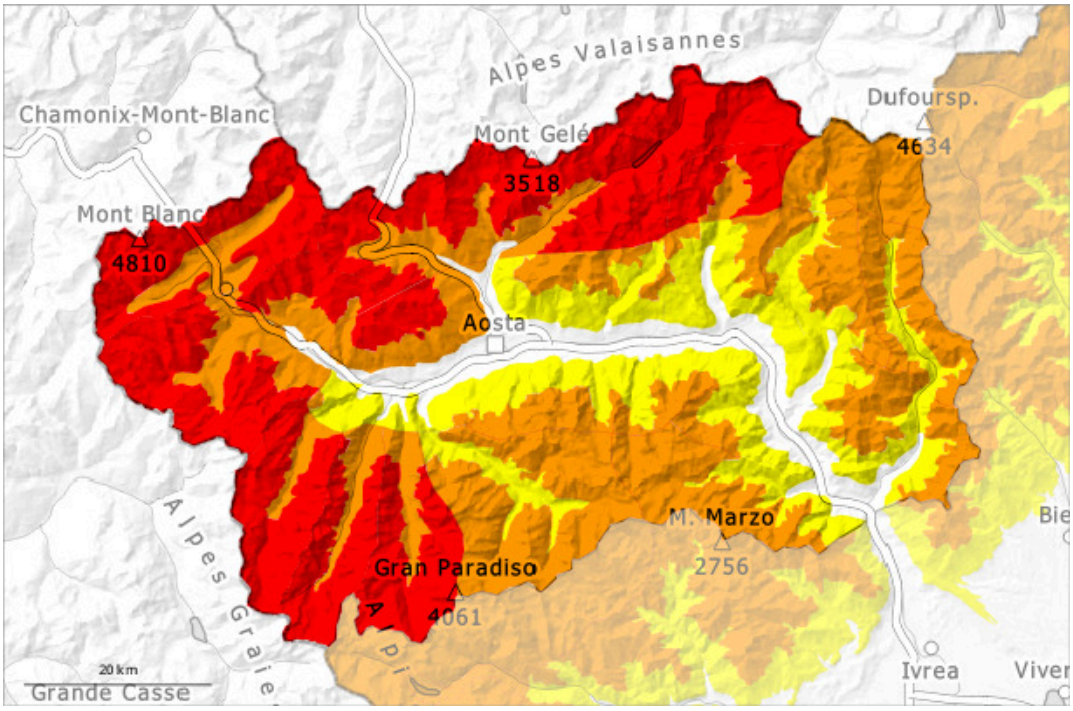


| 1 | 2 | 3 | 4 | 5 |
|---|---|---|---|---|
| debole | moderato | marcato | forte | molto forte |

## Grado di pericolo 4 - Forte

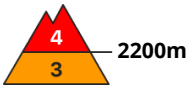


**Tendenza: pericolo valanghe stabile**
per Domenica il 22.02.2026

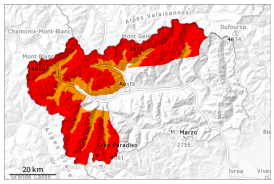

Lastrone da vento

2200m

Neve bagnata

2600m

Neve ventata recente e meno recente sono la principale fonte di pericolo. Inoltre il pericolo di valanghe umide e bagnate aumenterà a partire dal mattino. Per le escursioni e le discese fuori pista, le condizioni sono pericolose. È necessaria una prudente scelta dell'itinerario.

Con il favonio da forte a tempestoso proveniente da nord, negli ultimi giorni si sono formati nuovi accumuli di neve ventata. Nel corso della giornata gli accumuli di neve ventata, già grandi, cresceranno ulteriormente. I bacini di alimentazione in quota verranno di nuovo caricati a causa del vento. Qui sono ancora possibili valanghe asciutte spontanee di medie e di grandi dimensioni.
Lungo i percorsi abituali le valanghe possono ancora raggiungere dimensioni piuttosto grandi.
Con lo zero termico fino a 2600 associato al favonio e all'irradiazione solare, già dalla mattinata sono previste numerose valanghe umide e bagnate, a livello isolato anche di grandi dimensioni.
Un singolo appassionato di sport invernali può facilmente provocare il distacco di valanghe, anche di grandi dimensioni. Attenzione sui pendii ripidi e nelle conche, nei canaloni e dietro ai cambi di pendenza.

## Manto nevoso

**Situazione tipo** st.6: neve a debole coesione e vento | st.1: strato debole persistente basale

Durante la notte è caduta poca neve. Sono caduti diffusamente da 5 a 10 cm di neve al di sopra dei 1800 m circa.
Da domenica sono caduti diffusamente da 60 a 100 cm di neve al di sopra dei 1800 m circa, localmente anche di più.
In molte regioni, fino a sabato il vento sarà forte.
Il manto nevoso ha una stratificazione sfavorevole.
Nelle zone in prossimità delle creste e dei passi l'innevamento è estremamente variabile a seconda dell'azione del vento.
Nell'ultima settimana sono cadute alcune valanghe nubiformi di grandi dimensioni e, a livello isolato, di dimensioni molto grandi. Negli ultimi due giorni sono state distaccate in seguito al passaggio di persone isolate valanghe di neve a lastroni di medie e, a livello isolato, di grandi dimensioni.

## Tendenza

Il pericolo di valanghe umide e bagnate aumenterà nel corso della giornata.

## Grado di pericolo 3 - Marcato

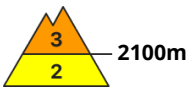


**Tendenza: pericolo valanghe stabile**
per Domenica il 22.02.2026

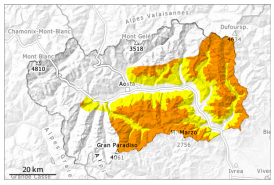

Lastrone da vento

Strati deboli persistenti

### La principale fonte di pericolo è costituita da valanghe di neve a lastroni. A partire dalla mattinata saranno possibili valanghe umide e bagnate.

Con il favonio da forte a tempestoso proveniente da nord, negli ultimi giorni si sono formati nuovi accumuli di neve ventata. Nel corso della giornata gli accumuli di neve ventata cresceranno ulteriormente.
Attenzione sui pendii molto ripidi e nelle conche, nei canaloni e dietro ai cambi di pendenza. Le valanghe possono distaccarsi già in seguito al passaggio di un singolo appassionato di sport invernali.
Gli strati deboli presenti nella neve vecchia richiedono attenzione. In alcuni punti le valanghe possono subire un distacco nella neve vecchia e raggiungere dimensioni piuttosto grandi.
Sono possibili distacchi a distanza. I rumori di "whum" e la formazione di fessure quando si calpesta la coltre di neve sono campanelli di allarme.
Con lo zero termico fino a 2600 associato al favonio e all'irradiazione solare, già dalla mattinata sono previste valanghe umide e bagnate, a livello isolato anche di grandi dimensioni.

## Manto nevoso

**Situazione tipo** st.6: neve a debole coesione e vento | st.1: strato debole persistente basale

Da domenica sono caduti diffusamente da 20 a 50 cm di neve al di sopra dei 1600 m circa. Fino a sabato il vento sarà forte.
Nelle zone in prossimità delle creste e dei passi l'innevamento è estremamente variabile a seconda dell'azione del vento. Il manto nevoso ha una stratificazione sfavorevole.
Specialmente sui pendii esposti a ovest, nord ed est, all'interno del manto di neve vecchia si trovano strati fragili a cristalli angolari.
Negli ultimi giorni sono cadute alcune valanghe asciutte spontanee di dimensioni medio-grandi.

## Tendenza

Il pericolo di valanghe umide e bagnate aumenterà nel corso della giornata.