Sabato 21.02.2026

Pubblicato il 20.02.2026 alle ore 17:00

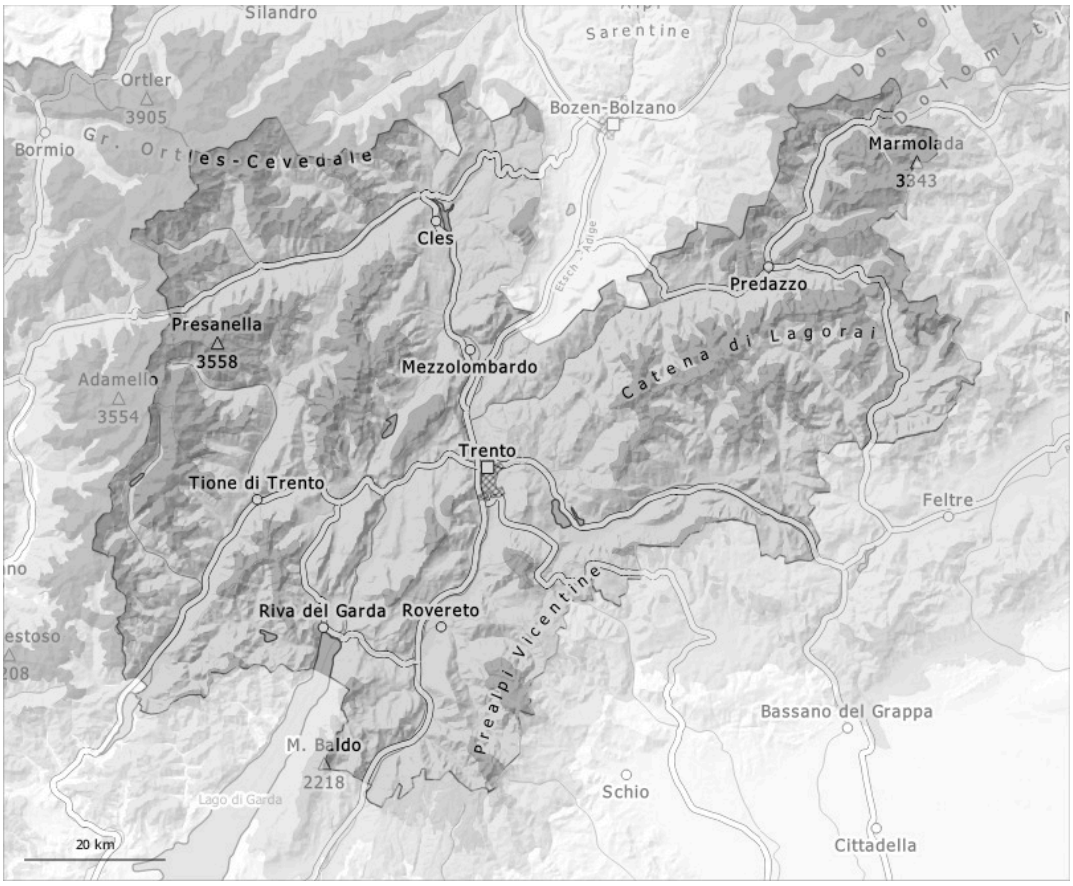

1	2	3	4	5
debole	moderato	marcato	forte	molto forte

Grado di pericolo 3 - Marcato

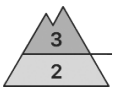

Limite del bosco

Tendenza: pericolo valanghe stabile
per Domenica il 22.02.2026

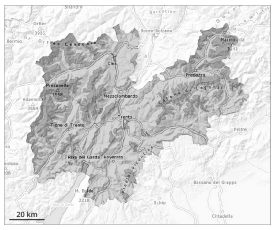

Lastrone da vento

Limite del bosco

Strati deboli persistenti

Limite del bosco

Neve bagnata

La neve fresca e la neve ventata rappresentano la principale fonte di pericolo. Al di fuori delle piste assicurate, la situazione valanghiva è in molti punti molto delicata.

Il vento a tratti tempestoso ha causato il trasporto di molta neve. Al di sopra del limite del bosco si sono formati accumuli di neve ventata instabili, soprattutto nelle zone in prossimità delle creste e dei passi a tutte le altitudini, come pure nelle conche, nei canaloni e dietro ai cambi di pendenza in quota.
Sui pendii soleggiati molto ripidi si prevedono valanghe spontanee di medie dimensioni. In alcuni punti le valanghe possono trascinare l'intero manto nevoso e raggiungere grandi dimensioni. Le valanghe di neve asciutta sono per lo più di dimensioni medie e distaccabili da un singolo appassionato di sport invernali. Sono possibili distacchi a distanza. I rumori di "whum" e la formazione di fessure quando si calpesta la coltre di neve sono campanelli di allarme che rimandano a questo pericolo.
I punti pericolosi sono frequenti e difficilmente individuabili anche da parte dell'escursionista esperto. Le escursioni richiedono un'attenta scelta dell'itinerario.

Manto nevoso

Situazione tipo st.6: neve a debole coesione e vento | st.1: strato debole persistente basale

In molte aree da giovedì sono caduti diffusamente da 20 a 40 cm di neve, localmente sino a 50 cm. La neve fresca e la neve ventata ricoprono un debole manto di neve vecchia soprattutto sui pendii ripidi ombreggiati al di sopra del limite del bosco. Nella parte basale del manto di neve vecchia si trovano pronunciati strati fragili. Le condizioni meteorologiche favoriranno un graduale indebolimento del manto nevoso sui pendii soleggiati.
Il manto nevoso rimane instabile in molti punti, soprattutto nelle zone in prossimità delle creste e dei passi

a tutte le altitudini, come pure nelle conche, nei canaloni e dietro ai cambi di pendenza in quota.

Tendenza

Il manto nevoso rimane instabile in molti punti. Il pericolo di valanghe rimarrà invariato.