ICGC Institut Cartogràfic i Geològic de Catalunya

Servei Meteorològic de Catalunya meteo.cat

Boletín de peligro de aludes para el Pirineo de Catalunya
Del 20/02/2026 al 21/02/2026

(Válido fuera pistas de esquí y zonas no controladas)

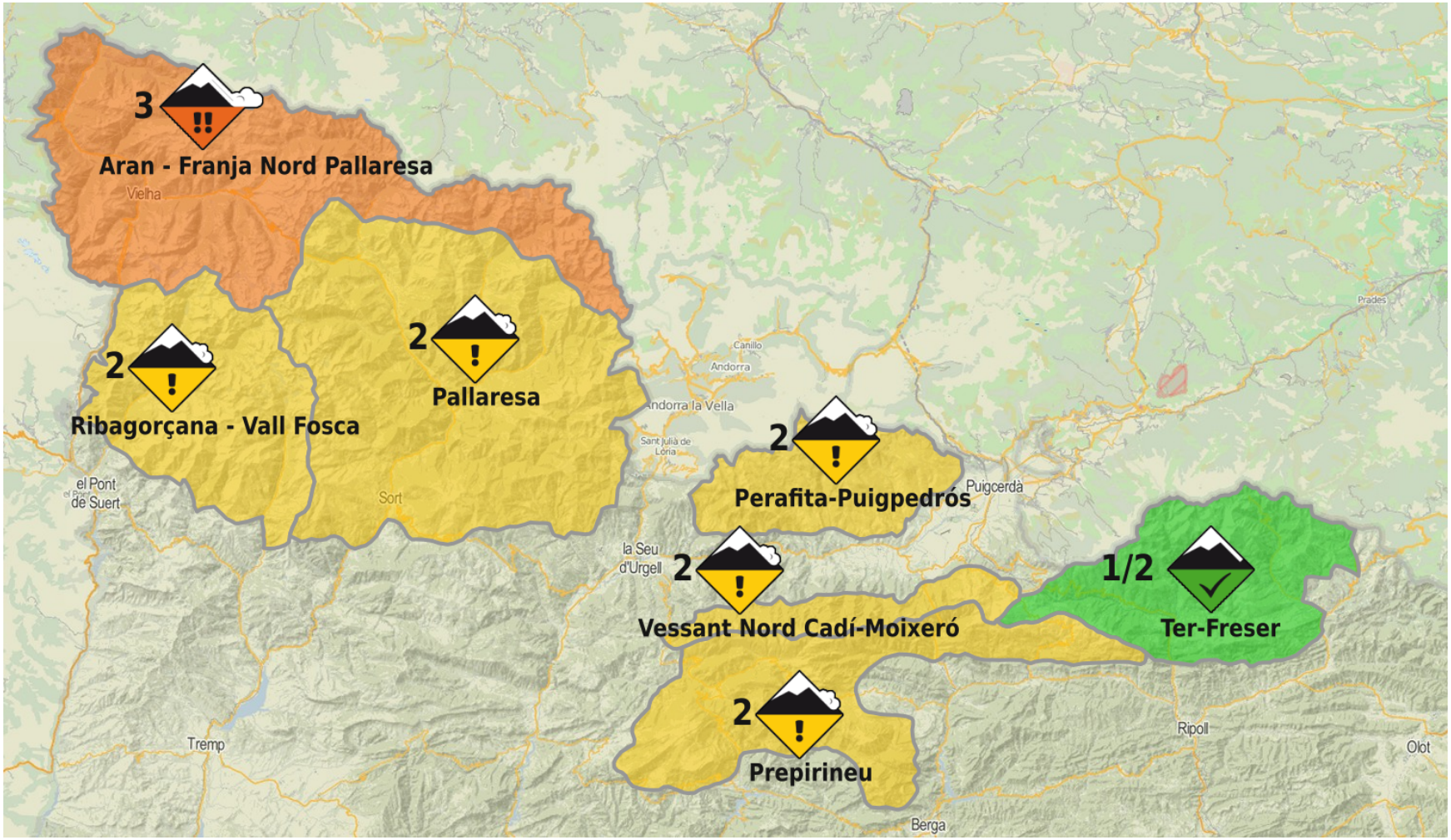

5 MUY FUERTE	4 FUERTE	3 NOTABLE	2 LIMITADO	1 DÉBIL

ICGC Institut Cartogràfic i Geològic de Catalunya

Servei Meteorològic de Catalunya meteo.cat

Boletín de peligro de aludes Aran - Franja Nord Pallaresa Del 20/02/2026 al 21/02/2026

(Válido fuera pistas de esquí y zonas no controladas)

NOTABLE (3)

Situación primaria

Nieve venteada

Distribución

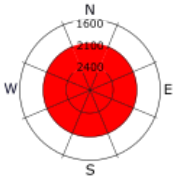

Tamaño

Origen

Tendencia

Situación secundaria

Nieve húmeda

Distribución

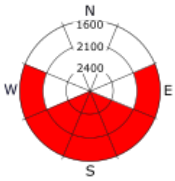

Tamaño

Origen

Tendencia

Estado del manto nivoso

El último episodio de nieve y viento ha formado nuevas placas, sobre todo en orientaciones E y S, por encima del límite del bosque. Se encuentran sobre todo bajo collados y crestas y cubetas resguardadas. Estas placas son reactivas y sensibles, pudiendo ceder tanto por sobrecarga débil como a veces de forma natural. Por lo general, pueden alcanzar tamaño medio, pero localmente alguna podría llegar a tamaño grande.
A medida que avance el día, en las horas centrales del sábado, con el aumento repentino de la temperatura y la insolación intensa, el manto se humedecerá, sobre todo en orientaciones S. Se espera actividad de aludes de nieve húmeda y caída de bolas, más frecuentes en vertientes de fuerte pendiente y bajo resaltes rocosos. Los aludes de nieve húmeda podrán ser de tamaño pequeño o medio. Es posible también actividad de deslizamientos basales en vertientes propicias más soleadas.

Distribución del manto nivoso

Los espesores a unos 2.200 m son superiores a los normales y rondan los 120-140 cm en el norte de Arán y los 160-200 cm en la Franja Norte Pallaresa y en el sur de Aran.

Tendencia para las próximas 48-72h

Las placas tenderán a estabilizarse progresivamente y persistirán los problemas de nieve húmeda. Peligro: en leve DESCENSO.

El próximo boletín será emitido el día 2026-02-21

5 MUY FUERTE	4 FUERTE	3 NOTABLE	2 LIMITADO	1 DÉBIL

EAWS EUROPEAN AVALANCHE WARNING SERVICES

ICGC Institut Cartogràfic i Geològic de Catalunya

Servei Meteorològic de Catalunya meteo.cat

Boletín de peligro de aludes Ribagorçana - Vall Fosca Del 20/02/2026 al 21/02/2026

(Válido fuera pistas de esquí y zonas no controladas)

LIMITADO (2)

Situación primaria

Nieve venteada

Distribución

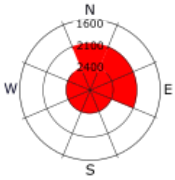

Tamaño

Origen

Tendencia

Situación secundaria

Nieve húmeda

Distribución

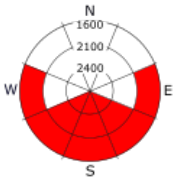

Tamaño

Origen

Tendencia

Estado del manto nivoso

El viento fuerte de los últimos días con nevadas poco abundantes ha formado nuevas placas de viento, sobre todo por encima del límite de bosque, más frecuentes en E y S pero también presentes en umbrías por el viento cruzado. Estas placas, por lo general de poco espesor, pueden mostrarse muy sensibles por sobrecargas débiles y romper provocando aludes pequeños o hasta tamaño medio más puntualmente.

El sábado, con el acusado aumento térmico previsto e intensa insolación, el manto se humedecerá superficialmente, sobre todo en orientaciones S, durante las horas centrales del día. Con estas condiciones, se espera actividad de aludes de nieve húmeda y caída de bolas, más frecuentes en laderas S de fuerte pendiente y bajo resaltes rocosos. Los aludes serán por lo general de tamaño pequeño, y más localmente hasta tamaño medio.

Distribución del manto nivoso

Hay nieve en el suelo a 1.500 m. El manto es esquiable por encima de unos 1500-1600 m. Los grosores alcanzan los 130-160 cm. Estos valores son muy superiores a los normales en la época.

Tendencia para las próximas 48-72h

Las placas tenderán a estabilizarse progresivamente y persistirán los problemas de nieve húmeda. Peligro: en leve DESCENSO.

El próximo boletín será emitido el día 2026-02-21

5 MUY FUERTE	4 FUERTE	3 NOTABLE	2 LIMITADO	1 DÉBIL

EAWS EUROPEAN AVALANCHE WARNING SERVICES

ICGC Institut Cartogràfic i Geològic de Catalunya

Servei Meteorològic de Catalunya

Boletín de peligro de aludes Pallaresa
Del 20/02/2026 al 21/02/2026

(Válido fuera pistas de esquí y zonas no controladas)

LIMITADO (2)

Situación primaria

Nieve venteada

Distribución

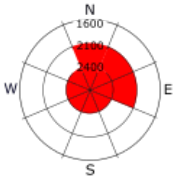

Tamaño

Origen

Tendencia

Situación secundaria

Nieve húmeda

Distribución

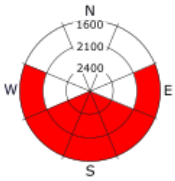

Tamaño

Origen

Tendencia

Estado del manto nivoso

El viento fuerte de los últimos días con nevadas poco abundantes ha formado nuevas placas de viento, sobre todo por encima del límite de bosque, más frecuentes en E y S pero también presentes en umbrías por el viento cruzado. Estas placas, por lo general de poco espesor, pueden mostrarse muy sensibles por sobrecargas débiles y romper provocando aludes pequeños o hasta tamaño medio más puntualmente.

El sábado, con el acusado aumento térmico previsto e intensa insolación, el manto se humedecerá superficialmente, sobre todo en orientaciones S, durante las horas centrales del día. Con estas condiciones, se espera actividad de aludes de nieve húmeda y caída de bolas, más frecuentes en laderas S de fuerte pendiente y bajo resaltes rocosos. Los aludes serán por lo general de tamaño pequeño, y más localmente hasta tamaño medio.

Distribución del manto nivoso

Hay nieve en el suelo a 1.500 m. El manto es esquiable por encima de unos 1500-1600 m. Los grosores alcanzan los 130-160 cm. Estos valores son muy superiores a los normales en la época.

Tendencia para las próximas 48-72h

Las placas tenderán a estabilizarse progresivamente y persistirán los problemas de nieve húmeda. Peligro: en leve DESCENSO.

El próximo boletín será emitido el día 2026-02-21

5 MUY FUERTE	4 FUERTE	3 NOTABLE	2 LIMITADO	1 DÉBIL

EAWS EUROPEAN AVALANCHE WARNING SERVICES

ICGC Institut Cartogràfic i Geològic de Catalunya

Servei Meteorològic de Catalunya

Boletín de peligro de aludes Perafita-Puigpedrós Del 20/02/2026 al 21/02/2026

(Válido fuera pistas de esquí y zonas no controladas)

LIMITADO (2)

Situación primaria

Nieve venteada

Distribución

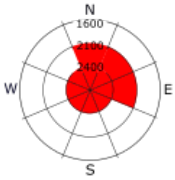

Tamaño

Origen

Tendencia

Situación secundaria

Nieve húmeda

Distribución

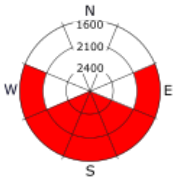

Tamaño

Origen

Tendencia

Estado del manto nivoso

La nevada de los últimos días acompañada del viento fuerte ha formado nuevas placas de viento, sobre todo por encima del límite de bosque, y principalmente en orientaciones E y S. Estas placas son en general de poco espesor y descansan sobre un manto encostrado o endurecido, pero pueden mostrarse sensibles por sobrecargas débiles y romper provocando aludes pequeños o de hasta tamaño medio.

El sábado, con el acusado aumento térmico previsto e intensa insolación, el manto de las vertientes más propicias, de fuerte pendiente y orientadas a S, se humedecerá superficialmente durante las horas centrales del día. Este humedecimiento podrá provocar purgas de nieve húmeda y caída de bolas, más frecuentes bajo resaltes rocosos. Los aludes serán por lo general de tamaño pequeño, y muy localmente hasta tamaño medio.

Distribución del manto nivoso

Hay nieve en el suelo por encima de 1.400-1500 m. Sin embargo, el manto es esquiable por encima de 1.500-1.600 m. Los grosores alcanzan los 130-150 cm a 2.200 m. Son grosores muy por encima de los habituales por la época.

Tendencia para las próximas 48-72h

Las placas tenderán a estabilizarse progresivamente y persistirán los problemas de nieve húmeda. Peligro: en leve DESCENSO.

El próximo boletín será emitido el día 2026-02-21

5 MUY FUERTE	4 FUERTE	3 NOTABLE	2 LIMITADO	1 DÉBIL

EAWS EUROPEAN AVALANCHE WARNING SERVICES

ICGC Institut Cartogràfic i Geològic de Catalunya

Servei Meteorològic de Catalunya meteo.cat

Boletín de peligro de aludes
Vessant Nord Cadí-Moixeró
Del 20/02/2026 al 21/02/2026

(Válido fuera pistas de esquí y zonas no controladas)

LIMITADO (2)

Situación primaria

Nieve venteada

Distribución

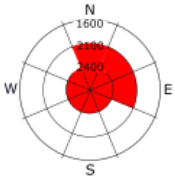

Tamaño

Origen

Tendencia

Situación secundaria

Nieve húmeda

Distribución

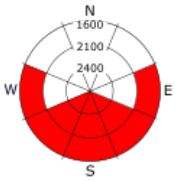

Tamaño

Origen

Tendencia

Estado del manto nivoso

El último episodio de viento fuerte y nevadas débiles ha transportado la nieve y ha formado nuevas placas, sobre todo en cota alta, bajo collados y cordales y en la parte alta de las canales. Estas placas, aunque progresivamente irán perdiendo reactividad, pueden ser todavía sensibles a sobrecargas débiles y provocar aludes de pequeño tamaño en general, o localmente de tamaño medio.

El sábado, con el fuerte aumento térmico y la intensa insolación, el manto se humedecerá, sobre todo en orientaciones S, y en menor medida W y E de cota baja, durante las horas centrales del día. Es probable actividad de aludes de nieve húmeda y caída de bolas, restringidas a las horas centrales del día y mayoritariamente a vertientes S de fuerte pendiente y bajo resaltes rocosos. Los aludes serán por lo general de tamaño pequeño, o puntualmente hasta tamaño medio.

Distribución del manto nivoso

Hay manto continuo por encima de unos 1.600 m y esquiable por encima de unos 1.700 m. Los espesores están alrededor de 150-170 cm en cotas medias. Estos valores son muy excedentarios para la época del año.

Tendencia para las próximas 48-72h

Las placas tenderán a estabilizarse progresivamente y persistirán los problemas de nieve húmeda. Peligro: en leve DESCENSO.

El próximo boletín será emitido el día 2026-02-21

5 MUY FUERTE	4 FUERTE	3 NOTABLE	2 LIMITADO	1 DÉBIL

EAWS EUROPEAN AVALANCHE WARNING SERVICES

ICGC Institut Cartogràfic i Geològic de Catalunya

Servei Meteorològic de Catalunya

Boletín de peligro de aludes Prepirineu
Del 20/02/2026 al 21/02/2026

(Válido fuera pistas de esquí y zonas no controladas)

LIMITADO (2)

Situación primaria

Nieve venteada

Distribución

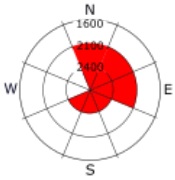

Tamaño

Origen

Tendencia

Situación secundaria

Nieve húmeda

Distribución

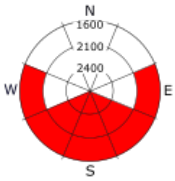

Tamaño

Origen

Tendencia

Estado del manto nivoso

Un manto endurecido superficialmente por costras o nieve venteada compacta no ha favorecido un transporte de nieve muy efectivo durante este último episodio de viento fuerte y precipitaciones débiles. Sin embargo, sobre todo en el norte del sector -vertiente sur del Cadí-Moixeró-, donde ha precipitado más, se han podido formar nuevas y pequeñas placas de viento, sobre todo en orientaciones S y E, que todavía podrían ser reactivas y provocar aludes accidentales de pequeño tamaño principalmente, puntualmente medio.

El sábado, la fuerte insolación y un aumento de temperatura diurna marcado, harán que el manto se humedezca superficialmente, sobre todo en orientaciones S. Se esperan purgas, caída de bolas o aludes de nieve húmeda, de pequeño tamaño en general, muy puntualmente medio, más frecuentes en vertientes S de fuerte pendiente y bajo resaltes rocosos.

Distribución del manto nivoso

Hay nieve desde 1400-1500 m. El manto es esquiable a partir de 1600 m. Los grosores están alrededor de 110-130 cm a unos 2.200 m y son superiores a los habituales.

Tendencia para las próximas 48-72h

Las placas tenderán a estabilizarse progresivamente y persistirán los problemas de nieve húmeda. Peligro: en leve DESCENSO.

El próximo boletín será emitido el día 2026-02-21

5 MUY FUERTE	4 FUERTE	3 NOTABLE	2 LIMITADO	1 DÉBIL

EAWS EUROPEAN AVALANCHE WARNING SERVICES

ICGC Institut Cartogràfic i Geològic de Catalunya

meteo.cat Servei Meteorològic de Catalunya

Boletín de peligro de aludes Ter-Freser
Del 20/02/2026 al 21/02/2026

(Válido fuera pistas de esquí y zonas no controladas)

DÉBIL (1) por debajo de 2.400 m.
LIMITADO (2) por encima.

Situación primaria

Nieve venteada

Distribución

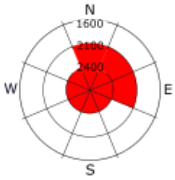

Tamaño

Origen

Tendencia

Estado del manto nivoso

Las precipitaciones débiles, viento fuerte y ventisca de las últimas jornadas han podido formar nuevas placas pequeñas, sobre todo en orientaciones S y E, que a menudo descansan sobre la previa costra superficial. En cotas altas, las placas de viento que podemos encontrar, pequeñas mayoritariamente, irán perdiendo reactividad progresivamente, pero todavía podrán ser sensibles por sobrecarga y provocar desencadenamiento de aludes accidentales de tamaño 1, pequeño, en general, o hasta tamaño medio, más puntualmente, en lugares donde se encuentren más acumulaciones.
El sábado, con el fuerte aumento térmico y la insolación intensa, no se descarta muy localmente alguna purga húmeda en laderas S de fuerte pendiente o bajo resaltes rocosos.

Distribución del manto nivoso

El manto nivoso presenta grosores muy excedentarios para la época del año. En lugares no afectados por el viento, los espesores oscilan entre 100-140 cm a unos 2.000 m, siendo esquiable a partir de unos 1.500 m.

Tendencia para las próximas 48-72h

Las placas tenderán a estabilizarse progresivamente. Peligro: en leve DESCENSO.

El próximo boletín será emitido el día 2026-02-21

5 MUY FUERTE	4 FUERTE	3 NOTABLE	2 LIMITADO	1 DÉBIL

EAWS EUROPEAN AVALANCHE WARNING SERVICES