MINISTERO DELLA DIFESA

meteomont Servizio Nazionale di previsione neve e valanghe

EAWS EUROPEAN AVALANCHE WARNING SERVICES

CARABINIERI

APPENNINO CALABRO

Bollettino Valanghe N. 235/2026 del 20/02/2026 ore 14.00
Validità 48 ore prossima emissione 21/02/2026

A cura del Servizio METEOMONT dell'ARMA dei CARABINIERI
In collaborazione con Servizio Meteorologico dell'Aeronautica militare

SITUAZIONE alle 14:00 del 20/02/2026

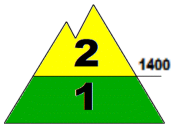

SITUAZIONE TIPO: neve a debole coesione e vento.



SITUAZIONE TIPO: pioggia su neve.

	Nord	Sud
Quota neve (mslm)	*1100 - 1400*	*1100 - 1400*

	Neve al suolo	Neve Fresca	Quota (mslm)
Altezza Neve (cm)	*038*	*023*	*1600*
	005	*005*	*1475*

VALANGHE OSSERVATE: Nessuna valanga.

PREVISIONI 21/02/2026

GRADO DI PERICOLO: MODERATO 2

SITUAZIONE TIPO: neve a debole coesione e vento.

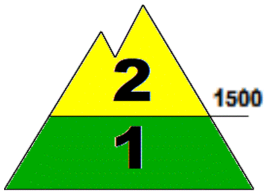

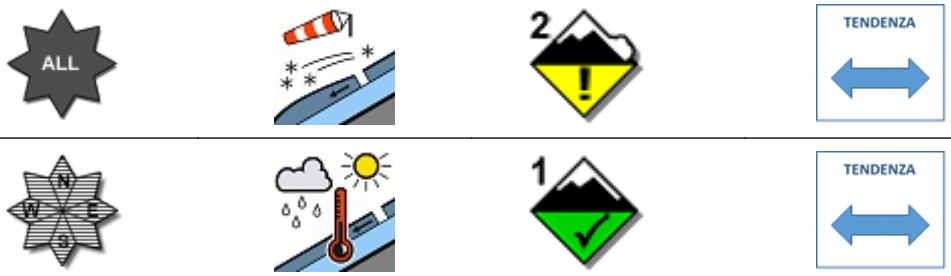

SITUAZIONE TIPO: pioggia su neve.

MANTO NEVOSO: La stabilità del manto nevoso è discreta su alcuni punti (aree) per tutte le esposizioni al di sopra di 1500 mslm, possibili valanghe di dimensioni medie.
La stabilità del manto nevoso è buona su pochissimi punti (aree) per isolati pendii al di sotto di 1500 mslm, possibili valanghe di dimensioni piccole.

AVVERTENZE

In considerazione delle avverse condizioni meteorologiche previste , le attività al di fuori delle piste battute e segnalate sono sconsigliate.

SCALA EUROPEA DEL GRADO DI PERICOLO VALANGHE

LEGENDA PROBLEMA

Bollettino realizzato su scala sinottica-regionale (standard EAWS). La sua valutazione non può escludere in alcun modo la necessità di una seria e capace valutazione locale del pericolo (singolo pendio) che può essere anche sensibilmente diverso. Le previsioni meteorologiche sono relative all'orario UTC (per l'Italia +1 in inverno e +2 in estate).

MINISTERO DELLA DIFESA

meteomont
Servizio Nazionale di previsione neve e valanghe

EAWS EUROPEAN AVALANCHE WARNING SERVICES

CARABINIERI

APPENNINO CALABRO

PREVISIONE METEO

Quota		21/02/2026 h6:00	21/02/2026 h12:00	21/02/2026 h18:00
1000	Venti	03 Nodi da Nord	06 Nodi da Nord	03 nodi da N-Ovest
	Temperature	+00 °C	+01 °C	+01 °C
	Temp.percepita	-2 °C	-2 °C	-1 °C
2000	Venti	07 Nodi da Nord	10 Nodi da Nord	09 nodi da N-Ovest
	Temperature	-02 °C	-02 °C	-01 °C
	Temp.percepita	-6 °C	-8 °C	-6 °C
3000	Venti	02 Nodi da Nord	03 Nodi da Nord	10 nodi da N-Ovest
	Temperature	-08 °C	-06 °C	-06 °C
	Temp.percepita	-8 °C	-9 °C	-13 °C
Zero termico		1400-1600 m.	1600-1800 m.	1600-1800 m.
Fenomeno		—	—	—
Stato del cielo				

LEGENDA FENOMENI

— Assenza Fenomeni · Nebbia · Foschia · Pioggia debole · Pioggia moderata · Pioggia forte · Temporali

Nevicata debole · Nevicata moderata · Nevicata forte

STATO DEL CIELO

Sereno · Poco nuvoloso · Nuvoloso · Molto nuvoloso · Coperto

Parametri meteonivometrici registrati presso i campi di rilevamento il 20/02/2026.

Località	Comune	Quota (m.s.l.m.)	Altezza neve (cm)	Neve caduta nelle 24 ore (cm)	Temp. Min (°C)	Temp. Max (°C)	Condizioni del tempo
BIVIO NARDODIPACE	Mongiana (VV)	1339	0	0	+1	+4	Pioggia moderata
GAMBARIE	Santo Stefano in Aspromonte (RC)	1367	Tracce di neve	Tracce di neve	-1	+7	Assenza di precipitazioni
COZZO VARDO	Morano Calabro (CS)	1475	4	4	-1	+2	Nevicata moderata
VALICO DI MONTE SCURO	Celico (CS)	1600	38	23	-1	+9	Nevicata moderata
BUTURO	Albi (CZ)	1530	22	14	-1	+7	Nevicata moderata

(*) Rilievi fuori campo

L'INFORMAZIONE E' PREVENZIONE - LEGGI L'ATTUALE GRADO DI PERICOLO VALANGHE!

IL CAPO DEL CENTRO NAZIONALE METEOMONT
(Ten. Col. RFI Emanuela Gini)
FIRMA AUTOGRAFA OMESSA AI SENSI
DELL'ART.3 DEL D.LGS N.39/1993