Bulletin d'estimation du risque d'avalanche

(valable en dehors des pistes balisées et ouvertes)

MASSIF : Renoso Incudine

Rédigé le vendredi 20 février 2026 à 15h

Estimation des risques pour le : SAMEDI 21 FÉVRIER

INSTABILITÉS DANS LA NEIGE FRAICHE VENTÉE

2

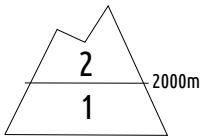

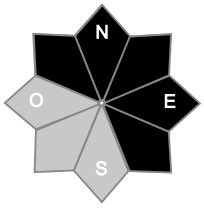

Au-dessus de 2000m indice de risque limité, plus bas indice faible.

Départs spontanés : Quelques départs par humidification au soleil.

Déclenchements provoqués : Quelques instabilités dans la neige récente ventée.

Indices de risque : 5 très fort - 4 fort - 3 marqué - 2 limité - 1 faible -- En noir : les pentes les plus dangereuses

Stabilité du manteau neigeux

Situation avalancheuse typique : neige ventée — neige humide

Déclenchements provoqués : Les récentes chutes de neige ventée ont généré de nouvelles plaques en versants Est. Certaines plaques d'un aspect poudreux sont déclenchables au passage d'un skieur ou randonneur. Elles sont plus épaisses et plus dures en altitude, et réparties de façon plus hétérogène, avec des accumulations localement épaisses. Ces plaques reposent sur des couches fragiles temporaires (neige récente moins dense ou neige roulée). Avalanches généralement de taille moyenne à grande (taille 2 à 3). En versants ombragés, une couche fragile persistante enfouie peut être sollicitée après cassure d'une plaque décrite au-dessus et donner une plus grande avalanche qui peut présenter des cassures importantes.
En dessous de 2000 mètres, voire plus haut en versants ensoleillés, la neige fraîche en surface, repose sur un manteau neigeux humidifié. Le déclenchement par un seul skieur n'est pas exclu. Les versants Nord et Est sont les plus chargés avec des plaques parfois épaisses.

Départs spontanés : Rares départs linéaires en neige ventée, par transport de la neige récente sous le vent de Nord. Avec le redoux, quelques petites avalanches sont possibles par humidification du manteau neigeux superficiel, départs ponctuels en pentes raides ensoleillées.

Autres : Risque de glissade en neige dure ou glacée aux abords des crêtes et sommets balayés par les vents.

Qualité de la neige

Qualification de l'enneigement : L'enneigement est excellent pour la saison à toutes altitudes. À Ghisoni Capanelle, on relève 1 mètre de neige à la station, 2 mètres au-dessus de 1800 m et plus de 3 mètres dans les combes abritées.
Limite d'enneigement skiable : 1300 à 1500 m selon le versant.
État de la neige : On trouve en surface une couche de neige fraîche, 10 à 30 cm mais le fort vent d'Ouest à Nord a rendu l'enneigement très hétérogène : les orientations Nord et Est sont souvent plus garnies que les pentes Ouest rapidement pelées ou verglacées dès que l'on se rapproche des crêtes et sommets. La neige est froide et poudreuse à l'abri du vent dès 1800 à 2000 m d'altitude, elle devient plus compacte, voire cartonnée dans les secteurs ventés. On trouve localement des accumulations de neige roulée. Corniches et accumulations parfois volumineuses sont en place.

Aperçu météo pour le samedi 21 février

	nuit	matin	après-midi	soir
Temps ensoleillé devenant plus doux				
Pluie-Neige				
Iso 0 °C	2 200 m	2 500 m	2 800 m	2 800 m
Vent 1500 m	↓ 20 km/h	↘ 15 km/h	↘ 15 km/h	↓ 15 km/h
Vent 2000 m	↓ 40 km/h	↓ 40 km/h	↓ 30 km/h	↓ 20 km/h

Épaisseur de neige hors-piste

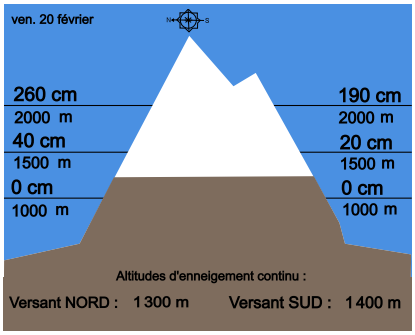

Précipitations à 1800 m

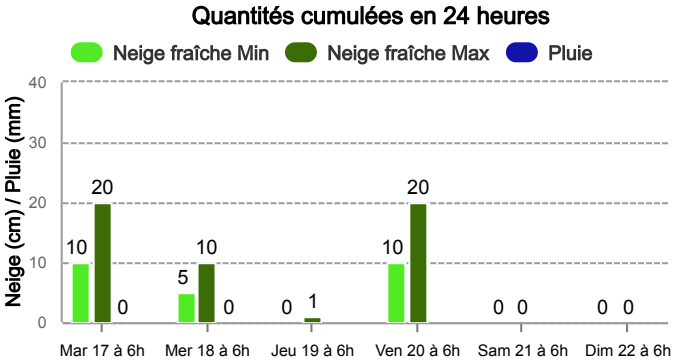

Tendance du dimanche 22 février

2

Indice de risque limité

Stabilisation des plaques en altitude mais augmentation de l'activité naturelle en neige humide avec la hausse des températures. Risque restant limité.

Pour consulter la vigilance en cours, veuillez vous rendre sur le site https://vigilance.meteofrance.fr/fr

Météo-France - 73 avenue de Paris, 94165 Saint-Mandé cedex - Contact : contact@meteo.fr

Rédigé par Météo-France avec la contribution des observateurs du réseau nivo-météorologiques. Partenariat : ANMSM (Maires de Stations de Montagne), DSF (Domaines Skiables de France), ADSP (Directeurs de Pistes et de la Sécurité des Stations de Sports d'Hiver) et autres acteurs de la montagne.

Bulletin neige & avalanches par téléphone au 0 892 68 10 20 Service 0,35 € / min + prix appel

RÉPUBLIQUE FRANÇAISE
Liberté Égalité Fraternité

METEO FRANCE
À VOS CÔTÉS, DANS UN CLIMAT QUI CHANGE

Bulletin d'estimation du risque d'avalanche

(valable en dehors des pistes balisées et ouvertes)

MASSIF : Renoso Incudine

Rédigé le vendredi 20 février 2026 à 15h

Conditions nivo-météo des 7 derniers jours

	sam. 14/02				dim. 15/02				lun. 16/02				mar. 17/02				mer. 18/02				jeu. 19/02				ven. 20/02			
	03h	09h	15h	21h	03h	09h	15h	21h	03h	09h	15h	21h	03h	09h	15h	21h	03h	09h	15h	21h	03h	09h	15h	21h	03h	09h	15h	21h
Météo																												
Vent (km/h)	50	40	30	50	40	50	50	50	90	100	110	120	110	70	60	50	45	55	45	40	60	70	80	100	80	60	60	40
à 2000m																												
Vent (km/h)	40	30	20	30	30	20	30	40	80	80	100	110	100	60	60	50	50	55	50	40	65	80	95	95	90	40	40	25
à 1500m																												

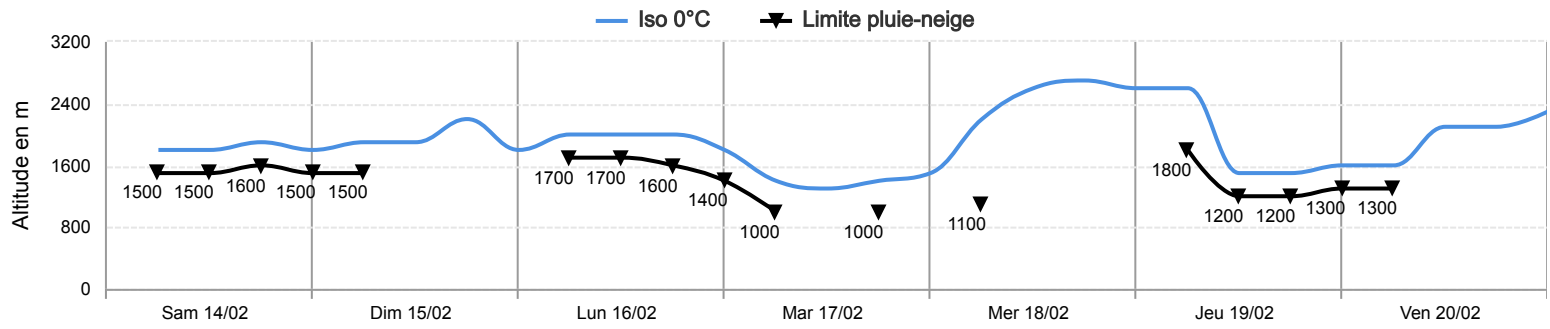

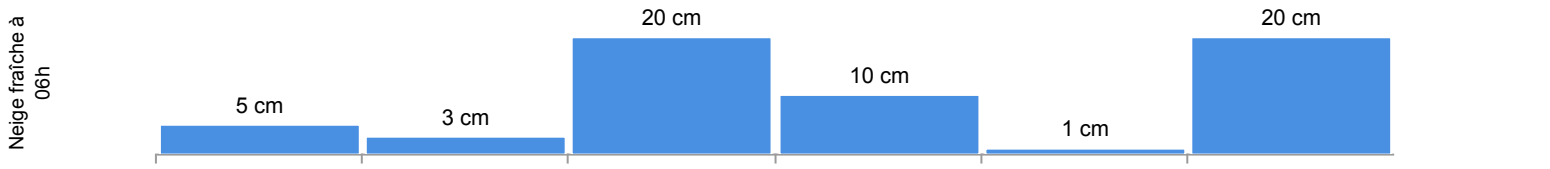

Risque d'avalanche	sam. 14/02	dim. 15/02	lun. 16/02	mar. 17/02	mer. 18/02	jeu. 19/02	ven. 20/02
	3	2	3	3	3	3	3

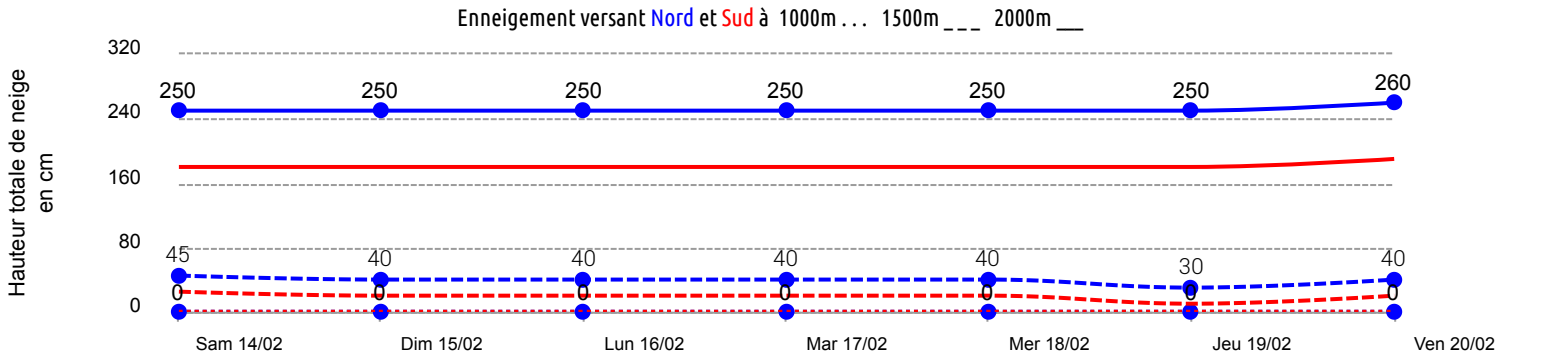

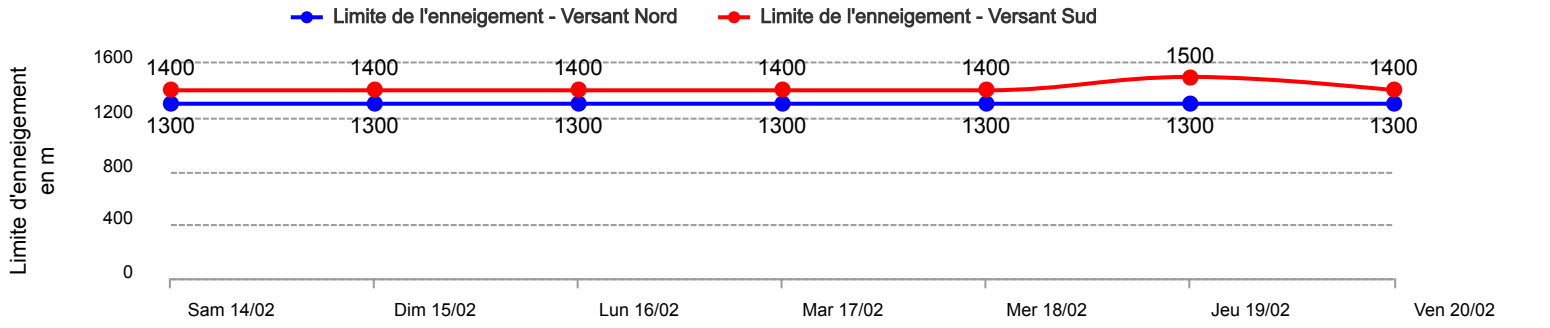

Pour consulter la vigilance en cours, veuillez vous rendre sur le site https://vigilance.meteofrance.fr/fr

Météo-France - 73 avenue de Paris, 94165 Saint-Mandé cedex - Contact : contact@meteo.fr

Bulletin neige & avalanches par téléphone au

0 892 68 10 20 Service 0,35 € / min + prix appel

Rédigé par Météo-France avec la contribution des observateurs du réseau nivo-météorologiques. Partenariat : ANMSM (Maires de Stations de Montagne), DSF (Domaines Skiables de France), ADSP (Directeurs de Pistes et de la Sécurité des Stations de Sports d'Hiver) et autres acteurs de la montagne.