Bulletin d'estimation du risque d'avalanche
(valable en dehors des pistes balisées et ouvertes)

MASSIF : Chartreuse

Rédigé le vendredi 20 février 2026 à 16h

Estimation des risques pour le : SAMEDI 21 FÉVRIER

MANTEAU NEIGEUX ENCORE MAL STABILISÉ, SURTOUT SUR LA PARTIE SOMMITALE DU MASSIF.

3

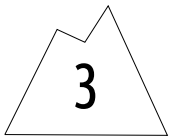

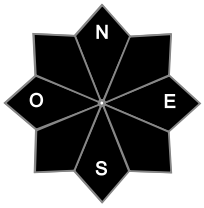

Indice de risque marqué.

Départs spontanés : Coulées au soleil + possibles avalanches de glissement.

Déclenchements provoqués : Nombreuses plaques formées par le vent du nord.

Indices de risque : 5 très fort - 4 fort - 3 marqué - 2 limité - 1 faible -- En noir : les pentes les plus dangereuses

Stabilité du manteau neigeux

Situation avalancheuse typique : neige fraîche neige ventée

Les dernières chutes de neige ont été de l'ordre de 40 cm, s'ajoutant à des cumuls déjà importants depuis plusieurs jours. Un vent de nord, soutenu près des crêtes, entraîne le transport de grosses quantités de neige meuble.
Déclenchements provoqués :le tassement de la neige récente a déjà commencé à opérer aux altitudes les plus basses, notamment à la faveur de quelques éclaircies. Par contre, sur la partie sommitale du massif de grosses accumulations sont en place et encore en cours de formation. Le passage d'un skieur est suffisant pour déclencher une avalanche de neige plus ou moins densifiée par le vent, donc pas toujours détectable.
Départs spontanés : ils peuvent être de différentes nature : soit des coulées de neige récente (taille 1 à 2) dans les pentes raides exposées au soleil pour la première fois depuis les dernières chutes, soit des plaques de neige sèche surchargées par le vent de nord dans les parages des crêtes, soit des avalanches de glissement emportant la totalité du manteau neigeux jusqu'au terrain, notamment dans les pentes herbeuses raides et ensoleillées en dessous de 1800 m.

Qualité de la neige

Qualification de l'enneigement : l'enneigement est bon pour la saison dès 1200 m, puis abondant au dessus de 1500 m environ, notamment dans les combes d'altitude. Les crêtes sont parfois dégarnies ou parfois fortement cornichées.

Limites skiables : vers 1100/1300 m.

Qualité de la neige samedi : alourdie et légèrement croûtée en début de journée jusqu'à 1500/2000 m selon les versants. Dans les ubacs d'altitude, la neige sera souvent soufflée.

Aperçu météo pour le samedi 21 février

	nuit	matin	après-midi	soir
Pluie-Neige				
Iso 0 °C	1 400 m	1 800 m	2 100 m	2 600 m
Vent 1500 m	20 km/h	20 km/h	20 km/h	15 km/h
Vent 2000 m	50 km/h	50 km/h	50 km/h	50 km/h

Épaisseur de neige hors-piste

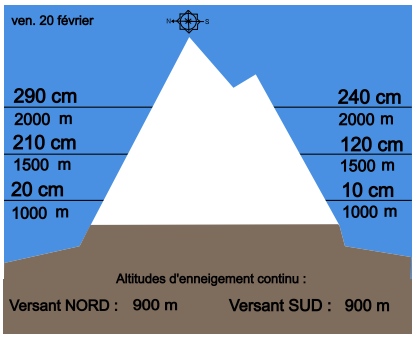

Précipitations à 1800 m

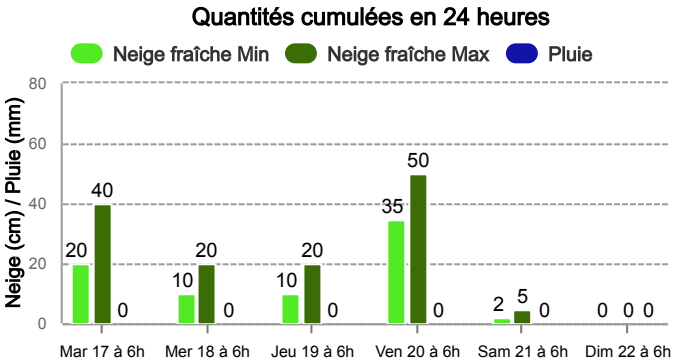

Tendance du dimanche 22 février

3 **Indice de risque marqué**

Le fort redoux attendu dimanche pourrait déstabiliser les pentes ensoleillées, jusqu'à des altitudes plus élevées que samedi. Dans les versants à l'ombre, l'instabilité du manteau neigeux restera encore très présente.

Pour consulter la vigilance en cours, veuillez vous rendre sur le site https://vigilance.meteofrance.fr/fr

Météo-France - 73 avenue de Paris, 94165 Saint-Mandé cedex - Contact : contact@meteo.fr

Rédigé par Météo-France avec la contribution des observateurs du réseau nivo-météorologiques. Partenariat : ANMSM (Maires de Stations de Montagne), DSF (Domaines Skiables de France), ADSP (Directeurs de Pistes et de la Sécurité des Stations de Sports d'Hiver) et autres acteurs de la montagne.

Bulletin neige & avalanches par téléphone au **0 892 68 10 20** Service 0,35 € / min + prix appel

RÉPUBLIQUE FRANÇAISE
Liberté Égalité Fraternité

METEO FRANCE
À VOS CÔTÉS, DANS UN CLIMAT QUI CHANGE

Bulletin d'estimation du risque d'avalanche

(valable en dehors des pistes balisées et ouvertes)

MASSIF : Chartreuse

Rédigé le vendredi 20 février 2026 à 16h

Conditions nivo-météo des 7 derniers jours

	sam. 14/02				dim. 15/02				lun. 16/02				mar. 17/02				mer. 18/02				jeu. 19/02				ven. 20/02			
	03h	09h	15h	21h	03h	09h	15h	21h	03h	09h	15h	21h	03h	09h	15h	21h	03h	09h	15h	21h	03h	09h	15h	21h	03h	09h	15h	21h
Météo																												
Vent (km/h)	15	25	40	35	45	25	30	55	65	75	80	80	75	60	45	30	30	20	45	90	75	50	55	70	65	60	60	60
à 2000m	←	↙	↙	↓	↓	↓	↘	→	↘	→	↘	↘	↘	↘	↘	↘	↓	→	↗	↑	↑	→	↘	↘	↓	↓	↓	↓
Vent (km/h)	10	20	30	35	35	10	10	25	35	45	60	60	50	40	30	20	15	15	25	75	45	25	25	25	40	35	35	30
à 1500m	↙	↙	↓	↓	↻	↙	→	→	↘	→	↘	↘	→	↘	↘	↓	↙	↑	↑	↑	↑	↗	→	↘	→	↓	↓	↓

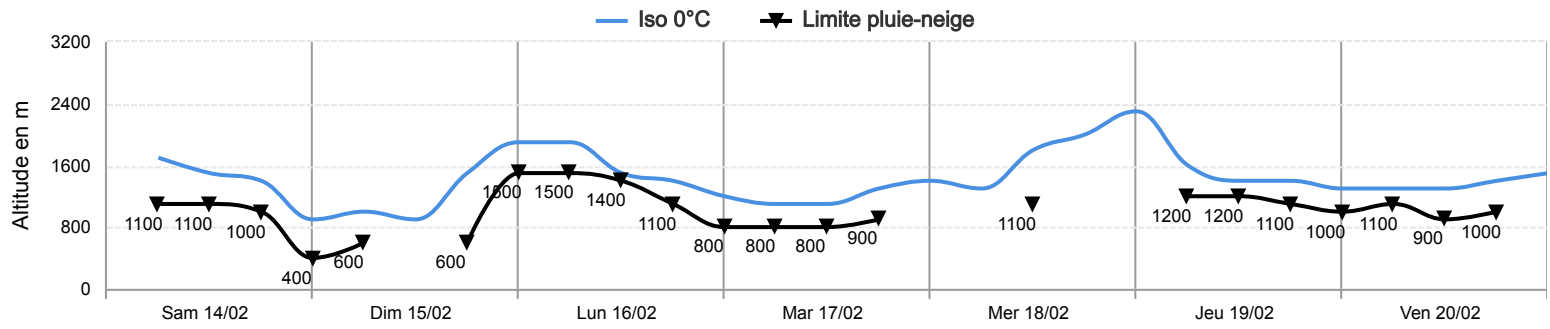

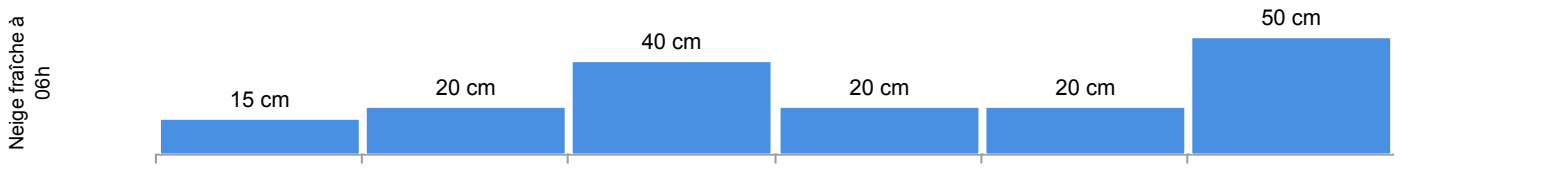

Risque d'avalanche	sam. 14/02	dim. 15/02	lun. 16/02	mar. 17/02	mer. 18/02	jeu. 19/02	ven. 20/02
	3	3	3	3	3	4	4

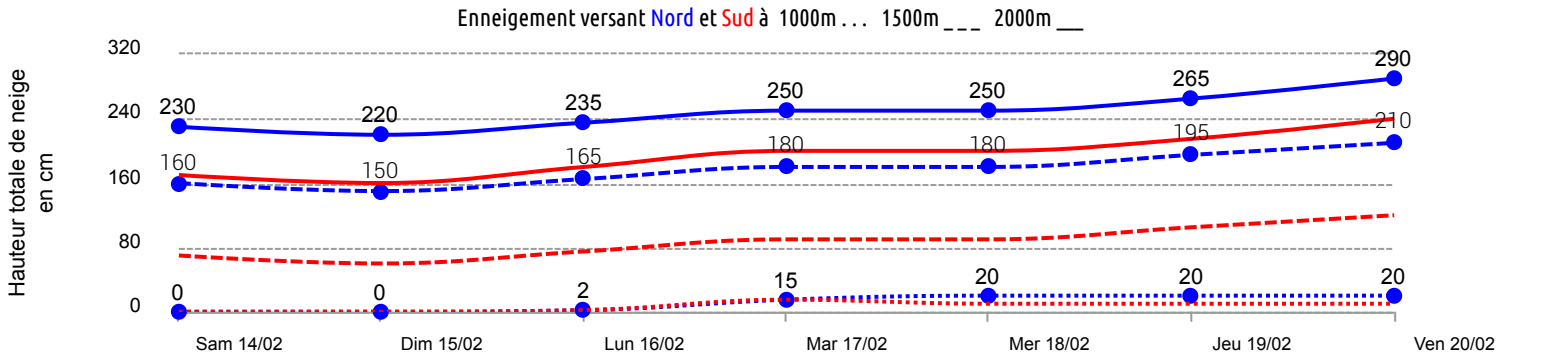

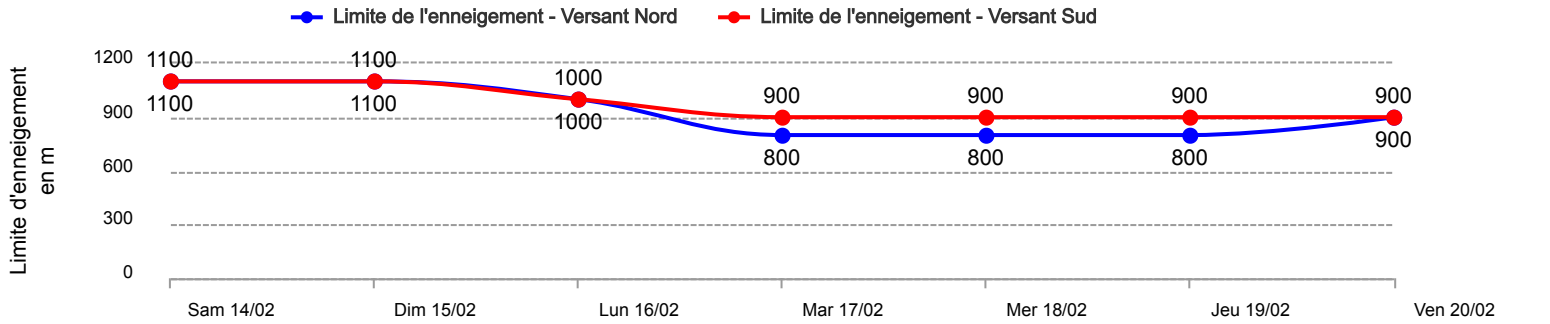

Pour consulter la vigilance en cours, veuillez vous rendre sur le site https://vigilance.meteofrance.fr/fr

Météo-France - 73 avenue de Paris, 94165 Saint-Mandé cedex - Contact : contact@meteo.fr

Rédigé par Météo-France avec la contribution des observateurs du réseau nivo-météorologiques. Partenariat : ANMSM (Maires de Stations de Montagne), DSF (Domaines Skiables de France), ADSP (Directeurs de Pistes et de la Sécurité des Stations de Sports d'Hiver) et autres acteurs de la montagne.

Bulletin neige & avalanches par téléphone au
0 892 68 10 20 Service 0,35 € / min + prix appel