Bulletin d'estimation du risque d'avalanche
(valable en dehors des pistes balisées et ouvertes)

MASSIF : Grandes-Rousses

Rédigé le vendredi 20 février 2026 à 16h

Estimation des risques pour le : SAMEDI 21 FÉVRIER

FORTE INSTABILITÉ DU MANTEAU NEIGEUX EN ALTITUDE.

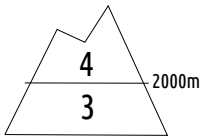

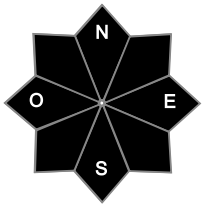

Au-dessus de 2000m indice de risque fort, plus bas indice marqué.

Départs spontanés : Coulées au soleil + possibles avalanches de glissement.

Déclenchements provoqués : Faciles et souvent de grande ampleur.

Indices de risque : 5 très fort - 4 fort - 3 marqué - 2 limité - 1 faible -- En noir : les pentes les plus dangereuses

Stabilité du manteau neigeux

Situation avalancheuse typique : neige fraîche — neige ventée

Les dernières chutes de neige ont été de l'ordre de 40/50 cm, s'ajoutant à des cumuls déjà importants depuis plusieurs jours. Un vent de nord soutenu entraîne le transport de grosses quantités de neige meuble en altitude.
Déclenchements provoqués : les éclaircies ensoleillées de ce vendredi ont favorisé le tassement de la neige récente sur la partie basse du massif. Par contre, au dessus de 2000 m environ, la neige récente n'est pas stabilisée, ce à quoi s'ajoutent de grosses accumulations dues au vent de nord. Les plaques, friables ou dures selon le travail du vent, sont très réactives. Les déclenchements préventifs effectués en station mettent en mouvement de gros volumes de neige et l'instabilité est encore plus sensible au dessus de 2300/2500 m.
Départs spontanés : ils peuvent être de différentes nature : soit des coulées de neige récente (taille 1 à 2) dans les pentes raides exposées au soleil pour la première fois depuis les dernières chutes, soit des plaques de neige sèche surchargées par le vent de nord dans les secteurs à plus de 2000/2400 m, soit des avalanches de glissement emportant la totalité du manteau neigeux jusqu'au terrain, notamment dans les pentes herbeuses raides et ensoleillées en dessous de 1800/2000 m.

Qualité de la neige

Qualification de l'enneigement : l'enneigement est bon pour la saison dès 1200 m, puis abondant au dessus de 1500 m environ, notamment dans les combes d'altitude. Les crêtes sont parfois dégarnies ou parfois fortement cornichées.

Limites skiables : vers 1100/1300 m.

Qualité de la neige samedi : alourdie et légèrement croûtée en début de journée jusqu'à 1600/2000 m selon les versants. Dans les ubacs d'altitude, la neige sera souvent soufflée. Dans les combes abritées du vent, on trouvera de grosses quantités de neige profonde.

Aperçu météo pour le samedi 21 février

	nuit	matin	après-midi	soir
Pluie-Neige				
Iso 0 °C	1 900 m	2 300 m	2 400 m	2 500 m
Vent 2000 m	40 km/h	25 km/h	25 km/h	20 km/h
Vent 3000 m	60 km/h	55 km/h	50 km/h	40 km/h

Épaisseur de neige hors-piste

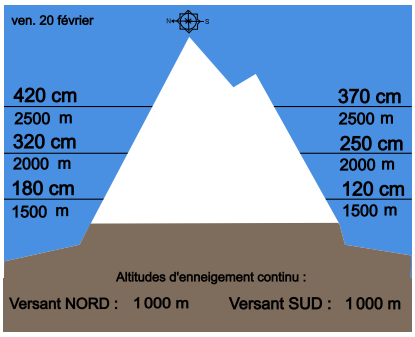

Précipitations à 1800 m

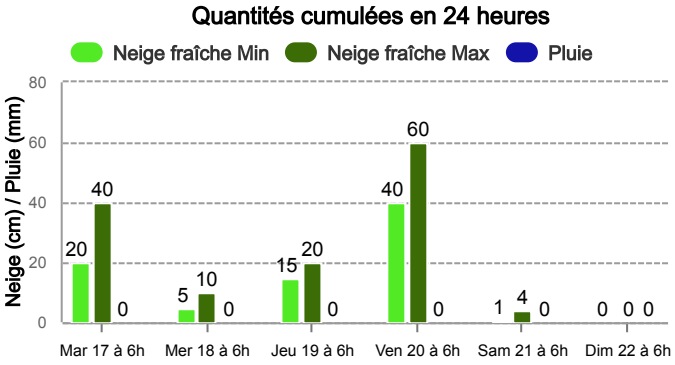

Tendance du dimanche 22 février

Indice de risque marqué

Le fort redoux attendu dimanche pourrait déstabiliser les pentes ensoleillées, jusqu'à des altitudes plus élevées que samedi. Dans les versants à l'ombre, l'instabilité du manteau neigeux restera encore très présente.

Pour consulter la vigilance en cours, veuillez vous rendre sur le site https://vigilance.meteofrance.fr/fr

Météo-France - 73 avenue de Paris, 94165 Saint-Mandé cedex - Contact : contact@meteo.fr

Rédigé par Météo-France avec la contribution des observateurs du réseau nivo-météorologiques. Partenariat : ANMSM (Maires de Stations de Montagne), DSF (Domaines Skiables de France), ADSP (Directeurs de Pistes et de la Sécurité des Stations de Sports d'Hiver) et autres acteurs de la montagne.

Bulletin neige & avalanches par téléphone au 0 892 68 10 20 Service 0,35 € / min + prix appel

RÉPUBLIQUE FRANÇAISE
Liberté Égalité Fraternité

METEO FRANCE
À VOS CÔTÉS, DANS UN CLIMAT QUI CHANGE

Bulletin d'estimation du risque d'avalanche

(valable en dehors des pistes balisées et ouvertes)

MASSIF : Grandes-Rousses

Rédigé le vendredi 20 février 2026 à 16h

Conditions nivo-météo des 7 derniers jours

	sam. 14/02				dim. 15/02				lun. 16/02				mar. 17/02				mer. 18/02				jeu. 19/02				ven. 20/02			
	03h	09h	15h	21h	03h	09h	15h	21h	03h	09h	15h	21h	03h	09h	15h	21h	03h	09h	15h	21h	03h	09h	15h	21h	03h	09h	15h	21h
Météo																												
Vent (km/h)	25	20	50	45	50	45	45	55	70	85	110	120	100	80	60	40	45	30	40	90	55	35	60	60	60	60	60	70
à 3000m																												
Vent (km/h)	25	5	20	10	5	10	25	30	40	60	80	80	70	55	45	25	20	20	20	65	35	20	25	25	35	40	35	40
à 2000m																												

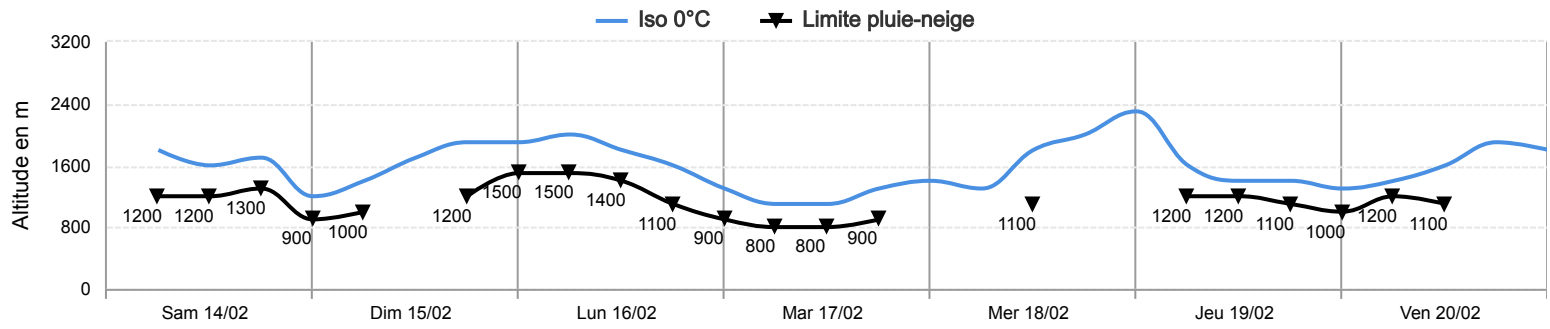

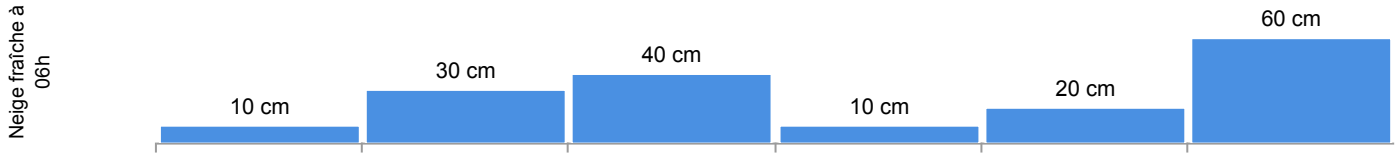

Risque d'avalanche	sam. 14/02	dim. 15/02	lun. 16/02	mar. 17/02	mer. 18/02	jeu. 19/02	ven. 20/02
	4	3	4	4	4	5	5

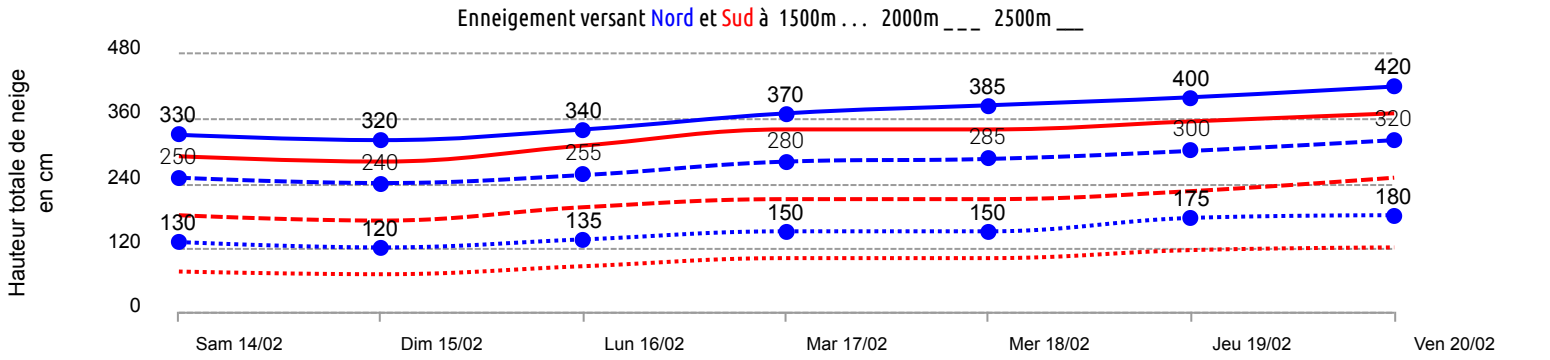

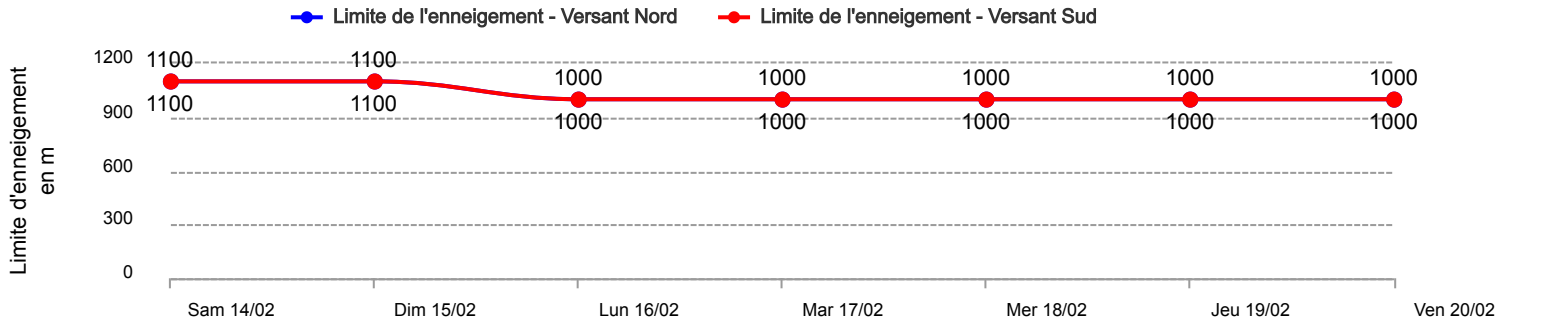

Pour consulter la vigilance en cours, veuillez vous rendre sur le site https://vigilance.meteofrance.fr/fr

Météo-France - 73 avenue de Paris, 94165 Saint-Mandé cedex - Contact : contact@meteo.fr

Rédigé par Météo-France avec la contribution des observateurs du réseau nivo-météorologiques. Partenariat : ANMSM (Maires de Stations de Montagne), DSF (Domaines Skiables de France), ADSP (Directeurs de Pistes et de la Sécurité des Stations de Sports d'Hiver) et autres acteurs de la montagne.

Bulletin neige & avalanches par téléphone au
0 892 68 10 20 Service 0,35 € / min + prix appel