RÉPUBLIQUE FRANÇAISE
Liberté Égalité Fraternité

METEO FRANCE
À VOS CÔTÉS, DANS UN CLIMAT QUI CHANGE

Bulletin d'estimation du risque d'avalanche

(valable en dehors des pistes balisées et ouvertes)

MASSIF : Haute-Bigorre

Rédigé le vendredi 20 février 2026 à 16h

Estimation des risques pour le : SAMEDI 21 FÉVRIER

NEIGE RECENTE VENTEE, S'HUMIDIFIANT AU SOLEIL, LENTE EVOLUTION A L'OMBRE.

3

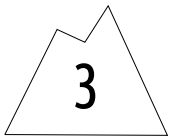

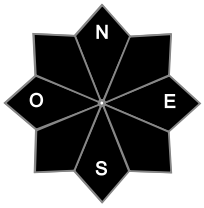

Indice de risque marqué.

Départs spontanés : en neige humide.

Déclenchements provoqués : plaques à vent.

Indices de risque : 5 très fort - 4 fort - 3 marqué - 2 limité - 1 faible -- En noir : les pentes les plus dangereuses

Stabilité du manteau neigeux

Situation avalancheuse typique : neige ventée neige humide

Déclenchements provoqués : de **nombreuses plaques à vent ou empilement de plaques sont en place en tous secteurs**, ne s'humidifiant que lentement et en surface dans les pentes ombragées, plus rapidement au soleil. Ces plaques sont **facilement déclenchables par un seul skieur ou randonneur**, formées d'empilement de couches frittées avec cohésion sur des couches mixtes de neige récente peu évoluée, de grains anguleux et de neige roulée. Une faible sollicitation peut donc donner lieu à des **avalanches de taille 2 à 3** avec **cassures linéaires de 20 à 40 cm** possibles, **taille 3 à localement 4** avec avec **cassures de 50 cm et plus au-dessus de 2300/2400m** d'altitude en tous versants. Dépôts de blocs durs en Ouest à Nord, moins solides dans les autres versants.
Ces **plaques**, **sensibles au faibles surcharges**, vont **persister au-dessus de 2000m dans les versants Nord**, **au-dessus de 2400/2500m en pentes Sud raides**.
Elles ne résisteront pas sous ces limites et orientations à l'humidification qui se met en place (douceur et soleil).

Observables : travail du vent très turbulent des derniers jours visible et plaques facilement identifiables en général, moins identifiables et d'aspect encore poudreux et mat dans combes déventées.

Départs spontanés : risque limité (2) en **pentes raides, au soleil et dans la douceur qui s'installe**. Des **coulées** (boulettes et escargots) en pentes **Est à Sud-Est le matin**, **petites avalanches** en général l'après-midi dans les pentes **Sud-Est à Sud-Ouest**.
Des avalanches de taille **moyenne** sont attendues **en cours d'après-midi** en partant des **accumulations constituées au-dessus de 2000 à 2200m** : **chute d'une corniche fragilisée au soleil, déclenchement des plaques décrites** ci-dessus entraînant la neige en contrebas, **plus rarement une avalanche de fond**, avec **cassures linéaires pouvant atteindre 20 à 50 cm**.

Autres : quelques **reptations possibles** et **apparition de quelques fissures** au **pied des pentes raides** ou proche des **ruptures de pentes**. Corniches en place fragilisées par l'humidification.

Qualité de la neige

Enneigement : en retrait lent ce samedi avec douceur et soleil qui s'installent, il débute vers 1200m en Nord, 1300m en Sud, mais ces limites remontent au cours de la journée. Crêtes, cols et sommets pelés en expositions Ouest, en neige dure à très dure partout ailleurs.
Limites skiables : à partir de 1300 à 1400m au petit matin suivant les versants, car sans sous-couche en dessous. La neige fond en versants ensoleillés, la limite remonte vers 1500/1600m dans la journée. Fonte plus lente à l'ombre.
État de la neige : au petit matin, neige frittée à cartonnée en versants ombragés au-dessus de 1600 à 1800m, neige dure et regelée partout ailleurs, mais petite croûte cassante sous 1800/1900m. La neige regelée ramollit au soleil. Dans les secteurs à l'ombre, la neige très travaillée par le vent s'humidifie juste en surface sous 1800 à 2000m, reste en l'état au-dessus.

Aperçu météo pour le samedi 21 février

	nuit	matin	après-midi	soir

Beau temps sec et doux, vent faible. Mise en place de cycles gel/dégel du manteau neigeux.

Pluie-Neige				
Iso 0 °C	3 000 m	3 100 m	3 300 m	3 400 m
Vent 2000 m	0 km/h	5 km/h	5 km/h	5 km/h
Vent 3000 m	15 km/h	10 km/h	15 km/h	15 km/h

Pour consulter la vigilance en cours, veuillez vous rendre sur le site https://vigilance.meteofrance.fr/fr

Météo-France - 73 avenue de Paris, 94165 Saint-Mandé cedex - Contact : contact@meteo.fr

Rédigé par Météo-France avec la contribution des observateurs du réseau nivo-météorologiques. Partenariat : ANMSM (Maires de Stations de Montagne), DSF (Domaines Skiables de France), ADSP (Directeurs de Pistes et de la Sécurité des Stations de Sports d'Hiver) et autres acteurs de la montagne.

Bulletin neige & avalanches par téléphone au
0 892 68 10 20 Service 0,35 € / min + prix appel

Bulletin d'estimation du risque d'avalanche

(valable en dehors des pistes balisées et ouvertes)

MASSIF : Haute-Bigorre

Rédigé le vendredi 20 février 2026 à 16h

Épaisseur de neige hors-piste

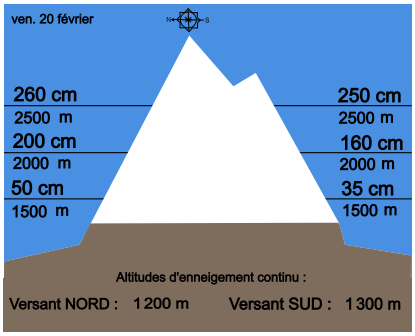

Précipitations à 1800 m

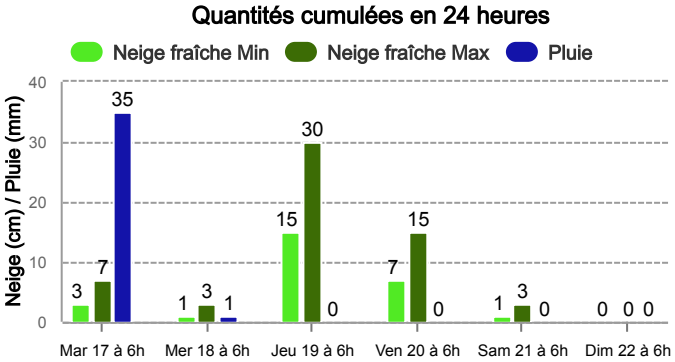

Tendance du dimanche 22 février

Indice de risque marqué

Maintien du risque accidentel au niveau 3 (marqué) par persistance des instabilités en neige récente et des plaques à vent dans les pentes d'un large secteur Nord d'altitude.

Pour consulter la vigilance en cours, veuillez vous rendre sur le site https://vigilance.meteofrance.fr/fr

Météo-France - 73 avenue de Paris, 94165 Saint-Mandé cedex - Contact : contact@meteo.fr

Rédigé par Météo-France avec la contribution des observateurs du réseau nivo-météorologiques. Partenariat : ANMSM (Maires de Stations de Montagne), DSF (Domaines Skiables de France), ADSP (Directeurs de Pistes et de la Sécurité des Stations de Sports d'Hiver) et autres acteurs de la montagne.

Bulletin neige & avalanches par téléphone au

0 892 68 10 20 Service 0,35 € / min + prix appel

RÉPUBLIQUE FRANÇAISE
Liberté Égalité Fraternité

METEO FRANCE
À VOS CÔTÉS, DANS UN CLIMAT QUI CHANGE

Bulletin d'estimation du risque d'avalanche

(valable en dehors des pistes balisées et ouvertes)

MASSIF : Haute-Bigorre

Rédigé le vendredi 20 février 2026 à 16h

Conditions nivo-météo des 7 derniers jours

	sam. 14/02				dim. 15/02				lun. 16/02				mar. 17/02				mer. 18/02				jeu. 19/02				ven. 20/02			
	03h	09h	15h	21h	03h	09h	15h	21h	03h	09h	15h	21h	03h	09h	15h	21h	03h	09h	15h	21h	03h	09h	15h	21h	03h	09h	15h	21h
Météo																												
Vent (km/h)	85	60	65	40	35	40	80	90	95	85	75	80	60	55	60	55	50	100	110	90	95	90	60	30	30	55	55	35
à 3000m																												
Vent (km/h)	55	55	55	40	40	15	35	50	55	35	60	60	55	45	10	15	25	60	75	45	70	70	45	25	25	10	15	5
à 2000m																												

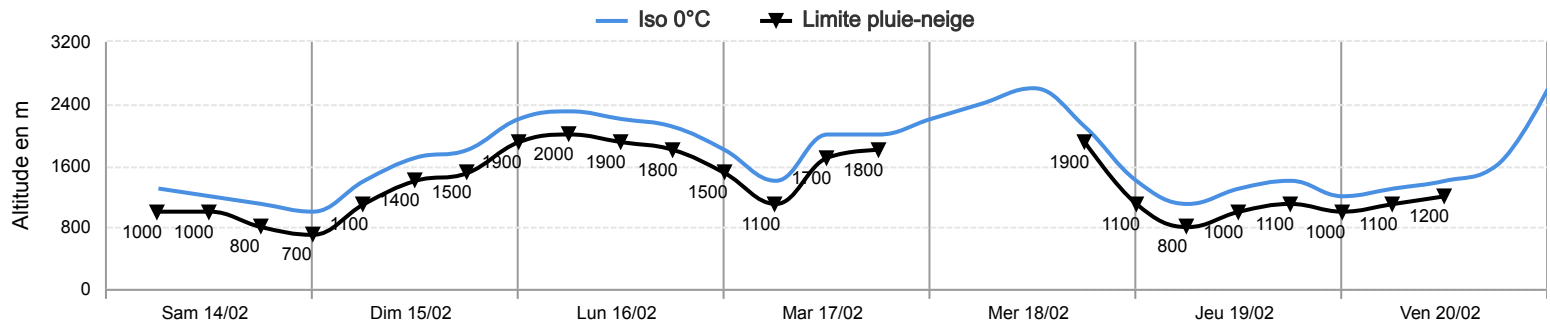

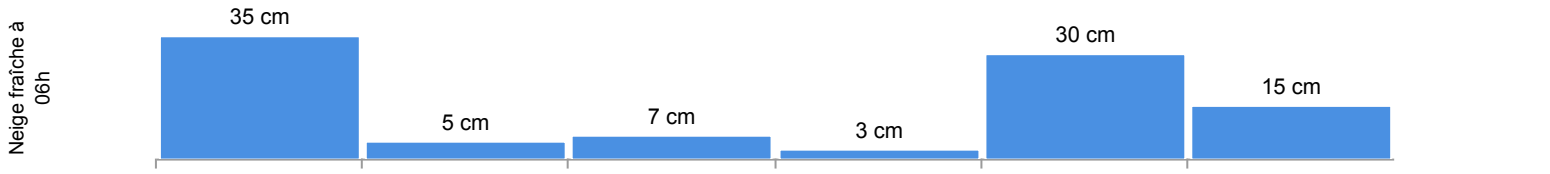

Risque d'avalanche	sam. 14/02	dim. 15/02	lun. 16/02	mar. 17/02	mer. 18/02	jeu. 19/02	ven. 20/02
	3	4	4	4	3	3	3

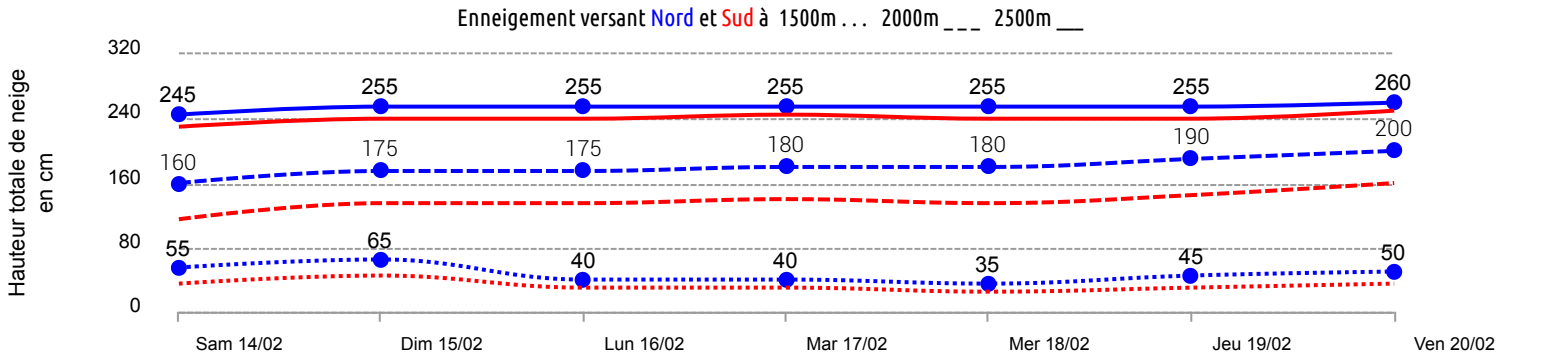

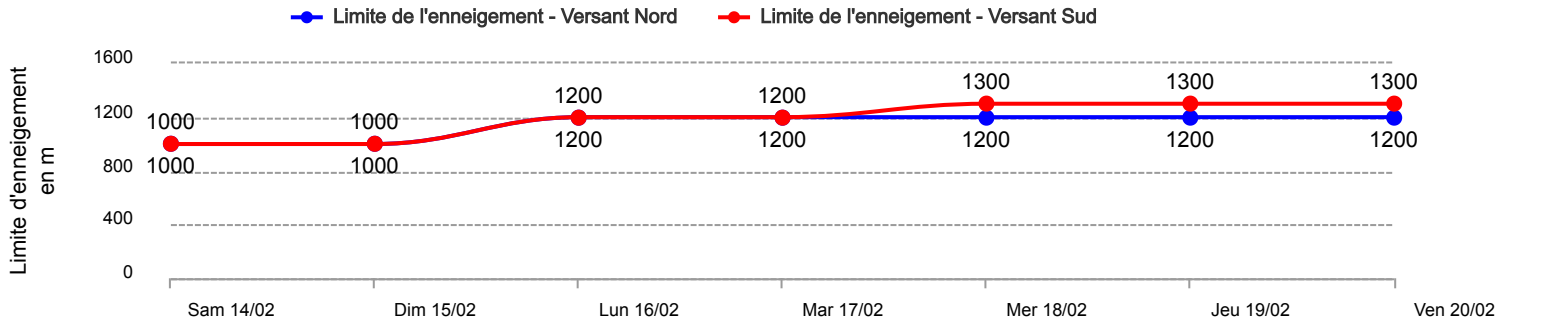

Pour consulter la vigilance en cours, veuillez vous rendre sur le site https://vigilance.meteofrance.fr/fr

Météo-France - 73 avenue de Paris, 94165 Saint-Mandé cedex - Contact : contact@meteo.fr

Rédigé par Météo-France avec la contribution des observateurs du réseau nivo-météorologiques. Partenariat : ANMSM (Maires de Stations de Montagne), DSF (Domaines Skiables de France), ADSP (Directeurs de Pistes et de la Sécurité des Stations de Sports d'Hiver) et autres acteurs de la montagne.

Bulletin neige & avalanches par téléphone au

0 892 68 10 20 Service 0,35 € / min + prix appel