Bulletin d'estimation du risque d'avalanche

(valable en dehors des pistes balisées et ouvertes)

MASSIF : Mercantour

Rédigé le vendredi 20 février 2026 à 16h

Estimation des risques pour le : SAMEDI 21 FÉVRIER

NOMBREUSES PLAQUES VENTÉES DANS LA NEIGE RÉCENTE, DÉPARTS NATURELS EN NEIGE HUMIDE

3

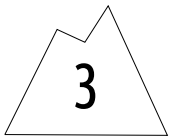

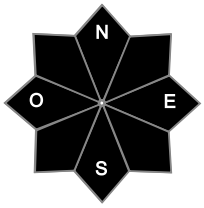

Indice de risque marqué.

Départs spontanés : devenant nombreux par humidification au soleil et avec la hausse des températures.

Déclenchements provoqués : nombreuses instabilités dans la neige récente ventée.

Indices de risque : 5 très fort - 4 fort - 3 marqué - 2 limité - 1 faible -- En noir : les pentes les plus dangereuses

Stabilité du manteau neigeux

Situation avalancheuse typique : neige ventée couche fragile persistante

Déclenchements provoqués :
Nombreuses instabilités dans la neige récente ventée, possibles en toutes orientations, en particulier au dessus de 2000 m, même loin des crêtes. Les plaques formées en surface du manteau neigeux sont souvent d'aspect durci par le vent, sinon encore poudreuses et plus difficiles à détecter dans les secteurs plus abrités. Elles peuvent être faciles à déclencher au passage d'un seul skieur, engendrant des cassures linéaires, et des avalanches de taille généralement petite à moyenne (taille 1 à 2), une rare grande est possible dans les zones de forte accumulation, plutôt en un large secteur est à sud.

Départs spontanés : départs d'avalanches par humidification superficielle du manteau neigeux : peu probables en début de journée, puis départs ponctuels en pentes raides au fil de la course du soleil, souvent près des rochers, le plus souvent de petite taille. Départs plus nombreux et plus volumineux en dessous de 2000/2200 m, où l'humidification est plus importante avec le redoux, de taille petite à moyenne.
Quelques départs linéaires en neige ventée sont encore possibles, par transport de neige récente sous l'effet du vent de nord encore sensible, généralement au dessus de 2400 m environ. Avalanches petites à moyennes, localement une grande taille est possible dans les zones de forte accumulation.

Qualité de la neige

Enneigement très excédentaire pour un mois de février. Il faut remonter à 2015 pour trouver un enneigement encore plus abondant à cette période de l'année.
Données observées : 155 cm à la nivôse de Millefonts à 2430 m.

Enneigement skiable dès 1300 m en ubacs en terrains favorables et 1600 m en adrets

État de la neige en surface : neige récente le plus souvent travaillée par le vent de nord, ou encore parfois poudreuse dans les zones abritées. En journée, poursuite du transport et de la densification de la neige récente par le vent de nord. Abords des crêtes et sommets dégarnis par le vent, ou au contraire corniches parfois épaisses. Bon regel nocturne en orientations ensoleillées jusqu'à 2400/2500 m, puis l'humidification reprend en journée, et gagne en profondeur en dessous de 2000/2200 m sous l'effet du redoux.

Aperçu météo pour le samedi 21 février

nuit	matin	après-midi	soir

Temps ensoleillé et de plus en plus doux. Vent de nord encore sensible en altitude.

Pluie-Neige				
Iso 0 °C	2 400 m	2 700 m	2 800 m	2 900 m
Vent 2000 m	↘ 15 km/h	↘ 20 km/h	↘ 15 km/h	↓ 20 km/h
Vent 3000 m	↘ 50 km/h	↘ 50 km/h	↘ 50 km/h	↘ 30 km/h

Épaisseur de neige hors-piste

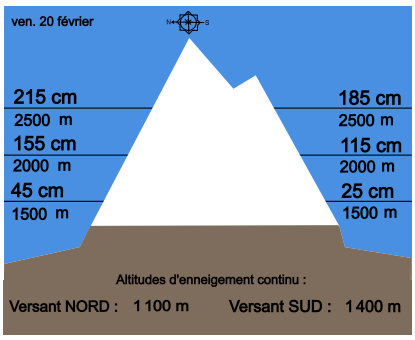

Précipitations à 1800 m

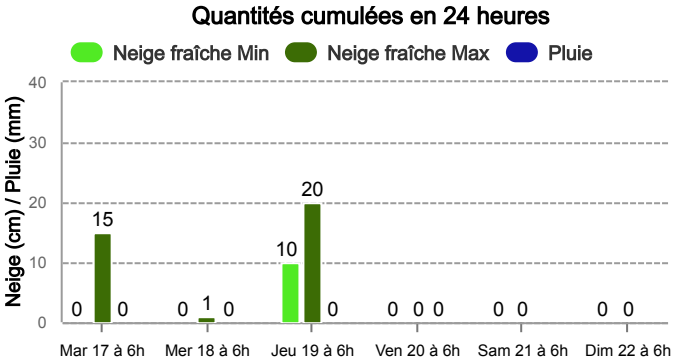

Tendance du dimanche 22 février

3

Indice de risque marqué

Risque restant marqué avec encore des plaques ventées présentes en altitude, et des départs naturels en neige humide devenant plus nombreux et de plus grande taille avec des températures encore en hausse.

Pour consulter la vigilance en cours, veuillez vous rendre sur le site https://vigilance.meteofrance.fr/fr

Météo-France - 73 avenue de Paris, 94165 Saint-Mandé cedex - Contact : contact@meteo.fr

Rédigé par Météo-France avec la contribution des observateurs du réseau nivo-météorologiques. Partenariat : ANMSM (Maires de Stations de Montagne), DSF (Domaines Skiables de France), ADSP (Directeurs de Pistes et de la Sécurité des Stations de Sports d'Hiver) et autres acteurs de la montagne.

Bulletin neige & avalanches par téléphone au
0 892 68 10 20 Service 0,35 € / min + prix appel

Bulletin d'estimation du risque d'avalanche

(valable en dehors des pistes balisées et ouvertes)

MASSIF : Mercantour

Rédigé le vendredi 20 février 2026 à 16h

Conditions nivo-météo des 7 derniers jours

	sam. 14/02				dim. 15/02				lun. 16/02				mar. 17/02				mer. 18/02				jeu. 19/02				ven. 20/02			
	03h	09h	15h	21h	03h	09h	15h	21h	03h	09h	15h	21h	03h	09h	15h	21h	03h	09h	15h	21h	03h	09h	15h	21h	03h	09h	15h	21h
Météo																												
Vent (km/h)	80	90	75	65	45	30	40	50	55	75	100	80	75	70	50	40	35	25	35	75	55	55	80	80	75	60	50	30
à 3000m																												
Vent (km/h)	50	75	65	50	30	10	20	30	30	40	65	40	60	50	20	20	15	15	20	40	30	35	35	45	45	40	15	15
à 2000m																												

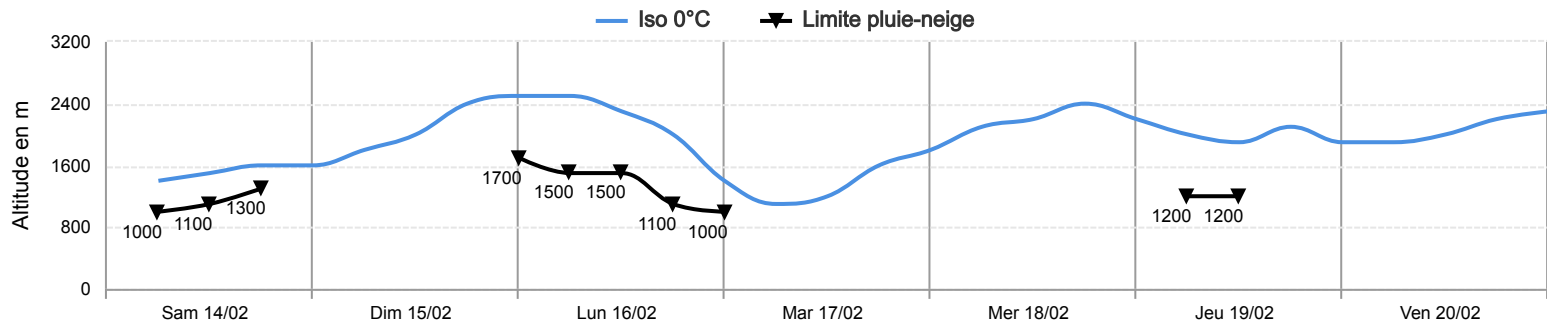

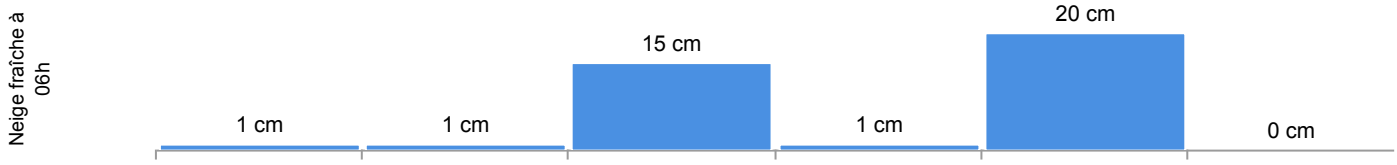

Risque d'avalanche	sam. 14/02	dim. 15/02	lun. 16/02	mar. 17/02	mer. 18/02	jeu. 19/02	ven. 20/02
	3	3	3	3	3	3	3

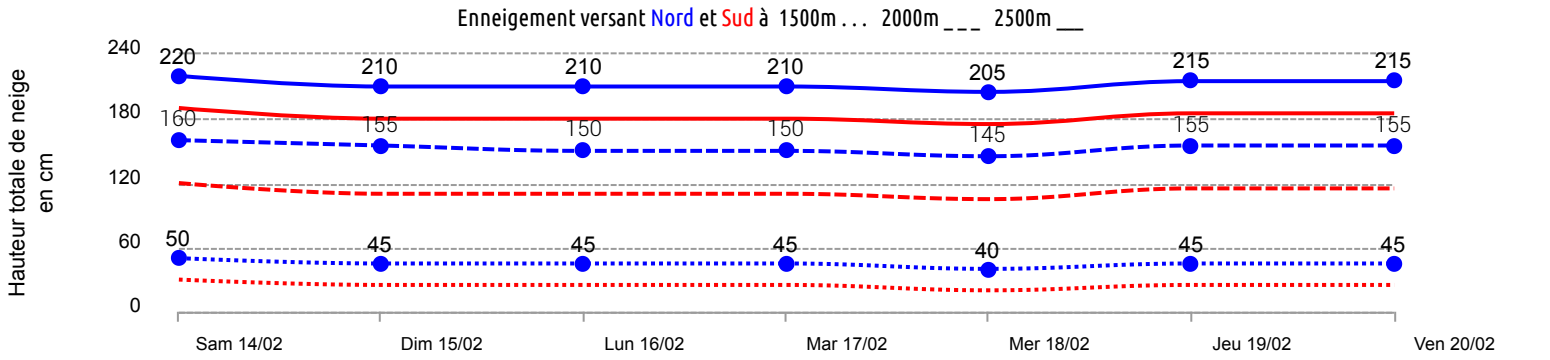

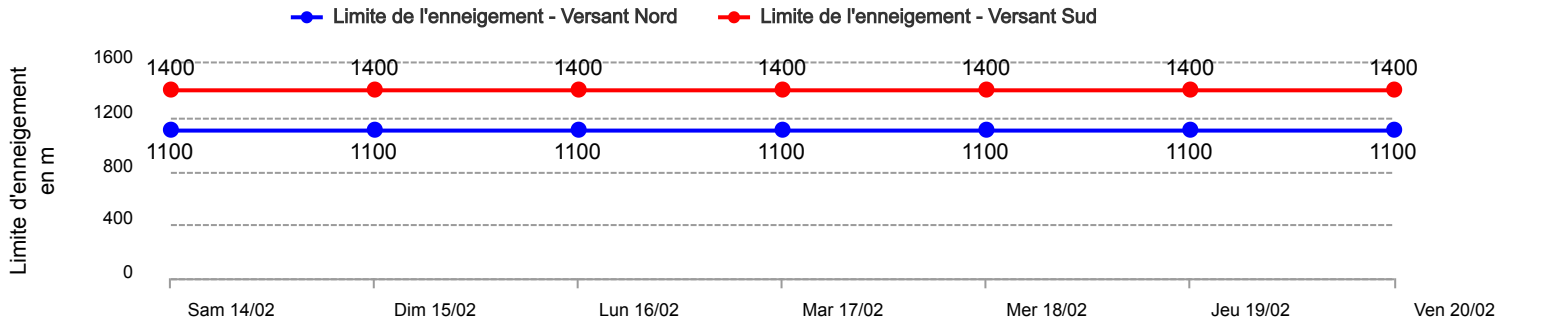

Pour consulter la vigilance en cours, veuillez vous rendre sur le site https://vigilance.meteofrance.fr/fr

Météo-France - 73 avenue de Paris, 94165 Saint-Mandé cedex - Contact : contact@meteo.fr

Bulletin neige & avalanches par téléphone au

0 892 68 10 20 Service 0,35 € / min + prix appel

Rédigé par Météo-France avec la contribution des observateurs du réseau nivo-météorologiques. Partenariat : ANMSM (Maires de Stations de Montagne), DSF (Domaines Skiables de France), ADSP (Directeurs de Pistes et de la Sécurité des Stations de Sports d'Hiver) et autres acteurs de la montagne.