Bulletin d'estimation du risque d'avalanche
(valable en dehors des pistes balisées et ouvertes)

MASSIF : Pays-Basque

Rédigé le vendredi 20 février 2026 à 16h

Estimation des risques pour le : SAMEDI 21 FÉVRIER

NEIGE RECENTE VENTEE, S'HUMIDIFIANT AU SOLEIL, LENTE EVOLUTION A L'OMBRE.

3

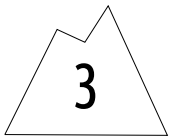

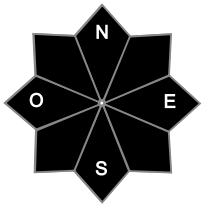

Indice de risque marqué.

Départs spontanés : en neige humide.

Déclenchements provoqués : plaques à vent.

Indices de risque : 5 très fort - 4 fort - 3 marqué - 2 limité - 1 faible -- En noir : les pentes les plus dangereuses

Stabilité du manteau neigeux

Situation avalancheuse typique : neige ventée neige humide

Déclenchements provoqués : de **nombreuses plaques à vent ou empilement de plaques sont en place en tous secteurs**, ne s'humidifiant que lentement et en surface dans les pentes ombragées, plus rapidement au soleil. Ces plaques sont **facilement déclenchables par un seul skieur ou randonneur**, engendrant des **avalanches de taille 2 à 3**, avec cassures linéaires de 10 à 30 cm possibles. Elles **ne devraient pas persister au-delà de la matinée en versants ensoleillés**, elles **résistent en versants ombragés**, sensibles à la surcharge **au-dessus de 1500/1700m en matinée, plutôt 1800/1900m l'après-midi.**

Observables : plaques facilement identifiables en versants exposés aux vents turbulents d'Ouest à Nord, un peu moins identifiables et encore d'aspect poudreux et mat dans les secteurs déventés.

Départs spontanés : risque faible à limité (1 à 2) en **pentes raides, au soleil et dans la douceur qui s'installe**. Des **coulées** (boulettes et escargots) en pentes **Est à Sud-Est le matin**, **petites avalanches** en général l'après-midi dans les pentes **Sud-Est à Sud-Ouest**. **Quelques avalanches** de taille **moyenne en cours d'après-midi** sont possibles en partant d'une **accumulation constituée sur le haut du massif** : **chute d'une corniche fragilisée au soleil**, **déclenchement des plaques décrites** ci-dessus, **plus rarement une avalanche de fond**, avec **cassures linéaires pouvant atteindre 15 à 30 cm**.

Autres : quelques **reptations possibles** et **apparition de quelques fissures** au **pied des pentes raides** ou proche des **ruptures de pentes**. Corniches en place fragilisées par l'humidification.

Qualité de la neige

Enneigement : en retrait lent ce samedi avec douceur et soleil qui s'installent, il débute vers 1200m en Nord, 1300m en Sud, mais ces limites remontent au cours de la journée. Crêtes, cols et sommets pelés en expositions Ouest, en neige dure à très dure partout ailleurs.
Limites skiables : à partir de 1300 à 1400m au petit matin suivant les versants, car sans sous-couche en dessous. La neige fond en versants ensoleillés, la limite remonte vers 1500/1600m dans la journée. Fonte plus lente à l'ombre.
État de la neige : au petit matin, neige frittée à cartonnée en versants ombragés au-dessus de 1600/1700m, neige dure et regelée partout ailleurs. La neige regelée ramollit au soleil, dans les secteurs à l'ombre, la neige très travaillée par le vent s'humidifie juste en surface sous 1800/1900m, reste en l'état au-dessus.

Aperçu météo pour le samedi 21 février

nuit	matin	après-midi	soir
800 m			

Beau temps sec et doux, vent faible. Mise en place de cycles gel/dégel du manteau neigeux.

Pluie-Neige				
Iso 0 °C	3 000 m	3 200 m	3 300 m	3 400 m
Vent 1000 m	5 km/h	0 km/h	10 km/h	10 km/h
Vent 2000 m	20 km/h	10 km/h	15 km/h	20 km/h

Épaisseur de neige hors-piste

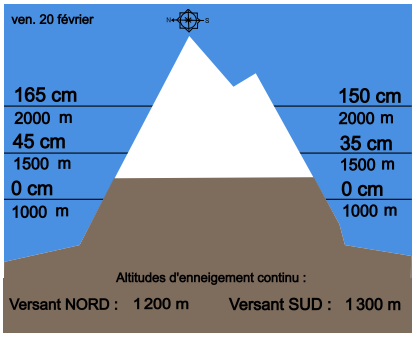

Précipitations à 1800 m

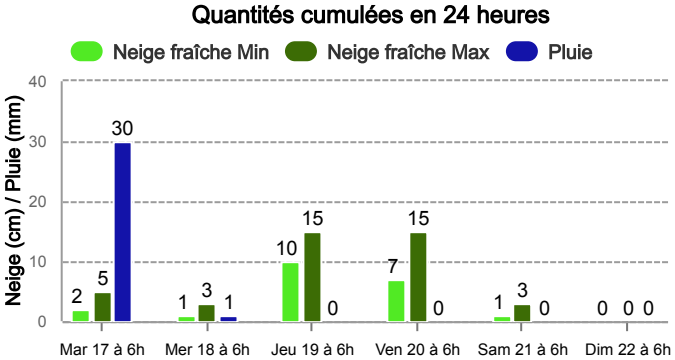

Tendance du dimanche 22 février

2

Indice de risque limité

Risque en baisse.

Pour consulter la vigilance en cours, veuillez vous rendre sur le site https://vigilance.meteofrance.fr/fr

Météo-France - 73 avenue de Paris, 94165 Saint-Mandé cedex - Contact : contact@meteo.fr

Bulletin neige & avalanches par téléphone au **0 892 68 10 20** Service 0,35 € / min + prix appel

Rédigé par Météo-France avec la contribution des observateurs du réseau nivo-météorologiques. Partenariat : ANMSM (Maires de Stations de Montagne), DSF (Domaines Skiables de France), ADSP (Directeurs de Pistes et de la Sécurité des Stations de Sports d'Hiver) et autres acteurs de la montagne.

RÉPUBLIQUE FRANÇAISE
Liberté Égalité Fraternité

METEO FRANCE
À VOS CÔTÉS, DANS UN CLIMAT QUI CHANGE

Bulletin d'estimation du risque d'avalanche

(valable en dehors des pistes balisées et ouvertes)

MASSIF : Pays-Basque

Rédigé le vendredi 20 février 2026 à 16h

Conditions nivo-météo des 7 derniers jours

	sam. 14/02				dim. 15/02				lun. 16/02				mar. 17/02				mer. 18/02				jeu. 19/02				ven. 20/02			
	03h	09h	15h	21h	03h	09h	15h	21h	03h	09h	15h	21h	03h	09h	15h	21h	03h	09h	15h	21h	03h	09h	15h	21h	03h	09h	15h	21h
Météo																												
Vent (km/h)	100	75	80	60	40	70	80	85	80	80	70	75	85	50	60	40	45	95	110	90	95	80	55	40	30	20	25	20
à 2000m	↓	↓	↘	↓	↘	↘	↘	↘	↘	↘	↘	↘	↘	→	↗	↗	↑	↑	↗	→	↘	↘	→	→	↘	↓	↓	↓
Vent (km/h)	60	40	45	25	15	15	20	25	35	35	30	35	25	15	20	10	15	40	70	50	55	40	25	15	15	10	15	10
à 1000m	↓	↓	↓	↓	↙	↘	→	↗	↗	→	↘	↓	↘	↘	↓	↑	↑	↑	↑	→	↘	↘	↘	↓	↘	↓	↓	↙

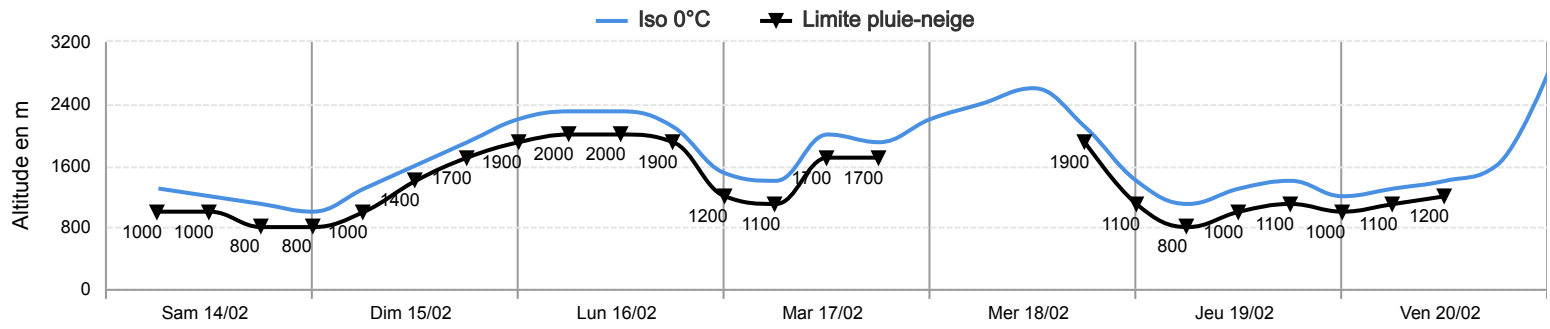

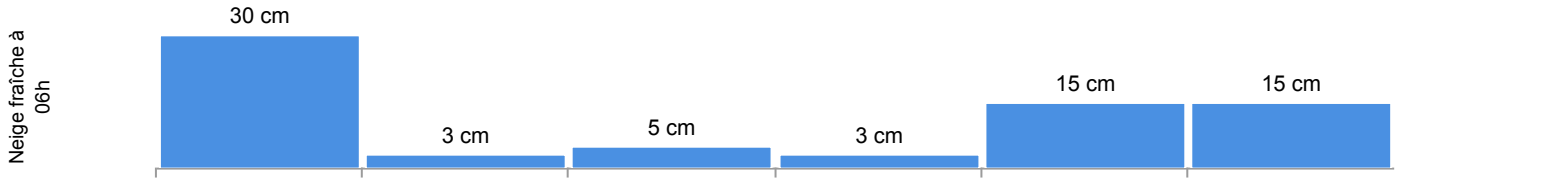

Risque d'avalanche							
	3	3	3	3	2	3	3
	sam. 14/02	dim. 15/02	lun. 16/02	mar. 17/02	mer. 18/02	jeu. 19/02	ven. 20/02

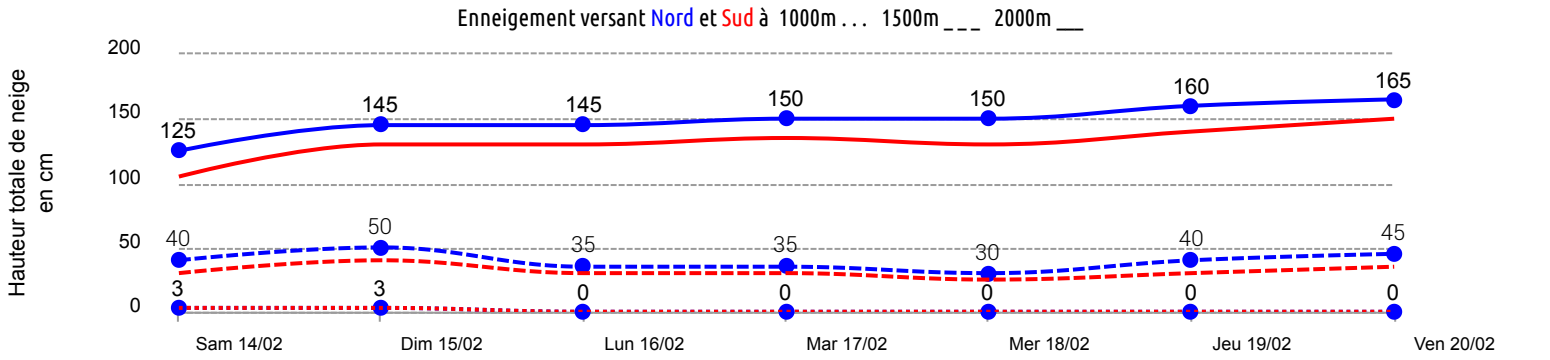

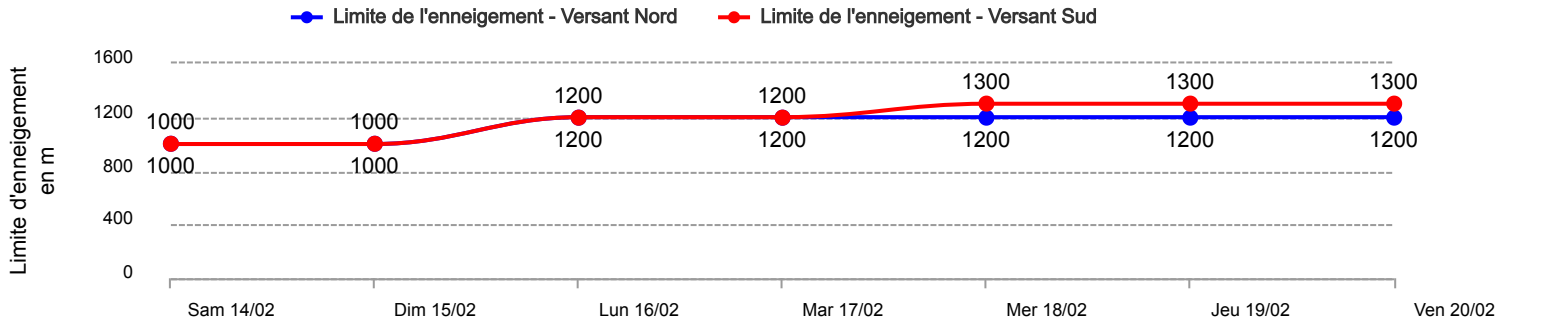

Pour consulter la vigilance en cours, veuillez vous rendre sur le site https://vigilance.meteofrance.fr/fr

Météo-France - 73 avenue de Paris, 94165 Saint-Mandé cedex - Contact : contact@meteo.fr

Rédigé par Météo-France avec la contribution des observateurs du réseau nivo-météorologiques. Partenariat : ANMSM (Maires de Stations de Montagne), DSF (Domaines Skiables de France), ADSP (Directeurs de Pistes et de la Sécurité des Stations de Sports d'Hiver) et autres acteurs de la montagne.

Bulletin neige & avalanches par téléphone au

0 892 68 10 20 Service 0,35 € / min + prix appel