Bulletin d'estimation du risque d'avalanche

(valable en dehors des pistes balisées et ouvertes)

MASSIF : Pelvoux

Rédigé le vendredi 20 février 2026 à 16h

Estimation des risques pour le : SAMEDI 21 FÉVRIER

MANTEAU NEIGEUX INSTABLE - NOMBREUSES INSTABILITÉS DANS LA NEIGE RÉCENTE VENTÉE

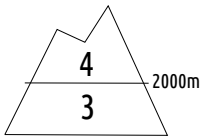

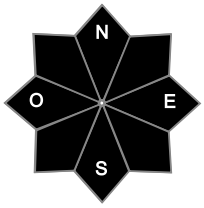

Au-dessus de 2000m indice de risque fort, plus bas indice marqué.

Départs spontanés : principalement par surcharge du au vent ou au fil de l'ensoleillement.

Déclenchements provoqués : nombreuses plaques dans la neige récente ventée, facilement déclenchables.

Indices de risque : 5 très fort - 4 fort - 3 marqué - 2 limité - 1 faible -- En noir : les pentes les plus dangereuses

Stabilité du manteau neigeux

Situation avalancheuse typique : neige ventée couche fragile persistante

Déclenchements provoqués : manteau neigeux encore peu stabilisé. Des plaques sont en place dans la neige récente ventée et d'autres en formation avec le fort vent de nord-ouest à nord en altitude ce samedi. Elles sont présentes en toutes orientations, même si plus nombreuses et sensibles au-dessus de 2000/2200 m en orientations nord-est, est et sud-est, et sont encore facilement déclenchables au passage d'un seul skieur. Dans les pentes abritées du vent, ces plaques sont encore d'aspect poudreux et donc difficilement identifiables, mais ont tendance à se stabiliser. En revanche, à proximité des crêtes et sommets, ces plaques sont plutôt durcies par le vent et réparties de manière hétérogène, avec des accumulations localement épaisses. Cassures épaisses sur de grandes largeurs, engendrant des avalanches de taille moyenne à grande (taille 2 à 3). Une très grande avalanche (taille 4) est possible en cas de sollicitation d'une couche fragile persistante enfouie en ubacs, emportant une grande partie du manteau neigeux en place. Ce type de départ peut être initié par la surcharge liée au passage d'une première avalanche de surface.

Départs spontanés : avalanches de neige récente en pentes raides ensoleillées. Avec le redoux en journée, nombreux départs superficiels attendus dans les versants les plus ensoleillés (est, sud, ouest). Avalanches de taille petite, voire de taille moyenne. Au-dessus de 2000/2200 m, départs parfois linéaires sous l'effet du fort transport par le vent de nord à nord-ouest. Avalanches de taille moyenne (taille 2) ou grande (taille 3) dans le cas de déstabilisation d'une plaque en place. Une très grande avalanche (taille 4) n'est pas exclue si une première plaque de surface vient solliciter une couche fragile plus profondément enfouie.

Qualité de la neige

L'enneigement est excédentaire pour un mois de février, notamment à basse altitude. Les chutes de neige se succèdent depuis le début du mois de janvier.
Hauteurs de neige observées : 346 cm à la Nivôse de Écrins vers 3000 m, 268 cm au Pré de Mme Carle à 1900 m, 159 cm au hameau de Dormillouse à 1730 m.

Limite d'enneigement skiable : la plupart des itinéraires sont skiables dès les fonds de vallées.

État de la neige de surface : épaisse couche de neige récente tombée entre jeudi et vendredi (localement jusqu'à 40/60 cm). Neige froide et légère dans les pentes bien abritées du vent, mais plus travaillée par le vent à proximité des crêtes et sommets. Manteau neigeux hétérogène sur les crêtes parfois décapées ou avec de grosses accumulations (corniches). Neige devenant plus lourde en dessous de 2000 m environ en ubacs, et s'humidifiant en surface jusqu'à 2500/2600 m en adrets.

Aperçu météo pour le samedi 21 février

nuit	matin	après-midi	soir

Retour du soleil avec un ciel parfois légèrement voilé. Températures en hausse et vent de nord encore fort.

Pluie-Neige				
Iso 0 °C	2 000 m	2 000 m	2 300 m	3 000 m
Vent 2000 m	55 km/h	60 km/h	60 km/h	50 km/h
Vent 3000 m	60 km/h	70 km/h	80 km/h	60 km/h

Épaisseur de neige hors-piste

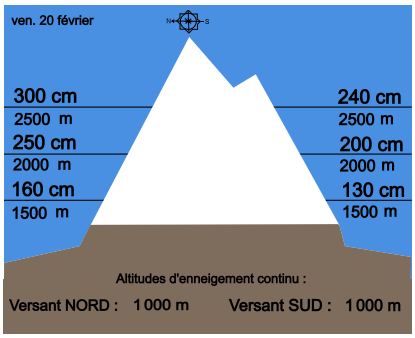

Précipitations à 1800 m

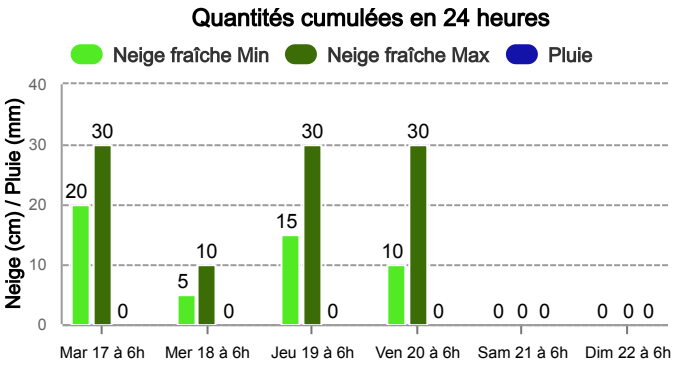

Tendance du dimanche 22 février

Indice de risque marqué

Risque en baisse, mais restant bien marqué. Des plaques sont en place et encore facilement déclenchables. Le vent faiblit, mais l'isotherme 0 degré remonte jusqu'à 3000 m. Le manteau neigeux s'humidifie progressivement.

Pour consulter la vigilance en cours, veuillez vous rendre sur le site https://vigilance.meteofrance.fr/fr

Météo-France - 73 avenue de Paris, 94165 Saint-Mandé cedex - Contact : contact@meteo.fr

Bulletin neige & avalanches par téléphone au 0 892 68 10 20 Service 0,35 € / min + prix appel

Rédigé par Météo-France avec la contribution des observateurs du réseau nivo-météorologiques. Partenariat : ANMSM (Maires de Stations de Montagne), DSF (Domaines Skiables de France), ADSP (Directeurs de Pistes et de la Sécurité des Stations de Sports d'Hiver) et autres acteurs de la montagne.

RÉPUBLIQUE FRANÇAISE
Liberté Égalité Fraternité

METEO FRANCE
À VOS CÔTÉS, DANS UN CLIMAT QUI CHANGE

Bulletin d'estimation du risque d'avalanche

(valable en dehors des pistes balisées et ouvertes)

MASSIF : Pelvoux

Rédigé le vendredi 20 février 2026 à 16h

Conditions nivo-météo des 7 derniers jours

	sam. 14/02				dim. 15/02				lun. 16/02				mar. 17/02				mer. 18/02				jeu. 19/02				ven. 20/02			
	03h	09h	15h	21h	03h	09h	15h	21h	03h	09h	15h	21h	03h	09h	15h	21h	03h	09h	15h	21h	03h	09h	15h	21h	03h	09h	15h	21h
Météo																												
Vent (km/h)	40	40	60	70	80	80	60	45	70	90	130	110	90	80	75	65	40	30	30	55	40	35	45	55	70	70	60	50
à 3000m																												
Vent (km/h)	15	15	30	45	40	35	30	25	30	60	80	70	70	55	50	30	25	15	15	30	25	20	30	35	30	60	55	50
à 2000m																												

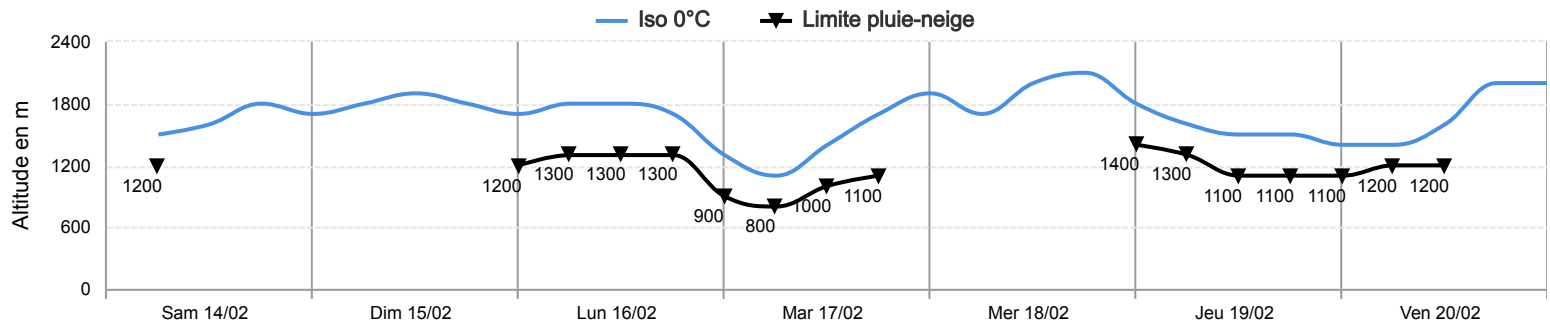

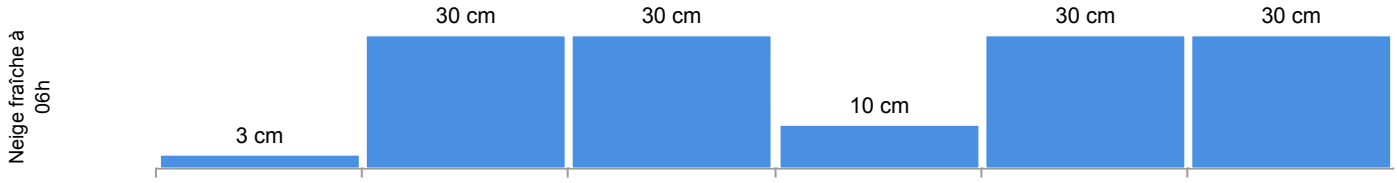

Risque d'avalanche	sam. 14/02	dim. 15/02	lun. 16/02	mar. 17/02	mer. 18/02	jeu. 19/02	ven. 20/02
	4	3	4	4	4	4	4

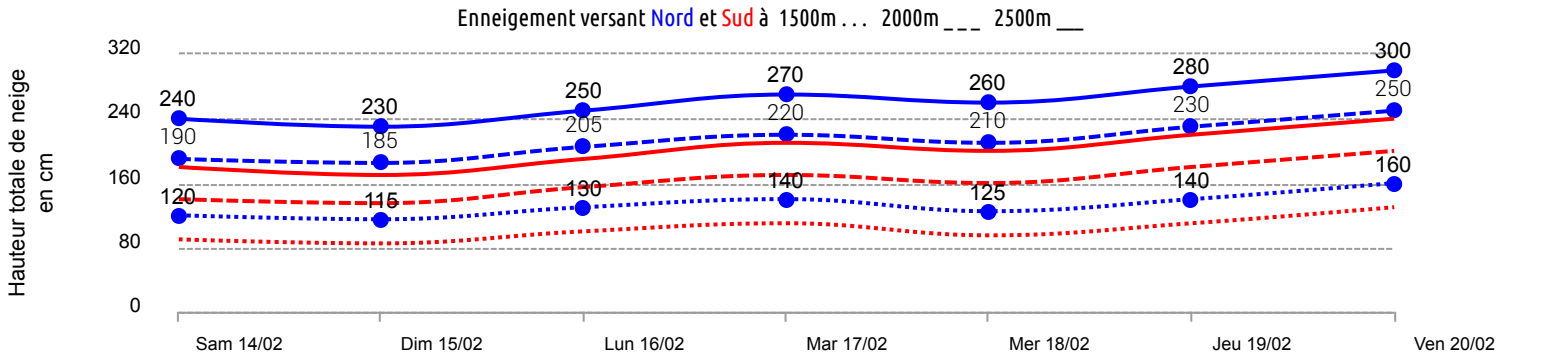

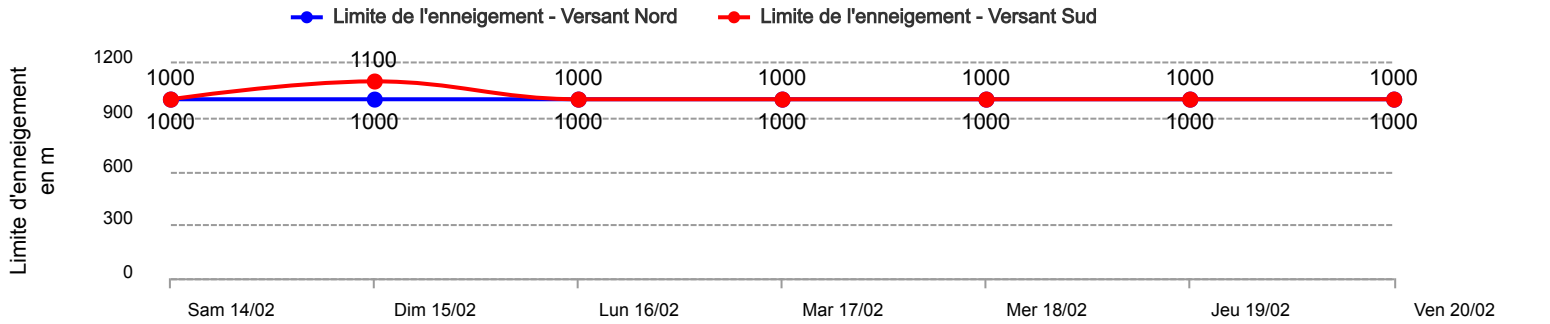

Pour consulter la vigilance en cours, veuillez vous rendre sur le site https://vigilance.meteofrance.fr/fr

Météo-France - 73 avenue de Paris, 94165 Saint-Mandé cedex - Contact : contact@meteo.fr

Rédigé par Météo-France avec la contribution des observateurs du réseau nivo-météorologiques. Partenariat : ANMSM (Maires de Stations de Montagne), DSF (Domaines Skiables de France), ADSP (Directeurs de Pistes et de la Sécurité des Stations de Sports d'Hiver) et autres acteurs de la montagne.

Bulletin neige & avalanches par téléphone au
0 892 68 10 20 Service 0,35 € / min + prix appel