RÉPUBLIQUE FRANÇAISE
Liberté Égalité Fraternité

METEO FRANCE
À VOS CÔTÉS, DANS UN CLIMAT QUI CHANGE

Bulletin d'estimation du risque d'avalanche
(valable en dehors des pistes balisées et ouvertes)
MASSIF : Cerdagne Canigou

Rédigé le vendredi 20 février 2026 à 17h

Estimation des risques pour le : SAMEDI 21 FÉVRIER

PERSISTANCE DE STRUCTURES DE PLAQUES EN ALTITUDE

3

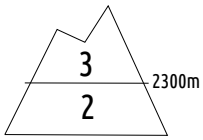

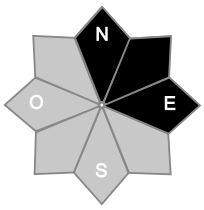

Au-dessus de 2300m indice de risque marqué, plus bas indice limité.

Départs spontanés : Coulées de surface

Déclenchements provoqués : Plaques à vent

Indices de risque : 5 très fort - 4 fort - 3 marqué - 2 limité - 1 faible -- En noir : les pentes les plus dangereuses

Stabilité du manteau neigeux

Situation avalancheuse typique : neige ventée

Déclenchements provoqués :
En altitude, au-dessus de 2200 à 2400m en général, des structures de plaques souvent dures, mais parfois friables, se sont formées ces derniers jours sous le vent d'ouest à nord-ouest. Elles sont surtout présentes dans un large secteur nord à est et pourront conduire à des avalanches de moyenne taille. Les nouvelles chutes de neige attendues sont faibles, mais le vent associé pourra favoriser la formation de nouvelles structures friables pouvant céder facilement au passage d'un pratiquant.
Observables : zone d'accumulations, neige travaillée par le vent en surface.

Départs spontanés :
Dans les secteurs ensoleillés au-dessus de 2000m, des départs spontanés ponctuels en **neige humide** sont à attendre à cause de l'intensification de l'humidification du manteau neigeux, causée par le redoux et le très bon ensoleillement de ce samedi. Des avalanches de taille moyenne sont à attendre. Dans les autres secteurs, de rares avalanches de taille moyenne sont possibles au cours de la journée.

Qualité de la neige

Enneigement :
L'enneigement reste largement supérieur à celui des cinq dernières années et se situe à un niveau remarquable par rapport aux statistiques plus anciennes. L'enneigement débute vers 1500m et devient rapidement conséquent avec l'altitude. La barre des 2m de neige est souvent atteinte dès 2000m d'altitude.

État de la neige :
Manteau compact de type printanier jusqu'à 2200m en versant nord et souvent jusqu'aux sommets en versants ensoleillés.
À partir de 2200m, on pourra trouver un peu plus de neige froide et sèche dans les vallons et secteurs abrités du vent, une neige très travaillée par le vent ailleurs. Les crêtes et sommets peuvent se retrouver décapés par le vent violent.

Aperçu météo pour le samedi 21 février

	nuit	matin	après-midi	soir
Grand beau				
Pluie-Neige				
Iso 0 °C	2 600 m	3 000 m	3 100 m	3 200 m
Vent 2000 m	25 km/h	20 km/h	20 km/h	15 km/h
Vent 3000 m	45 km/h	35 km/h	30 km/h	25 km/h

Épaisseur de neige hors-piste

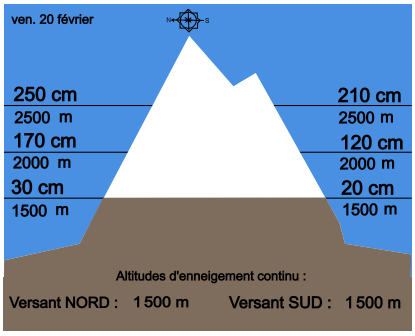

Précipitations à 1800 m

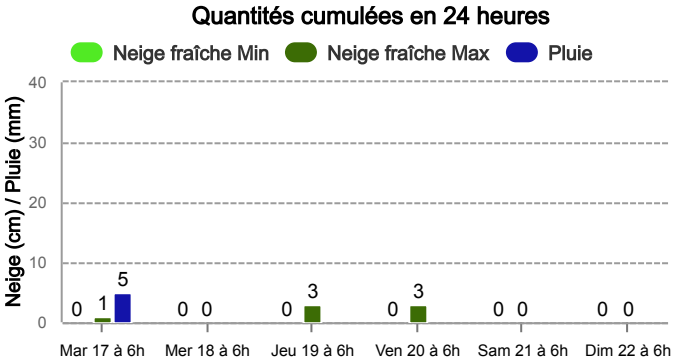

Tendance du dimanche 22 février

3 **Indice de risque marqué**

Le risque de déclenchement provoqué devrait très progressivement diminuer avec la stabilisation du manteau neigeux, favorisée par la douceur.

Pour consulter la vigilance en cours, veuillez vous rendre sur le site https://vigilance.meteofrance.fr/fr

Météo-France - 73 avenue de Paris, 94165 Saint-Mandé cedex - Contact : contact@meteo.fr

Rédigé par Météo-France avec la contribution des observateurs du réseau nivo-météorologiques. Partenariat : ANMSM (Maires de Stations de Montagne), DSF (Domaines Skiables de France), ADSP (Directeurs de Pistes et de la Sécurité des Stations de Sports d'Hiver) et autres acteurs de la montagne.

Bulletin neige & avalanches par téléphone au
0 892 68 10 20 Service 0,35 € / min + prix appel

RÉPUBLIQUE FRANÇAISE
Liberté Égalité Fraternité

METEO FRANCE
À VOS CÔTÉS, DANS UN CLIMAT QUI CHANGE

Bulletin d'estimation du risque d'avalanche

(valable en dehors des pistes balisées et ouvertes)

MASSIF : Cerdagne Canigou

Rédigé le vendredi 20 février 2026 à 17h

Conditions nivo-météo des 7 derniers jours

	sam. 14/02				dim. 15/02				lun. 16/02				mar. 17/02				mer. 18/02				jeu. 19/02				ven. 20/02			
	03h	09h	15h	21h	03h	09h	15h	21h	03h	09h	15h	21h	03h	09h	15h	21h	03h	09h	15h	21h	03h	09h	15h	21h	03h	09h	15h	21h
Météo																												
Vent (km/h)	90	90	100	100	95	60	65	65	95	100	105	120	120	110	90	75	65	55	70	80	80	70	70	75	65	65	55	50
à 3000m	↓	↓	↘	↘	↘	↓	↘	→	↘	↘	↘	↘	↘	↘	↘	↘	→	↗	↗	↗	↘	↓	↓	↓	↓	↓	↓	↓
Vent (km/h)	70	70	80	80	60	40	35	40	50	65	80	85	85	65	50	40	30	25	35	50	75	60	60	65	60	60	40	30
à 2000m	↘	↘	↘	↘	↘	↘	↘	↘	↘	↘	↘	↘	↘	↘	↘	→	→	↗	↗	↗	↘	↓	↓	↓	↓	↓	↓	↓

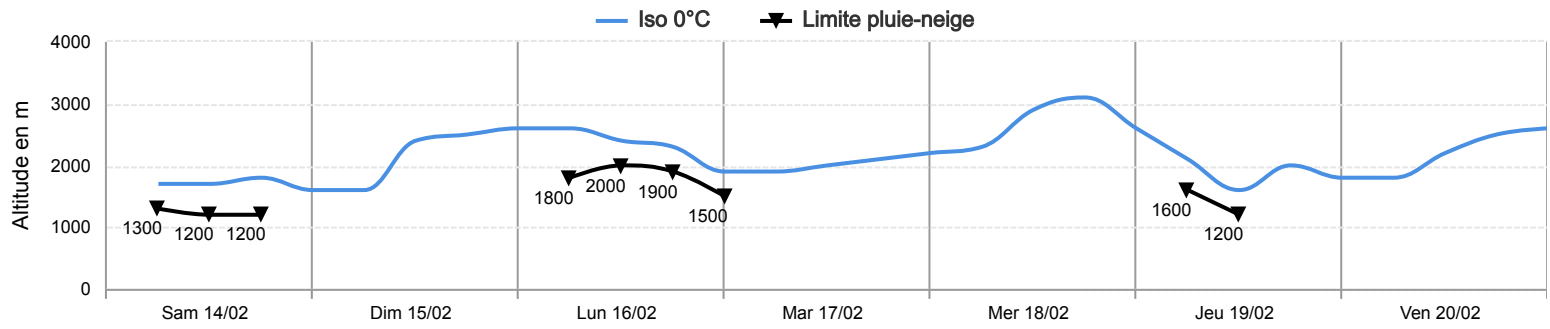

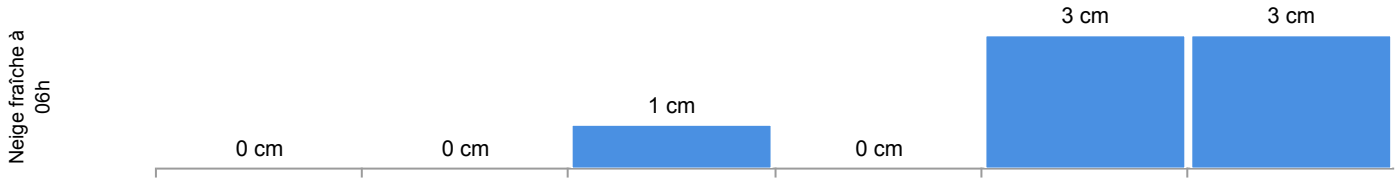

Risque d'avalanche	sam. 14/02	dim. 15/02	lun. 16/02	mar. 17/02	mer. 18/02	jeu. 19/02	ven. 20/02
	2	3	3	3	3	3	3

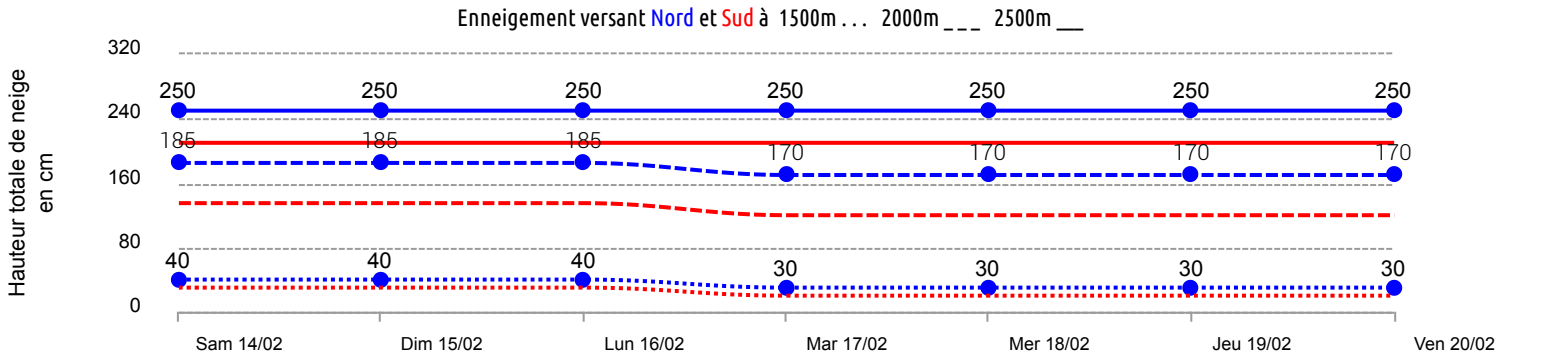

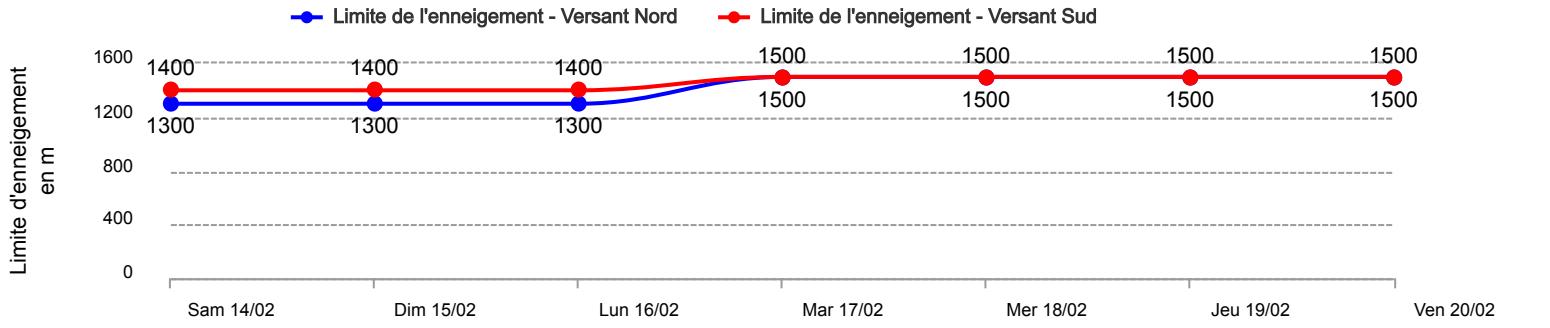

Pour consulter la vigilance en cours, veuillez vous rendre sur le site https://vigilance.meteofrance.fr/fr

Météo-France - 73 avenue de Paris, 94165 Saint-Mandé cedex - Contact : contact@meteo.fr

Rédigé par Météo-France avec la contribution des observateurs du réseau nivo-météorologiques. Partenariat : ANMSM (Maires de Stations de Montagne), DSF (Domaines Skiables de France), ADSP (Directeurs de Pistes et de la Sécurité des Stations de Sports d'Hiver) et autres acteurs de la montagne.

Bulletin neige & avalanches par téléphone au
0 892 68 10 20 Service 0,35 € / min + prix appel