Bulletin d'estimation du risque d'avalanche
(valable en dehors des pistes balisées et ouvertes)

MASSIF : Haute-Ariege

Rédigé le vendredi 20 février 2026 à 17h

Estimation des risques pour le : SAMEDI 21 FÉVRIER

PRÉSENCE DE PLAQUES À VENT, SURTOUT EN ALTITUDE

3

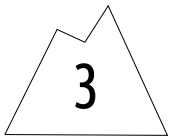

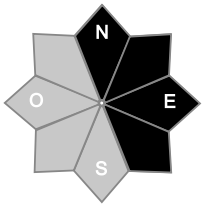

Indice de risque marqué.

Départs spontanés : en neige humide

Déclenchements provoqués : instabilités en neige récente ventée

Indices de risque : 5 très fort - 4 fort - 3 marqué - 2 limité - 1 faible -- En noir : les pentes les plus dangereuses

Stabilité du manteau neigeux

Situation avalancheuse typique : neige ventée neige humide

Déclenchements provoqués : Dans les secteurs où la neige reste froide (pentes ombragées ou même au soleil à haute altitude), des avalanches de **plaques** dans la neige récente sont **facilement déclenchables** par un pratiquant. En effet, de **nombreuses plaques** parfois friables et **difficilement détectables,** parfois un peu plus dures selon le travail du vent, se sont formées ces derniers jours sous l'effet d'un vent turbulent ayant soufflé parfois très fort **à toutes altitudes.** Des cassures typiques de quelques dizaines de centimètres sont à attendre, mais localement des cassures plus grandes sont possibles dans les zones de plus forte accumulation notamment dans un vaste secteur nord à sud-est. Facteur aggravant : au-dessus de 2200m, des grains anguleux ont pu se former localement les jours précédents et se retrouver enfouis sous la neige récente.
Observables : Fissures devant les skis, "whoomfs" au passage d'un pratiquant. Les plaques friables restent toutefois difficilement détectables, car d'aspect poudreux.

Départs spontanés :
Dans les secteurs ensoleillés au-dessus de 2000m, des départs spontanés ponctuels en **neige humide** sont à attendre à cause de l'intensification de l'humidification de la couche de neige récente causée par le redoux et le très bon ensoleillement de ce samedi. Des avalanches de taille moyenne sont à attendre. Dans les autres secteurs, quelques avalanches de taille moyenne sont possibles au cours de la journée. On peut noter que les importantes corniches présentes en bon nombre d'endroits sont susceptibles d'être fragilisées par l'humidification et chuter, et possiblement provoquer un départ d'avalanche, éventuellement en cassure linéaire en mobilisant les plaques évoquées plus haut.

Qualité de la neige

Enneigement :
A la faveur des multiples passages perturbés qui se sont succédé depuis le début de l'année, l'enneigement est largement supérieur à celui des cinq dernières années et se situe à un très bon niveau par rapport aux statistiques plus anciennes. La barre des 2m de neige est souvent atteinte dès 2000m d'altitude.

Qualité de la neige :
Une couche de neige récente, souvent travaillée par le vent, devrait être encore présente au matin dès 1200/1300m. Cette neige pourrait avoir un aspect regelé par une possible humidification jusque vers 2000m en soirée avant les belles éclaircies nocturnes. Elle va rapidement fondre au soleil en journée aux plus basses altitudes, plus lentement à l'ombre. Cette neige repose sur un manteau compacté soit par la pluie du début de semaine jusqu'à 2200m soit par le vent. Les crêtes et sommets peuvent se retrouver décapés par le vent violent.
En journée, on trouvera un tableau classique, à savoir des conditions de neige de printemps dans un vaste secteur sud et une neige qui reste poudreuse ou tassée par le vent dans les secteurs ombragés.

Aperçu météo pour le samedi 21 février

	nuit	matin	après-midi	soir
Grand beau				
Pluie-Neige				
Iso 0 °C	1 900 m	3 000 m	3 100 m	3 200 m
Vent 2000 m	25 km/h	20 km/h	20 km/h	15 km/h
Vent 3000 m	45 km/h	35 km/h	30 km/h	25 km/h

Épaisseur de neige hors-piste

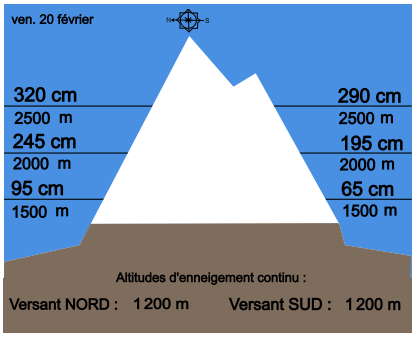

Précipitations à 1800 m

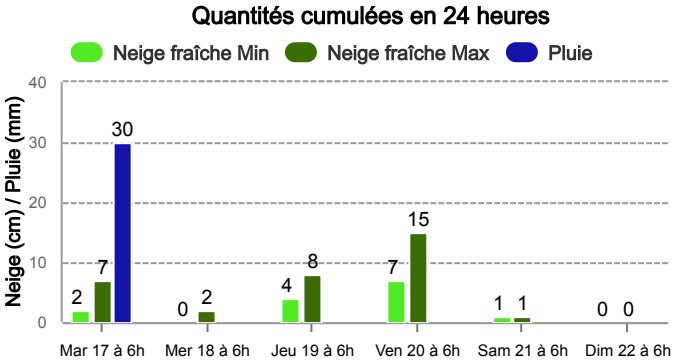

Tendance du dimanche 22 février

3 **Indice de risque marqué**

Le risque devrait très progressivement diminuer avec la stabilisation du manteau neigeux, favorisée par la douceur.

Pour consulter la vigilance en cours, veuillez vous rendre sur le site https://vigilance.meteofrance.fr/fr

Météo-France - 73 avenue de Paris, 94165 Saint-Mandé cedex - Contact : contact@meteo.fr

Rédigé par Météo-France avec la contribution des observateurs du réseau nivo-météorologiques. Partenariat : ANMSM (Maires de Stations de Montagne), DSF (Domaines Skiables de France), ADSP (Directeurs de Pistes et de la Sécurité des Stations de Sports d'Hiver) et autres acteurs de la montagne.

Bulletin neige & avalanches par téléphone au **0 892 68 10 20** Service 0,35 € / min + prix appel

RÉPUBLIQUE FRANÇAISE
Liberté Égalité Fraternité

METEO FRANCE
À VOS CÔTÉS, DANS UN CLIMAT QUI CHANGE

Bulletin d'estimation du risque d'avalanche

(valable en dehors des pistes balisées et ouvertes)

MASSIF : Haute-Ariege

Rédigé le vendredi 20 février 2026 à 17h

Conditions nivo-météo des 7 derniers jours

	sam. 14/02				dim. 15/02				lun. 16/02				mar. 17/02				mer. 18/02				jeu. 19/02				ven. 20/02			
	03h	09h	15h	21h	03h	09h	15h	21h	03h	09h	15h	21h	03h	09h	15h	21h	03h	09h	15h	21h	03h	09h	15h	21h	03h	09h	15h	21h
Météo																												
Vent (km/h)	90	90	90	80	90	60	50	50	65	75	80	90	90	75	50	40	40	55	65	65	80	70	70	75	65	65	55	50
à 3000m																												
Vent (km/h)	70	65	70	60	55	35	30	35	40	60	70	75	70	45	35	25	15	25	50	45	50	45	45	40	35	35	30	30
à 2000m																												

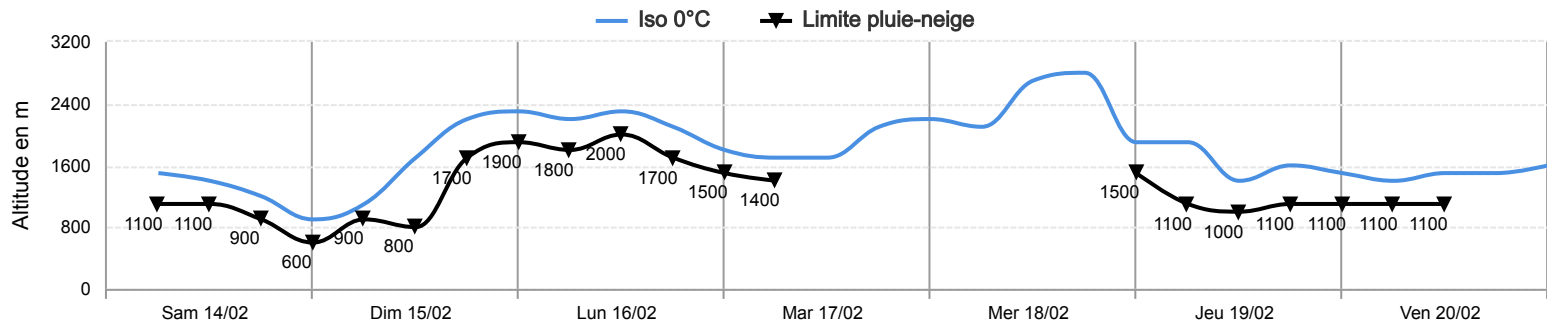

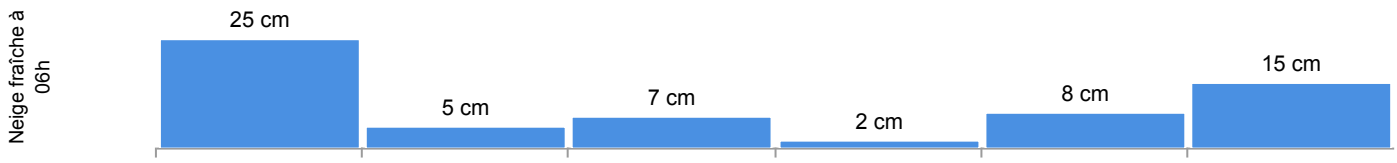

Risque d'avalanche	sam. 14/02	dim. 15/02	lun. 16/02	mar. 17/02	mer. 18/02	jeu. 19/02	ven. 20/02
	3	4	4	4	3	3	3

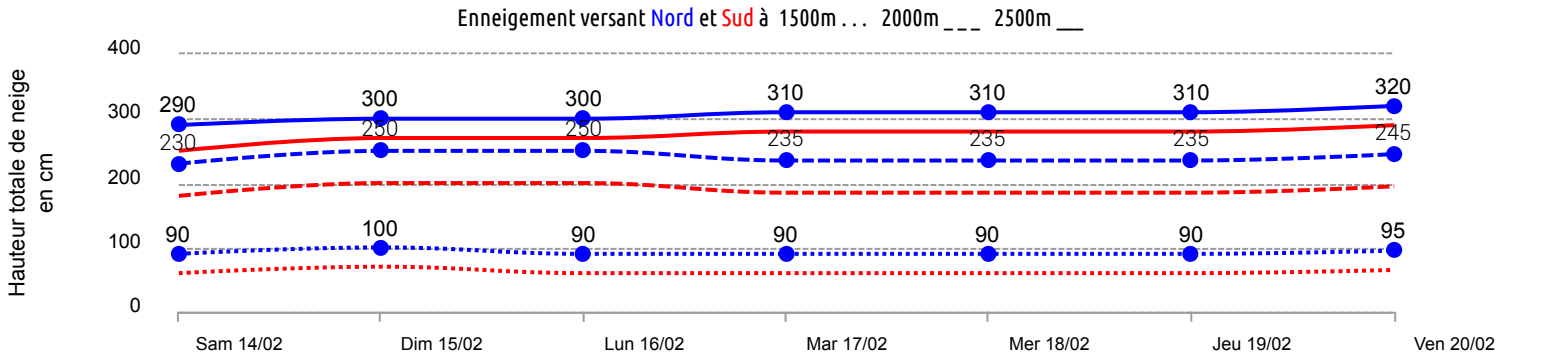

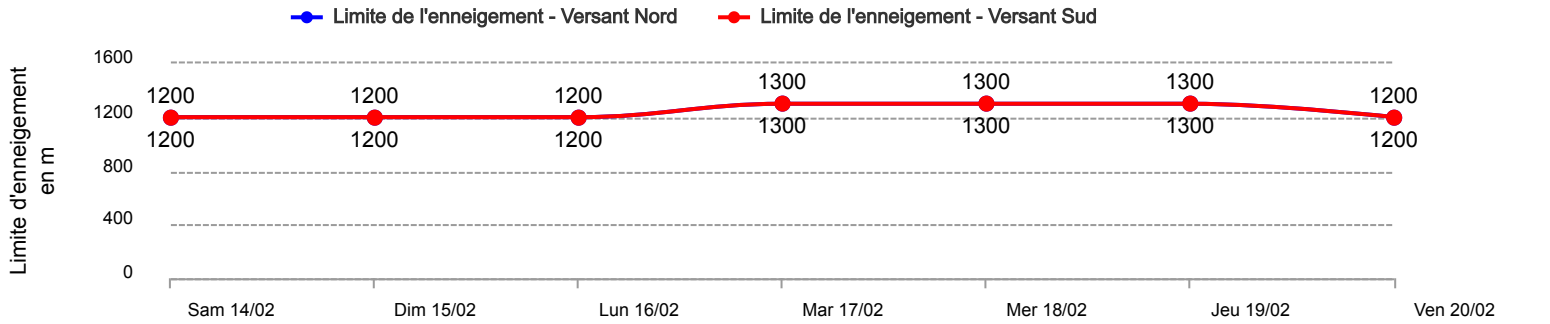

Pour consulter la vigilance en cours, veuillez vous rendre sur le site https://vigilance.meteofrance.fr/fr

Météo-France - 73 avenue de Paris, 94165 Saint-Mandé cedex - Contact : contact@meteo.fr

Rédigé par Météo-France avec la contribution des observateurs du réseau nivo-météorologiques. Partenariat : ANMSM (Maires de Stations de Montagne), DSF (Domaines Skiables de France), ADSP (Directeurs de Pistes et de la Sécurité des Stations de Sports d'Hiver) et autres acteurs de la montagne.

Bulletin neige & avalanches par téléphone au

0 892 68 10 20 Service 0,35 € / min + prix appel