GOBIERNO DE ESPAÑA
VICEPRESIDENCIA TERCERA DEL GOBIERNO
MINISTERIO PARA LA TRANSICIÓN ECOLÓGICA Y EL RETO DEMOGRÁFICO

Boletín de información nivológica y de peligro de aludes

Pirineo Navarro y Aragonés

aemet Agencia Estatal de Meteorología

sábado, 21 de febrero de 2026

Pronóstico hasta las 24 horas del domingo, día 22 de febrero

(Válido fuera de pistas de esquí balizadas y abiertas)

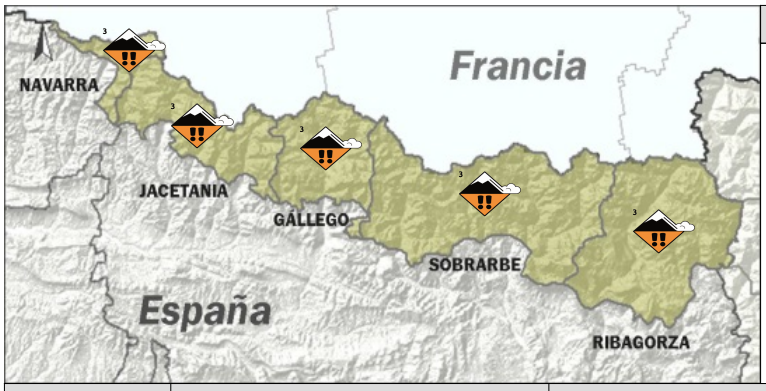

Problemas de aludes

Placas de viento

Nieve húmeda

Macizo	Peligro	Problemas de aludes, cota, orientación, tamaño	Innivación observada (m)
Navarra	3 3 / 2→3 / 2300 Durante el día **Notable**	**Placas de viento** 2300 / N O E S / 2 **Nieve húmeda** N O E S / 2	2026-02-21 N S Cotas bajas
Jacetania	3 3 / 2→3 / 2300 Durante el día **Notable**	**Placas de viento** 2300 / N O E S / 2 **Nieve húmeda** N O E S / 2	2026-02-21 N S Cotas bajas
Gállego	3 3 / 2→3 / 2300 Durante el día **Notable**	**Placas de viento** 2300 / N O E S / 2 **Nieve húmeda** N O E S / 2	2026-02-21 N S Cotas bajas

Sobrarbe	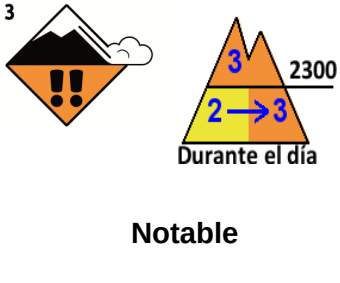 **Notable**	**Placas de viento** **Nieve húmeda** 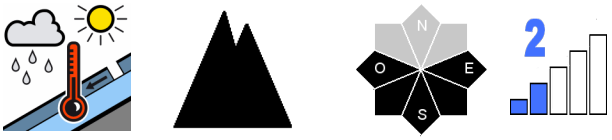	2026-02-21
Ribagorza	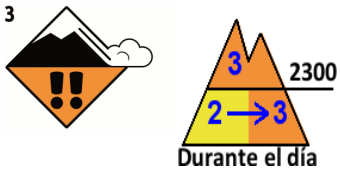 **Notable**	**Placas de viento** **Nieve húmeda** 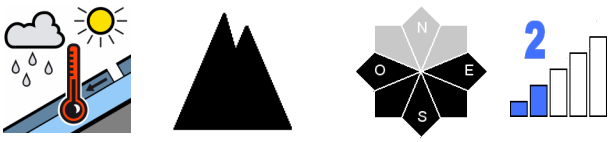	2026-02-21

Estado del manto y observaciones recientes

Ayer viernes de madrugada se daban las últimas nevadas débiles del pasado episodio, junto con vientos fuertes o muy fuertes que produjeron ventiscas y nuevas placas de viento durante gran parte del día. Tras éste, se ha producido un cambio brusco del ambiente, con la entrada de un potente anticiclón que está propiciando un notable aumento de la insolación y las temperaturas durante este fin de semana.

El manto es continuo desde fondos de valle y presenta espesores muy por encima de lo que sería habitual a estas alturas de la temporada. En general es esquiable a partir de 1500 metros en las solanas y desde fondo de valle en umbrías. Por encima de 2100 metros se superan fácilmente los 150-200 cm, aún más en ventisqueros, hoyas y otras zonas propensas a la acumulación.

El manto se ha ido humidificando significativamente y, salvo en algunas umbrías de cotas altas, hay presencia de costras debido al ciclo de fusión diurno y rehielo nocturno, y en la mayoría de casos no llegan a hundirse. En zonas expuestas al viento, sobretodo en orientaciones norte y oeste de cotas medias y altas la nieve está muy erosionada, con zonas peladas. Por contra, en zonas de acumulación la nieve está venteada y con presencia de placas de viento en proceso de estabilización, más lento en las umbrías de cotas altas donde además éstas pueden reposar sobre una capa débil enterrada de facetas formada el 14 de febrero. Otras capas débiles persistentes pueden seguir latentes aunque se espera que alguna pueda ir evolucionando con el débil gradiente térmico de estos días.

En un test realizado ayer en Góriz a 2200m, orientación SE, fracturó una capa débil a 40cm de profundidad ante esfuerzo difícil con propagación. Otro test realizado hoy en Cap de LLauset a 2500m, orientación E, ha presentado fractura fácil a 15cm de profundidad pero sin propagación.

AEMET. Se autoriza la reproducción de su contenido citando la fuente.

En las últimas 24 horas se han reportado coladas de nieve húmeda, además de algunos aludes de fondo y dos de placa, en su mayoría de tamaños medianos, raramente grandes, y en orientaciones norte y este con altitudes de salida de entre 2000 y 2500 metros.

Evolución del manto y peligro de aludes para el domingo, día 22

Problema de nieve húmeda. Problema de placas de viento en cotas altas.

Mañana domingo continuará el acusado ascenso térmico y la insolación, por ello el peligro ascenderá a partir del mediodía, cuando serán más frecuentes los aludes de nieve húmeda, con mayor probabilidad en las solanas. Por lo general serán de tamaño 1 (pequeño, riesgo de caída) o 2 (mediano, capaz de enterrar a una persona), o localmente 3 (grande, capaz de enterrar a un grupo de personas). No se descarta que puedan producirse aludes de fondo en pendientes propensas de terreno herboso o de roca lisa.

En cotas altas por encima de 2300 metros aún podrán ser reactivas las placas de viento, con preferencia en orientaciones norte, este y sur, pudiendo colapsar ante una sobrecarga débil (paso de un solo esquiador) ocasionando aludes de dimensión 1 o 2, localmente 3. Además, es posible que en umbrías de cotas altas por encima de 2500 metros estas sobrecargas puedan fracturar la capa débil de facetas del 14 de febrero, o excepcionalmente alguna capa débil persistente más antigua, y que en el peor de los casos podrían desencadenar un alud de dimensiones aún mayores.

Predicción meteorológica para el domingo, día 22

Cielos despejados o con velos de nubes altas. Temperaturas mínimas en ascenso y máximas con pocos cambios. Alguna helada débil en cumbres. Viento flojo de componente oeste, moderado en cotas altas.

Datos en la atmósfera libre:

Altitud de la isoterma de 0 ºC: 3500 m
Altitud de la isoterma de -10 ºC: 5000 m

Viento a 1500 m: NW 10 km/h
Viento a 3000 m: W 30 km/h

Evolución para el lunes día 23

Disminución del problema de placas de viento y continuación del problema de nieve húmeda. Peligro sin cambios o en ligero descenso.

(Información elaborada a partir de los datos recibidos de los refugios de Linza, Lizara, Panticosa, Bachimaña, Góriz, Pineta, Estós, Angel Orús, La Renclusa, Cap de Llauset y Belagua, de las estaciones de esquí de Candanchú, Astún, Formigal y Panticosa (lagos), de la estación de esquí de fondo de Llanos del Hospital y de Ordesa Pradera)

Escala europea de peligro de aludes

Débil | Limitado | Notable | Fuerte | Muy Fuerte

Problemas de aludes

Nieve reciente | Placas de viento | Capas débiles persistentes | Nieve húmeda | Deslizamientos basales | Sin problema evidente

AEMET. Se autoriza la reproducción de su contenido citando la fuente.

Nota1: Se recuerda que, siempre que haya nieve, la ausencia total de peligro no existe. Hay que tener presente que en circunstancias desfavorables, con aludes de tamaño 1 (alud pequeño o colada) y tamaño 2 (alud mediano), se pueden sufrir severos daños personales.

Nota2: Los BPA se elaboran en base a información meteorológica así como al estado del manto nivoso a través de sondeos puntuales. Se advierte a los usuarios de la variabilidad de esta información al extrapolarla a zonas extensas de montaña. Por ello, AEMET no se hace responsable de su uso para la toma de decisiones que conciernen a la seguridad personal, ni de los riesgos físicos o materiales de ellas derivadas.

AEMET. Se autoriza la reproducción de su contenido citando la fuente.