Sonntag 22.02.2026

Veröffentlicht am 21.02.2026 um 17:00

Vormittag

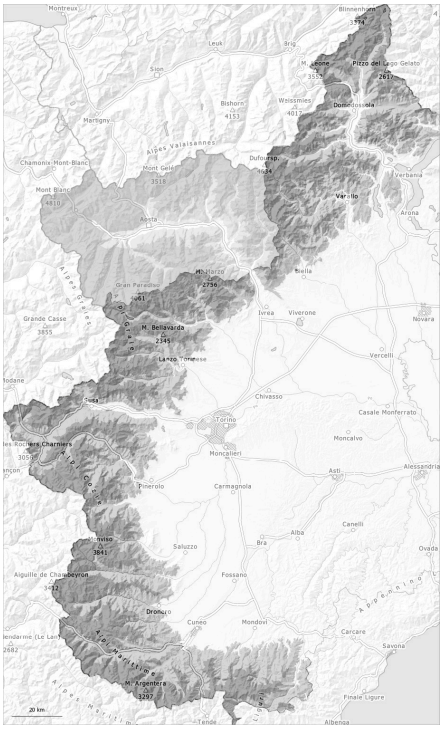

Nachmittag

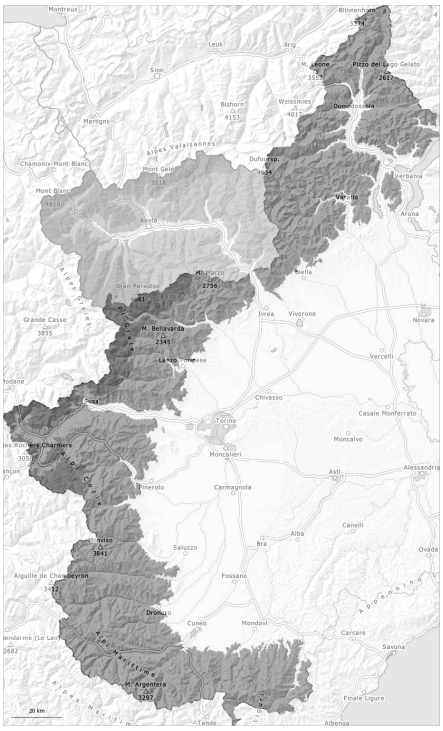

1	2	3	4	5
gering	mäßig	erheblich	groß	sehr groß

Gefahrenstufe 4 - Groß

AM:

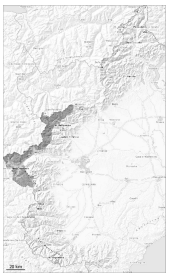

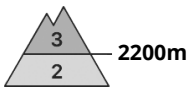

Tendenz: Lawinengefahr nimmt ab
am Montag, den 23.02.2026

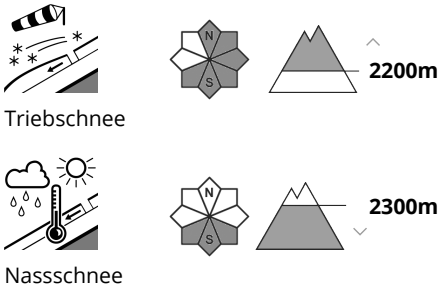

PM:

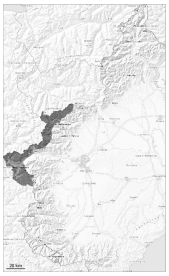

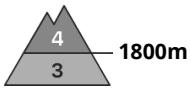

Tendenz: Lawinengefahr nimmt ab
am Montag, den 23.02.2026

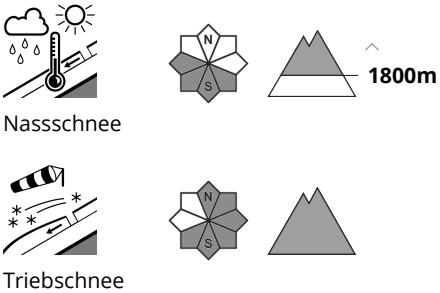

Triebschnee und Nassschnee vorsichtig beurteilen. Vor allem aber nimmt die Gefahr von feuchten und nassen Lawinen ab dem Morgen zu.

Triebschneeansammlungen können von einzelnen Wintersportlern ausgelöst werden und vereinzelt groß werden.
Entlang der Grenze zu Frankreich sind die Gefahrenstellen häufiger und die Gefahr höher.

Markante Erwärmung: An steilen Sonnenhängen und an Felswandfüßen steigt die Auslösebereitschaft von trockenen und nassen Lawinen im Tagesverlauf an. Die Lawinen können in den typischen Lawinenzügen weiterhin ziemlich groß werden.
Die Spitze der Lawinenaktivität wird voraussichtlich im Tagesverlauf erreicht, in tiefen und mittleren Lagen schon am Vormittag.

Schneedecke

Gefahrenmuster gm.6: lockerer schnee und wind | gm.10: frühjahrssituation

Dort liegt für die Jahreszeit viel Schnee. Seit Montag fielen gebietsweise oberhalb von rund 1800 m 70 bis 120 cm Schnee, lokal auch mehr.
Mit Schneefall und teils stürmischem Nordwestwind entstanden in den letzten Tagen

Triebschneeansammlungen. Dies vor allem in den Föhngebieten oberhalb der Waldgrenze und in Kammlagen, Rinnen und Mulden.
In Gipfellagen liegen je nach Windeinfluss sehr unterschiedliche Schneehöhen.
Der Neuschnee der letzten Woche liegt oberhalb der Waldgrenze teilweise auf Oberflächenreif.
Verschiedene Triebschneeschichten liegen stellenweise auf einer weichen Altschneeoberfläche.
Sonnenhänge unterhalb von rund 2500 m: Die Sonneneinstrahlung führt im Tagesverlauf zu einer zunehmenden Anfeuchtung der Schneedecke.

Tendenz

Es ist mild. Die Gefahr von trockenen und feuchten Lawinen steigt im Tagesverlauf etwas an. In diesen Gebieten wurde die Spitze der Lawinenaktivität bereits überschritten.

Gefahrenstufe 3 - Erheblich

AM:

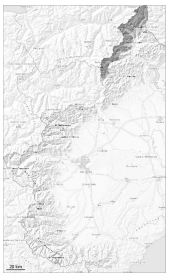

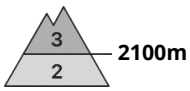

Tendenz: Lawinengefahr bleibt gleich
am Montag, den 23.02.2026

Triebschnee

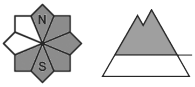

Nassschnee

PM:

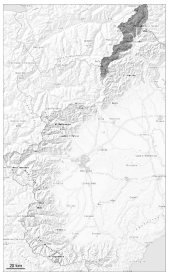

Tendenz: Lawinengefahr bleibt gleich
am Montag, den 23.02.2026

Triebschnee

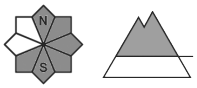

Nassschnee

Frischen und älteren Triebschnee vorsichtig beurteilen. Die Gefahr von feuchten und nassen Lawinen steigt im Tagesverlauf rasch an.

Die Triebschneeansammlungen der letzten Woche können schon von einzelnen Wintersportlern ausgelöst werden. In Rinnen, Mulden und hinter Geländekanten und oberhalb der Waldgrenze sind Schneebrettlawinen möglich, vereinzelt auch große.

Tagesverlauf: Im felsdurchsetzten Steilgelände und aus noch nicht entladenen Einzugsgebieten sind mit der Erwärmung mittlere und große feuchte und nasse Lawinen möglich.

Schneedecke

Gefahrenmuster gm.6: lockerer schnee und wind | gm.10: frühjahrssituation

Mit Schneefall und teils stürmischem Nordwestwind entstanden in den letzten Tagen frische Triebschneeansammlungen. Dies vor allem in den Föhngebieten oberhalb der Waldgrenze sowie in Rinnen, Mulden und hinter Geländekanten.
Der Föhn hat viel Schnee verfrachtet.
In Kamm- und Passlagen liegen je nach Windeinfluss sehr unterschiedliche Schneehöhen.
In der Altschneedecke sind vor allem an steilen Nordwest-, Nord- und Osthängen störanfällige

Schwachschichten vorhanden.
Verschiedene Triebschneeschichten liegen stellenweise auf grobkörnigem Altschnee.

Tendenz

Es ist mild. Mittag und Nachmittag: Allmählicher Anstieg der Gefahr von trockenen und feuchten Lawinen mit der tageszeitlichen Erwärmung und der Sonneneinstrahlung.

Gefahrenstufe 3 - Erheblich

AM:

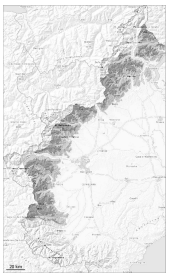

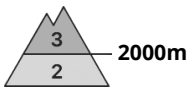

Tendenz: Lawinengefahr bleibt gleich
am Montag, den 23.02.2026

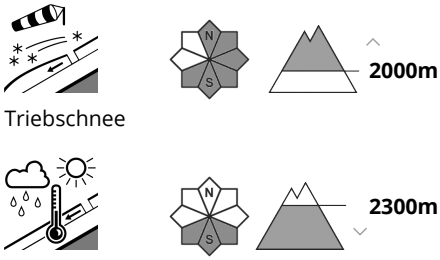

PM:

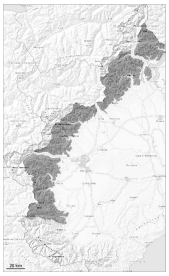

Tendenz: Lawinengefahr bleibt gleich
am Montag, den 23.02.2026

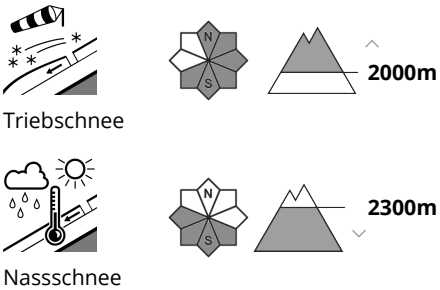

Schneebrettlawinen sind die Hauptgefahr. Zudem nimmt die Gefahr von feuchten und nassen Lawinen ab dem Morgen zu.

Die frischen und schon etwas älteren Triebschneeansammlungen müssen oberhalb der Waldgrenze vorsichtig beurteilt werden. Diese können schon von einzelnen Wintersportlern ausgelöst werden und mittlere Größe erreichen.

Markante Erwärmung bis auf 2700 m: An steilen Sonnenhängen und an Felswandfüßen steigt die Auslösebereitschaft von trockenen und nassen Lawinen im Tagesverlauf an.
Es sind mittlere und vereinzelt große spontane Lawinen möglich.
Die Spitze der Lawinenaktivität wird voraussichtlich im Tagesverlauf erreicht, in tiefen und mittleren Lagen schon am Vormittag.

Schneedecke

Gefahrenmuster gm.6: lockerer schnee und wind | gm.10: frühjahrssituation

In diesen Gebieten oberhalb von rund 1300 m liegt für die Jahreszeit viel Schnee.
Mit starkem Nordwestwind entstanden in den letzten Tagen frische Triebschneeansammlungen. Der starke Wind hat viel Schnee verfrachtet.

In Gipfellagen liegen je nach Windeinfluss sehr unterschiedliche Schneehöhen.
Vor allem mittlere und hohe Lagen sowie in windgeschützten Lagen: Die Schneedecke ist trocken, mit einer lockeren Oberfläche.
Sonnenhänge unterhalb von rund 2500 m: Die Sonneneinstrahlung führt im Tagesverlauf zu einer zunehmenden Anfeuchtung der Schneedecke.

Tendenz

Es ist mild. Mittag und Nachmittag: Allmählicher Anstieg der Gefahr von trockenen und feuchten Lawinen mit der Sonneneinstrahlung.

Gefahrenstufe 3 - Erheblich

AM:

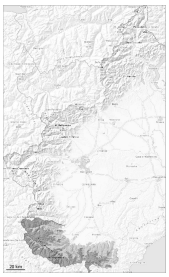

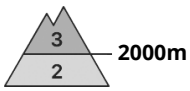

Tendenz: Lawinengefahr nimmt ab
am Montag, den 23.02.2026

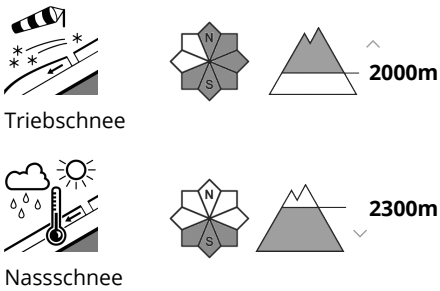

PM:

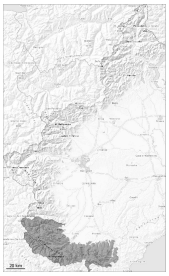

Tendenz: Lawinengefahr nimmt ab
am Montag, den 23.02.2026

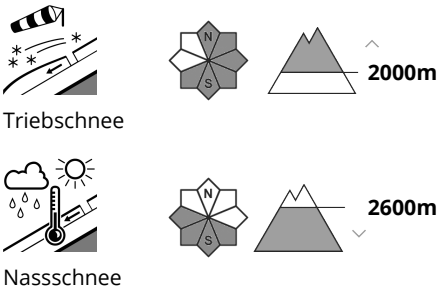

Frischen und älteren Triebschnee vorsichtig beurteilen. Die Gefahr von feuchten und nassen Lawinen steigt bereits am Vormittag an.

Die frischen und schon etwas älteren Triebschneeansammlungen müssen oberhalb der Waldgrenze vorsichtig beurteilt werden. Diese können weiterhin schon von einzelnen Wintersportlern ausgelöst werden und mittlere Größe erreichen.

Markante Erwärmung: An steilen Sonnenhängen und an Felswandfüßen steigt die Auslösebereitschaft von trockenen und nassen Lawinen im Tagesverlauf an. Vorsicht an sehr steilen Hängen auch in tiefen und mittleren Lagen.

Es sind zunehmend mittlere und vereinzelt große spontane Lawinen möglich.

Schneedecke

Gefahrenmuster gm.6: lockerer schnee und wind | gm.10: frühjahrssituation

Am Donnerstag fielen in allen Höhenlagen verbreitet 15 bis 25 cm Schnee.
Der starke Wind hat Neu- und Altschnee verfrachtet. Mit starkem Nordwestwind entstanden in den letzten Tagen frische Triebschneeansammlungen.

V.a. in Gipfellagen liegen je nach Windeinfluss sehr unterschiedliche Schneehöhen.
Schattenhänge: Die Schneedecke ist trocken, mit einer lockeren Oberfläche.
Sonnenhänge: Die Sonneneinstrahlung führt im Tagesverlauf unterhalb von rund 2500 m zu einer zunehmenden Anfeuchtung der Schneedecke.

Tendenz

Es ist mild. Mittag und Nachmittag: Allmählicher Anstieg der Gefahr von trockenen und feuchten Lawinen mit der Sonneneinstrahlung.