Sonntag 22.02.2026

Veröffentlicht am 21.02.2026 um 17:00

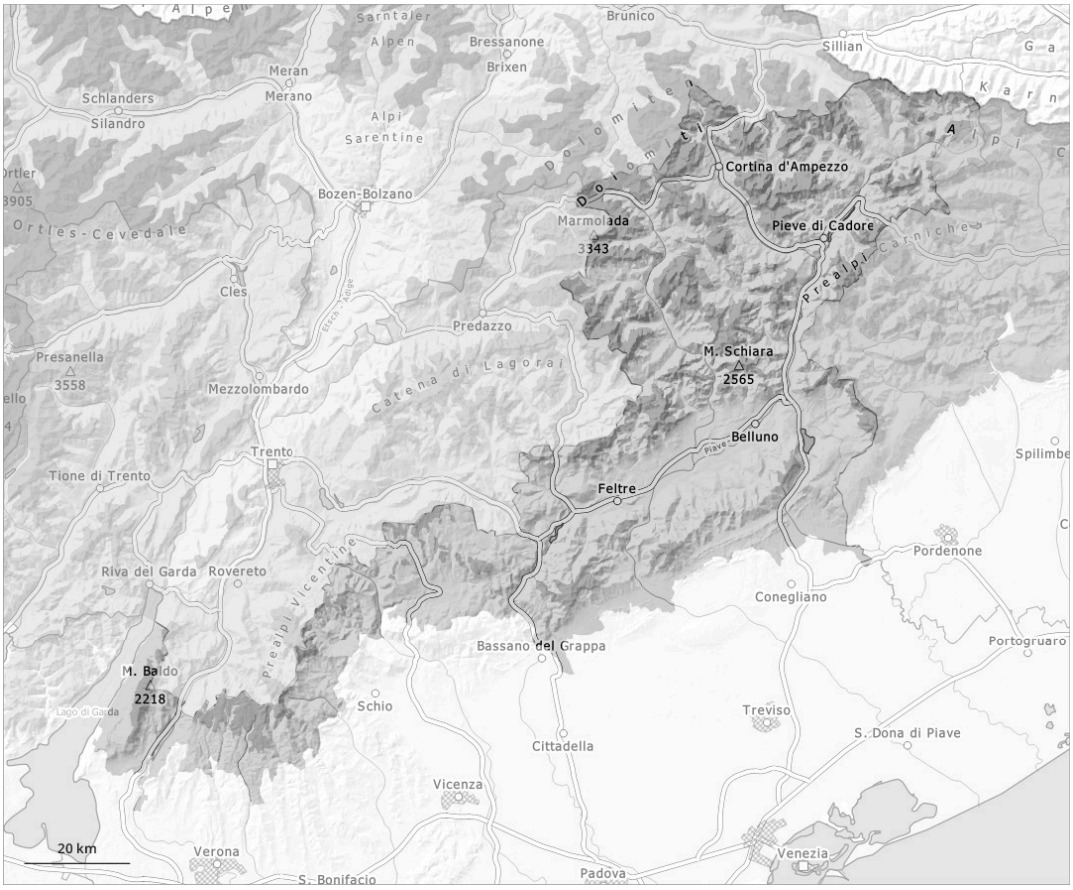

1	2	3	4	5
gering	mäßig	erheblich	groß	sehr groß

Gefahrenstufe 3 - Erheblich

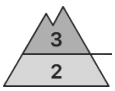

Waldgrenze

Tendenz: Lawinengefahr bleibt gleich
am Montag, den 23.02.2026

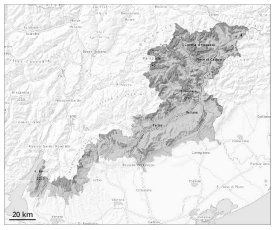

Triebschnee

Waldgrenze

Altschnee

Waldgrenze

Nassschnee

2300m

Triebschnee vorsichtig beurteilen. Mit der tageszeitlichen Erwärmung steigt die Gefahr von feuchten Lawinen im Tagesverlauf an. Ausgeprägte Schwachschichten im Altschnee erfordern eine defensive Routenwahl.

Der Wind bläst verbreitet stark. Verbreitet entstehen flächige Triebschneeansammlungen. Die Gefahrenstellen liegen vor allem an Triebschneehängen aller Expositionen oberhalb von rund 1900 m sowie an Übergängen von wenig zu viel Schnee.
Schwachschichten im Altschnee sind heimtückisch. Die Lawinen können stellenweise in tiefen Schichten ausgelöst werden und vereinzelt groß werden. Sie können schon von einzelnen Wintersportlern ausgelöst werden. Wummgeräusche und Risse beim Betreten der Schneedecke sind Alarmzeichen. Die Gefahrenstellen sind recht häufig und gut zu erkennen. Erfahrung und Zurückhaltung sind nötig. Mit der Sonneneinstrahlung steigt die Gefahr von feuchten Lawinen im Tagesverlauf an.

Schneedecke

Der Neuschnee vom Donnerstag liegt oberhalb der Waldgrenze auf einer ungünstigen Altschneeoberfläche. Vor allem oberhalb von rund 1900 m entstanden teils große Triebschneeansammlungen. Der untere Teil der Schneedecke ist kantig aufgebaut und schwach. Lawinen können auch in tieferen Schichten ausgelöst werden. Sonne und Wärme führen im Tagesverlauf vor allem an sehr steilen Sonnenhängen unterhalb von rund 2300 m zu einer Anfeuchtung der Schneedecke.