ICGC Institut Cartogràfic i Geològic de Catalunya

Servei Meteorològic de Catalunya meteo.cat

Boletín de peligro de aludes para el Pirineo de Catalunya
Del 21/02/2026 al 23/02/2026

(Válido fuera pistas de esquí y zonas no controladas)

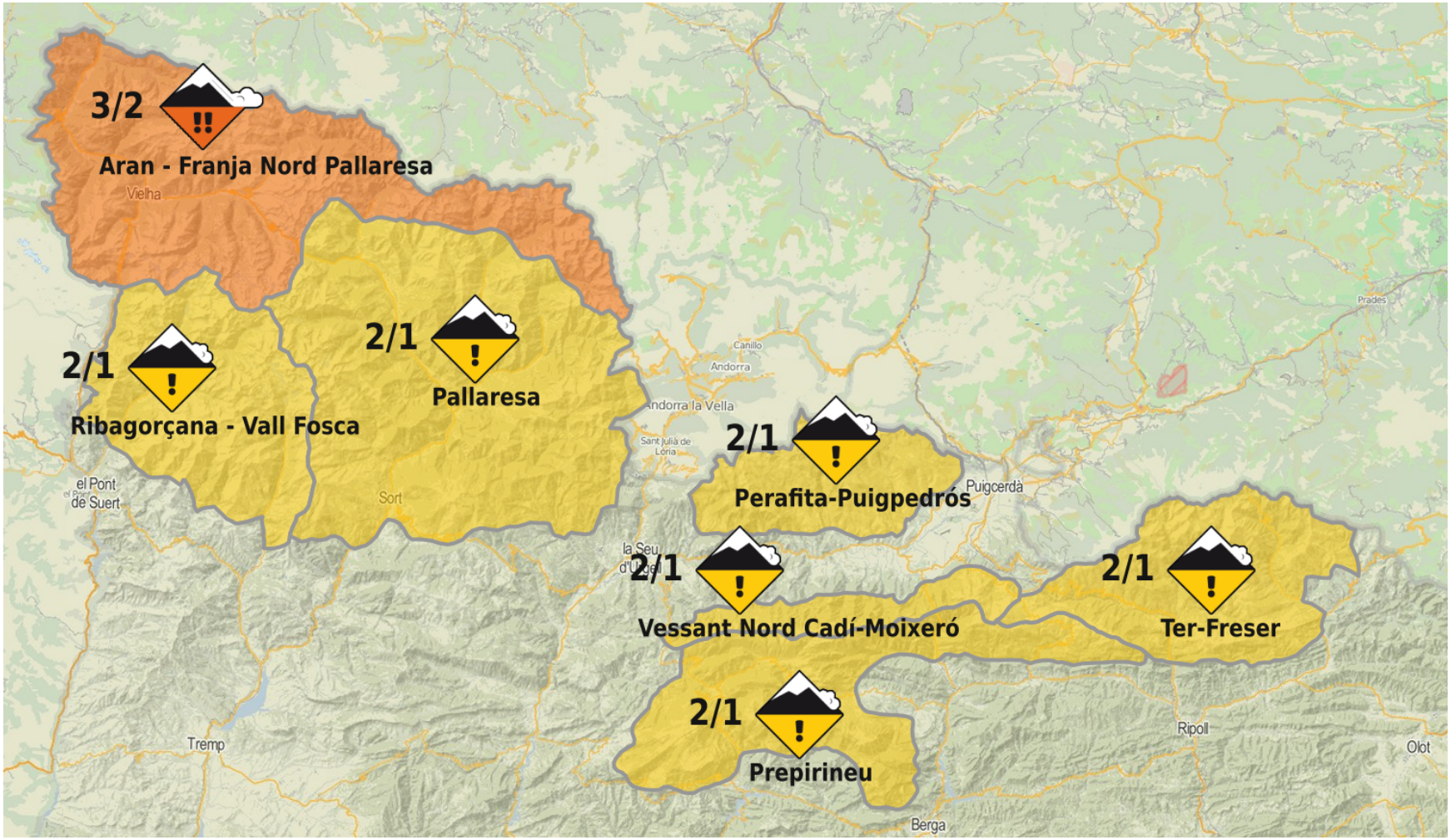

5 MUY FUERTE	4 FUERTE	3 NOTABLE	2 LIMITADO	1 DÉBIL

ICGC Institut Cartogràfic i Geològic de Catalunya

Servei Meteorològic de Catalunya

Boletín de peligro de aludes Aran - Franja Nord Pallaresa Del 21/02/2026 al 23/02/2026

(Válido fuera pistas de esquí y zonas no controladas)

NOTABLE (3) de mediodía hasta la tarde, LIMITADO (2) el resto

Situación primaria

Nieve húmeda

Distribución

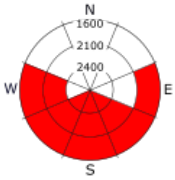

Tamaño

Origen

Tendencia

Situación secundaria

Nieve venteada

Distribución

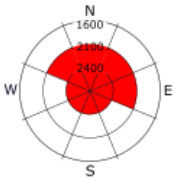

Tamaño

Origen

Tendencia

Estado del manto nivoso

El viernes y el sábado se han observado algunos aludes de placa y de nieve húmeda. El manto, con las altas temperaturas y fuerte insolación, se humedece rápidamente, sobre todo en orientaciones S. Son probables caídas de bolas y aludes de nieve húmeda de pequeño o mediano tamaño, principalmente en orientaciones S y E, en laderas de fuerte pendiente, hasta cotas altas, de unos 2.600 m en S. Son también posibles deslizamientos basales sobre sustrato propicio, herboso o rocoso liso.

Las placas de viento van perdiendo reactividad con el paso de los días. Pueden estar presentes todavía en todas las orientaciones de cota alta y en umbrías y E de cotas medias. Aunque menos sensibles, todavía pueden ceder al paso de una persona y desencadenar aludes que pueden ser de tamaño medio. Las placas irán perdiendo estructura y reactividad, en umbrías por el facetamiento, y en solanas por el humedecimiento, y el problema de placa de viento irá claramente de baja.

Distribución del manto nivoso

Los espesores a unos 2.200 m son superiores a los normales y rondan los 120-140 cm en el norte de Arán y los 160-200 cm en la Franja Nord Pallaresa y en el sur de Aran.

Tendencia para las próximas 48-72h

El problema de placa de viento se irá minimizando y persistirá el de nieve húmeda. Peligro: en leve DESCENSO.

El próximo boletín será emitido el día 2026-02-23

5 MUY FUERTE	4 FUERTE	3 NOTABLE	2 LIMITADO	1 DÉBIL

EAWS EUROPEAN AVALANCHE WARNING SERVICES

ICGC Institut Cartogràfic i Geològic de Catalunya

Servei Meteorològic de Catalunya

Boletín de peligro de aludes Ribagorçana - Vall Fosca Del 21/02/2026 al 23/02/2026

(Válido fuera pistas de esquí y zonas no controladas)

LIMITADO (2) de mediodía hasta la tarde, DÉBIL (1) el resto

Situación primaria

Nieve húmeda

Distribución

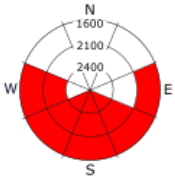

Tamaño

Origen

Tendencia

Situación secundaria

Nieve venteada

Distribución

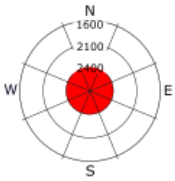

Tamaño

Origen

Tendencia

Estado del manto nivoso

Se prevén temperaturas altas y fuerte insolación hoy sábado y los próximos días que provocarán un humedecimiento del manto, especialmente en orientaciones S y W, a partir del mediodía. De madrugada y primeras horas de la mañana se encontrará rehelado y encostrado en estos sectores. Podrán desencadenarse aludes de nieve húmeda en laderas solanas de fuerte pendiente, más probables a partir de mediodía y hasta la tarde. Los aludes serán de pequeño tamaño en general, localmente podrán alcanzar tamaño medio.

Las placas de viento en cota alta aún pueden mostrarse algo sensibles, sobre todo en el extremo N del sector, y es posible el desencadenamiento accidental de aludes. Estos serían en general pequeños, puntualmente medianos, pero con el paso de los días seran cada vez menos presentes por el humedecimiento en solanas y la pérdida de cohesión por facetamiento en umbrías, y el problema de placa irá claramente de baja.

Distribución del manto nivoso

Hay nieve en el suelo a 1.400 m. El manto es esquiable por encima de unos 1.500 m. Los grosores alcanzan los 130-160 cm. Estos valores son muy superiores a los normales en la época.

Tendencia para las próximas 48-72h

El problema de placa de viento se irá minimizando y persistirá el de nieve húmeda. Peligro: en leve DESCENSO.

El próximo boletín será emitido el día 2026-02-23

5 MUY FUERTE	4 FUERTE	3 NOTABLE	2 LIMITADO	1 DÉBIL

EAWS EUROPEAN AVALANCHE WARNING SERVICES

ICGC Institut Cartogràfic i Geològic de Catalunya

Servei Meteorològic de Catalunya

Boletín de peligro de aludes Pallaresa
Del 21/02/2026 al 23/02/2026

(Válido fuera pistas de esquí y zonas no controladas)

LIMITADO (2) de mediodía hasta la tarde, DÉBIL (1) el resto

Situación primaria

Nieve húmeda

Distribución

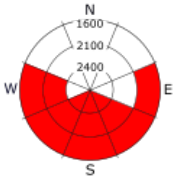

Tamaño

Origen

Tendencia

Situación secundaria

Nieve venteada

Distribución

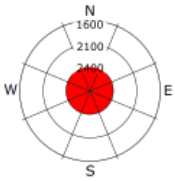

Tamaño

Origen

Tendencia

Estado del manto nivoso

Se prevén temperaturas altas y fuerte insolación hoy sábado y los próximos días que provocarán un humedecimiento del manto, especialmente en orientaciones S y W, a partir del mediodía. De madrugada y primeras horas de la mañana se encontrará rehelado y encostrado en estos sectores. Podrán desencadenarse aludes de nieve húmeda en laderas solanas de fuerte pendiente, más probables a partir de mediodía y hasta la tarde. Los aludes serán de pequeño tamaño en general, localmente podrán alcanzar tamaño medio.
Las placas de viento en cota alta aún pueden mostrarse algo sensibles, sobre todo en el extremo N del sector, y es posible el desencadenamiento accidental de aludes. Estos serían en general pequeños, puntualmente medianos, pero con el paso de los días seran cada vez menos presentes por el humedecimiento en solanas y la pérdida de cohesión por facetamiento en umbrías, y el problema de placa irá claramente de baja.

Distribución del manto nivoso

Hay nieve en el suelo a 1.400 m. El manto es esquiable por encima de unos 1.500 m. Los grosores alcanzan los 130-160 cm. Estos valores son muy superiores a los normales en la época.

Tendencia para las próximas 48-72h

El problema de placa de viento se irá minimizando y persistirá el de nieve húmeda. Peligro: en leve DESCENSO.

El próximo boletín será emitido el día 2026-02-23

5 MUY FUERTE	4 FUERTE	3 NOTABLE	2 LIMITADO	1 DÉBIL

EAWS EUROPEAN AVALANCHE WARNING SERVICES

ICGC Institut Cartogràfic i Geològic de Catalunya

Servei Meteorològic de Catalunya

Boletín de peligro de aludes Perafita-Puigpedrós Del 21/02/2026 al 23/02/2026

(Válido fuera pistas de esquí y zonas no controladas)

LIMITADO (2) de mediodía hasta la tarde, DÉBIL (1) el resto

Situación primaria

Nieve húmeda

Distribución

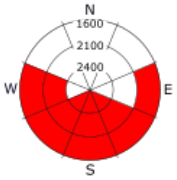

Tamaño

Origen

Tendencia

Situación secundaria

Nieve venteada

Distribución

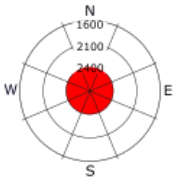

Tamaño

Origen

Tendencia

Estado del manto nivoso

Las altas temperaturas y la intensa insolación previstas provocarán un humedecimiento del manto, principalmente en orientaciones S y W, desde mediodía y hasta la tarde. De madrugada el manto estará encostrado y rehelado. Se esperan caída de bolas y aludes de nieve húmeda en los momentos de mayor humedecimiento, sobre todo en laderas S y W de más pendiente, más frecuentes bajo resaltes rocosos, tanto el domingo como el lunes. Los aludes serán de pequeño tamaño; puntualmente, alguno podría alcanzar tamaño medio.

En cota alta, todavía podemos encontrar algunas pequeñas placas superficiales que, por sobrecarga, podrían ceder generando aludes de pequeño tamaño. Con el paso de los días, estas placas, en umbrías, irán perdiendo estructura y cohesión, por facetamiento, y en solanas se irán estabilizando y humedeciendo, y el problema irá de baja.

Distribución del manto nivoso

Hay nieve en el suelo por encima de 1.400-1.500 m y el manto es esquiable por encima de 1.500-1.600 m. Los grosores alcanzan los 130-150 cm a 2.200 m. Son grosores muy por encima de los habituales por la época.

Tendencia para las próximas 48-72h

El problema de placa de viento se irá minimizando y persistirá el de nieve húmeda. Peligro: en leve DESCENSO.

El próximo boletín será emitido el día 2026-02-23

5 MUY FUERTE	4 FUERTE	3 NOTABLE	2 LIMITADO	1 DÉBIL

EAWS EUROPEAN AVALANCHE WARNING SERVICES

ICGC Institut Cartogràfic i Geològic de Catalunya

Servei Meteorològic de Catalunya

Boletín de peligro de aludes Vessant Nord Cadí-Moixeró Del 21/02/2026 al 23/02/2026

(Válido fuera pistas de esquí y zonas no controladas)

LIMITADO (2) de mediodía hasta la tarde, DÉBIL (1) el resto

Situación primaria

Nieve húmeda

Distribución

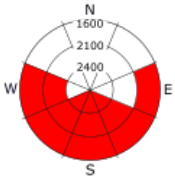

Tamaño

Origen

Tendencia

Situación secundaria

Nieve venteada

Distribución

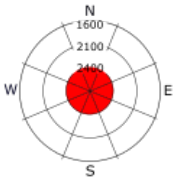

Tamaño

Origen

Tendencia

Estado del manto nivoso

El ascenso térmico a partir del sábado y con continuidad los próximos días, y la fuerte insolación, humedecerá el manto, sobre todo en orientaciones S y W. En umbrías de cota alta todavía se mantiene la nieve seca. A partir de mediodía, el manto humedecido dará lugar a caída de bolas y aludes de nieve húmeda, en laderas solanas y de fuerte pendiente, y bajo resaltes rocosos. Los aludes serán de pequeño tamaño, aunque puntualmente podrían alcanzar tamaño medio. A últimas horas de la tarde, con el enfriamiento del manto, esta actividad se detendrá.
En cota alta, todavía podemos encontrar algunas placas en cualquier orientación que pueden romper al paso de una persona y provocar aludes de pequeño tamaño en general. Estas placas, superficiales, tenderán a desactivarse con el paso de los días por la pérdida de cohesión debido al facetamiento previsto en umbrías y por el humedecimiento en solanas, y el problema de placa de viento disminuirá.

Distribución del manto nivoso

Hay manto continuo por encima de unos 1.600 m y esquiable por encima de unos 1.700 m. Los espesores están alrededor de 150-170 cm en cotas medias. Estos valores son muy excedentarios para la época del año.

Tendencia para las próximas 48-72h

El problema de placa de viento se irá minimizando y persistirá el de nieve húmeda. Peligro: en leve DESCENSO.

El próximo boletín será emitido el día 2026-02-23

5 MUY FUERTE	4 FUERTE	3 NOTABLE	2 LIMITADO	1 DÉBIL

EAWS EUROPEAN AVALANCHE WARNING SERVICES

ICGC Institut Cartogràfic i Geològic de Catalunya

Servei Meteorològic de Catalunya

Boletín de peligro de aludes Prepirineu
Del 21/02/2026 al 23/02/2026

(Válido fuera pistas de esquí y zonas no controladas)

LIMITADO (2) de mediodía hasta la tarde, DÉBIL (1) el resto

Situación primaria

Nieve húmeda

Distribución

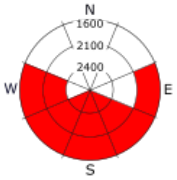

Tamaño

Origen

Tendencia

Situación secundaria

Nieve venteada

Distribución

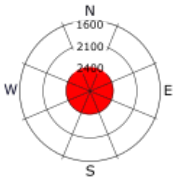

Tamaño

Origen

Tendencia

Estado del manto nivoso

Con las altas temperaturas e intensa radiación para los próximos días, el manto experimentará un ciclo de fusión-rehielo diurno-nocturno que afectará principalmente a las orientaciones S y W. Durante las horas del humedecimiento más intenso, desde mediodía hasta la tarde, se prevé actividad de aludes de nieve húmeda y caída de bolas. Los aludes serán de pequeño tamaño en general, localmente de tamaño medio.

Las placas que todavía se pueden encontrar en cota alta, formadas en los últimos episodios de viento y nieve, pueden localmente ceder por sobrecarga y desencadenar aludes de pequeño tamaño, pero estas placas irán perdiendo reactividad con el paso de los días por el humedecimiento en solanas y la pérdida de cohesión por facetamiento en umbrías altas.

Distribución del manto nivoso

Hay nieve desde 1400-1500 m. El manto es esquiable a partir de 1600 m. Los grosores están alrededor de 110-130 cm a unos 2.200 m y son superiores a los habituales.

Tendencia para las próximas 48-72h

El problema de placa de viento se irá minimizando y persistirá el de nieve húmeda. Peligro: en leve DESCENSO.

El próximo boletín será emitido el día 2026-02-23

5 MUY FUERTE	4 FUERTE	3 NOTABLE	2 LIMITADO	1 DÉBIL

EAWS EUROPEAN AVALANCHE WARNING SERVICES

ICGC Institut Cartogràfic i Geològic de Catalunya

meteo.cat Servei Meteorològic de Catalunya

Boletín de peligro de aludes Ter-Freser
Del 21/02/2026 al 23/02/2026

(Válido fuera pistas de esquí y zonas no controladas)

LIMITADO (2) de mediodía hasta la tarde, DÉBIL (1) el resto

Situación primaria

Nieve húmeda

Distribución

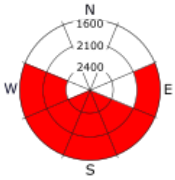

Tamaño

Origen

Tendencia

Situación secundaria

Nieve venteada

Distribución

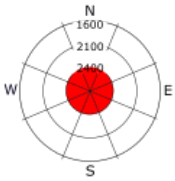

Tamaño

Origen

Tendencia

Estado del manto nivoso

Las altas temperaturas y la intensa insolación previstas provocarán un humedecimiento del manto, principalmente en orientaciones S y W, desde mediodía y hasta la tarde. De madrugada el manto estará encostrado y rehelado. Se esperan caída de bolas y aludes de nieve húmeda en los momentos de mayor humedecimiento, sobre todo en vertientes S y W de mayor pendiente, más frecuentes bajo resaltes rocosos, tanto el domingo como el lunes. Los aludes serán de pequeño tamaño, puntualmente alguno podría alcanzar tamaño medio.

En cota alta, todavía podemos encontrar algunas pequeñas placas superficiales que por sobrecarga podrían ceder generando aludes de pequeño tamaño. Con el paso de los días, estas placas, en umbrías, irán perdiendo estructura y cohesión, por facetamiento, y en solanas se irán estabilizando y humedeciendo, y el problema irá de baja.

Distribución del manto nivoso

El manto nivoso presenta grosores muy excedentarios para la época del año. En lugares no afectados por el viento, los espesores oscilan entre 100-140 cm a unos 2.000 m, siendo esquiable a partir de unos 1.500 m.

Tendencia para las próximas 48-72h

El problema de placa de viento se irá minimizando y persistirá el de nieve húmeda. Peligro: en leve DESCENSO.

El próximo boletín será emitido el día 2026-02-23

5 MUY FUERTE	4 FUERTE	3 NOTABLE	2 LIMITADO	1 DÉBIL

EAWS EUROPEAN AVALANCHE WARNING SERVICES