BUTLLETÍ DEL PERILL D'ALLAUS DEL PRINCIPAT D'ANDORRA

Servei meteorològic nacional
Principat d'Andorra

Elaborat el 21/02/2026 16:00
Propera actualització 22/02/2026 a les 16h

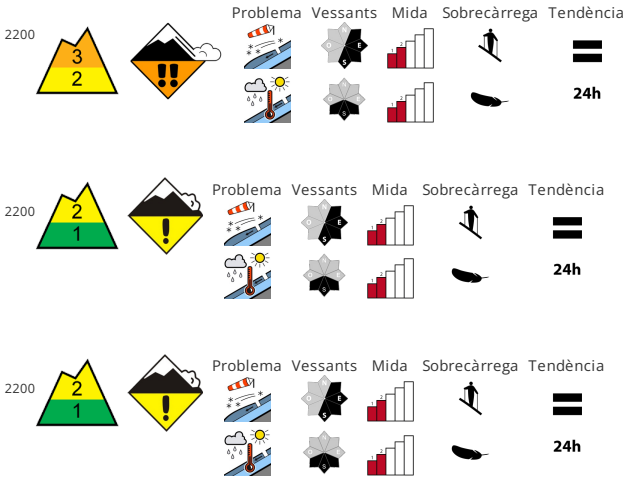

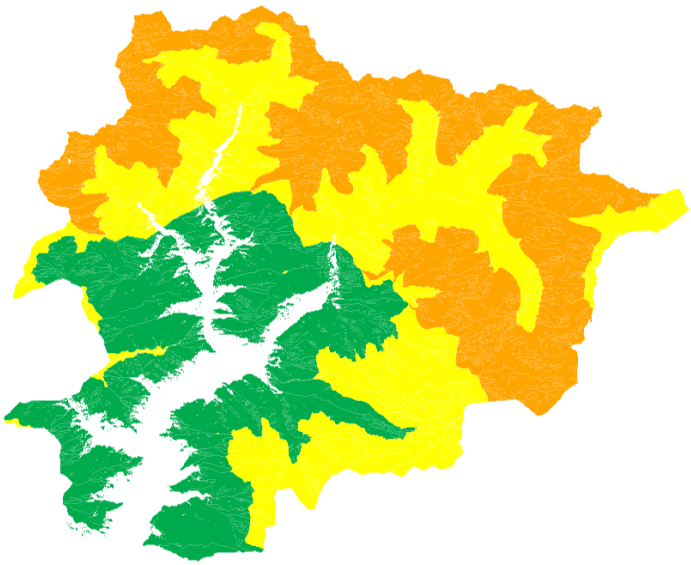

ESTABILITAT DEL MANTELL NIVAL

La neu recent i en particular les plaques de vent a vegades gruixudes poden fàcilment ser desencadenades de manera accidental o, de manera aïllada, natural en orientacions nord-est a fins al sud per l'est per sobre dels 2200 m aproximadament. Són especialment perillosos els vessants exposats a nord-est, est i sud-est , on al mantell de neu vella hi ha capes febles persistents. A més s'ha de tenir compte amb les plaques de vent tapades amb neu recent. Amb l'augment de la temperatura diürna i la radiació solar, són probables cada cop més nombroses allaus de placa humida de mida mitjana. A partir del migdia la probabilitat de desencadenament d'allaus humides augmentarà clarament sobretot als vessants assolellats inclinats. Això es dona especialment a la base de parets rocoses , i també en terreny dret i escarpat. A més, són possibles allaus de lliscament basal en qualsevol moment.

QUALITAT DE LA NEU

Els gruixos de neu varien molt per sobre dels 2500 m aproximadament per la influència del vent. Acumulacions de neu ventada més recents descansen a sobre d'una crosta. Evitar les zones amb esquerdes de lliscament basal.

GRUIXOS DEL MANTELL NIVAL FORA DE PISTA

Zona nord		Gruix neu		
Mantell Nival		1500m	2000m	2500m
N	1300 m	30 cm	150 cm	200 cm
S	1500 m	0 cm	100 cm	150 cm

Zona centre		Gruix neu		
Mantell Nival		1500m	2000m	2500m
N	1300 m	20 cm	150 cm	200 cm
S	1500 m	0 cm	100 cm	150 cm

Zona sud		Gruix neu		
Mantell Nival		1500m	2000m	2500m
N	1300 m	20 cm	120 cm	150 cm
S	1500 m	0 cm	60 cm	100 cm

Govern d'Andorra

EAWS
EUROPEAN AVALANCHE WARNING SERVICES

Aquest butlletí ha estat elaborat seguint les normes i recomanacions de l'**European Avalanche Warning Services**, del qual el **Servei meteorològic Nacional** n'és membre

BUTLLETÍ DEL PERILL D'ALLAUS DEL PRINCIPAT D'ANDORRA

Servei meteorològic nacional
Principat d'Andorra

Informació detallada per espais naturals protegits

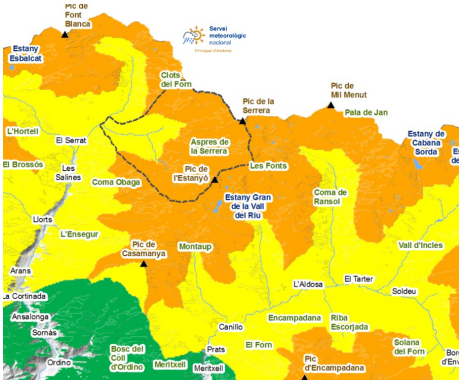

SORTENY

La nevada de dijous va afegir alguns centímetres a cotes baixes per sobre de la crosta de regel. A cotes altes es va acumular més neu, fet que farà més agradables les excursions, sobretot per sota del límit del bosc. En altura la neu estarà més ventada i amb distribucions molt irregulars, sovint encrostada. Trobem neu a tots els camins des de Llorts i l´accés amb esquís fins al Refugi es pot fer com feia anys que no es veia durant tantes setmanes seguides. Haurem de seguir les recomanacions de l´estabilitat del mantell nival per evitar posar-nos en perill als vessants est. Amb l´augment de temperatures apareixeran problemes de neu humida als vessants sud, fet que en un primer moment comportarà un augment de l´activitat d´allaus, però ajudarà a estabilitzar el mantell.

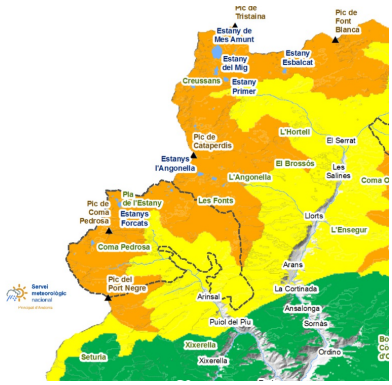

COMAPEDROSA

A cotes baixes la neu s´ha compactat i ha reduït el seu gruix a causa de l´humidificació provocada per les pluges de fa una setmana. Per sobre d´aquesta crosta, però, hi ha una mica de neu nova. A dins del bosc serà menys abundant i haurem de vigilar a no relliscar, però a les clarianes i a les parts altes aïllarà el gel. Tot i així, la distribució de la neu és molt irregular a causa del vent. Als vessants orientats a est, com pot ser l´accés des d´Arinsal pel Port Negre (Sanfons) haurem d´extremar les precaucions o evitar-los per no desencadenar les plaques de vent formades aquests darrers dies. El problema de neu humida anirà a més durant el cap de setmana.

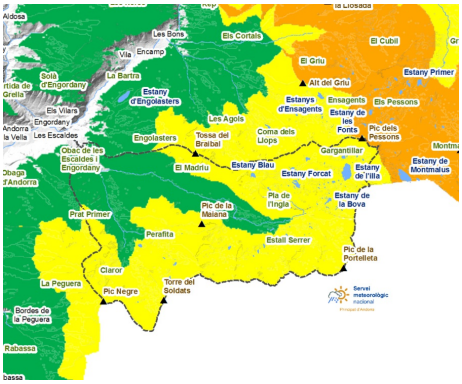

MADRIU-PERAFITA-CLAROR

Als vessants est s´hi ha de circular amb molta cautela, ja que és on hi ha les acumulacions de neu ventada més importants i perilloses. A cotes altes els vent haurà deixat la neu dura al descobert i amb condicions difícils de baixar en algunes ocasions.

Govern d'Andorra

EAWS EUROPEAN AVALANCHE WARNING SERVICES

Aquest butlletí ha estat elaborat seguint les normes i recomanacions de l'**European Avalanche Warning Services**, del qual el **Servei meteorològic Nacional** n'és membre

BUTLLETÍ DEL PERILL D'ALLAUS DEL PRINCIPAT D'ANDORRA

Servei meteorològic nacional
Principat d'Andorra

Gruixos de neu nova dels darrers dies (de les últimes 24h mesurat a les 06:00h UTC)

	17/02/2026	18/02/2026	19/02/2026	20/02/2026
FEDA (Central)	0 cm	0 cm	0 cm	0 cm
Engolasters - FEDA	0 cm	0 cm	0 cm	0 cm
Bony de les Neres	0 cm	0 cm	4 cm	0 cm
Sorteny	0 cm	3 cm	16 cm	0 cm
Perafita	0 cm	0 cm	9 cm	0 cm
Tossa Espiolets	0 cm	1 cm	0 cm	53 cm
Grau Roig - FEDA	0 cm	3 cm	1 cm	0 cm
Fontverd	0 cm	3 cm	2 cm	0 cm
Ransol - FEDA	2 cm	0 cm	0 cm	0 cm
Setúria	0 cm	2 cm	4 cm	0 cm
Caborreu	0 cm	0 cm	0 cm	0 cm
La Solana	0 cm	6 cm	0 cm	0 cm
Envalira Antenes	3 cm	2 cm	1 cm	0 cm
Vall del Riu FEDA	0 cm	2 cm	19 cm	0 cm