MINISTERO DELLA DIFESA

meteomont Servizio Nazionale di previsione neve e valanghe

EAWS EUROPEAN AVALANCHE WARNING SERVICES

CARABINIERI

ALPI RETICHE

Bollettino Valanghe N. 353/2026 del 20/02/2026 ore 14.00
Validità 48 ore prossima emissione 21/02/2026

A cura del Servizio METEOMONT dell'ARMA dei CARABINIERI
In collaborazione con Servizio Meteorologico dell'Aeronautica militare

SITUAZIONE alle 14:00 del 20/02/2026

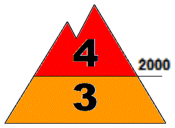

SITUAZIONE TIPO: neve a debole coesione e vento.

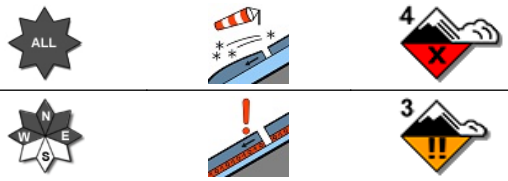

SITUAZIONE TIPO: strato debole persistente basale.

Quota neve (mslm)	Nord	Sud
	500	700

Altezza Neve (cm)	Neve al suolo	Neve Fresca	Quota (mslm)
	75	1	2582
	91	12	2150

VALANGHE OSSERVATE: Alcune valanghe di grandi dimensioni, I due tipi di valanghe di neve di superficie.

PREVISIONI 21/02/2026

GRADO DI PERICOLO: FORTE 4

SITUAZIONE TIPO: neve a debole coesione e vento.

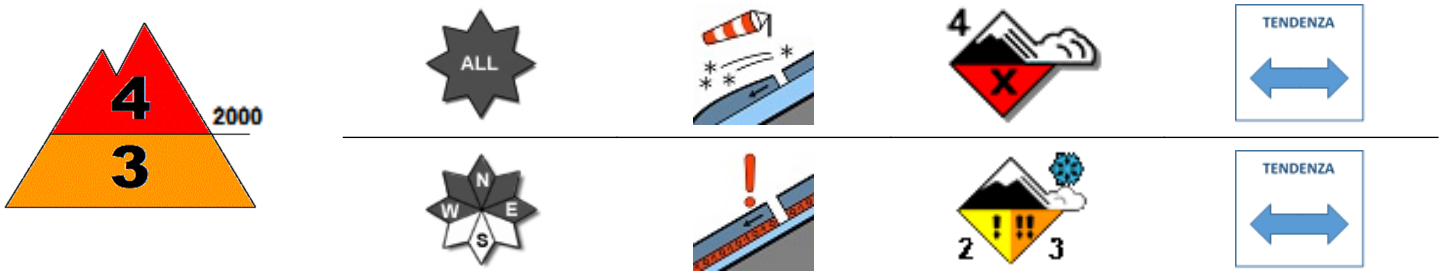

SITUAZIONE TIPO: strato debole persistente basale.

MANTO NEVOSO: La stabilità del manto nevoso è molto scarsa su molti punti (aree) per tutte le esposizioni al di sopra di 2000 mslm, possibili valanghe di dimensioni grandi.
La stabilità del manto nevoso è scarsa su molti punti (aree) per versanti da ovest a est al di sotto di 2000 mslm, possibili valanghe di dimensioni medie.

AVVERTENZE

A seguito dell'attività eolica registrata sono da evitare le zone di accumulo, conche, canaloni, cambi di pendenza e pendii sotto vento in genere.

SCALA EUROPEA DEL GRADO DI PERICOLO VALANGHE

LEGENDA PROBLEMA

Bollettino realizzato su scala sinottica-regionale (standard EAWS). La sua valutazione non può escludere in alcun modo la necessità di una seria e capace valutazione locale del pericolo (singolo pendio) che può essere anche sensibilmente diverso. Le previsioni meteorologiche sono relative all'orario UTC (per l'Italia +1 in inverno e +2 in estate).

Bollettino sottoposto a processi di: Acquisizione e controllo del C-Sifa e della rete di Osservatori e Esperti - Validazione del Previsore di turno - Certificazione della Sezione Meteomont.

MINISTERO DELLA DIFESA

meteomont
Servizio Nazionale di previsione neve e valanghe

EAWS EUROPEAN AVALANCHE WARNING SERVICES

CARABINIERI

ALPI RETICHE

PREVISIONE METEO

Quota		21/02/2026 h6:00	21/02/2026 h12:00	21/02/2026 h18:00
1000	Venti	03 nodi da N-Ovest	03 nodi da N-Ovest	04 nodi da N-Ovest
	Temperature	-01 °C	+00 °C	+01 °C
	Temp.percepita	-3 °C	-2 °C	-1 °C
2000	Venti	03 nodi da N-Ovest	03 nodi da N-Ovest	04 nodi da N-Ovest
	Temperature	-01 °C	+00 °C	+01 °C
	Temp.percepita	-3 °C	-2 °C	-1 °C
3000	Venti	18 nodi da N-Ovest	20 nodi da N-Ovest	21 Nodi da Nord
	Temperature	-08 °C	-07 °C	-06 °C
	Temp.percepita	-17 °C	-16 °C	-15 °C
Zero termico		1600-1800 m.	2000-2200 m.	2100-2300 m.
Fenomeno		—	—	—
Stato del cielo				

LEGENDA FENOMENI

— Assenza Fenomeni · Nebbia · Foschia · Pioggia debole · Pioggia moderata · Pioggia forte · Temporali

Nevicata debole · Nevicata moderata · Nevicata forte

STATO DEL CIELO

Sereno · Poco nuvoloso · Nuvoloso · Molto nuvoloso · Coperto

Parametri meteonivometrici registrati presso i campi di rilevamento il 20/02/2026.

Località	Comune	Quota (m.s.l.m.)	Altezza neve (cm)	Neve caduta nelle 24 ore (cm)	Temp. Min (°C)	Temp. Max (°C)	Condizioni del tempo
SPONDA	Livigno (SO)	2150	91	12	-5	-1	Assenza di precipitazioni
BORMIO2000-LECCIONA	Valdisotto (SO)	2050	86	23	-5	-2	Assenza di precipitazioni
VALAR	Valdidentro (SO)	1930	89	18	N.P.	N.P.	Assenza di precipitazioni
DOSSO DEL VALLONE	Valfurva (SO)	2582	75	Tracce di neve	-12	-7	Assenza di precipitazioni
APRICA *	Corteno Golgi (BS)	1199	25	0	N.P.	N.P.	Assenza di precipitazioni
PREDA	Edolo (BS)	1580	56	16	-1	0	Assenza di precipitazioni
COLONIA VIGILI	Ponte di Legno (BS)	1640	87	30	-9	+1	Assenza di precipitazioni
PARÈ DI LIVIGNO *	Livigno (SO)	2302	113	20	N.P.	N.P.	Scaccianeve (tormenta) sulla stazione

(*) Rilievi fuori campo

L'INFORMAZIONE E' PREVENZIONE - LEGGI L'ATTUALE GRADO DI PERICOLO VALANGHE!

IL CAPO DEL CENTRO NAZIONALE METEOMONT
(Ten. Col. RFI Emanuela Gini)
FIRMA AUTOGRAFA OMESSA AI SENSI
DELL'ART.3 DEL D.LGS N.39/1993

Bollettino realizzato su scala sinottica-regionale (standard EAWS). La sua valutazione non può escludere in alcun modo la necessità di una seria e capace valutazione locale del pericolo (singolo pendio) che può essere anche sensibilmente diverso. Le previsioni meteorologiche sono relative all'orario UTC (per l'Italia +1 in inverno e +2 in estate).