MINISTERO DELLA DIFESA

meteomont Servizio Nazionale di previsione neve e valanghe

EAWS EUROPEAN AVALANCHE WARNING SERVICES

CARABINIERI

AERONAUTICA MILITARE SERVIZIO METEOROLOGICO

ALPI LIGURI SUD

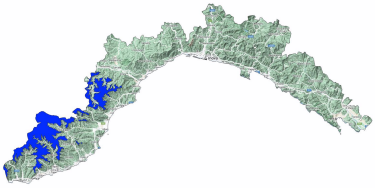

Bollettino Valanghe N. 304/2026 del 21/02/2026 ore 14.00
Validità 48 ore prossima emissione 22/02/2026

A cura del Servizio METEOMONT dell'ARMA dei CARABINIERI
In collaborazione con Servizio Meteorologico dell'Aeronautica militare

SITUAZIONE alle 14:00 del 21/02/2026

SITUAZIONE TIPO: situazione primaverile.

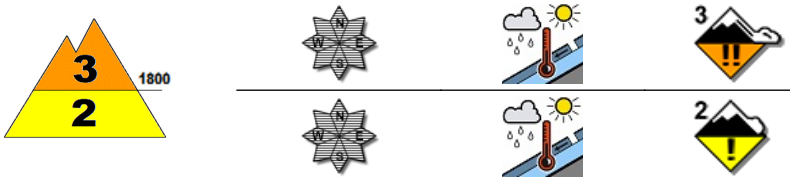

SITUAZIONE TIPO: situazione primaverile.

Quota neve (mslm)	Nord	Sud
	1100 - 1300	1300 - 1700

Altezza Neve (cm)	Neve al suolo	Neve Fresca	Quota (mslm)
	180	00	1800
	30-150	00	1500

VALANGHE OSSERVATE: Nessuna valanga.

PREVISIONI 22/02/2026

GRADO DI PERICOLO: MARCATO 3

SITUAZIONE TIPO: situazione primaverile.



SITUAZIONE TIPO: situazione primaverile.

MANTO NEVOSO: La stabilità del manto nevoso è scarsa su alcuni punti (aree) per isolati pendii al di sopra di 1800 mslm, possibili valanghe di dimensioni medie.
La stabilità del manto nevoso è scarsa su pochi punti (aree) per isolati pendii al di sotto di 1800 mslm, possibili valanghe di dimensioni medie.

AVVERTENZE

Il rialzo termico diurno richiede un'attenta valutazione temporale dell'escursione che eviti l'attraversamento di pendii ripidi nelle ore più calde della giornata.

SCALA EUROPEA DEL GRADO DI PERICOLO VALANGHE

LEGENDA PROBLEMA

Bollettino realizzato su scala sinottica-regionale (standard EAWS). La sua valutazione non può escludere in alcun modo la necessità di una seria e capace valutazione locale del pericolo (singolo pendio) che può essere anche sensibilmente diverso. Le previsioni meteorologiche sono relative all'orario UTC (per l'Italia +1 in inverno e +2 in estate).

MINISTERO DELLA DIFESA

meteomont
Servizio Nazionale di previsione neve e valanghe

EAWS EUROPEAN AVALANCHE WARNING SERVICES

CARABINIERI

ALPI LIGURI SUD

PREVISIONE METEO

Quota		22/02/2026 h6:00	22/02/2026 h12:00	22/02/2026 h18:00
1000	Venti	03 nodi da N-Ovest	01 Nodi da S-Ovest	02 nodi da N-Ovest
	Temperature	+05 °C	+07 °C	+06 °C
	Temp.percepita	4 °C	7 °C	6 °C
2000	Venti	02 Nodi da Ovest	02 Nodi da S-Ovest	01 Nodi da Nord
	Temperature	+08 °C	+07 °C	+08 °C
	Temp.percepita	8 °C	7 °C	8 °C
3000	Venti	05 nodi da N-Ovest	07 nodi da Ovest	07 nodi da N-Ovest
	Temperature	+01 °C	+02 °C	+04 °C
	Temp.percepita	-2 °C	-2 °C	1 °C
Zero termico		3000-3200 m.	3200-3400 m.	3500-3700 m.
Fenomeno		—	—	—
Stato del cielo				

LEGENDA FENOMENI

— Assenza Fenomeni · Nebbia · Foschia · Pioggia debole · Pioggia moderata · Pioggia forte · Temporali

Nevicata debole · Nevicata moderata · Nevicata forte

STATO DEL CIELO

Sereno · Poco nuvoloso · Nuvoloso · Molto nuvoloso · Coperto

Parametri meteonivometrici registrati presso i campi di rilevamento il 21/02/2026.

Località	Comune	Quota (m.s.l.m.)	Altezza neve (cm)	Neve caduta nelle 24 ore (cm)	Temp. Min (°C)	Temp. Max (°C)	Condizioni del tempo
PASSO MELOGNO	Calizzano (SV)	1028	78	0	N.P.	N.P.	Assenza di precipitazioni
PIAN DI FONTANA-MONESI	Triora (IM)	1525	150	0	+0	+12	Assenza di precipitazioni
MELOSA	Pigna (IM)	1540	26	0	+3	+10	Assenza di precipitazioni

(*) Rilievi fuori campo

L'INFORMAZIONE E' PREVENZIONE - LEGGI L'ATTUALE GRADO DI PERICOLO VALANGHE!

IL CAPO DEL CENTRO NAZIONALE METEOMONT
(Ten. Col. RFI Emanuela Gini)
FIRMA AUTOGRAFA OMESSA AI SENSI
DELL'ART.3 DEL D.LGS N.39/1993