MINISTERO DELLA DIFESA

meteomont
Servizio Nazionale di previsione neve e valanghe

EAWS EUROPEAN AVALANCHE WARNING SERVICES

CARABINIERI

AERONAUTICA MILITARE SERVIZIO METEOROLOGICO

MAJELLA

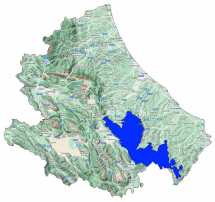

Bollettino Valanghe N. 340/2026 del 21/02/2026 ore 14.00
Validità 48 ore prossima emissione 22/02/2026

A cura del Servizio METEOMONT dell'ARMA dei CARABINIERI
In collaborazione con Servizio Meteorologico dell'Aeronautica militare

SITUAZIONE alle 14:00 del 21/02/2026

SITUAZIONE TIPO: neve pallottolare sepolta.

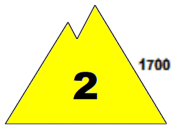



SITUAZIONE TIPO: situazione primaverile.

Quota neve (mslm)	Nord	Sud
	1100 - 1400	1200 - 1400

Altezza Neve (cm)	Neve al suolo	Neve Fresca	Quota (mslm)
	217	025	2251
	046	011	1650

VALANGHE OSSERVATE: Nessuna valanga.

PREVISIONI 22/02/2026

GRADO DI PERICOLO: MARCATO 3

SITUAZIONE TIPO: neve pallottolare sepolta.

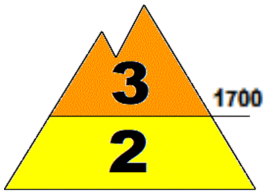

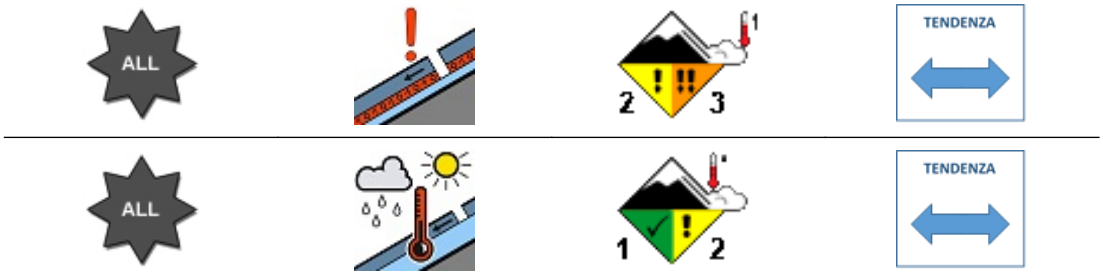

SITUAZIONE TIPO: situazione primaverile.

MANTO NEVOSO: La stabilità del manto nevoso è scarsa su alcuni punti (aree) per tutte le esposizioni al di sopra di 1700 mslm, possibili valanghe di dimensioni grandi.
La stabilità del manto nevoso è scarsa su alcuni punti (aree) per tutte le esposizioni al di sotto di 1700 mslm, possibili valanghe di dimensioni medie.

AVVERTENZE

Viste le condizioni del manto nevoso, le attività al di fuori delle piste battute e segnalate richiedono ottime capacità di valutazione del pericolo locale.

SCALA EUROPEA DEL GRADO DI PERICOLO VALANGHE

LEGENDA PROBLEMA

Bollettino realizzato su scala sinottica-regionale (standard EAWS). La sua valutazione non può escludere in alcun modo la necessità di una seria e capace valutazione locale del pericolo (singolo pendio) che può essere anche sensibilmente diverso. Le previsioni meteorologiche sono relative all'orario UTC (per l'Italia +1 in inverno e +2 in estate).

MINISTERO DELLA DIFESA

meteomont
Servizio Nazionale di previsione neve e valanghe

EAWS EUROPEAN AVALANCHE WARNING SERVICES

CARABINIERI

MAJELLA

PREVISIONE METEO

Quota		22/02/2026 h6:00	22/02/2026 h12:00	22/02/2026 h18:00
1000	Venti	02 Nodi da Nord	02 Nodi da N-Est	02 Nodi da S-Ovest
	Temperature	+00 °C	+04 °C	+04 °C
	Temp.percepita	0 °C	4 °C	4 °C
2000	Venti	06 Nodi da Nord	03 Nodi da N-Est	03 Nodi da Ovest
	Temperature	-01 °C	+01 °C	+04 °C
	Temp.percepita	-5 °C	-1 °C	3 °C
3000	Venti	14 Nodi da Nord	11 Nodi da Nord	11 nodi da N-Ovest
	Temperature	-07 °C	-04 °C	-02 °C
	Temp.percepita	-15 °C	-10 °C	-8 °C
Zero termico		1500-1700 m.	2200-2400 m.	2500-2700 m.
Fenomeno		—	—	—
Stato del cielo				

LEGENDA FENOMENI

— Assenza Fenomeni · Nebbia · Foschia · Pioggia debole · Pioggia moderata · Pioggia forte · Temporali

Nevicata debole · Nevicata moderata · Nevicata forte

STATO DEL CIELO

Sereno · Poco nuvoloso · Nuvoloso · Molto nuvoloso · Coperto

Parametri meteonivometrici registrati presso i campi di rilevamento il 21/02/2026.

Località	Comune	Quota (m.s.l.m.)	Altezza neve (cm)	Neve caduta nelle 24 ore (cm)	Temp. Min (°C)	Temp. Max (°C)	Condizioni del tempo
QUARTARANA	Campo di Giove (AQ)	1200	1	1	-2	+8	Nevicata debole intermittente
PASSOLANCIANO	Lettomanoppello (PE)	1300	11	11	-2	+5	Assenza di precipitazioni
VALICO DELLA FORCHETTA	Palena (CH)	1270	1	1	-2	+7	Assenza di precipitazioni
VALLE DEL SOLE	Pizzoferrato (CH)	1440	2	1	-2	+4	Assenza di precipitazioni
MAIELETTA MAMMA ROSA	Pretoro (CH)	1650	46	11	-7	0	Assenza di precipitazioni
PENDICI FOCALONE *	Pennapiedimonte (CH)	2251	217	25	N.P.	N.P.	Assenza di precipitazioni

(*) Rilievi fuori campo

L'INFORMAZIONE E' PREVENZIONE - LEGGI L'ATTUALE GRADO DI PERICOLO VALANGHE!

IL CAPO DEL CENTRO NAZIONALE METEOMONT
(Ten. Col. RFI Emanuela Gini)
FIRMA AUTOGRAFA OMESSA AI SENSI
DELL'ART.3 DEL D.LGS N.39/1993

Bollettino realizzato su scala sinottica-regionale (standard EAWS). La sua valutazione non può escludere in alcun modo la necessità di una seria e capace valutazione locale del pericolo (singolo pendio) che può essere anche sensibilmente diverso. Le previsioni meteorologiche sono relative all'orario UTC (per l'Italia +1 in inverno e +2 in estate).