MINISTERO DELLA DIFESA

meteomont Servizio Nazionale di previsione neve e valanghe

EAWS EUROPEAN AVALANCHE WARNING SERVICES

CARABINIERI

APPENNINO LUCANO

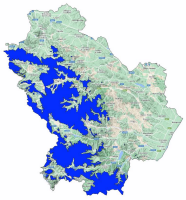

Bollettino Valanghe N. 250/2026 del 21/02/2026 ore 14.00
Validità 48 ore prossima emissione 22/02/2026

A cura del Servizio METEOMONT dell'ARMA dei CARABINIERI
In collaborazione con Servizio Meteorologico dell'Aeronautica militare

SITUAZIONE alle 14:00 del 21/02/2026

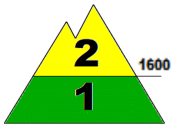

SITUAZIONE TIPO: neve a debole coesione e vento.



SITUAZIONE TIPO: situazione primaverile.

Quota neve (mslm)	Nord	Sud
	1300 - 1400	1500

Altezza Neve (cm)	Neve al suolo	Neve Fresca	Quota (mslm)
	019	001	1530
	002	000	1380

VALANGHE OSSERVATE: Nessuna valanga.

PREVISIONI 22/02/2026

GRADO DI PERICOLO: MODERATO 2

SITUAZIONE TIPO: situazione primaverile.

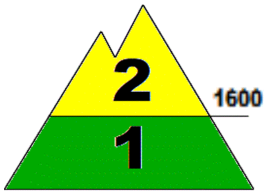

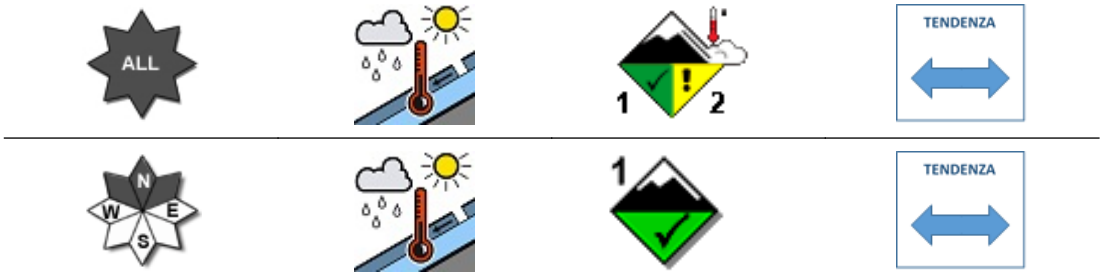

SITUAZIONE TIPO: situazione primaverile.

MANTO NEVOSO: La stabilità del manto nevoso è discreta su alcuni punti (aree) per tutte le esposizioni al di sopra di 1600 mslm, possibili valanghe di dimensioni medie.
La stabilità del manto nevoso è buona su molti punti (aree) per versanti settentrionali al di sotto di 1600 mslm, possibili valanghe di dimensioni piccole.

AVVERTENZE

Il rialzo termico diurno richiede un'attenta valutazione temporale dell'escursione che eviti l'attraversamento di pendii ripidi nelle ore più calde della giornata.

SCALA EUROPEA DEL GRADO DI PERICOLO VALANGHE

LEGENDA PROBLEMA

Bollettino realizzato su scala sinottica-regionale (standard EAWS). La sua valutazione non può escludere in alcun modo la necessità di una seria e capace valutazione locale del pericolo (singolo pendio) che può essere anche sensibilmente diverso. Le previsioni meteorologiche sono relative all'orario UTC (per l'Italia +1 in inverno e +2 in estate).

APPENNINO LUCANO

PREVISIONE METEO

Quota		22/02/2026 h6:00	22/02/2026 h12:00	22/02/2026 h18:00
1000	Venti	08 Nodi da N-Est	11 Nodi da Nord	07 Nodi da Nord
	Temperature	+06 °C	+07 °C	+07 °C
	Temp.percepita	3 °C	4 °C	5 °C
2000	Venti	19 Nodi da Nord	19 Nodi da Nord	15 Nodi da Nord
	Temperature	+00 °C	+00 °C	+03 °C
	Temp.percepita	-7 °C	-7 °C	-2 °C
3000	Venti	19 Nodi da Nord	19 Nodi da Nord	18 Nodi da Nord
	Temperature	-07 °C	-04 °C	-02 °C
	Temp.percepita	-16 °C	-12 °C	-9 °C
Zero termico		1500-1700 m.	2000-2200 m.	2300-2500 m.
Fenomeno		—	—	—
Stato del cielo				

LEGENDA FENOMENI

— Assenza Fenomeni · Nebbia · Foschia · Pioggia debole · Pioggia moderata · Pioggia forte · Temporali

Nevicata debole · Nevicata moderata · Nevicata forte

STATO DEL CIELO

Sereno · Poco nuvoloso · Nuvoloso · Molto nuvoloso · Coperto

Parametri meteonivometrici registrati presso i campi di rilevamento il 21/02/2026.

Località	Comune	Quota (m.s.l.m.)	Altezza neve (cm)	Neve caduta nelle 24 ore (cm)	Temp. Min (°C)	Temp. Max (°C)	Condizioni del tempo
LAUDEMIO	Lagonegro (PZ)	1532	19	1	-3	+3	Assenza di precipitazioni
PIANO IMPERATORE	Marsicovetere (PZ)	1560	11	1	+0	+2	Assenza di precipitazioni
PEDARRETO	Rotonda (PZ)	1380	2	0	+1	+5	Assenza di precipitazioni

(*) Rilievi fuori campo

L'INFORMAZIONE E' PREVENZIONE - LEGGI L'ATTUALE GRADO DI PERICOLO VALANGHE!

IL CAPO DEL CENTRO NAZIONALE METEOMONT
(Ten. Col. RFI Emanuela Gini)
FIRMA AUTOGRAFA OMESSA AI SENSI
DELL'ART.3 DEL D.LGS N.39/1993

Bollettino realizzato su scala sinottica-regionale (standard EAWS). La sua valutazione non può escludere in alcun modo la necessità di una seria e capace valutazione locale del pericolo (singolo pendio) che può essere anche sensibilmente diverso. Le previsioni meteorologiche sono relative all'orario UTC (per l'Italia +1 in inverno e +2 in estate).