Bulletin d'estimation du risque d'avalanche
(valable en dehors des pistes balisées et ouvertes)

MASSIF : Bauges

Rédigé le samedi 21 février 2026 à 16h

Estimation des risques pour le : DIMANCHE 22 FÉVRIER

REDOUX : PLAQUES DE FOND ET NEIGE HUMIDE

2

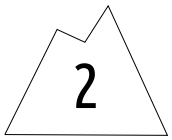

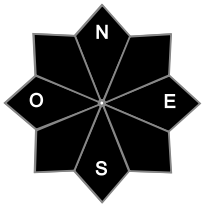

Indice de risque limité.

Départs spontanés : Plaques de fond et départs ponctuels au soleil.

Déclenchements provoqués : rares plaques en ubacs d'altitude.

Indices de risque : 5 très fort - 4 fort - 3 marqué - 2 limité - 1 faible -- En noir : les pentes les plus dangereuses

Stabilité du manteau neigeux

Situation avalancheuse typique : avalanches de fond neige humide

Départs spontanés :
* En dessous de 2200 m : **plaques de fond**. Tous versants, mais départs plus nombreux dans les pentes sud. Départs dans les pentes raides et lisses (pentes herbeuses, dalles rocheuses). Taille 2 (moyenne) à 3 (grande).
* **Chutes de corniches**, épaisses et volumineuses, **pouvant solliciter de très larges plaques friables.**
* Au fil de l'ensoleillement, départ en poire dans la neige récente humidifiée. Taille 1 à 2.

Déclenchements provoqués :
* Au-dessus de 1800 m : quelques plaques dans la neige récente humide. Un peu plus sensible dans les ubacs proches des plus hauts sommets. Taille 1 à 2 (petite à moyenne).

Qualité de la neige

Enneigement : Bon pour la saison à toutes altitudes grâce aux fréquentes chutes de neige du mois de février. On peut chausser les skis vers 1200 m dans tous les versants. L'épaisseur du manteau neigeux varie : nombreuses congères et corniches.

Qualité de la neige dimanche :
- En dessous de 1600/1800 m : crouté le matin, puis neige humide et très lourde.
- Au-dessus de 1800 m : finement crouté le matin qui s'humidifie en journée. En ubacs, proche des plus hauts sommets, neige encore froide et souple qui se densifie en journée.

Aperçu météo pour le dimanche 22 février

nuit	matin	après-midi	soir

Ensoleillé avec un fin voile en altitude. Températures en hausse à 1500 m : -1 à 12°C !

Pluie-Neige				
Iso 0 °C	2 600 m	2 800 m	2 900 m	2 800 m
Vent 1500 m	10 km/h	5 km/h	15 km/h	10 km/h
Vent 2000 m	25 km/h	25 km/h	25 km/h	20 km/h

Épaisseur de neige hors-piste

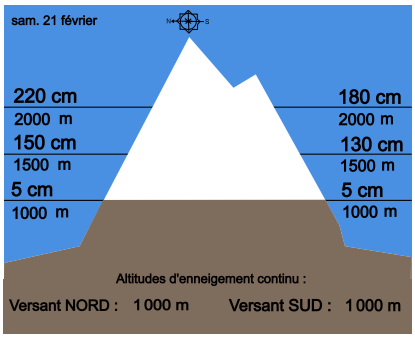

Précipitations à 1800 m

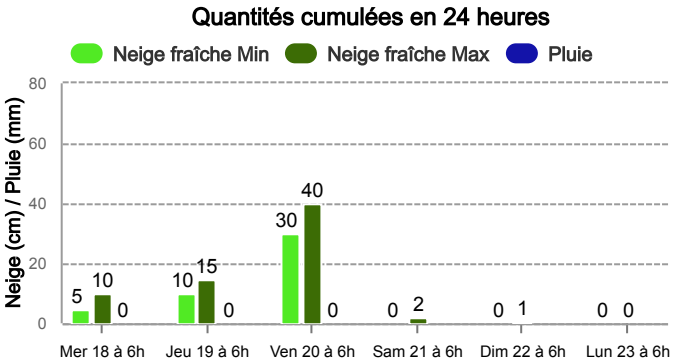

Tendance du lundi 23 février

2

Indice de risque limité

Risque stationnaire. Un peu plus nuageux.

Pour consulter la vigilance en cours, veuillez vous rendre sur le site https://vigilance.meteofrance.fr/fr

Météo-France - 73 avenue de Paris, 94165 Saint-Mandé cedex - Contact : contact@meteo.fr

Rédigé par Météo-France avec la contribution des observateurs du réseau nivo-météorologiques. Partenariat : ANMSM (Maires de Stations de Montagne), DSF (Domaines Skiables de France), ADSP (Directeurs de Pistes et de la Sécurité des Stations de Sports d'Hiver) et autres acteurs de la montagne.

Bulletin neige & avalanches par téléphone au 0 892 68 10 20 Service 0,35 € / min + prix appel

RÉPUBLIQUE FRANÇAISE
Liberté Égalité Fraternité

METEO FRANCE
À VOS CÔTÉS, DANS UN CLIMAT QUI CHANGE

Bulletin d'estimation du risque d'avalanche

(valable en dehors des pistes balisées et ouvertes)

MASSIF : Bauges

Rédigé le samedi 21 février 2026 à 16h

Conditions nivo-météo des 7 derniers jours

	dim. 15/02				lun. 16/02				mar. 17/02				mer. 18/02				jeu. 19/02				ven. 20/02				sam. 21/02			
	03h	09h	15h	21h	03h	09h	15h	21h	03h	09h	15h	21h	03h	09h	15h	21h	03h	09h	15h	21h	03h	09h	15h	21h	03h	09h	15h	21h
Météo																												
Vent (km/h)	45	35	35	45	45	55	60	55	55	50	40	30	15	25	25	60	40	40	30	45	55	35	25	25	25	25	30	30
à 2000m																												
Vent (km/h)	35	20	20	25	30	45	50	40	40	40	25	20	10	20	20	40	25	30	25	30	40	25	20	15	20	15	15	10
à 1500m																												

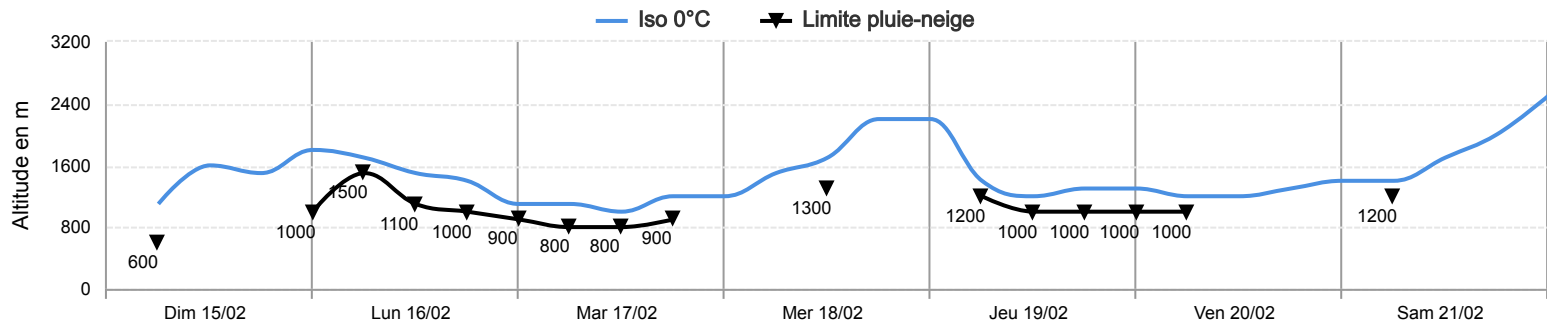

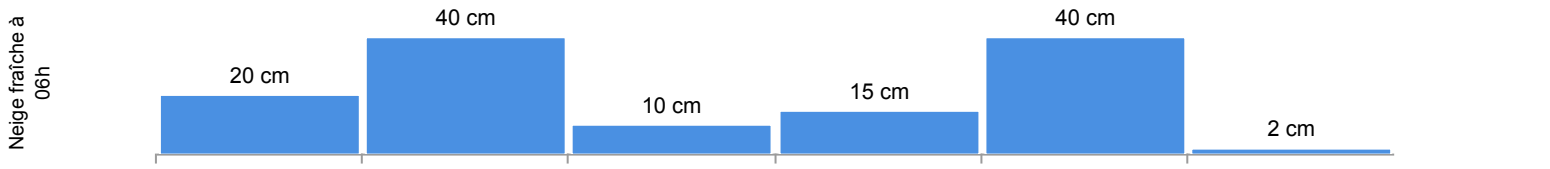

Risque d'avalanche							
	dim. 15/02	lun. 16/02	mar. 17/02	mer. 18/02	jeu. 19/02	ven. 20/02	sam. 21/02

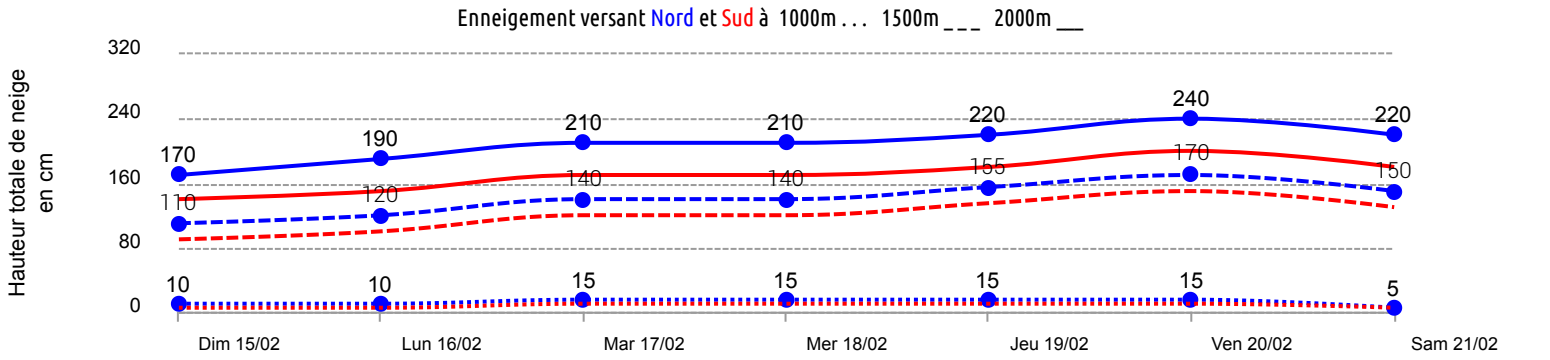

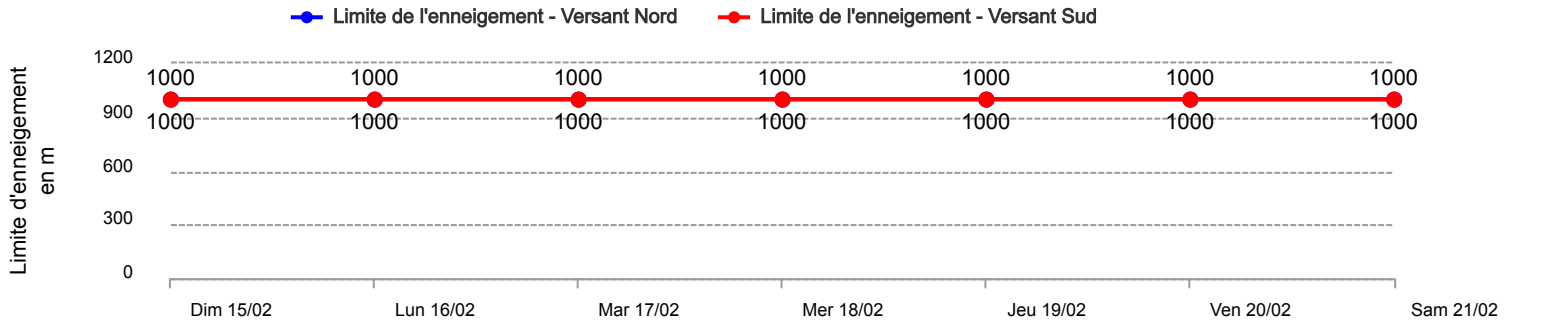

Pour consulter la vigilance en cours, veuillez vous rendre sur le site https://vigilance.meteofrance.fr/fr

Météo-France - 73 avenue de Paris, 94165 Saint-Mandé cedex - Contact : contact@meteo.fr

Rédigé par Météo-France avec la contribution des observateurs du réseau nivo-météorologiques. Partenariat : ANMSM (Maires de Stations de Montagne), DSF (Domaines Skiables de France), ADSP (Directeurs de Pistes et de la Sécurité des Stations de Sports d'Hiver) et autres acteurs de la montagne.

Bulletin neige & avalanches par téléphone au
0 892 68 10 20 Service 0,35 € / min + prix appel