RÉPUBLIQUE FRANÇAISE
Liberté Égalité Fraternité

METEO FRANCE
À VOS CÔTÉS, DANS UN CLIMAT QUI CHANGE

Bulletin d'estimation du risque d'avalanche

(valable en dehors des pistes balisées et ouvertes)

MASSIF : Capcir Puymorens

Rédigé le samedi 21 février 2026 à 16h

Estimation des risques pour le : DIMANCHE 22 FÉVRIER

PRÉSENCE DE PLAQUES À VENT EN ALTITUDE

3

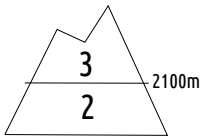

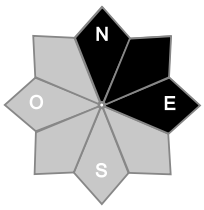

Au-dessus de 2100m indice de risque marqué, plus bas indice limité.

Départs spontanés : en neige humide

Déclenchements provoqués : présence de plaques en versants ombragés et en altitude

Indices de risque : 5 très fort - 4 fort - 3 marqué - 2 limité - 1 faible -- En noir : les pentes les plus dangereuses

Stabilité du manteau neigeux

Situation avalancheuse typique : neige ventée neige humide

Déclenchements provoqués :
Nombreuses **structures de plaques** présentes dans la neige récente (formées ces derniers jours sous l'effet d'un vent turbulent ayant soufflé parfois très fort**).** Elles sont **facilement déclenchables** dans les secteurs où la neige est restée froide (pentes ombragées ou à haute altitude), parfois loin des crêtes. Des cassures typiques de quelques dizaines de centimètres sont à attendre, localement plus dans les zones de plus forte accumulation (au dessus de 2100m dans un vaste secteur nord à sud-est). Ces plaques pourront être friables ou dures, suivant l'intensité du vent leur ayant donné naissance. La couche fragile est majoritairement composée de neige moins ventée, mais au dessus de 2200m on pourra parfois trouver quelques grains anguleux enfouis pouvant jouer ce rôle.
Observables : Fissures devant les skis, "whoomfs" au passage d'un pratiquant. Les plaques friables restent toutefois difficilement détectables, car d'aspect poudreux.

Départs spontanés :
Des départs spontanés ponctuels ou linéaires en **neige humide** sont à attendre au fil de l'ensoleillement, plutôt à basse et moyenne altitude (avalanches petites à moyennes).

Autre : Chutes de corniches probables avec la poursuite de l'humidification.

Qualité de la neige

Enneigement :
A la faveur des multiples passages perturbés qui se sont succédé depuis le début de l'année, l'enneigement est largement supérieur à celui des cinq dernières années et se situe bien au dessus de la moyenne. La barre des 2m de neige est souvent atteinte dès 2000m d'altitude. On pourra commencer à skier confortablement dès 1400/1500m.

Qualité de la neige :
En matinée, on trouvera dans de nombreux secteurs en dessous de 2100m une neige croutée souvent portante. Au fil des heures et de l'ensoleillement, cette croute sera remplacée par de la neige humide et lourde. En journée, on trouvera un tableau classique, à savoir des conditions de neige de printemps dans un vaste secteur sud et une neige qui reste poudreuse ou tassée par le vent dans les secteurs ombragés d'altitude. Certaines crêtes sont dégarnies pendant que d'autres sont couvertes de quelques cm de glace dure.

Aperçu météo pour le dimanche 22 février

	nuit	matin	après-midi	soir
Grand beau temps dans la douceur				
Pluie-Neige				
Iso 0 °C	3 200 m	3 500 m	3 500 m	3 500 m
Vent 2000 m	↘ 10 km/h	↗ 10 km/h	↘ 10 km/h	→ 10 km/h
Vent 3000 m	↓ 20 km/h	→ 15 km/h	→ 15 km/h	→ 15 km/h

Pour consulter la vigilance en cours, veuillez vous rendre sur le site https://vigilance.meteofrance.fr/fr

Météo-France - 73 avenue de Paris, 94165 Saint-Mandé cedex - Contact : contact@meteo.fr

Rédigé par Météo-France avec la contribution des observateurs du réseau nivo-météorologiques. Partenariat : ANMSM (Maires de Stations de Montagne), DSF (Domaines Skiables de France), ADSP (Directeurs de Pistes et de la Sécurité des Stations de Sports d'Hiver) et autres acteurs de la montagne.

Bulletin neige & avalanches par téléphone au
0 892 68 10 20 Service 0,35 € / min + prix appel

Bulletin d'estimation du risque d'avalanche

(valable en dehors des pistes balisées et ouvertes)

MASSIF : Capcir Puymorens

Rédigé le samedi 21 février 2026 à 16h

Épaisseur de neige hors-piste

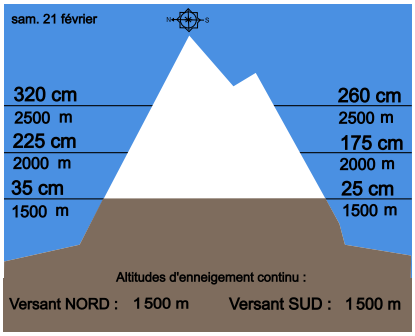

Précipitations à 1800 m

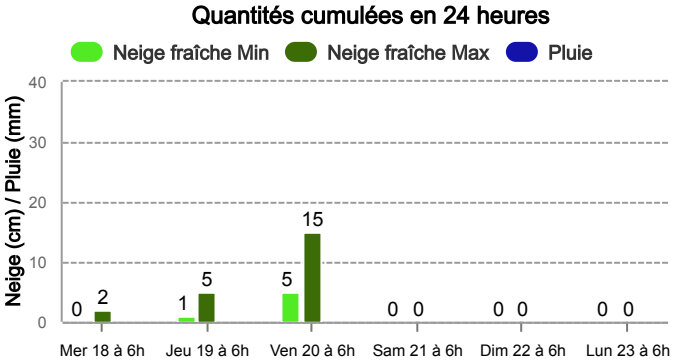

Tendance du lundi 23 février

Indice de risque marqué

Poursuite de la stabilisation progressive des plaques à vent, instabilités encore présentes en neige humide.

Pour consulter la vigilance en cours, veuillez vous rendre sur le site https://vigilance.meteofrance.fr/fr

Météo-France - 73 avenue de Paris, 94165 Saint-Mandé cedex - Contact : contact@meteo.fr

Rédigé par Météo-France avec la contribution des observateurs du réseau nivo-météorologiques. Partenariat : ANMSM (Maires de Stations de Montagne), DSF (Domaines Skiables de France), ADSP (Directeurs de Pistes et de la Sécurité des Stations de Sports d'Hiver) et autres acteurs de la montagne.

Bulletin neige & avalanches par téléphone au

0 892 68 10 20 Service 0,35 € / min + prix appel

RÉPUBLIQUE FRANÇAISE
Liberté Égalité Fraternité

METEO FRANCE
À VOS CÔTÉS, DANS UN CLIMAT QUI CHANGE

Bulletin d'estimation du risque d'avalanche

(valable en dehors des pistes balisées et ouvertes)

MASSIF : Capcir Puymorens

Rédigé le samedi 21 février 2026 à 16h

Conditions nivo-météo des 7 derniers jours

	dim. 15/02				lun. 16/02				mar. 17/02				mer. 18/02				jeu. 19/02				ven. 20/02				sam. 21/02			
	03h	09h	15h	21h	03h	09h	15h	21h	03h	09h	15h	21h	03h	09h	15h	21h	03h	09h	15h	21h	03h	09h	15h	21h	03h	09h	15h	21h
Météo																												
Vent (km/h)	105	80	70	70	95	100	105	120	120	110	90	75	65	55	70	80	80	70	70	75	65	65	55	50	45	35	30	25
à 3000m																												
Vent (km/h)	80	45	50	60	50	65	80	85	85	65	50	40	30	25	35	50	75	60	60	65	60	60	40	30	25	20	20	15
à 2000m																												

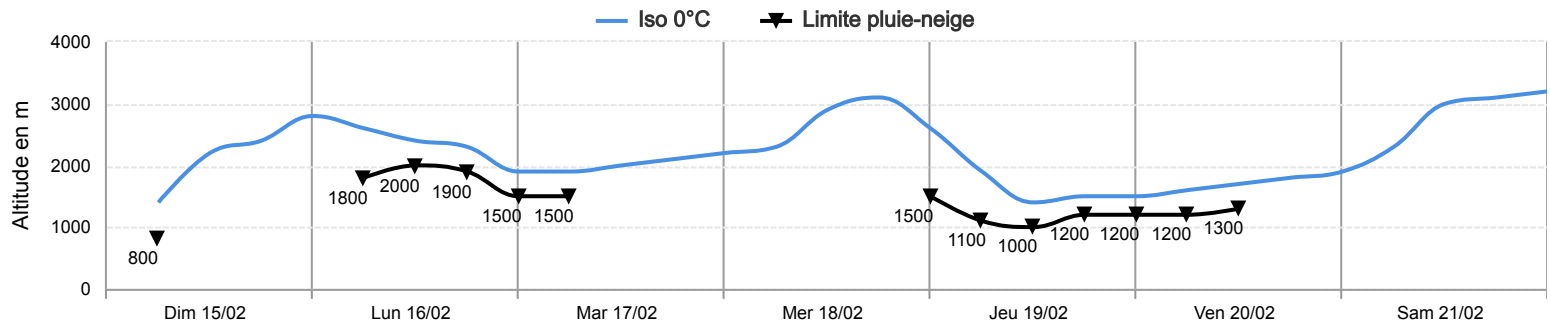

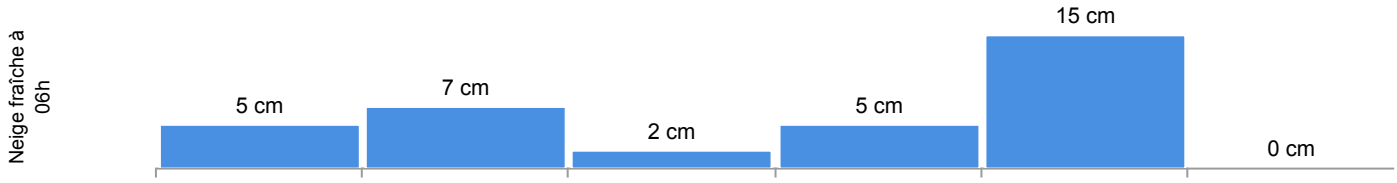

Risque d'avalanche	dim. 15/02	lun. 16/02	mar. 17/02	mer. 18/02	jeu. 19/02	ven. 20/02	sam. 21/02
	4	4	4	3	3	3	3

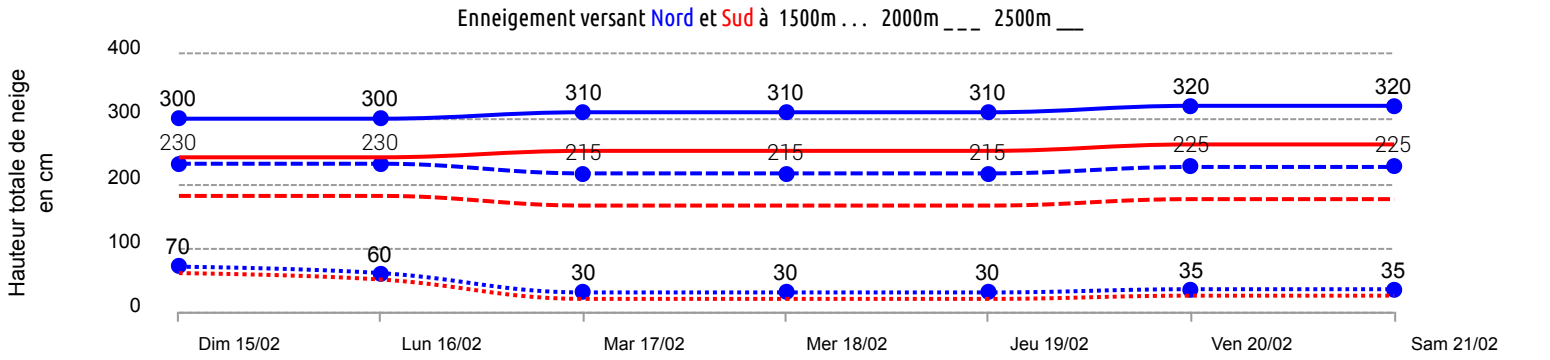

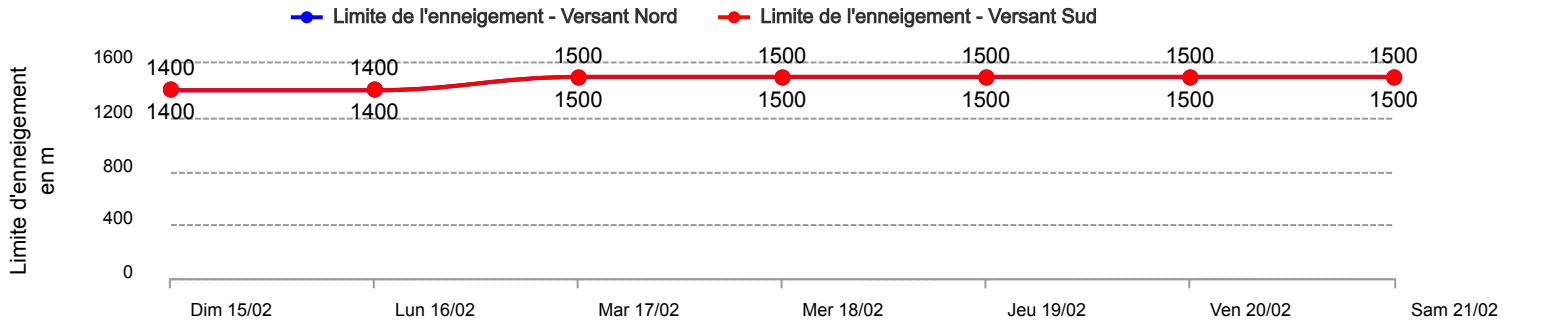

Pour consulter la vigilance en cours, veuillez vous rendre sur le site https://vigilance.meteofrance.fr/fr

Météo-France - 73 avenue de Paris, 94165 Saint-Mandé cedex - Contact : contact@meteo.fr

Rédigé par Météo-France avec la contribution des observateurs du réseau nivo-météorologiques. Partenariat : ANMSM (Maires de Stations de Montagne), DSF (Domaines Skiables de France), ADSP (Directeurs de Pistes et de la Sécurité des Stations de Sports d'Hiver) et autres acteurs de la montagne.

Bulletin neige & avalanches par téléphone au
0 892 68 10 20 Service 0,35 € / min + prix appel