Bulletin d'estimation du risque d'avalanche

(valable en dehors des pistes balisées et ouvertes)

MASSIF : Champsaur

Rédigé le samedi 21 février 2026 à 16h

Estimation des risques pour le : DIMANCHE 22 FÉVRIER

MANTEAU NEIGEUX ENCORE PEU STABILISÉ : PLAQUES FRÉQUENTES ET LOCALEMENT ÉPAISSES + ACTIVITÉ NATURELLE EN NEIGE HUMIDE AU SOLEIL

3

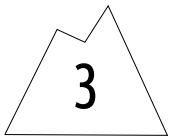

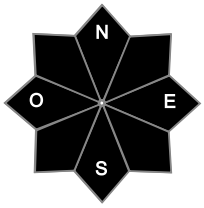

Indice de risque marqué.

Départs spontanés : en plaque / en neige humide au soleil.

Déclenchements provoqués : plaques pouvant être volumineuses.

Indices de risque : 5 très fort - 4 fort - 3 marqué - 2 limité - 1 faible -- En noir : les pentes les plus dangereuses

Stabilité du manteau neigeux

Situation avalancheuse typique : neige ventée couche fragile persistante

Déclenchements provoqués : les plaques formées par le vent de nord-ouest des derniers jours sont encore faciles à déclencher. Elles se trouvent dans les accumulations derrière les bosses, les ruptures de pentes, même loin en contrebas des crêtes là où le vent a soufflé fort. Avalanches petites à moyennes (taille 1 à 2).
Ponctuellement, les cassures sont nettement plus épaisses et emportent la quasi-totalité du manteau neigeux en place, engendrant alors des grandes avalanches (taille 3). Déclenchement plus difficile, mais propagation de la cassure possible sur une grande largeur, essentiellement en ubacs. Le départ d'une première avalanche de surface augmente la probabilité de faire partir l'une de ces plaques volumineuses reposant sur des couches fragiles persistantes enfouies vers la base du manteau neigeux.

Départs spontanés : - dans les versants au soleil, avalanches de neige humide de plus en plus fréquentes au fil de la journée, départs surtout près des rochers. Ces avalanches mobilisent plutôt la neige de surface à haute altitude, mais elles finissent par emporter des volumes de neige nettement plus conséquents sous 2000/2200 m environ, en emportant parfois une grande partie de la neige en place à basse altitude. Avalanche moyennes voire grandes (taille 2 à 3) quand la topographie est favorable, et pouvant descendre à basse altitude dans les couloirs habituels.
- près des crêtes/sommets, encore quelques départs de plaques suite au transport de neige par le vent, au passage de boulettes/avalanches superficielles de neige humide, ou à la chute d'une corniche.

Qualité de la neige

L'enneigement est excédentaire pour un mois de février.
Hauteurs de neige observées : 90 cm au hameau des Portes dans le Valgaudemar à 1270 m, 190 cm à la Nivôse d'Orcières à 2280 m, et 210 cm au-dessus de Prapic à 2480 m.

Limite d'enneigement skiable : la plupart des itinéraires sont skiables dès les fonds de vallées en ubacs, plutôt 1400/1500 m en adrets.

État de la neige de surface : manteau neigeux souvent bien travaillé par le vent de nord qui a cartonné ou durci de nombreuses pentes d'altitude. Enneigement hétérogène près des hautes crêtes avec d'importantes accumulations et corniches qui côtoient des secteurs décapés par le vent.
La neige de surface reste froide et plus légère dans les ubacs abrités, elle est souvent en cycle printanier dans les adrets (croûtée le matin, puis humidification au soleil en journée).

Aperçu météo pour le dimanche 22 février

	nuit	matin	après-midi	soir

Conditions printanières au soleil, quelques voiles nuageux d'altitude. Encore un peu de vent de nord-ouest sur les plus hauts sommets du massif.

Pluie-Neige				
Iso 0 °C	3 000 m	3 000 m	3 000 m	3 100 m
Vent 2000 m	↓ 15 km/h	↘ 10 km/h	↘ 15 km/h	↓ 15 km/h
Vent 3000 m	↓ 45 km/h	↘ 30 km/h	→ 30 km/h	↓ 35 km/h

Épaisseur de neige hors-piste

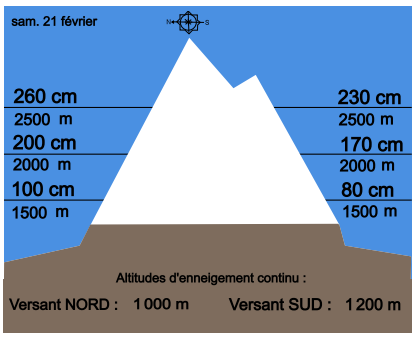

Précipitations à 1800 m

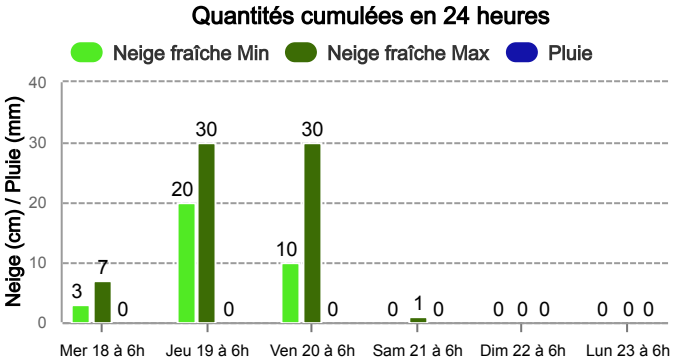

Tendance du lundi 23 février

3

Indice de risque marqué

Le manteau neigeux reste encore assez instable : présence de plaques pouvant être épaisses + activité naturelle en neige humide à des altitudes de plus en plus élevées.

Pour consulter la vigilance en cours, veuillez vous rendre sur le site https://vigilance.meteofrance.fr/fr

Météo-France - 73 avenue de Paris, 94165 Saint-Mandé cedex - Contact : contact@meteo.fr

Rédigé par Météo-France avec la contribution des observateurs du réseau nivo-météorologiques. Partenariat : ANMSM (Maires de Stations de Montagne), DSF (Domaines Skiables de France), ADSP (Directeurs de Pistes et de la Sécurité des Stations de Sports d'Hiver) et autres acteurs de la montagne.

Bulletin neige & avalanches par téléphone au
0 892 68 10 20 Service 0,35 € / min + prix appel

RÉPUBLIQUE FRANÇAISE
Liberté Égalité Fraternité

METEO FRANCE
À VOS CÔTÉS, DANS UN CLIMAT QUI CHANGE

Bulletin d'estimation du risque d'avalanche

(valable en dehors des pistes balisées et ouvertes)

MASSIF : Champsaur

Rédigé le samedi 21 février 2026 à 16h

Conditions nivo-météo des 7 derniers jours

	dim. 15/02				lun. 16/02				mar. 17/02				mer. 18/02				jeu. 19/02				ven. 20/02				sam. 21/02			
	03h	09h	15h	21h	03h	09h	15h	21h	03h	09h	15h	21h	03h	09h	15h	21h	03h	09h	15h	21h	03h	09h	15h	21h	03h	09h	15h	21h
Météo																												
Vent (km/h)	60	70	50	40	80	100	130	120	105	95	80	75	45	30	25	50	45	50	65	60	75	70	70	60	60	60	60	55
à 3000m	↓	↓	↘	→	→	→	→	→	→	↘	↘	↘	↘	↘	↗	↗	↗	↘	↘	↘	↘	↓	↓	↓	↓	↓	↓	↓
Vent (km/h)	20	15	25	25	30	65	80	70	70	50	45	25	20	15	15	25	45	45	45	50	55	45	40	40	35	45	40	30
à 2000m	↓	↙	↘	↘	→	→	→	→	↘	↘	↘	↘	↘	↘	→	↖	↖	↘	↘	↘	↘	↓	↓	↓	↓	↓	↓	↓

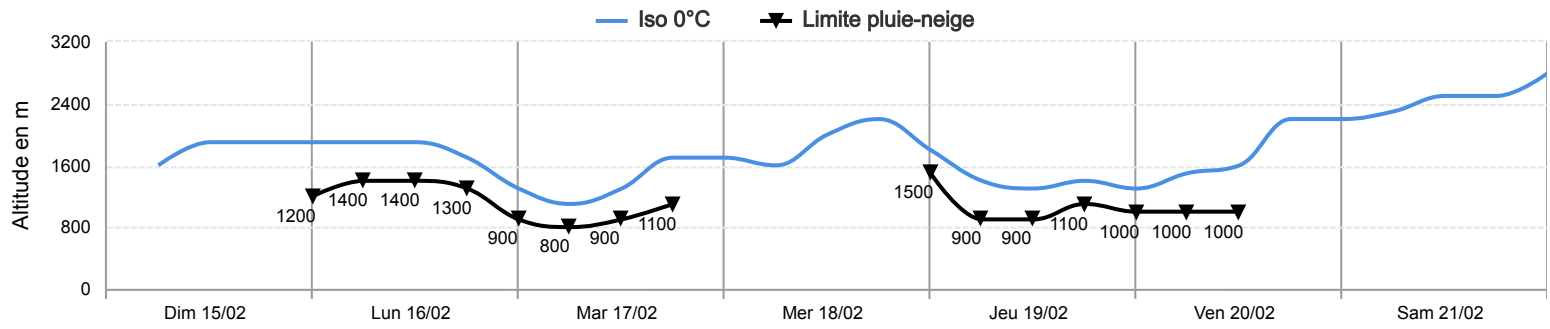

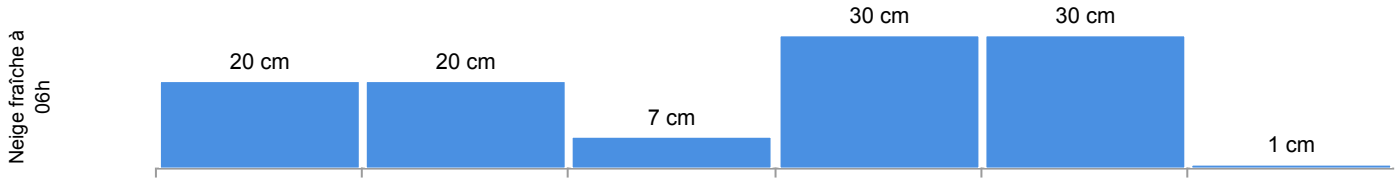

Risque d'avalanche							
	dim. 15/02	lun. 16/02	mar. 17/02	mer. 18/02	jeu. 19/02	ven. 20/02	sam. 21/02

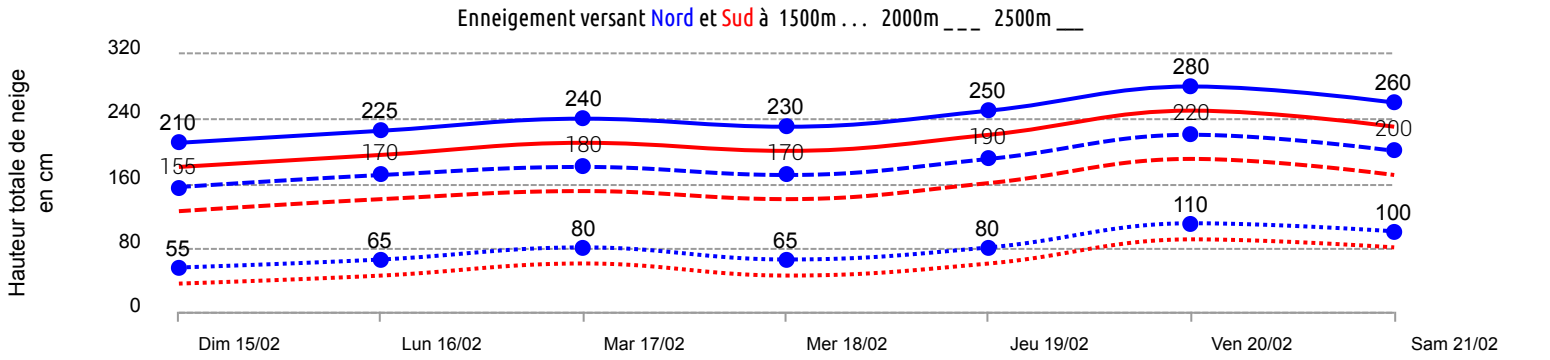

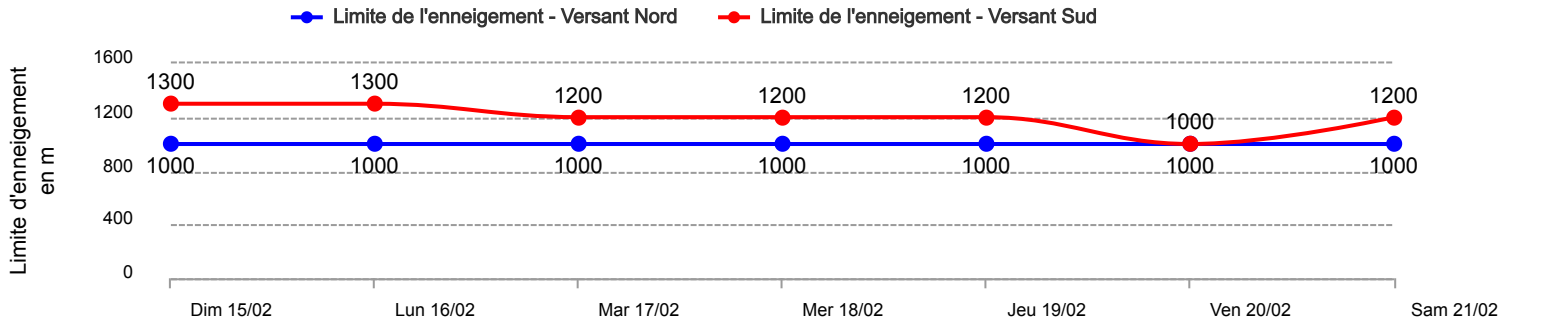

Pour consulter la vigilance en cours, veuillez vous rendre sur le site https://vigilance.meteofrance.fr/fr

Météo-France - 73 avenue de Paris, 94165 Saint-Mandé cedex - Contact : contact@meteo.fr

Rédigé par Météo-France avec la contribution des observateurs du réseau nivo-météorologiques. Partenariat : ANMSM (Maires de Stations de Montagne), DSF (Domaines Skiables de France), ADSP (Directeurs de Pistes et de la Sécurité des Stations de Sports d'Hiver) et autres acteurs de la montagne.

Bulletin neige & avalanches par téléphone au

0 892 68 10 20 Service 0,35 € / min + prix appel