RÉPUBLIQUE FRANÇAISE
*Liberté Égalité Fraternité*

METEO FRANCE
À VOS CÔTÉS, DANS UN CLIMAT QUI CHANGE

# Bulletin d'estimation du risque d'avalanche
## (valable en dehors des pistes balisées et ouvertes)

# MASSIF : Devoluy

Rédigé le samedi 21 février 2026 à 16h

## Estimation des risques pour le : DIMANCHE 22 FÉVRIER

**MANTEAU NEIGEUX ENCORE PEU STABILISÉ : PLAQUES FRÉQUENTES ET LOCALEMENT ÉPAISSES + ACTIVITÉ NATURELLE EN NEIGE HUMIDE AU SOLEIL**

3

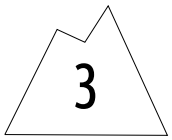


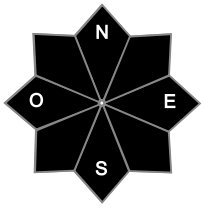


Indice de risque marqué.

**Départs spontanés :** en plaque / en neige humide au soleil.

**Déclenchements provoqués :** plaques pouvant être volumineuses.

Indices de risque : 5 très fort - 4 fort - 3 marqué - 2 limité - 1 faible -- En noir : les pentes les plus dangereuses

## Stabilité du manteau neigeux

**Situation avalancheuse typique :** neige ventée neige humide

**Déclenchements provoqués :** les plaques formées par le vent fort des derniers jours peuvent encore céder au passage d'un seul skieur. On les trouve dans les accumulations même loin des crêtes, derrières les bosses ou les ruptures de pentes. Avalanches petites à moyennes (taille 1 à 2).
Très localement, une grande avalanche (taille 3) reste non exclue en ubacs d'altitude, en cas de rupture sur la couche fragile persistante présente à la base du manteau neigeux. Déclenchement plus difficile, mais pouvant être initié par un premier départ de surface.

**Départs spontanés :** - dans les pentes au soleil, avalanches de neige humide de plus en plus fréquentes au fil de la journée. Elles restent la plupart du temps superficielles vers les plus hauts sommets du massif, mais peuvent finir par mobiliser des volumes de neige conséquents à plus basse altitude (sous 2000/2200 m environ), en emportant parfois tout le manteau neigeux en place. Avalanches moyennes, voire grandes (taille 2 à 3), pouvant descendre à basse altitude dans les couloirs habituels.
- près des crêtes/sommets, encore quelques départs de plaques suite au transport de neige par le vent, au passage de boulettes/avalanches superficielles de neige humide, ou à la chute d'une corniche.

## Qualité de la neige

**L'enneigement** est excédentaire pour un mois de février.

**Limite d'enneigement skiable** : vers 1200 m sur la plupart des itinéraires en ubacs, 1300/1400 m en adrets.

**État de la neige de surface** : manteau neigeux fortement travaillé par le vent de nord qui a cartonné ou durci de nombreuses pentes. Enneigement hétérogène près des hautes crêtes avec d'importantes accumulations et corniches qui côtoient des secteurs décapés par le vent.
La neige de surface reste froide dans les ubacs d'altitude abrités du vent, elle est souvent en cycle printanier dans les adrets (croûtée le matin, puis humidification au soleil en journée).

## Aperçu météo pour le dimanche 22 février

| | nuit | matin | après-midi | soir |
|---|---|---|---|---|
| | | | | |

Conditions printanières au soleil, quelques voiles nuageux d'altitude. Encore un peu de vent de nord-ouest sur les plus hauts sommets du massif.

| Pluie-Neige | | | | |
|---|---|---|---|---|
| Iso 0 °C | 3 000 m | 3 000 m | 3 000 m | 3 100 m |
| Vent 2000 m | ↓ 25 km/h | ↓ 15 km/h | → 15 km/h | ↓ 15 km/h |
| Vent 3000 m | ↓ 40 km/h | ↘ 35 km/h | ↘ 35 km/h | ↘ 40 km/h |

## Épaisseur de neige hors-piste

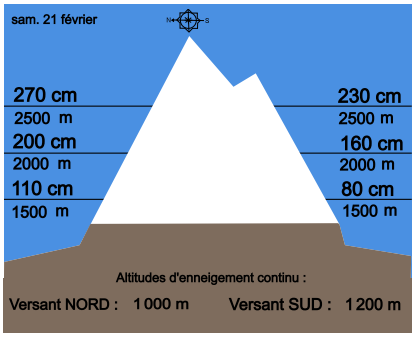


## Précipitations à 1800 m

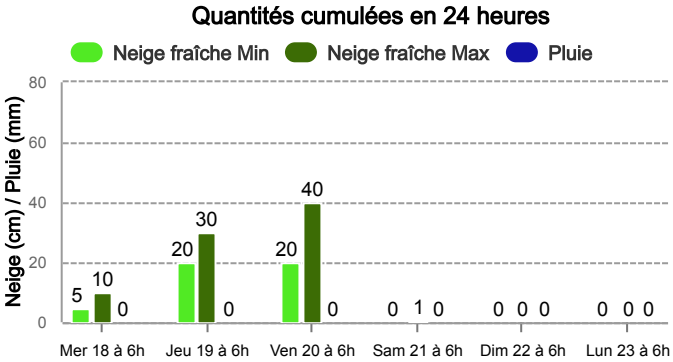


## Tendance du lundi 23 février

3

**Indice de risque marqué**

Le manteau neigeux reste encore assez instable : présence de plaques localement épaisses + activité naturelle en neige humide à des altitudes de plus en plus élevées.

Pour consulter la vigilance en cours, veuillez vous rendre sur le site https://vigilance.meteofrance.fr/fr

Météo-France - 73 avenue de Paris, 94165 Saint-Mandé cedex - Contact : contact@meteo.fr

Rédigé par Météo-France avec la contribution des observateurs du réseau nivo-météorologiques. Partenariat : ANMSM (Maires de Stations de Montagne), DSF (Domaines Skiables de France), ADSP (Directeurs de Pistes et de la Sécurité des Stations de Sports d'Hiver) et autres acteurs de la montagne.

Bulletin neige & avalanches par téléphone au
0 892 68 10 20 Service 0,35 € / min + prix appel

RÉPUBLIQUE FRANÇAISE
*Liberté Égalité Fraternité*

METEO FRANCE
À VOS CÔTÉS, DANS UN CLIMAT QUI CHANGE

# Bulletin d'estimation du risque d'avalanche

## (valable en dehors des pistes balisées et ouvertes)

# MASSIF : Devoluy

Rédigé le samedi 21 février 2026 à 16h

## Conditions nivo-météo des 7 derniers jours

| | dim. 15/02 | | | | lun. 16/02 | | | | mar. 17/02 | | | | mer. 18/02 | | | | jeu. 19/02 | | | | ven. 20/02 | | | | sam. 21/02 | | | |
|---|---|---|---|---|---|---|---|---|---|---|---|---|---|---|---|---|---|---|---|---|---|---|---|---|---|---|---|---|
| | 03h | 09h | 15h | 21h | 03h | 09h | 15h | 21h | 03h | 09h | 15h | 21h | 03h | 09h | 15h | 21h | 03h | 09h | 15h | 21h | 03h | 09h | 15h | 21h | 03h | 09h | 15h | 21h |
| Météo | | | | | | | | | | | | | | | | | | | | | | | | | | | | |
| Vent (km/h) | 90 | 80 | 70 | 50 | 60 | 80 | 120 | 110 | 90 | 80 | 75 | 70 | 50 | 35 | 40 | 65 | 50 | 55 | 70 | 75 | 80 | 90 | 80 | 80 | 80 | 80 | 80 | 60 |
| à 3000m | | | | | | | | | | | | | | | | | | | | | | | | | | | | |
| Vent (km/h) | 70 | 50 | 45 | 30 | 30 | 55 | 70 | 70 | 70 | 60 | 55 | 50 | 40 | 20 | 20 | 45 | 45 | 30 | 40 | 55 | 75 | 60 | 60 | 60 | 45 | 60 | 60 | 40 |
| à 2000m | | | | | | | | | | | | | | | | | | | | | | | | | | | | |

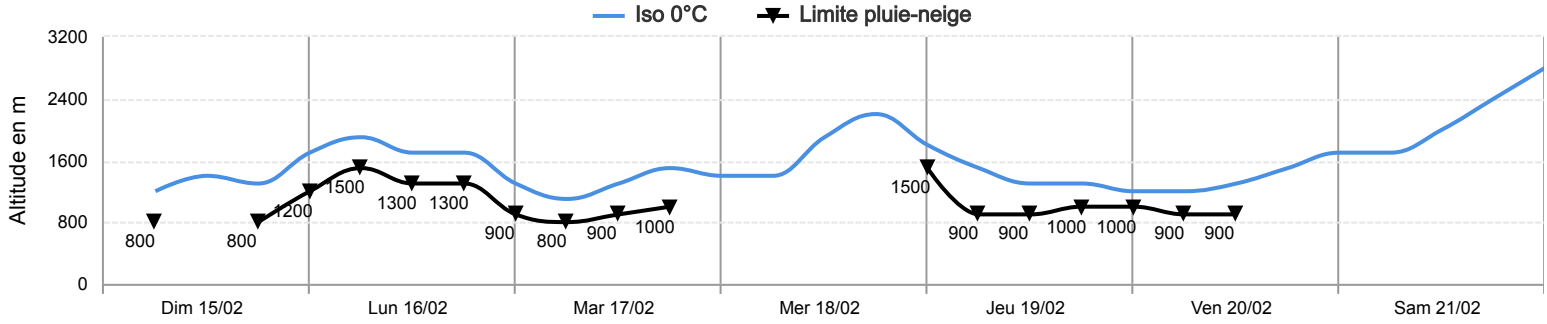


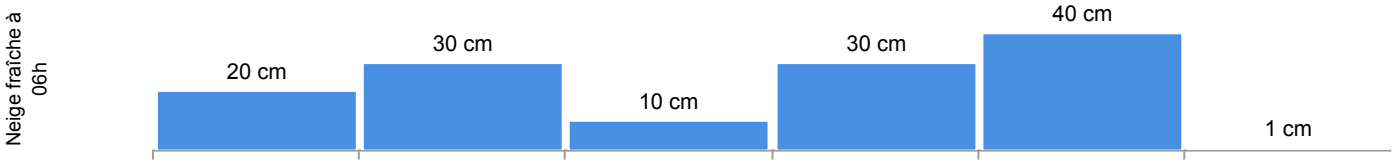


| Risque d'avalanche | dim. 15/02 | lun. 16/02 | mar. 17/02 | mer. 18/02 | jeu. 19/02 | ven. 20/02 | sam. 21/02 |
|---|---|---|---|---|---|---|---|
| | 3 | 3 | 4 | 4 | 4 | 4 | 4 |

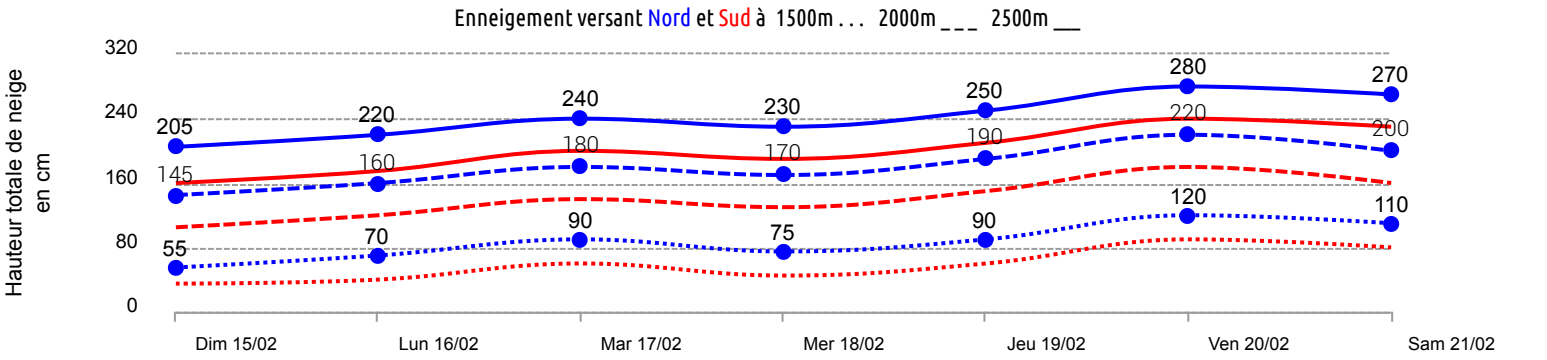


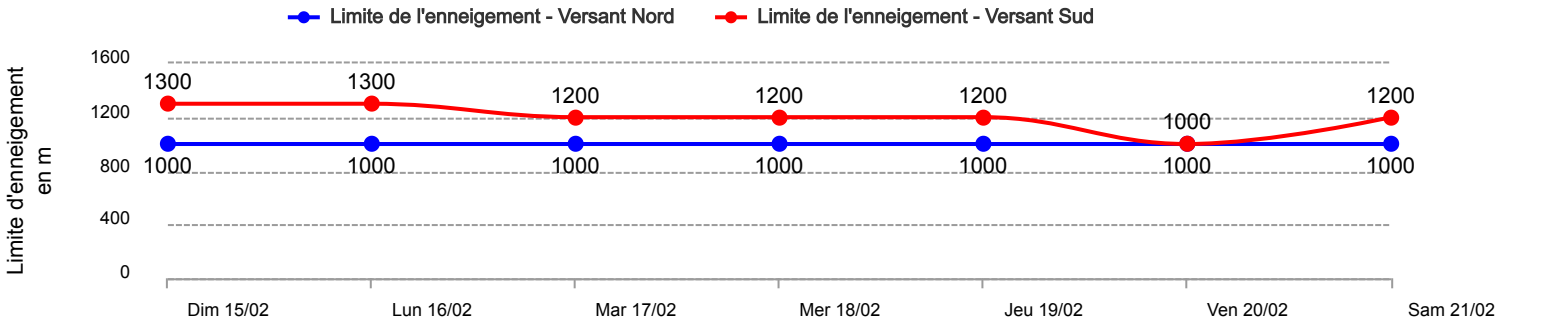


Pour consulter la vigilance en cours, veuillez vous rendre sur le site https://vigilance.meteofrance.fr/fr


Météo-France - 73 avenue de Paris, 94165 Saint-Mandé cedex - Contact : contact@meteo.fr


Bulletin neige & avalanches par téléphone au

0 892 68 10 20 Service 0,35 € / min + prix appel


Rédigé par Météo-France avec la contribution des observateurs du réseau nivo-météorologiques. Partenariat : ANMSM (Maires de Stations de Montagne), DSF (Domaines Skiables de France), ADSP (Directeurs de Pistes et de la Sécurité des Stations de Sports d'Hiver) et autres acteurs de la montagne.