RÉPUBLIQUE FRANÇAISE
Liberté Égalité Fraternité

METEO FRANCE
À VOS CÔTÉS, DANS UN CLIMAT QUI CHANGE

Bulletin d'estimation du risque d'avalanche
(valable en dehors des pistes balisées et ouvertes)
MASSIF : Grandes-Rousses

Rédigé le samedi 21 février 2026 à 16h

Estimation des risques pour le : DIMANCHE 22 FÉVRIER

GROSSES QUANTITÉS DE NEIGE RÉCENTE SOUFFLÉE ET MAL STABILISÉE EN ALTITUDE.

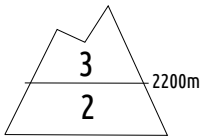

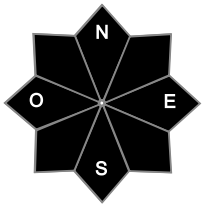

Au-dessus de 2200m indice de risque marqué, plus bas indice limité.

Départs spontanés : Neige humide et plaques de fond dans les adrets.

Déclenchements provoqués : Plaques dures en altitude.

Indices de risque : 5 très fort - 4 fort - 3 marqué - 2 limité - 1 faible -- En noir : les pentes les plus dangereuses

Stabilité du manteau neigeux

Situation avalancheuse typique : neige ventée avalanches de fond

Déclenchements provoqués : Dans les zones abritées du vent à plus de 2200 m, la neige récente est encore insuffisamment stabilisée et reste sensible au passage d'un skieur (plaques friables de taille 2 en général). D'autre part, le vent de nord a transporté d'importantes quantités de neige meuble récemment tombée et de grosses accumulations sont en place. Elles sont plus difficiles à mettre en mouvement par un randonneur, mais en cas de déclenchement, la cassure peut très souvent dépasser 1 mètre.
Départs spontanés : Jusqu'en milieu de nuit de samedi à dimanche, il n'est pas exclu qu'une plaque chargée par la neige rapportée par le vent de nord puisse céder sur la partie haute du massif. En journée de dimanche, le risque concerne surtout la recrudescence des avalanches de fond dans les versants ensoleillés jusqu'à 1800/2200 m, emportant toute la neige jusqu'au sol (taille 1 et 2, rarement 3). Dans les adrets de plus haute altitude, le fort redoux pourrait provoquer des départs spontanés de neige humide.

Qualité de la neige

Qualification de l'enneigement : l'enneigement est bon pour la saison dès 1200 m, puis abondant au dessus de 1500 m environ, notamment dans les combes d'altitude. Les crêtes sont parfois dégarnies ou parfois fortement cornichées.

Limites skiables : vers 1100/1300 m.

Qualité de la neige dimanche : Neige lourde au moins jusqu'à 1800 m, croûtée en début de journée et s'humidifiant rapidement et plus profondément dans les versants ensoleillés. Dans les ubacs d'altitude, la neige est souvent soufflée. Dans les combes abritées du vent, on trouve de grosses quantités de neige profonde.

Aperçu météo pour le dimanche 22 février

	nuit	matin	après-midi	soir
Pluie-Neige				
Iso 0 °C	2 600 m	3 100 m	3 000 m	2 900 m
Vent 2000 m	15 km/h	10 km/h	15 km/h	15 km/h
Vent 3000 m	45 km/h	25 km/h	30 km/h	30 km/h

Épaisseur de neige hors-piste

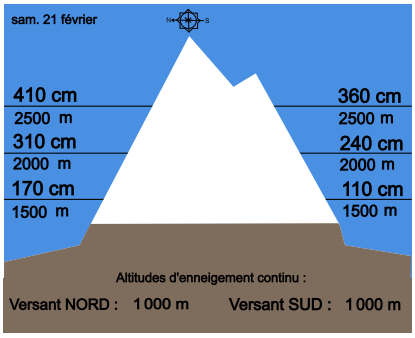

Précipitations à 1800 m

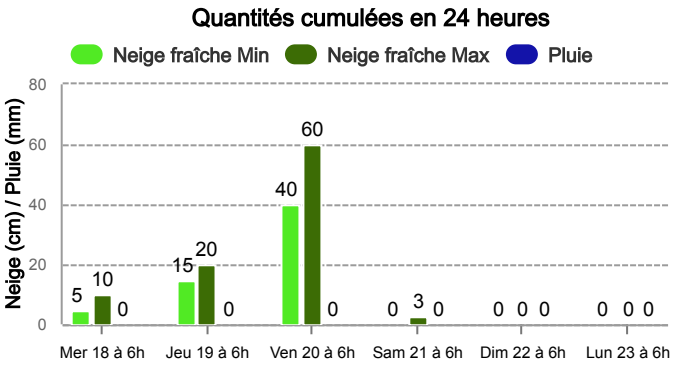

Tendance du lundi 23 février

Indice de risque marqué

Lundi, poursuite du temps ensoleillé et doux entraînant humidification et tassement en moyenne montagne et dans les adrets. Par contre en haute montagne, la stabilisation reste lente et le risque accidentel encore marqué.

Pour consulter la vigilance en cours, veuillez vous rendre sur le site https://vigilance.meteofrance.fr/fr

Météo-France - 73 avenue de Paris, 94165 Saint-Mandé cedex - Contact : contact@meteo.fr

Rédigé par Météo-France avec la contribution des observateurs du réseau nivo-météorologiques. Partenariat : ANMSM (Maires de Stations de Montagne), DSF (Domaines Skiables de France), ADSP (Directeurs de Pistes et de la Sécurité des Stations de Sports d'Hiver) et autres acteurs de la montagne.

Bulletin neige & avalanches par téléphone au
0 892 68 10 20 Service 0,35 € / min + prix appel

RÉPUBLIQUE FRANÇAISE
Liberté Égalité Fraternité

METEO FRANCE
À VOS CÔTÉS, DANS UN CLIMAT QUI CHANGE

Bulletin d'estimation du risque d'avalanche

(valable en dehors des pistes balisées et ouvertes)

MASSIF : Grandes-Rousses

Rédigé le samedi 21 février 2026 à 16h

Conditions nivo-météo des 7 derniers jours

	dim. 15/02				lun. 16/02				mar. 17/02				mer. 18/02				jeu. 19/02				ven. 20/02				sam. 21/02			
	03h	09h	15h	21h	03h	09h	15h	21h	03h	09h	15h	21h	03h	09h	15h	21h	03h	09h	15h	21h	03h	09h	15h	21h	03h	09h	15h	21h
Météo																												
Vent (km/h)	50	45	45	55	70	85	110	120	100	80	60	40	45	30	40	90	55	35	60	60	60	60	60	70	60	55	50	40
à 3000m																												
Vent (km/h)	5	10	25	30	40	60	80	80	70	55	45	25	20	20	20	65	35	20	25	25	35	40	35	40	40	25	25	20
à 2000m																												

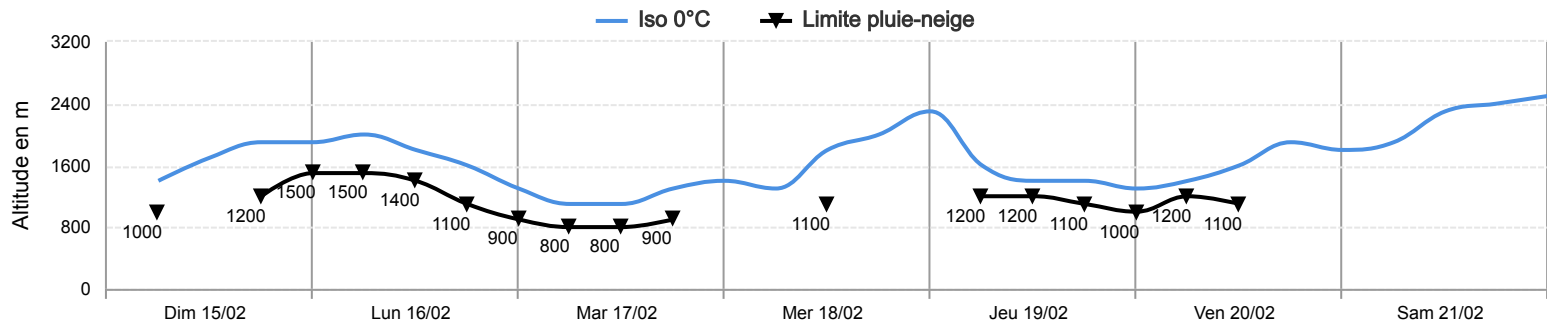

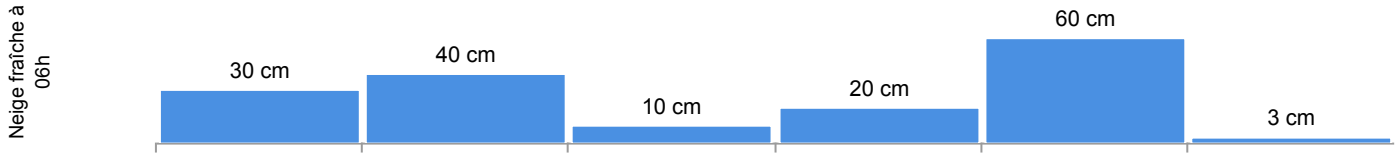

Risque d'avalanche	dim. 15/02	lun. 16/02	mar. 17/02	mer. 18/02	jeu. 19/02	ven. 20/02	sam. 21/02
	3	4	4	4	5	5	4

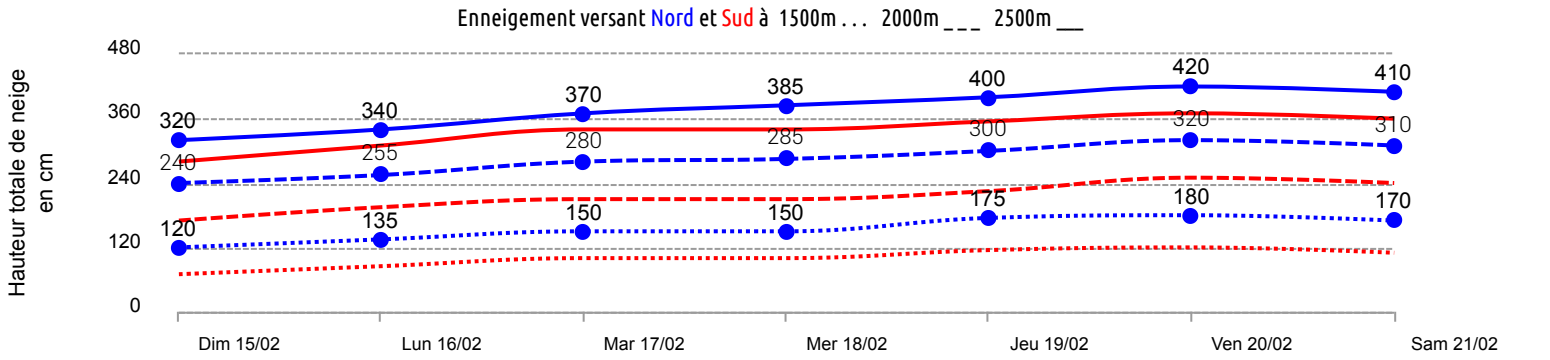

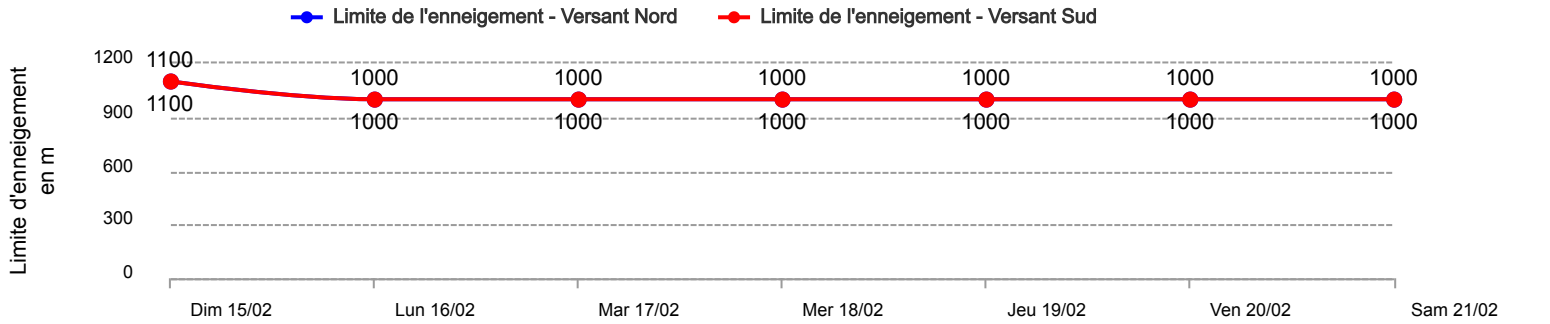

Pour consulter la vigilance en cours, veuillez vous rendre sur le site https://vigilance.meteofrance.fr/fr

Météo-France - 73 avenue de Paris, 94165 Saint-Mandé cedex - Contact : contact@meteo.fr

Rédigé par Météo-France avec la contribution des observateurs du réseau nivo-météorologiques. Partenariat : ANMSM (Maires de Stations de Montagne), DSF (Domaines Skiables de France), ADSP (Directeurs de Pistes et de la Sécurité des Stations de Sports d'Hiver) et autres acteurs de la montagne.

Bulletin neige & avalanches par téléphone au
0 892 68 10 20 Service 0,35 € / min + prix appel