Bulletin d'estimation du risque d'avalanche
(valable en dehors des pistes balisées et ouvertes)
MASSIF : Maurienne

Rédigé le samedi 21 février 2026 à 16h

Estimation des risques pour le : DIMANCHE 22 FÉVRIER

QUELQUES PLAQUES ENCORE PARFOIS TRÈS RÉACTIVES DANS UN MANTEAU PEU STABILISÉ.
REDOUX MARQUÉ CAUSANT DE NOMBREUX DÉPARTS NATURELS EN MOYENNE MONTAGNE.

3

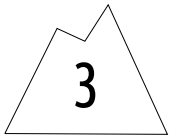

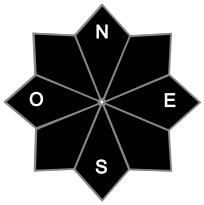

Indice de risque marqué.

Départs spontanés : en journée, nombreux départs (talus et plaques de fond) en basse et moyenne montagne.

Déclenchements provoqués : quelques plaques encore très réactives, parfois de grandes cassures.

Indices de risque : 5 très fort - 4 fort - 3 marqué - 2 limité - 1 faible -- En noir : les pentes les plus dangereuses

Stabilité du manteau neigeux

Situation avalancheuse typique : neige ventée couche fragile persistante

Déclenchements provoqués : on trouve encore **quelques plaques** très **sensibles au passage d'un skieur.** Ces plaques sont **friables à dures**, avec **parfois peu d'indices visuels pour les distinguer**, le vent de nord-ouest ayant plus ou moins contribué à leur formation selon les secteurs. Au vu des forts cumuls de neige récente, les **cassures peuvent être très épaisses** donnant généralement des avalanches de **taille 2 (moyennes)**. On retrouve ces plaques dès 2000/2200 m en nord, beaucoup plus haut et de façon limitée en sud.
Facteur aggravant, au-dessus de 2000 m et en versants froids (Est/Nord/Ouest), les **couches fragiles persistantes enfouies** dans le manteau pourront encore réagir au passage d'un skieur ou en cascade à la suite d'une première plaque : elles engendrent alors de **plus grandes et larges avalanches** (taille 3).

Départs spontanés : le redoux se poursuit, avec un isotherme 0 °C qui atteint 2800 m. On s'attend à :
(1) En tous versants sous 2000/2400 m, de nombreuses plaques de fond et glissements de talus, surtout dans les pentes raides et herbeuses. Les épaisseurs de neige étant notables dès ces moyennes altitudes (100-150 cm), les volumes mobilisés sont conséquents et les avalanches de taille 1 à 2 ainsi engendrées peuvent concerner les routes ou parkings d'altitude.
(2) En Sud jusqu'à haute altitude, quelques départs ponctuels dans la neige fraîche s'humidifiant : les falaises et couloirs raides se purgent sous le soleil. Généralement des tailles 1 (petites) à 2, mais une exceptionnelle avalanche de taille 3 mobilisant en cascade la couche fragile persistante enfouie n'est pas exclue.

Qualité de la neige

Enneigement : excédentaire à toutes les altitudes et dans tous les versants. Les départs classiques de ski de randonnée sont désormais copieusement enneigés. Les trois perturbations qui se sont succédé ont permis d'épaissir le manteau d'en moyenne 1 m vers 2000 m.

Limite skiable : skiable dès 900/1000 m dans les prairies orientées Nord, plutôt 1200/1400 m en Sud pas trop raide.

Qualité de la neige : la neige a subi une humidification superficielle en tous versants sous 2000 m, et même bien plus haut en sud. La neige y est croutée infâme le matin suite au bon regel, puis lourde voire collante en journée. Cette humidification va se poursuivre en sud jusqu'à haute altitude en journée, avec le soleil qui sort pleinement pour la première fois (bottage probable).
En versants ombragés, la neige est globalement très travaillée par le vent, avec des quantités certes importantes mais rendues très hétérogènes (certaines croupes sont quasiment dégarnies).

Aperçu météo pour le dimanche 22 février

	nuit	matin	après-midi	soir

Ciel bleu et redoux marqué, surtout dans les adrets.

Pluie-Neige				
Iso 0 °C	2 400 m	2 900 m	2 900 m	2 700 m
Vent 2000 m	↘ 15 km/h	↘ 10 km/h	↘ 10 km/h	↘ 10 km/h
Vent 3000 m	↘ 40 km/h	↘ 30 km/h	↘ 30 km/h	↘ 30 km/h

Épaisseur de neige hors-piste

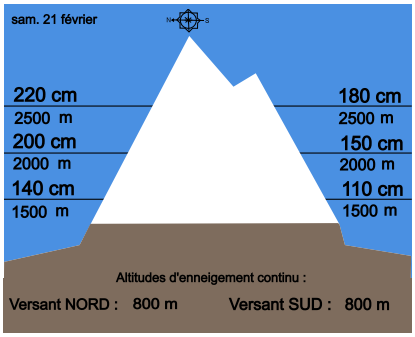

Précipitations à 1800 m

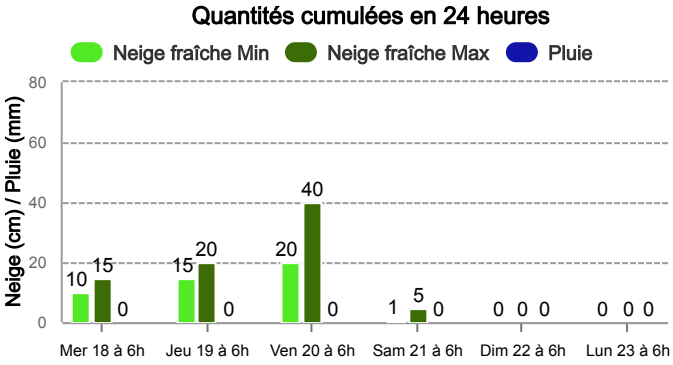

Tendance du lundi 23 février

2

Indice de risque limité

La stabilisation se poursuit efficacement, le risque est "limité" : quelques plaques encore localement réactives en altitude, poursuite de l'humidification au soleil et plaques de fond en moyenne montagne.

Pour consulter la vigilance en cours, veuillez vous rendre sur le site https://vigilance.meteofrance.fr/fr

Météo-France - 73 avenue de Paris, 94165 Saint-Mandé cedex - Contact : contact@meteo.fr

Rédigé par Météo-France avec la contribution des observateurs du réseau nivo-météorologiques. Partenariat : ANMSM (Maires de Stations de Montagne), DSF (Domaines Skiables de France), ADSP (Directeurs de Pistes et de la Sécurité des Stations de Sports d'Hiver) et autres acteurs de la montagne.

Bulletin neige & avalanches par téléphone au
0 892 68 10 20 Service 0,35 € / min + prix appel

Bulletin d'estimation du risque d'avalanche

(valable en dehors des pistes balisées et ouvertes)

MASSIF : Maurienne

Rédigé le samedi 21 février 2026 à 16h

Conditions nivo-météo des 7 derniers jours

	dim. 15/02				lun. 16/02				mar. 17/02				mer. 18/02				jeu. 19/02				ven. 20/02				sam. 21/02			
	03h	09h	15h	21h	03h	09h	15h	21h	03h	09h	15h	21h	03h	09h	15h	21h	03h	09h	15h	21h	03h	09h	15h	21h	03h	09h	15h	21h
Météo																												
Vent (km/h)	65	55	55	50	65	80	90	100	90	70	60	50	45	35	35	50	55	50	65	65	60	55	50	50	50	50	50	50
à 3000m																												
Vent (km/h)	25	15	20	25	35	60	75	80	70	50	40	30	20	15	25	35	40	35	50	50	45	35	30	30	30	20	20	20
à 2000m																												

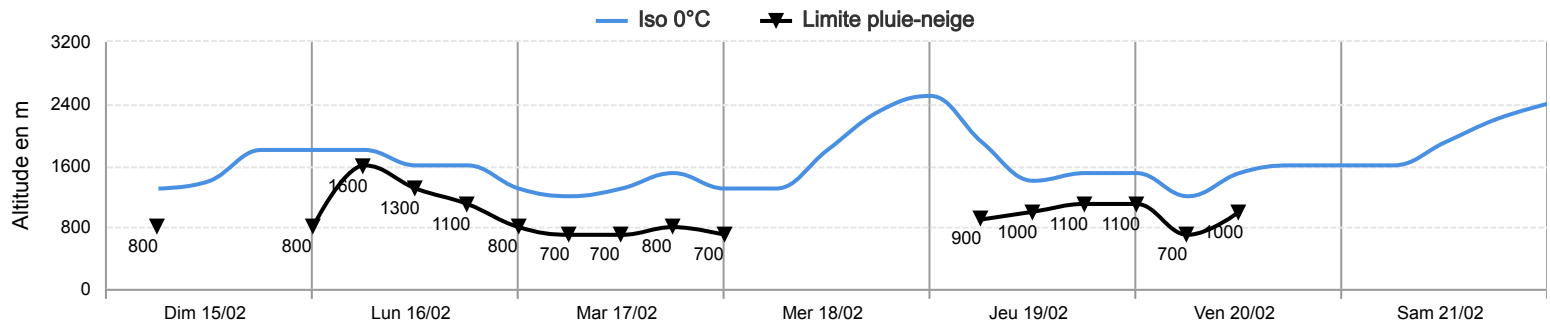

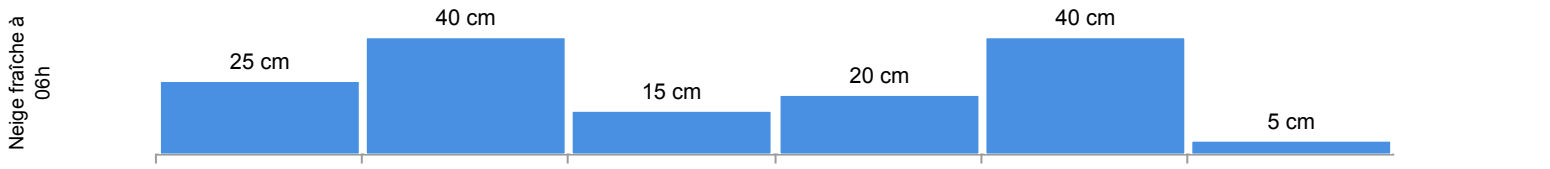

Risque d'avalanche	dim. 15/02	lun. 16/02	mar. 17/02	mer. 18/02	jeu. 19/02	ven. 20/02	sam. 21/02
	3	4	4	4	5	4	4

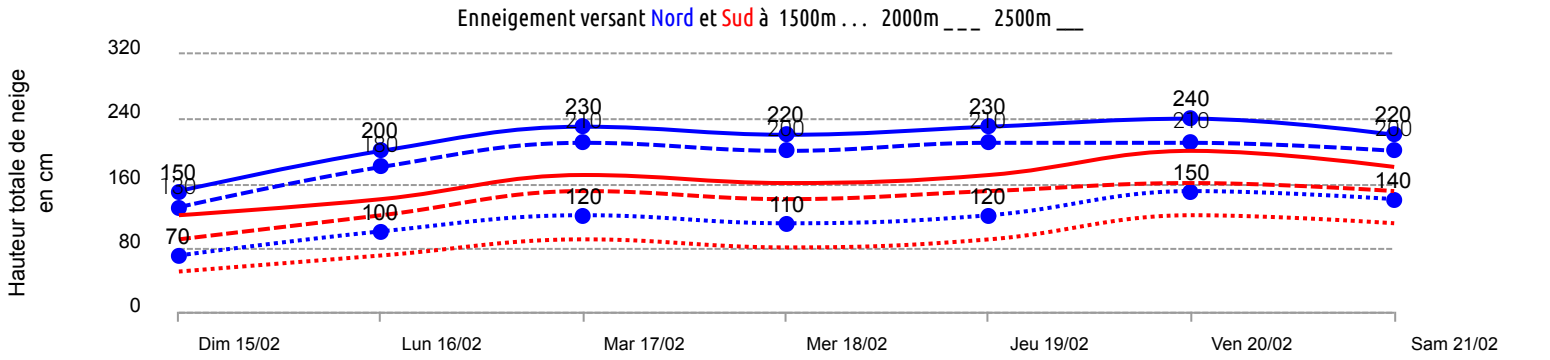

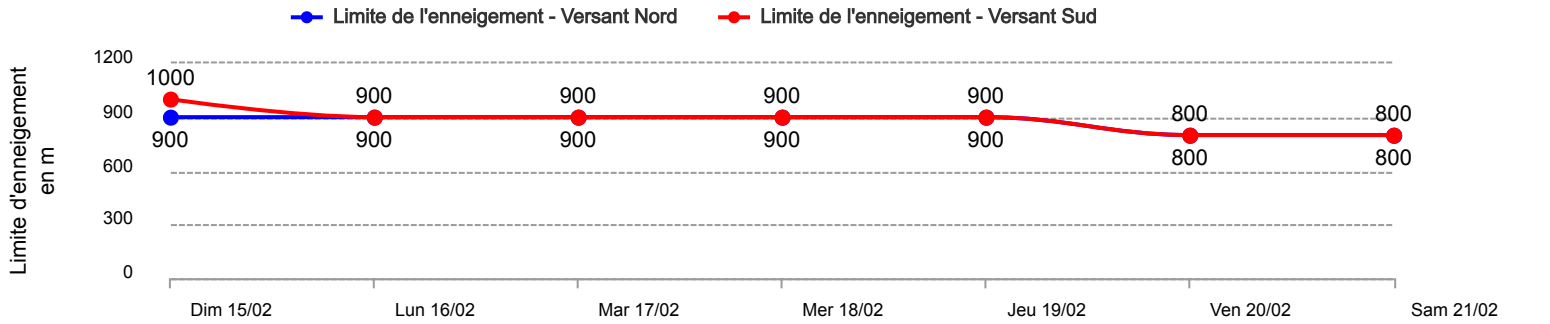

Pour consulter la vigilance en cours, veuillez vous rendre sur le site https://vigilance.meteofrance.fr/fr

Météo-France - 73 avenue de Paris, 94165 Saint-Mandé cedex - Contact : contact@meteo.fr

Rédigé par Météo-France avec la contribution des observateurs du réseau nivo-météorologiques. Partenariat : ANMSM (Maires de Stations de Montagne), DSF (Domaines Skiables de France), ADSP (Directeurs de Pistes et de la Sécurité des Stations de Sports d'Hiver) et autres acteurs de la montagne.

Bulletin neige & avalanches par téléphone au

0 892 68 10 20 Service 0,35 € / min + prix appel