Bulletin d'estimation du risque d'avalanche
(valable en dehors des pistes balisées et ouvertes)

MASSIF : Mercantour

Rédigé le samedi 21 février 2026 à 16h

Estimation des risques pour le : DIMANCHE 22 FÉVRIER

NOMBREUSES PLAQUES DANS LA NEIGE RÉCENTE VENTÉE, DÉPARTS NATURELS EN NEIGE HUMIDE

3

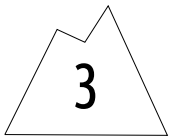

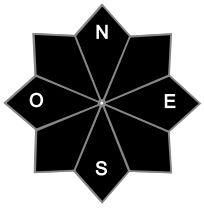

Indice de risque marqué.

Départs spontanés : départs de neige humide devenant nombreux au soleil au fil de la journée

Déclenchements provoqués : instabilités dans la neige récente ventée.

Indices de risque : 5 très fort - 4 fort - 3 marqué - 2 limité - 1 faible -- En noir : les pentes les plus dangereuses

Stabilité du manteau neigeux

Situation avalancheuse typique : neige ventée neige humide

Déclenchements provoqués :
- instabilités dans la neige récente ventée, possibles en toutes orientations, en particulier au-dessus de 2000 m, même loin des crêtes. Plaques d'aspect variable : en neige durcie par le vent proche des crêtes, parfois friables dans les zones plus abritées, voir même en neige humide en surface en versants ensoleillés d'altitude. Encore faciles à déclencher au passage d'un seul skieur, elles engendrent des avalanches de taille petite voir moyenne (taille 1 à 2), notamment en secteur est à sud.

- des départs sous les skis de neige fortement humidifiée sont possibles en versant raides ensoleillés en cours de journée, plutôt en dessous de 2200/2400 m. Avalanches de taille petite à moyenne (taille 1 à 2)

Départs spontanés : départs ponctuels par humidification du manteau neigeux : peu probables en début de journée, puis devenant fréquents en cours de journée, en pentes raides ensoleillées à toutes altitudes, notamment près des rochers. Avalanches de taille petite à moyenne (taille 1 à 2), rarement grande (taille 3), notamment en dessous de 2200/2400 m où le manteau est humidifié en profondeur.

Rares avalanches possibles à la suite d'une rupture de corniche ou de reptation en cours d'ouvertures. Taille moyenne à grande (taille 2 à 3).

Qualité de la neige

Enneigement très excédentaire pour un mois de février. Il faut remonter à 2015 pour trouver un enneigement encore plus abondant à cette période de l'année.
Données observées : 155 cm à la nivôse de Millefonts à 2430 m.

Enneigement skiable dès 1300 m en ubacs en terrains favorables et 1600 m en adrets

État de la neige en surface : neige récente le plus souvent travaillée par le vent de nord, parfois poudreuse dans les ubacs abrités du vent. Neige croutée en versant ensoleillé le matin jusqu'à 2500/2700 m, puis l'humidification reprend en journée et gagne en profondeur avec la hausse des températures. Zones dégarnies par le vent proches des crêtes, alternant avec des corniches parfois épaisses.

Aperçu météo pour le dimanche 22 février

	nuit	matin	après-midi	soir

Temps sec, très doux, avec des passages de nuages élevés.

Pluie-Neige				
Iso 0 °C	2 900 m	3 200 m	3 400 m	3 500 m
Vent 2000 m	↘ 15 km/h	↘ 15 km/h	↘ 20 km/h	↘ 15 km/h
Vent 3000 m	↘ 30 km/h	↘ 35 km/h	↘ 45 km/h	↘ 50 km/h

Épaisseur de neige hors-piste

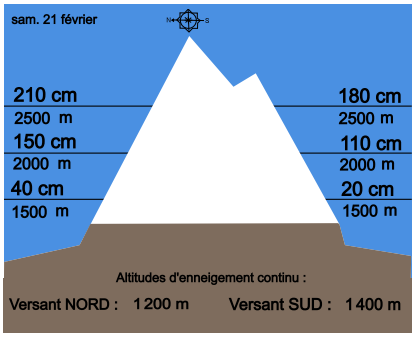

Précipitations à 1800 m

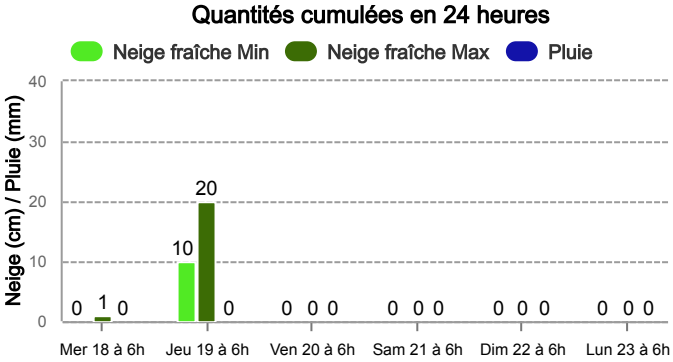

Tendance du lundi 23 février

3

Indice de risque marqué

Risque restant marqué, avec encore quelques plaques sensibles dans la neige ventée, et des départs localement volumineux au soleil.

Pour consulter la vigilance en cours, veuillez vous rendre sur le site https://vigilance.meteofrance.fr/fr

Météo-France - 73 avenue de Paris, 94165 Saint-Mandé cedex - Contact : contact@meteo.fr

Rédigé par Météo-France avec la contribution des observateurs du réseau nivo-météorologiques. Partenariat : ANMSM (Maires de Stations de Montagne), DSF (Domaines Skiables de France), ADSP (Directeurs de Pistes et de la Sécurité des Stations de Sports d'Hiver) et autres acteurs de la montagne.

Bulletin neige & avalanches par téléphone au **0 892 68 10 20** Service 0,35 € / min + prix appel

RÉPUBLIQUE FRANÇAISE
Liberté Égalité Fraternité

METEO FRANCE
À VOS CÔTÉS, DANS UN CLIMAT QUI CHANGE

Bulletin d'estimation du risque d'avalanche
(valable en dehors des pistes balisées et ouvertes)

MASSIF : Mercantour

Rédigé le samedi 21 février 2026 à 16h

Conditions nivo-météo des 7 derniers jours

	dim. 15/02				lun. 16/02				mar. 17/02				mer. 18/02				jeu. 19/02				ven. 20/02				sam. 21/02			
	03h	09h	15h	21h	03h	09h	15h	21h	03h	09h	15h	21h	03h	09h	15h	21h	03h	09h	15h	21h	03h	09h	15h	21h	03h	09h	15h	21h
Météo																												
Vent (km/h)	45	30	40	50	55	75	100	80	75	70	50	40	35	25	35	75	55	55	80	80	75	60	50	30	50	55	50	30
à 3000m																												
Vent (km/h)	30	10	20	30	30	40	65	40	60	50	20	20	15	15	20	40	30	35	35	45	45	40	15	15	15	20	15	20
à 2000m																												

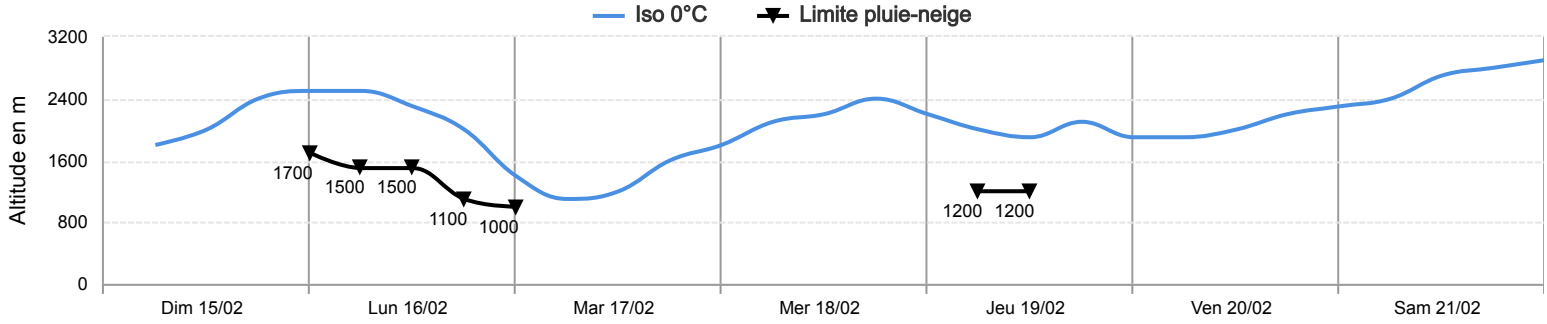

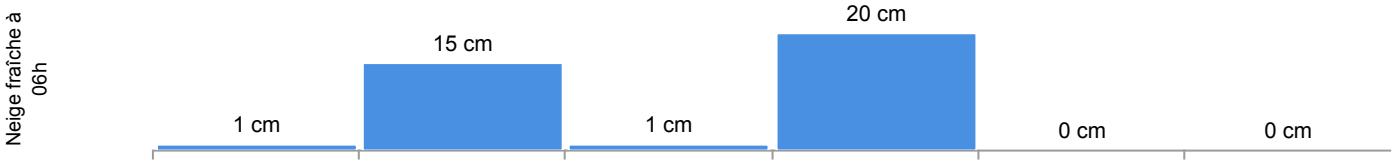

Risque d'avalanche	dim. 15/02	lun. 16/02	mar. 17/02	mer. 18/02	jeu. 19/02	ven. 20/02	sam. 21/02
	3	3	3	3	3	3	3

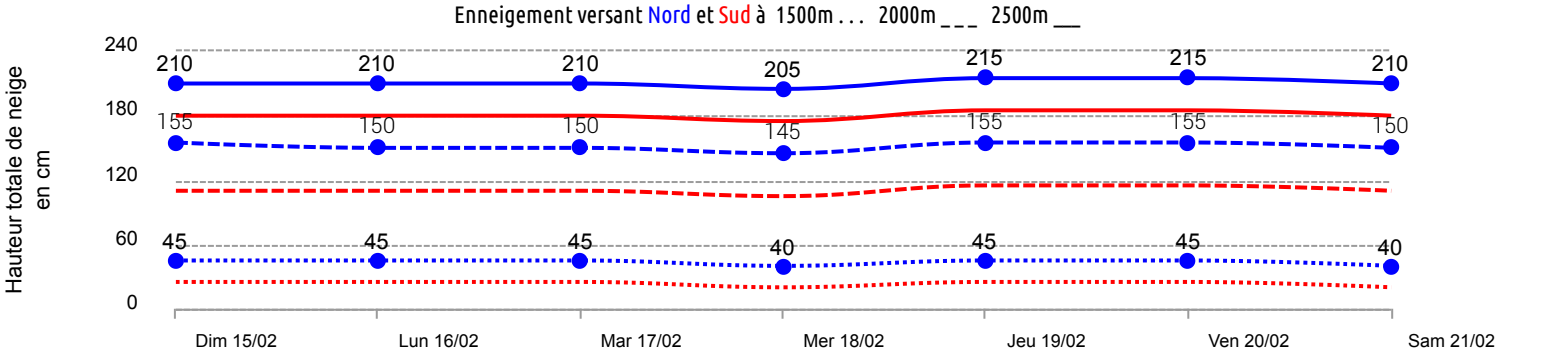

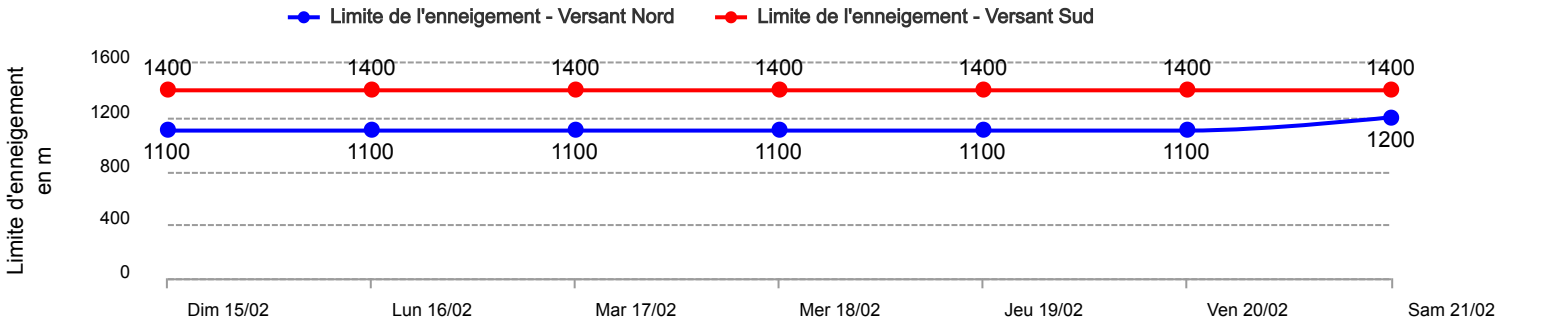

Pour consulter la vigilance en cours, veuillez vous rendre sur le site https://vigilance.meteofrance.fr/fr

Météo-France - 73 avenue de Paris, 94165 Saint-Mandé cedex - Contact : contact@meteo.fr

Rédigé par Météo-France avec la contribution des observateurs du réseau nivo-météorologiques. Partenariat : ANMSM (Maires de Stations de Montagne), DSF (Domaines Skiables de France), ADSP (Directeurs de Pistes et de la Sécurité des Stations de Sports d'Hiver) et autres acteurs de la montagne.

Bulletin neige & avalanches par téléphone au

0 892 68 10 20 Service 0,35 € / min + prix appel