Bulletin d'estimation du risque d'avalanche
(valable en dehors des pistes balisées et ouvertes)

MASSIF : Pays-Basque

Rédigé le samedi 21 février 2026 à 16h

Estimation des risques pour le : DIMANCHE 22 FÉVRIER

NEIGE VENTÉE AU PLUS HAUT DU MASSIF, S'HUMIDIFIANT PROGRESSIVEMENT, HUMIDIFICATION AILLEURS.

2

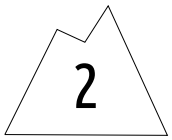

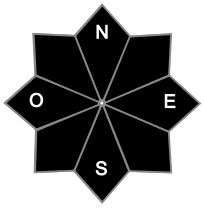

Indice de risque limité.

Départs spontanés : Dans la neige humide.

Déclenchements provoqués : Plaques à vent en altitude.

Indices de risque : 5 très fort - 4 fort - 3 marqué - 2 limité - 1 faible -- En noir : les pentes les plus dangereuses

Stabilité du manteau neigeux

Situation avalancheuse typique : neige ventée neige humide

Déclenchements provoqués : **Au plus haut du massif,** des plaques à vent peuvent encore persister notamment dans les pentes ombragées, issues des chutes de neige précédentes. Elles restent facilement déclenchables par un simple skieur et leur déclenchement peut engendrer des cassures linéaires moyennes à plus rarement grandes. Ces plaques tendent à s'humidifier progressivement au fil de la journée avec la douceur ambiante.
Partout ailleurs, un simple skieur peut déclencher une petite avalanche, parfois une avalanche moyenne dans la neige humide.

Départs spontanés : Des avalanches petites à moyennes sont attendues dans la neige humide, concernant d'abord les pentes raides Est à Sud-Est dans la matinée, puis rapidement tous les versants au fil de la journée et de l'ensoleillement.
Au plus haut du massif, de petites avalanches ou des moyennes sont possibles, par déclenchement des plaques décrites ci-dessus. Ces avalanches peuvent aussi se produire par l'humidification en profondeur du manteau neigeux (avalanche de fond) dans les pentes raides ou bien par chute d'une corniche fragilisée au soleil entraînant la neige en contrebas.

Autres : quelques **reptations possibles** et **apparition de quelques fissures** au **pied des pentes raides** ou proche des **ruptures de pentes**. Corniches en place fragilisées par l'humidification.

Qualité de la neige

Enneigement : en retrait progressif ce dimanche avec la douceur ambiante poursuivant celle de la veille et le soleil qui est bien installé. Il débute vers 1300m en Nord, 1400m en Sud. Crêtes, cols et sommets pelés en expositions Ouest, en neige dure à très dure partout ailleurs.
Limites skiables : à partir de 1300 à 1400m au petit matin suivant les versants, car sans sous-couche en dessous. La neige fond en versants ensoleillés, la limite remonte vers 1500/1600m dans la journée. Fonte plus lente à l'ombre.
État de la neige : Au petit matin, neige travaillée par le vent dans les versants ombragés au plus haut du massif, la neige est dure et regelée partout ailleurs. La neige regelée ramollit au soleil et s'humidifie progressivement. La neige reste le plus souvent en l'état au plus haut du massif dans les secteurs ombragés, très travaillée par le vent.

Aperçu météo pour le dimanche 22 février

	nuit	matin	après-midi	soir
Pluie-Neige				
Iso 0 °C	3 500 m	3 500 m	3 500 m	3 400 m
Vent 1000 m	↑ 15 km/h	↗ 15 km/h	↓ 10 km/h	↓ 5 km/h
Vent 2000 m	↑ 25 km/h	↑ 25 km/h	↗ 25 km/h	→ 25 km/h

Temps sec et bien ensoleillé, quelques passages nuageux d'altitude en cours de journée. Douceur ambiante et vent faible.

Épaisseur de neige hors-piste

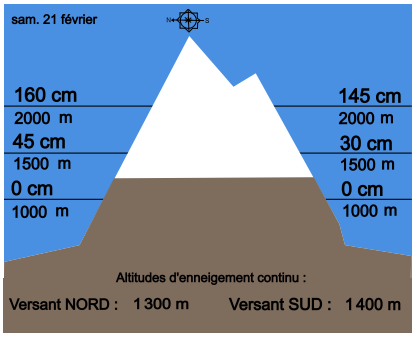

Précipitations à 1800 m

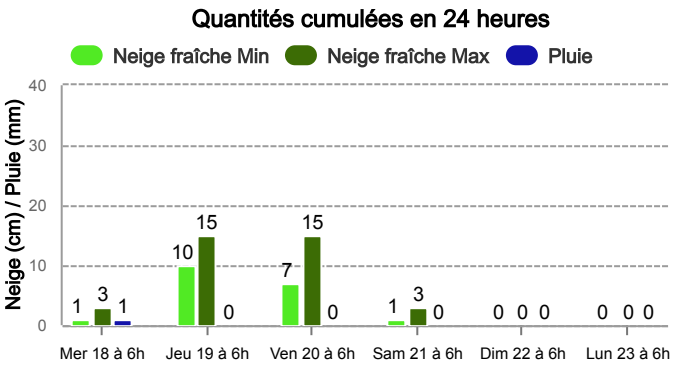

Tendance du lundi 23 février

2

Indice de risque limité

Risque stationnaire. Plaques en altitude, notamment dans les secteurs ombragés, s'humidifiant progressivement. Poursuite de l'humidification ailleurs.

Pour consulter la vigilance en cours, veuillez vous rendre sur le site https://vigilance.meteofrance.fr/fr

Météo-France - 73 avenue de Paris, 94165 Saint-Mandé cedex - Contact : contact@meteo.fr

Rédigé par Météo-France avec la contribution des observateurs du réseau nivo-météorologiques. Partenariat : ANMSM (Maires de Stations de Montagne), DSF (Domaines Skiables de France), ADSP (Directeurs de Pistes et de la Sécurité des Stations de Sports d'Hiver) et autres acteurs de la montagne.

Bulletin neige & avalanches par téléphone au
0 892 68 10 20 Service 0,35 € / min + prix appel

RÉPUBLIQUE FRANÇAISE
Liberté Égalité Fraternité

METEO FRANCE
À VOS CÔTÉS, DANS UN CLIMAT QUI CHANGE

Bulletin d'estimation du risque d'avalanche

(valable en dehors des pistes balisées et ouvertes)

MASSIF : Pays-Basque

Rédigé le samedi 21 février 2026 à 16h

Conditions nivo-météo des 7 derniers jours

	dim. 15/02				lun. 16/02				mar. 17/02				mer. 18/02				jeu. 19/02				ven. 20/02				sam. 21/02			
	03h	09h	15h	21h	03h	09h	15h	21h	03h	09h	15h	21h	03h	09h	15h	21h	03h	09h	15h	21h	03h	09h	15h	21h	03h	09h	15h	21h
Météo																												
Vent (km/h)	40	70	80	85	80	80	70	75	85	50	60	40	45	95	110	90	95	80	55	40	30	20	25	20	20	10	15	20
à 2000m																												
Vent (km/h)	15	15	20	25	35	35	30	35	25	15	20	10	15	40	70	50	55	40	25	15	15	10	15	10	5	2	10	10
à 1000m																												

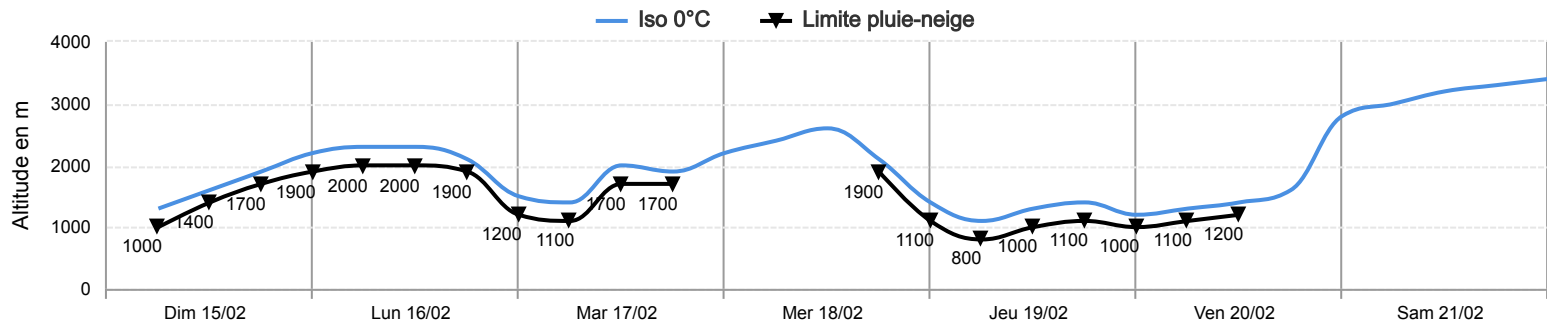

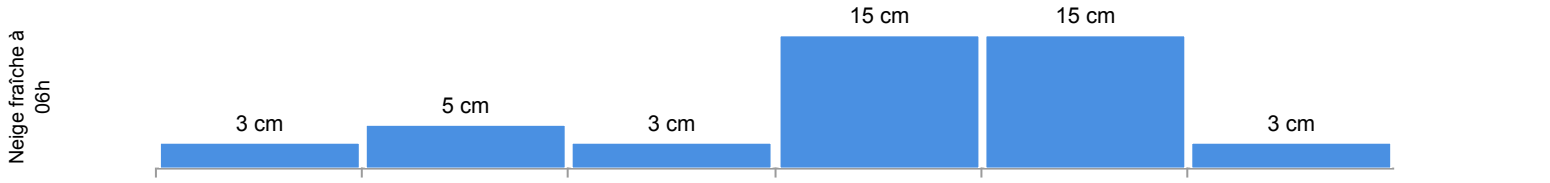

Risque d'avalanche	dim. 15/02	lun. 16/02	mar. 17/02	mer. 18/02	jeu. 19/02	ven. 20/02	sam. 21/02
	3	3	3	2	3	3	3

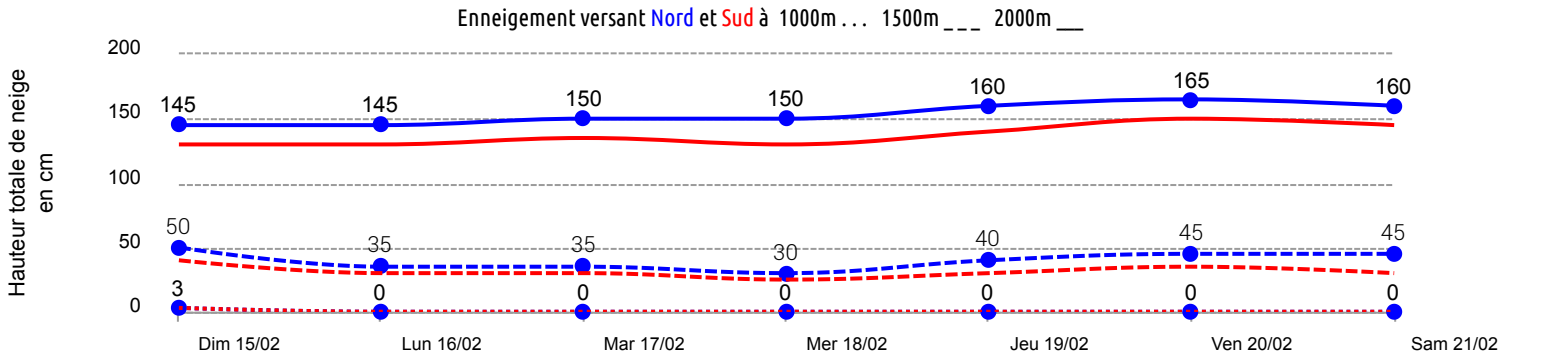

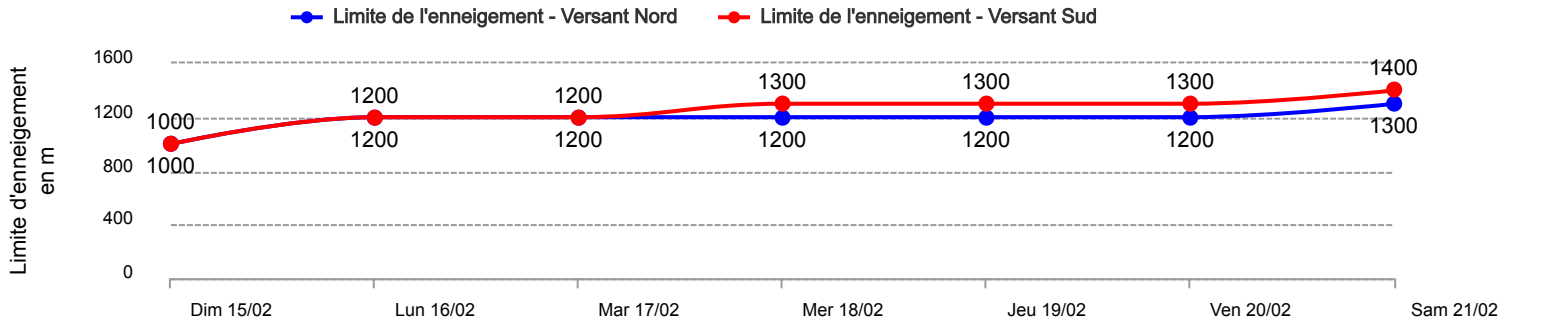

Pour consulter la vigilance en cours, veuillez vous rendre sur le site https://vigilance.meteofrance.fr/fr

Météo-France - 73 avenue de Paris, 94165 Saint-Mandé cedex - Contact : contact@meteo.fr

Rédigé par Météo-France avec la contribution des observateurs du réseau nivo-météorologiques. Partenariat : ANMSM (Maires de Stations de Montagne), DSF (Domaines Skiables de France), ADSP (Directeurs de Pistes et de la Sécurité des Stations de Sports d'Hiver) et autres acteurs de la montagne.

Bulletin neige & avalanches par téléphone au

0 892 68 10 20 Service 0,35 € / min + prix appel