Bulletin d'estimation du risque d'avalanche
(valable en dehors des pistes balisées et ouvertes)

MASSIF : Thabor

Rédigé le samedi 21 février 2026 à 16h

Estimation des risques pour le : DIMANCHE 22 FÉVRIER

SITUATION ENCORE DÉLICATE : PLAQUES POUVANT ÊTRE ÉPAISSES ET ACTIVITÉ NATURELLE EN NEIGE HUMIDE AU SOLEIL

3

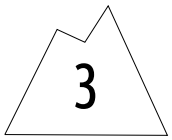

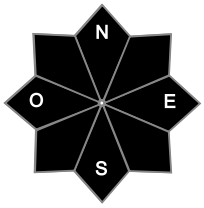

Indice de risque marqué.

Départs spontanés : en plaque / en neige humide au soleil.

Déclenchements provoqués : plaques pouvant être volumineuses.

Indices de risque : 5 très fort - 4 fort - 3 marqué - 2 limité - 1 faible -- En noir : les pentes les plus dangereuses

Stabilité du manteau neigeux

Situation avalancheuse typique : neige ventée couche fragile persistante

Déclenchements provoqués : les plaques formées par le vent de nord-ouest des derniers jours sont encore faciles à déclencher. Elles se trouvent dans les accumulations derrière les bosses, les ruptures de pentes, même loin en contrebas des crêtes là où le vent a soufflé fort. Avalanches petites à moyennes (taille 1 à 2).
Parfois, les cassures sont nettement plus épaisses et emportent la quasi-totalité du manteau neigeux en place, engendrant alors des grandes avalanches (taille 3). Propagation possible de la cassure sur une grande largeur, essentiellement en ubacs. Le départ d'une première avalanche de surface augmente fortement la probabilité de déclencher une plaque volumineuse de ce type, reposant sur des couches fragiles persistantes présentes à la base du manteau neigeux.

Départs spontanés : - dans les pentes ensoleillées, avalanches de neige humide de plus en plus fréquentes au fil de la journée, départs essentiellement près des rochers. Plutôt superficielles à haute altitude, ces avalanches peuvent finir par mobiliser des volumes de neige plus conséquents sous 2000/2200 m. Avalanches moyennes voire grandes (taille 2 à 3) si topographie favorable, et pouvant descendre à basse altitude dans les couloirs habituels.
- près des crêtes/sommets, encore quelques départs de plaques suite au transport de neige par le vent, au passage de boulettes/avalanches superficielles de neige humide, ou à la chute d'une corniche.

Qualité de la neige

L'enneigement est excédentaire pour un mois de février.
Hauteurs de neige observées vers 2500 m : 210 cm dans le vallon du Chardonnet, 150 cm à la Nivôse des Rochilles, 95 cm à la Nivôse du Galibier.

Limite d'enneigement skiable en fond de vallées.

État de la neige de surface : manteau neigeux fortement travaillé par le vent de nord-ouest qui a cartonné ou durci de nombreuses pentes. Enneigement hétérogène près des hautes crêtes avec d'importantes accumulations et corniches qui côtoient des secteurs décapés par le vent.
La neige de surface reste froide et plus légère dans les ubacs abrités du vent, elle est souvent en cycle printanier dans les adrets (croûtée le matin, puis humidification au soleil en journée).

Aperçu météo pour le dimanche 22 février

	nuit	matin	après-midi	soir

Conditions printanières au soleil, quelques voiles nuageux d'altitude. Vent de nord-ouest encore sensible en altitude.

Pluie-Neige				
Iso 0 °C	2 600 m	3 000 m	3 000 m	3 000 m
Vent 2000 m	↘ 25 km/h	↘ 20 km/h	↘ 20 km/h	↘ 20 km/h
Vent 3000 m	↘ 50 km/h	↘ 40 km/h	↘ 40 km/h	↘ 45 km/h

Épaisseur de neige hors-piste

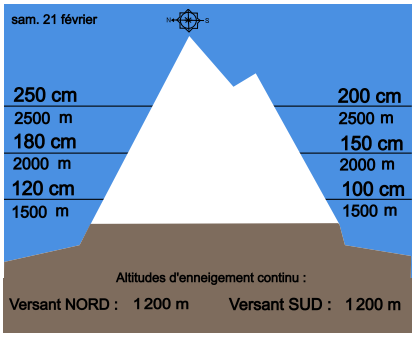

Précipitations à 1800 m

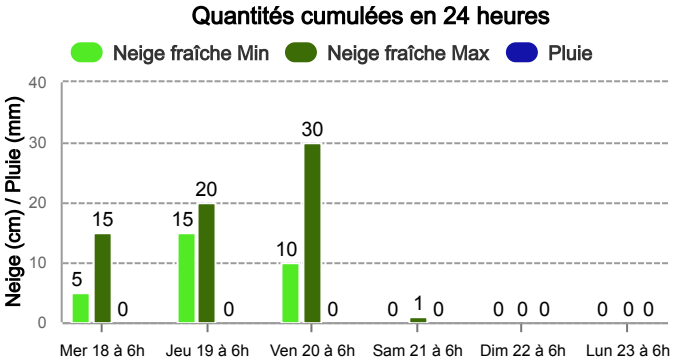

Tendance du lundi 23 février

3

Indice de risque marqué

Le manteau neigeux reste encore assez instable : présence de plaques pouvant être épaisses + activité naturelle en neige humide à des altitudes de plus en plus élevées.

Pour consulter la vigilance en cours, veuillez vous rendre sur le site https://vigilance.meteofrance.fr/fr

Météo-France - 73 avenue de Paris, 94165 Saint-Mandé cedex - Contact : contact@meteo.fr

Rédigé par Météo-France avec la contribution des observateurs du réseau nivo-météorologiques. Partenariat : ANMSM (Maires de Stations de Montagne), DSF (Domaines Skiables de France), ADSP (Directeurs de Pistes et de la Sécurité des Stations de Sports d'Hiver) et autres acteurs de la montagne.

Bulletin neige & avalanches par téléphone au
0 892 68 10 20 Service 0,35 € / min + prix appel

RÉPUBLIQUE FRANÇAISE
Liberté Égalité Fraternité

METEO FRANCE
À VOS CÔTÉS, DANS UN CLIMAT QUI CHANGE

Bulletin d'estimation du risque d'avalanche

(valable en dehors des pistes balisées et ouvertes)

MASSIF : Thabor

Rédigé le samedi 21 février 2026 à 16h

Conditions nivo-météo des 7 derniers jours

	dim. 15/02				lun. 16/02				mar. 17/02				mer. 18/02				jeu. 19/02				ven. 20/02				sam. 21/02			
	03h	09h	15h	21h	03h	09h	15h	21h	03h	09h	15h	21h	03h	09h	15h	21h	03h	09h	15h	21h	03h	09h	15h	21h	03h	09h	15h	21h
Météo																												
Vent (km/h)	80	80	70	40	80	100	120	100	90	80	70	65	70	35	25	40	45	50	60	60	70	60	60	50	70	80	80	60
à 3000m																												
Vent (km/h)	35	40	40	10	40	60	80	70	70	60	60	45	40	25	20	25	25	30	40	45	35	40	35	30	35	45	45	25
à 2000m																												

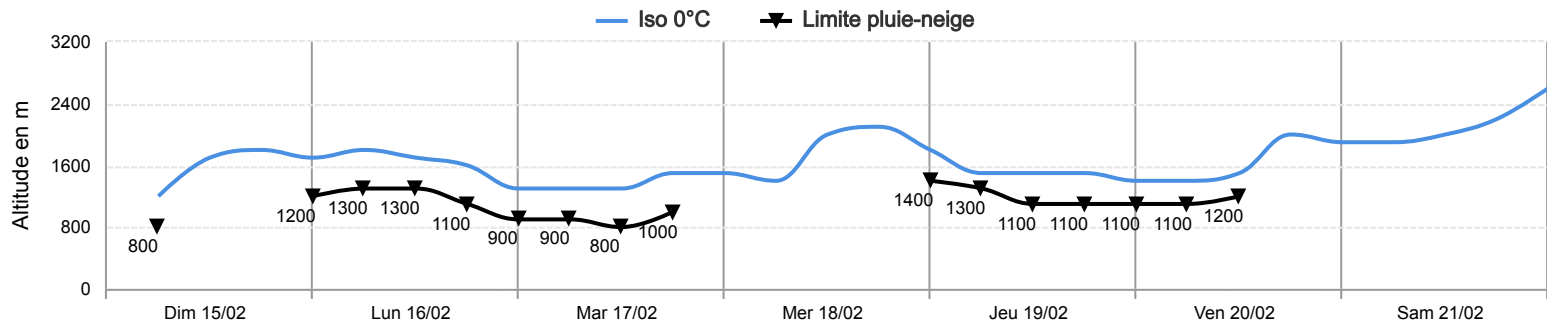

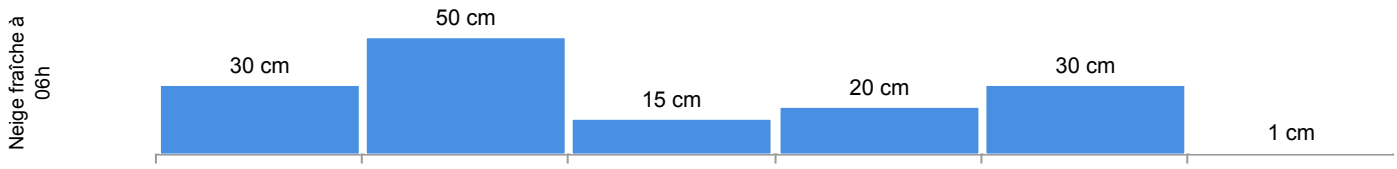

Risque d'avalanche	dim. 15/02	lun. 16/02	mar. 17/02	mer. 18/02	jeu. 19/02	ven. 20/02	sam. 21/02
	3	4	4	4	4	4	4

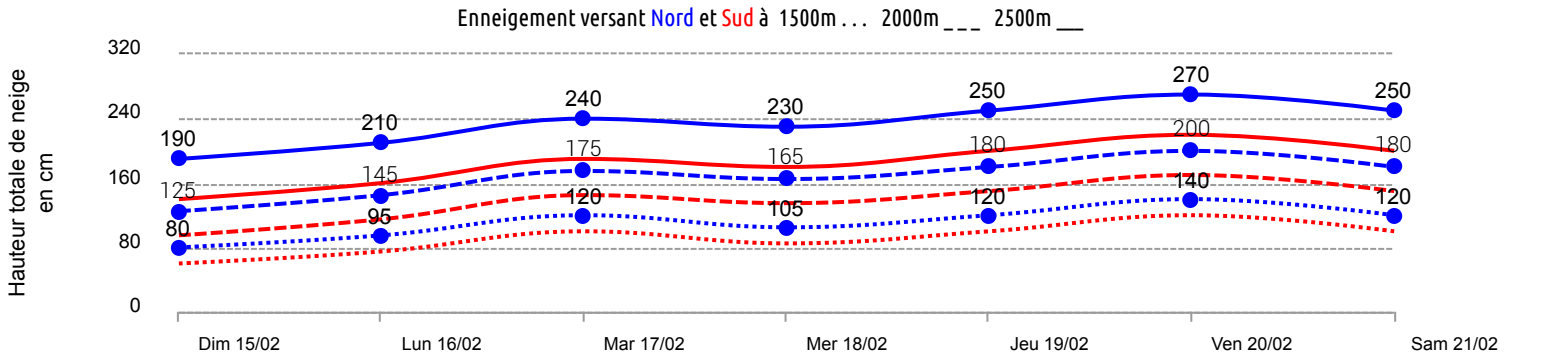

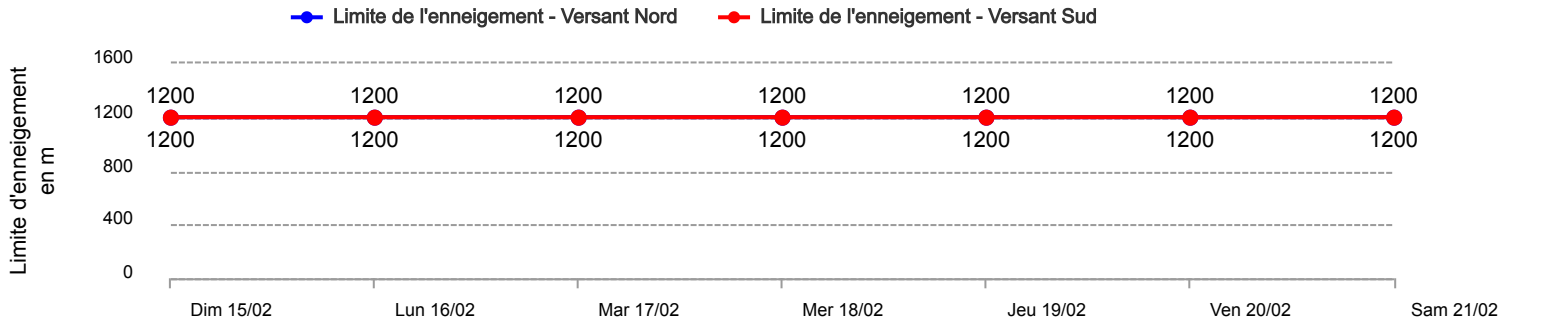

Pour consulter la vigilance en cours, veuillez vous rendre sur le site https://vigilance.meteofrance.fr/fr

Météo-France - 73 avenue de Paris, 94165 Saint-Mandé cedex - Contact : contact@meteo.fr

Rédigé par Météo-France avec la contribution des observateurs du réseau nivo-météorologiques. Partenariat : ANMSM (Maires de Stations de Montagne), DSF (Domaines Skiables de France), ADSP (Directeurs de Pistes et de la Sécurité des Stations de Sports d'Hiver) et autres acteurs de la montagne.

Bulletin neige & avalanches par téléphone au

0 892 68 10 20 Service 0,35 € / min + prix appel