Bulletin d'avalanches jusqu'à dimanche, 22. février 2026

Danger d'avalanche

actualisé le 21.2.2026, 17:00

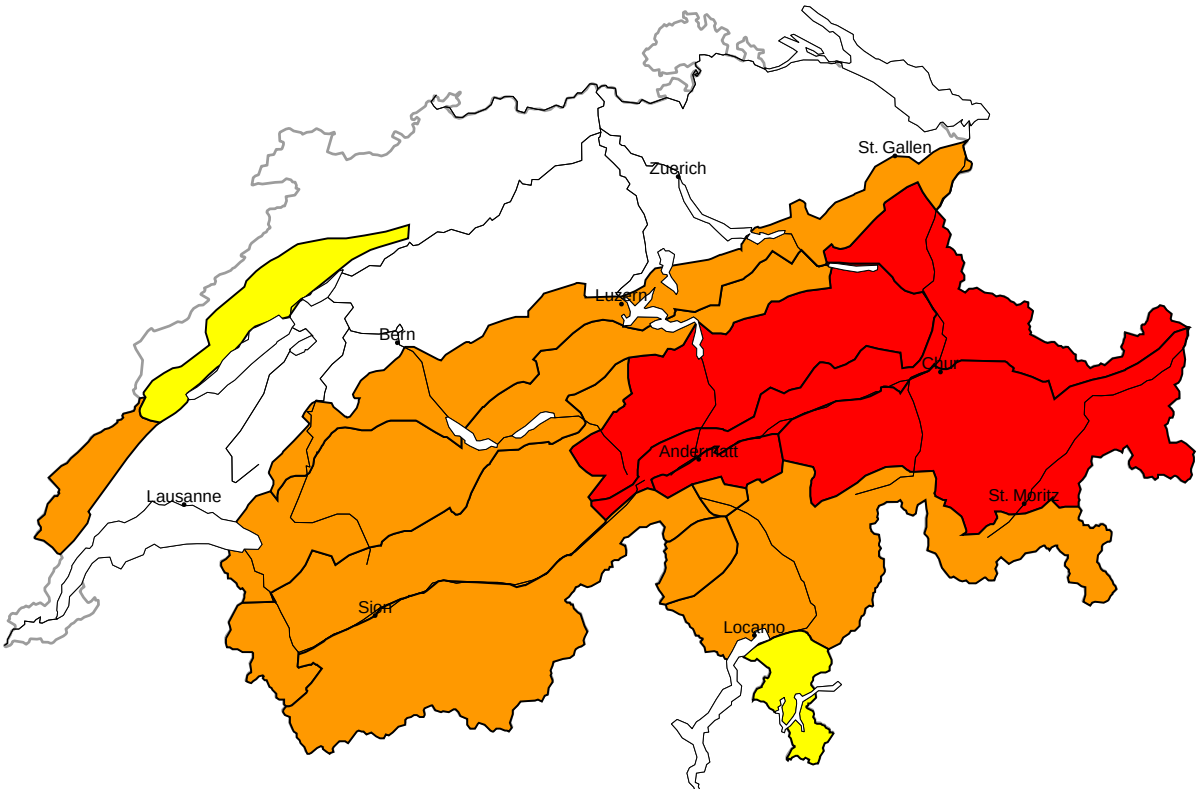

région A — Fort (4=)

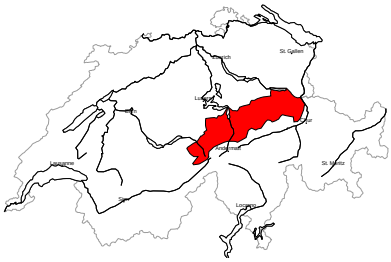

Neige fraîche, Couche fragile persistante

Endroits dangereux

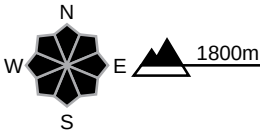

Description des dangers

La neige fraîche abondante et la neige soufflée sont fragiles. Des avalanches spontanées sont à attendre. Elles peuvent atteindre une très grande taille. Des avalanches peuvent avancer jusqu'en vallée dans les parcours d'avalanches typiques. Les voies de communication exposées sont menacées.
Avec la fin des précipitations l'activité des avalanches spontanées diminue. Pour des randonnées et descentes hors-piste en dehors des pistes sécurisées les conditions sont dangereuses.

Limité (2)

Neige glissante

Endroits dangereux

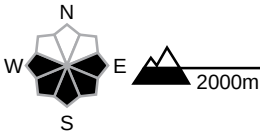

Description des dangers

Sur les pentes raides herbeuses des avalanches de glissement de plus en plus nombreuses sont à attendre. Celles-ci peuvent aussi atteindre une grande taille. Des glissements sur les talus sont possibles.

Degrés de danger 1 faible | 2 limité | 3 marqué | 4 fort | 5 très fort

région B

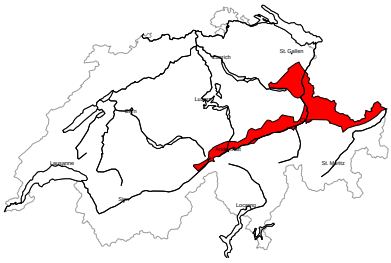

Fort (4-)

Neige fraîche, Couche fragile persistante

Endroits dangereux

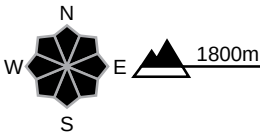

Description des dangers
La neige fraîche abondante et la neige soufflée sont fragiles. Des avalanches spontanées sont à attendre. Elles peuvent atteindre une très grande taille de manière isolée. Les tronçons exposés des voies de communication peuvent être menacés. Avec la fin des précipitations l'activité des avalanches spontanées diminue.
Des avalanches peuvent en de nombreux endroits être déjà déclenchées par un seul amateur de sports d'hiver. Pour des randonnées et descentes hors-piste en dehors des pistes sécurisées les conditions sont dangereuses.

Limité (2)

Neige glissante

Endroits dangereux

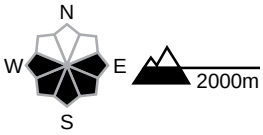

Description des dangers
Sur les pentes raides herbeuses des avalanches de glissement de plus en plus nombreuses sont à attendre. Celles-ci peuvent aussi atteindre une grande taille. Des glissements sur les talus sont possibles.

région C

Fort (4-)

Neige soufflée, Couche fragile persistante

Endroits dangereux

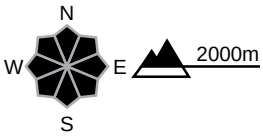

Description des dangers
La neige fraîche et la neige soufflée reposent sur une couche fragile de neige ancienne. Des avalanches peuvent en de nombreux endroits être déclenchées très facilement. Elles peuvent se déclencher dans les couches proches du sol et atteindre une grande taille. Des bruits sourds ainsi que des avalanches récentes attirent l'attention sur le danger. Des déclenchements à distance sont à attendre. Des avalanches spontanées sont encore possibles surtout pendant la nuit.
Le danger concerne principalement les terrains alpins de sports d'hiver. Pour des randonnées et descentes hors-piste en dehors des pistes sécurisées les conditions sont dangereuses.

Limité (2)

Neige glissante

Endroits dangereux

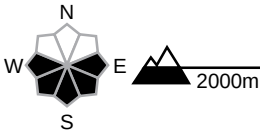

Description des dangers
Sur les pentes raides herbeuses des avalanches de glissement de plus en plus nombreuses sont à attendre. Celles-ci peuvent aussi atteindre une grande taille. Des glissements sur les talus sont possibles.

région D

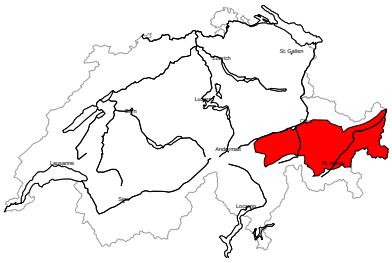

Fort (4-)

Neige soufflée, Couche fragile persistante

Endroits dangereux

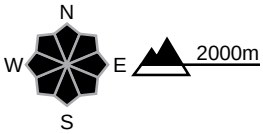

Description des dangers
La neige fraîche et la neige soufflée reposent sur une couche fragile de neige ancienne. Des avalanches peuvent en de nombreux endroits être déclenchées très facilement. Elles peuvent se déclencher dans les couches proches du sol et atteindre une grande taille. Des bruits sourds ainsi que des avalanches récentes attirent l'attention sur le danger. Des déclenchements à distance sont à attendre. Des avalanches spontanées sont encore possibles surtout pendant la nuit.
Le danger concerne principalement les terrains alpins de sports d'hiver. Pour des randonnées et descentes hors-piste en dehors des pistes sécurisées les conditions sont dangereuses.

région E

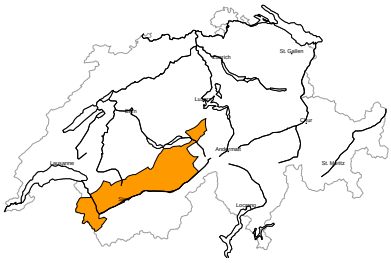

Marqué (3+)

Neige fraîche

Endroits dangereux

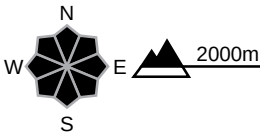

Description des dangers
La neige fraîche abondante et la neige soufflée sont fragiles. Des amateurs de sports d'hiver même seuls peuvent déclencher des avalanches. Des avalanches peuvent entraîner avec elles les couches profondes du manteau neigeux. Des avalanches spontanées ne sont plus à attendre que de façon isolée, mais celles-ci peuvent devenir très grandes.
Les randonnées et descentes hors-piste demandent beaucoup d'expérience dans l'évaluation du danger d'avalanche.

Limité (2)

Neige glissante

Endroits dangereux

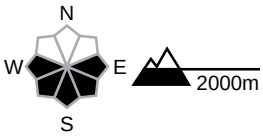

Description des dangers
Sur les pentes raides herbeuses des avalanches de glissement de plus en plus nombreuses sont à attendre. Celles-ci peuvent aussi atteindre une grande taille. Des glissements sur les talus sont possibles.

région F

Marqué (3+)

Neige fraîche, Couche fragile persistante

Endroits dangereux

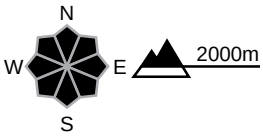

Description des dangers
La neige fraîche et la neige soufflée reposent sur une couche fragile de neige ancienne. Des avalanches peuvent être déclenchées très facilement. Elles peuvent se déclencher dans les couches profondes du manteau neigeux et atteindre une grande taille. Des bruits sourds ainsi que des avalanches récentes attirent l'attention sur le danger. Des déclenchements à distance sont possibles.
Les randonnées et descentes hors-piste demandent beaucoup d' expérience dans l'évaluation du danger d'avalanche et de la retenue.

Limité (2)

Neige glissante

Endroits dangereux

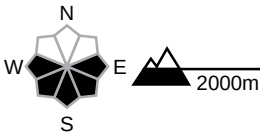

Description des dangers
Sur les pentes raides herbeuses des avalanches de glissement de plus en plus nombreuses sont à attendre. Celles-ci peuvent aussi atteindre une grande taille. Des glissements sur les talus sont possibles.

région G

Marqué (3+)

Neige soufflée, Couche fragile persistante

Endroits dangereux

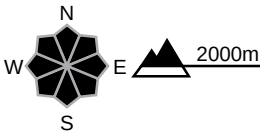

Description des dangers
Les accumulations déjà plus anciennes de neige soufflée reposent sur une couche fragile de neige ancienne. Des avalanches peuvent être déclenchées facilement. Elles peuvent aussi se déclencher dans les couches profondes du manteau neigeux et atteindre une grande taille. Des bruits sourds et des fissures lors du passage sur le manteau neigeux peuvent attirer l'attention sur le danger. Des déclenchements à distance sont possibles.
Les randonnées et descentes hors-piste demandent de l' expérience dans l'évaluation du danger d'avalanche et de la retenue.

région H

Marqué (3+)

Neige soufflée, Couche fragile persistante

Endroits dangereux

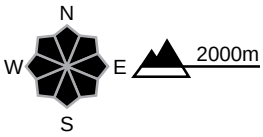

Description des dangers
Les accumulations déjà plus anciennes de neige soufflée reposent sur une couche fragile de neige ancienne. Des avalanches peuvent être déclenchées facilement. Elles peuvent aussi se déclencher dans les couches profondes du manteau neigeux et atteindre une grande taille. Des bruits sourds et des fissures lors du passage sur le manteau neigeux peuvent attirer l'attention sur le danger. Des déclenchements à distance sont possibles.
Les randonnées et descentes hors-piste demandent de l' expérience dans l'évaluation du danger d'avalanche et de la retenue.

Limité (2)

Neige glissante

Endroits dangereux

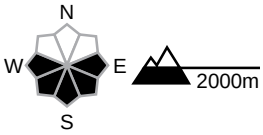

Description des dangers
Sur les pentes raides herbeuses des avalanches de glissement de plus en plus nombreuses sont à attendre. Celles-ci peuvent aussi atteindre une grande taille. Des glissements sur les talus sont possibles.

région I

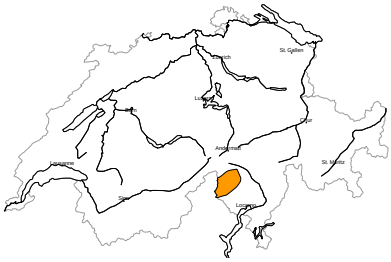

Marqué (3+)

Neige fraîche, Couche fragile persistante

Endroits dangereux

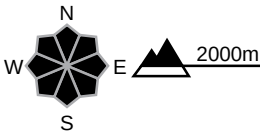

Description des dangers
La neige fraîche et la neige soufflée reposent sur une couche fragile de neige ancienne. Des avalanches peuvent être déclenchées très facilement. Elles peuvent se déclencher dans les couches profondes du manteau neigeux et atteindre une grande taille. Des bruits sourds ainsi que des avalanches récentes attirent l'attention sur le danger. Des déclenchements à distance sont possibles.
Les randonnées et descentes hors-piste demandent beaucoup d' expérience dans l'évaluation du danger d'avalanche et de la retenue.

Bulletin d'avalanches jusqu'à dimanche, 22. février 2026

région J

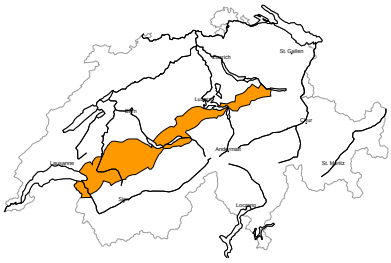

Marqué (3=)

Neige fraîche

Endroits dangereux

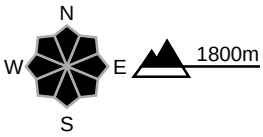

Description des dangers
La neige fraîche abondante des derniers jours et les accumulations de neige soufflée sont fragiles. Des avalanches peuvent être déclenchées par un seul amateur de sports d'hiver. Elles peuvent de manière isolée entraîner avec elles les couches plus profondes du manteau neigeux et atteindre une grande taille.
Les randonnées et descentes hors-piste demandent une expérience dans l'évaluation du danger d'avalanche.

Limité (2)

Neige glissante

Endroits dangereux

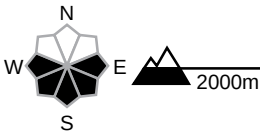

Description des dangers
Sur les pentes raides herbeuses des avalanches de glissement de plus en plus nombreuses sont à attendre. Celles-ci peuvent aussi atteindre une grande taille. Des glissements sur les talus sont possibles.

région K

Marqué (3-)

Neige fraîche

Endroits dangereux

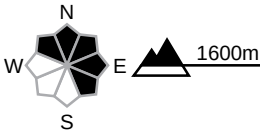

Description des dangers
La neige fraîche des derniers jours et les accumulations de neige soufflée sont partiellement encore fragiles en altitude. Des amateurs de sports d'hiver seuls peuvent par endroits déclencher des avalanches, pouvant atteindre une taille moyenne. Les endroits dangereux se situent surtout dans les combes, couloirs et derrière les ruptures de terrain.
Les randonnées demandent une expérience dans l'évaluation du danger d'avalanche.

Limité (2)

Neige glissante

Endroits dangereux

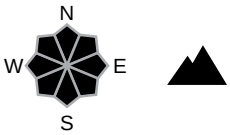

Description des dangers
Sur les pentes raides herbeuses des avalanches de glissement de plus en plus nombreuses sont à attendre, surtout de taille moyenne. Des glissements sur les talus sont possibles.

région L — Limité (2+)

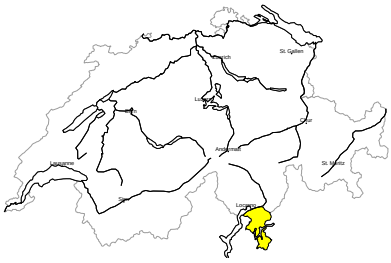

Neige soufflée, Couche fragile persistante

Endroits dangereux

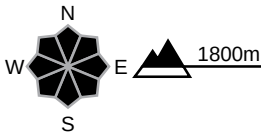

Description des dangers
Les accumulations de neige soufflée des derniers jours devraient être évaluées avec prudence en terrain raide. Des avalanches peuvent se rompre jusque dans les couches profondes surtout sur les pentes à l'ombre et atteindre une taille moyenne. Un choix prudent des itinéraires est important.

région M — Limité (2)

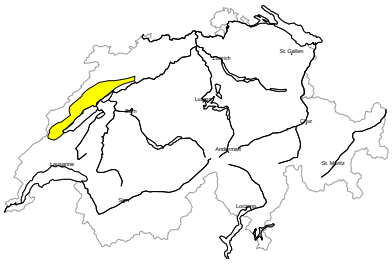

Neige glissante

Endroits dangereux

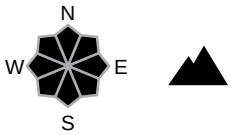

Description des dangers
Sur les pentes raides herbeuses des avalanches de glissement de plus en plus nombreuses sont à attendre, surtout de taille moyenne. Des glissements sur les talus sont possibles.

Manteau neigeux et météo

actualisé le 21.2.2026, 17:00

Manteau neigeux

Les abondantes quantités de neige fraîche et de neige soufflée des derniers jours et semaines sont toujours instables en de nombreux endroits.
Au nord d'une ligne Rhône-Rhin et dans la partie la plus occidentale du Bas-Valais, de 2 à 3,5 m de neige sont tombés au cours des 2 dernières semaines. Les couches fragiles du manteau de neige ancienne sont ainsi recouvertes d'une épaisse couche et leur décrochement ne peut pratiquement plus être provoqué par des personnes. Les avalanches peuvent cependant encore entraîner avec elles des couches plus profondes et, dans ce cas, atteindre une très grande ampleur.
Au sud d'une ligne Rhône-Rhin, le problème de la neige ancienne reste marqué. C'est au Tessin et dans les Grisons que la neige ancienne fragile est la plus susceptible de se décrocher. Les endroits dangereux y sont toujours aussi fréquents, les bruits sourds et les déclenchements à distance sont typiques, même dans la limite de la forêt. Dans le sud du Valais, les couches fragiles marquées dans la partie inférieure du manteau neigeux sont généralement recouvertes d'une couche un peu plus épaisse. Les endroits dangereux où des avalanches peuvent être déclenchées dans la neige ancienne fragile sont donc un peu plus rares et se situent surtout aux endroits plutôt faiblement enneigés.
Avec les températures douces, il faut s'attendre de plus en plus à des avalanches de glissement de taille moyenne ou grande sur les pentes herbeuses raides en dessous de 2000 m environ.

Rétrospective météo de ce samedi

Dans une grande partie du nord et de l'est, il y a eu des précipitations qui étaient intenses en cours de journée. Dans l'extrême sud, le temps était ensoleillé. La limite des chutes de neige est montée depuis 1100 m à environ 1500 m.

Neige fraîche
Depuis vendredi après-midi jusqu’à samedi après-midi au-dessus de 1600 m:
- Est du versant nord des Alpes: de 30 à 40 cm
- Région d'Aletsch, vallée de Conches, centre du versant nord des Alpes, nord des Grisons, nord de la Basse-Engadine : de 20 à 30 cm
- Reste du versant nord des Alpes, reste de la région du Gottard : de 10 à 20 cm
- Ailleurs: souvent de 5 à 10 cm; dans l'extrême sud, temps sec

Température
À la mi-journée à 2000 m, entre -2 °C dans le nord et +2 °C dans le sud

Vent
Modéré à fort de secteur nord-ouest

Prévisions météorologiques jusqu’à dimanche

En première moitié de nuit, il y aura encore des précipitations dans l'est. La limite pluie-neige se situera à 1500 m et pourra à la fin encore monter un peu dans certaines régions. Pendant la journée, le temps sera, dans toutes les régions, au moins partiellement ensoleillé avec des champs nuageux élevés.

Neige fraîche
Depuis samedi après-midi jusqu’à dimanche matin, au-dessus de 1800 m environ:
- Est du versant nord des Alpes, nord des Grisons, nord de la Basse-Engadine: de 10 à 20 cm
- Centre du versant nord des Alpes, reste des Grisons : de 5 à 10 cm ; ailleurs, moins de neige fraîche ou temps sec

Température
En hausse; à la mi-journée à 2000 m entre +2 °C dans le nord et +4 °C dans le sud

Vent
- En première moitié de nuit, vent du nord-ouest modéré à fort dans le sud et en général en altitude, puis diminuant
- En journée, vent d'ouest souvent modéré, parfois fort dans le nord l'après-midi

Tendance jusqu’à mardi

Lundi, de 5 à 15 cm de neige tomberont à nouveau dans le nord et l'est au-dessus de 1600 m environ. Le temps sera partiellement ensoleillé dans l'ouest et généralement ensoleillé dans le sud. Le vent du nord-ouest sera modéré, mais parfois fort en altitude dans le sud.
Pendant la nuit de lundi à mardi, quelques centimètres de neige tomberont encore sur l'extrême est du pays. Pendant la journée, le temps est ensoleillé dans l'ouest et le sud, mais vers l'est il ne sera que partiellement ensoleillé. Il fera nettement plus doux. L'isotherme 0°C montera à 3000 m en cours de journée dans l'ouest.
Le danger d'avalanches diminuera, mais seulement très lentement dans le sud du Valais, dans le Tessin et dans les Grisons, en raison de la présence de couches fragiles marquées. Avec le radoucissement du temps, il faudra s'attendre à davantage d'avalanches de glissement, qui peuvent atteindre une grande ampleur dans l'ouest et le nord, en raison des grandes quantités de neige.