Pericolo valanghe

aggiornato al 21.2.2026, 17:00

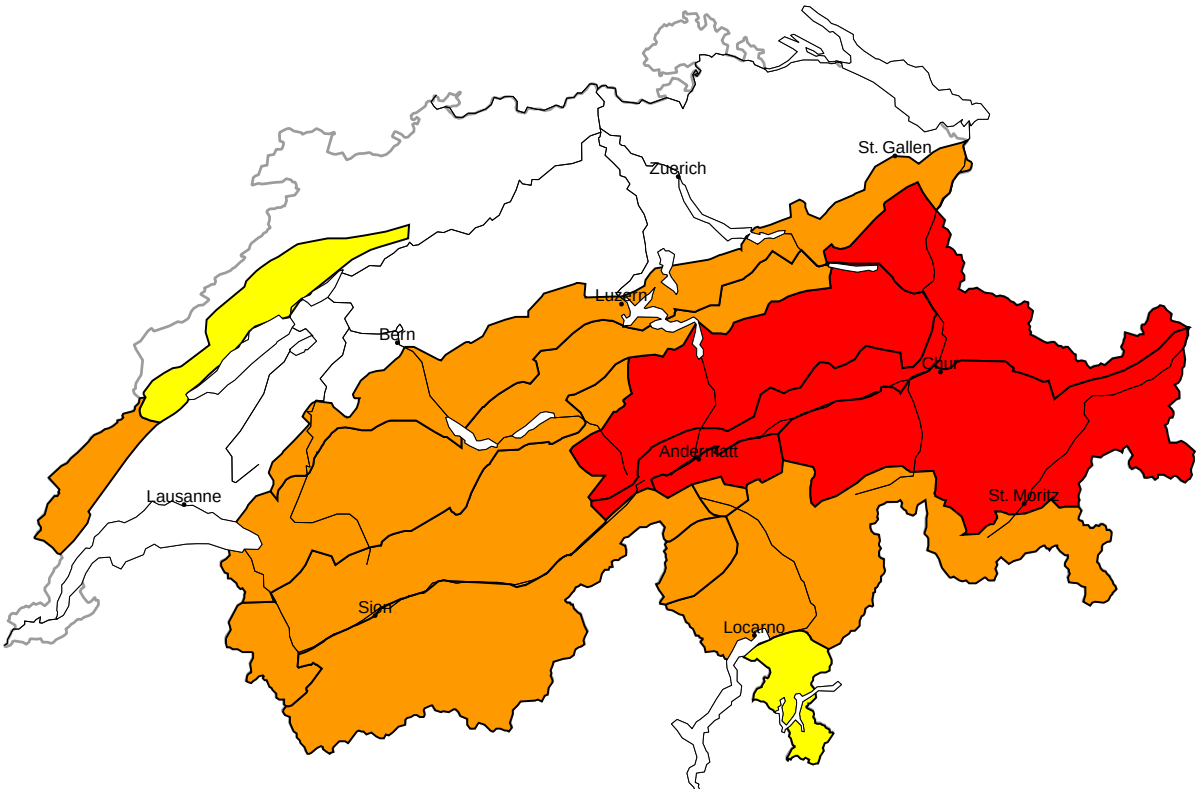

regione A

Forte (4=)

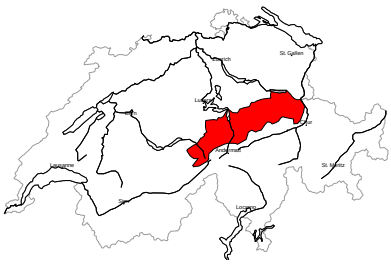

Neve fresca, Strati deboli persistenti

Punti pericolosi

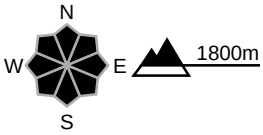

Descrizione del pericolo

Le grandi quantità di neve fresca e neve ventata sono instabili. Sono previste valanghe spontanee. Esse possono raggiungere dimensioni molto grandi. Lungo i percorsi abituali le valanghe possono avanzare sino a valle. Le vie di comunicazione esposte saranno in pericolo.
Con il cessare delle precipitazioni, l'attività di valanghe spontanee diminuirà. Per le escursioni e le discese fuori pista al di fuori delle piste assicurate, le condizioni sono pericolose.

Moderato (2)

Valanghe di slittamento

Punti pericolosi

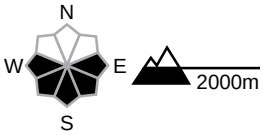

Descrizione del pericolo

Sui pendii erbosi ripidi, sono previste sempre più numerose valanghe per scivolamento di neve. Queste possono anche raggiungere grandi dimensioni. Sono possibili colate dalle scarpate.

Scala del pericolo 1 debole | 2 moderato | 3 marcato | 4 forte | 5 molto forte

Bollettino valanghe sino a domenica, 22. febbraio 2026

regione B

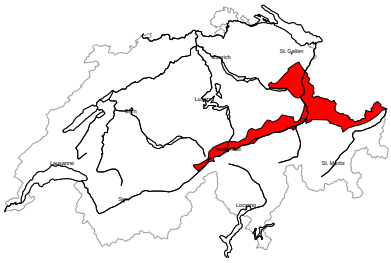

Forte (4-)

Neve fresca, Strati deboli persistenti

Punti pericolosi

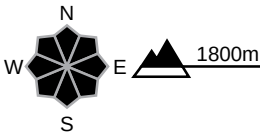

Descrizione del pericolo
Le grandi quantità di neve fresca e neve ventata sono instabili. Sono previste valanghe spontanee. Esse possono raggiungere dimensioni molto grandi a livello isolato. I tratti esposti delle vie di comunicazione potranno essere in pericolo. Con il cessare delle precipitazioni, l'attività di valanghe spontanee diminuirà. Le valanghe possono in molti punti distaccarsi già in seguito al passaggio di un singolo appassionato di sport invernali. Per le escursioni e le discese fuori pista al di fuori delle piste assicurate, le condizioni sono pericolose.

Moderato (2)

Valanghe di slittamento

Punti pericolosi

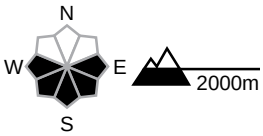

Descrizione del pericolo
Sui pendii erbosi ripidi, sono previste sempre più numerose valanghe per scivolamento di neve. Queste possono anche raggiungere grandi dimensioni. Sono possibili colate dalle scarpate.

regione C

Forte (4-)

Lastroni da vento, Strati deboli persistenti

Punti pericolosi

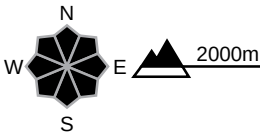

Descrizione del pericolo
La neve fresca e la neve ventata ricoprono un debole manto di neve vecchia. Le valanghe possono in molti punti distaccarsi molto facilmente. Esse possono staccarsi negli strati basali del manto e raggiungere grandi dimensioni. I rumori di "whum" così come nuove valanghe sono segnali da ricondurre a questo pericolo. Si prevedono distacchi a distanza. Soprattutto durante la notte saranno ancora possibili valanghe spontanee. Il pericolo si riferisce principalmente alle zone alpine frequentate dagli appassionati di sport invernali. Per le escursioni e le discese fuori pista al di fuori delle piste assicurate, le condizioni sono pericolose.

Moderato (2)

Valanghe di slittamento

Punti pericolosi

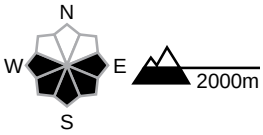

Descrizione del pericolo
Sui pendii erbosi ripidi, sono previste sempre più numerose valanghe per scivolamento di neve. Queste possono anche raggiungere grandi dimensioni. Sono possibili colate dalle scarpate.

regione D

Forte (4-)

Lastroni da vento, Strati deboli persistenti

Punti pericolosi

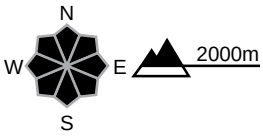

Descrizione del pericolo
La neve fresca e la neve ventata ricoprono un debole manto di neve vecchia. Le valanghe possono in molti punti distaccarsi molto facilmente. Esse possono staccarsi negli strati basali del manto e raggiungere grandi dimensioni. I rumori di "whum" così come nuove valanghe sono segnali da ricondurre a questo pericolo. Si prevedono distacchi a distanza. Soprattutto durante la notte saranno ancora possibili valanghe spontanee. Il pericolo si riferisce principalmente alle zone alpine frequentate dagli appassionati di sport invernali. Per le escursioni e le discese fuori pista al di fuori delle piste assicurate, le condizioni sono pericolose.

regione E

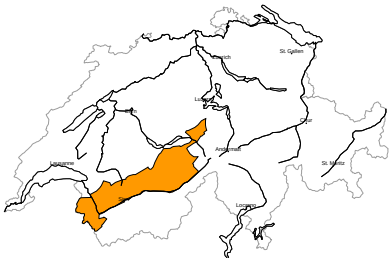

Marcato (3+)

Neve fresca

Punti pericolosi

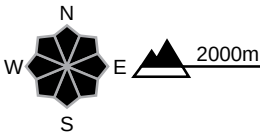

Descrizione del pericolo
Le grandi quantità di neve fresca e neve ventata sono instabili. Già un singolo appassionato di sport invernali può provocare il distacco di valanghe. Le valanghe possono trascinare gli strati più profondi del manto nevoso. Sono previste solo più isolate valanghe spontanee, che possono raggiungere dimensioni molto grandi.
Le escursioni e le discese fuori pista richiedono molta esperienza nella valutazione del pericolo di valanghe.

Moderato (2)

Valanghe di slittamento

Punti pericolosi

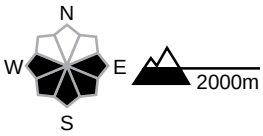

Descrizione del pericolo
Sui pendii erbosi ripidi, sono previste sempre più numerose valanghe per scivolamento di neve. Queste possono anche raggiungere grandi dimensioni. Sono possibili colate dalle scarpate.

regione F

Marcato (3+)

Neve fresca, Strati deboli persistenti

Punti pericolosi

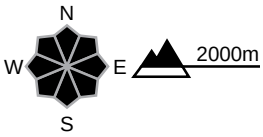

Descrizione del pericolo
La neve fresca e la neve ventata ricoprono un debole manto di neve vecchia. Le valanghe possono distaccarsi molto facilmente. Esse possono distaccarsi negli strati più profondi e raggiungere grandi dimensioni. I rumori di "whum" così come nuove valanghe sono segnali da ricondurre a questo pericolo. Sono possibili distacchi a distanza.
Le escursioni e le discese fuori pista richiedono molta esperienza nella valutazione del pericolo di valanghe e attenzione.

Moderato (2)

Valanghe di slittamento

Punti pericolosi

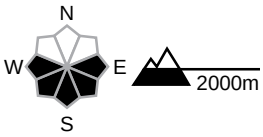

Descrizione del pericolo
Sui pendii erbosi ripidi, sono previste sempre più numerose valanghe per scivolamento di neve. Queste possono anche raggiungere grandi dimensioni. Sono possibili colate dalle scarpate.

regione G

Marcato (3+)

Lastroni da vento, Strati deboli persistenti

Punti pericolosi

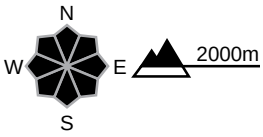

Descrizione del pericolo
Gli accumuli di neve ventata meno recenti ricoprono un debole manto di neve vecchia. Le valanghe possono distaccarsi facilmente. Esse possono anche distaccarsi negli strati più profondi e raggiungere grandi dimensioni. I rumori di "whum" e la formazione di fessure quando si calpesta la coltre di neve sono possibili segnali di pericolo. Sono possibili distacchi a distanza.
Le escursioni e le discese fuori pista richiedono esperienza nella valutazione del pericolo di valanghe e attenzione.

regione H

Marcato (3+)

Lastroni da vento, Strati deboli persistenti

Punti pericolosi

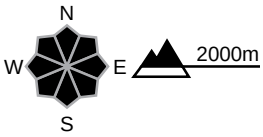

Descrizione del pericolo
Gli accumuli di neve ventata meno recenti ricoprono un debole manto di neve vecchia. Le valanghe possono distaccarsi facilmente. Esse possono anche distaccarsi negli strati più profondi e raggiungere grandi dimensioni. I rumori di "whum" e la formazione di fessure quando si calpesta la coltre di neve sono possibili segnali di pericolo. Sono possibili distacchi a distanza.
Le escursioni e le discese fuori pista richiedono esperienza nella valutazione del pericolo di valanghe e attenzione.

Moderato (2)

Valanghe di slittamento

Punti pericolosi

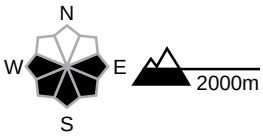

Descrizione del pericolo
Sui pendii erbosi ripidi, sono previste sempre più numerose valanghe per scivolamento di neve. Queste possono anche raggiungere grandi dimensioni. Sono possibili colate dalle scarpate.

regione I

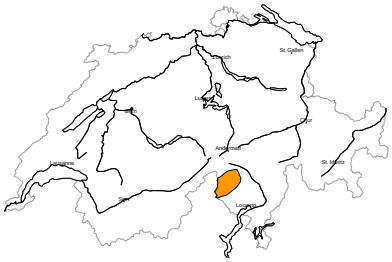

Marcato (3+)

Neve fresca, Strati deboli persistenti

Punti pericolosi

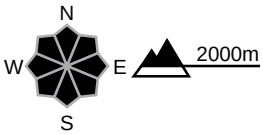

Descrizione del pericolo
La neve fresca e la neve ventata ricoprono un debole manto di neve vecchia. Le valanghe possono distaccarsi molto facilmente. Esse possono distaccarsi negli strati più profondi e raggiungere grandi dimensioni. I rumori di "whum" così come nuove valanghe sono segnali da ricondurre a questo pericolo. Sono possibili distacchi a distanza.
Le escursioni e le discese fuori pista richiedono molta esperienza nella valutazione del pericolo di valanghe e attenzione.

Bollettino valanghe sino a domenica, 22. febbraio 2026

regione J

Marcato (3=)

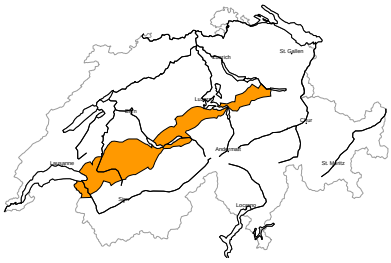

Neve fresca

Punti pericolosi

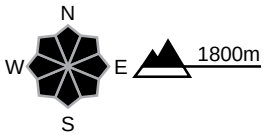

Descrizione del pericolo
L'abbondante neve fresca degli ultimi giorni e gli accumuli di neve ventata sono instabili. Le valanghe possono distaccarsi in seguito al passaggio di un singolo appassionato di sport invernali. Esse possono a livello isolato coinvolgere gli strati più profondi e raggiungere grandi dimensioni.
Le escursioni e le discese fuori pista richiedono esperienza nella valutazione del pericolo di valanghe.

Moderato (2)

Valanghe di slittamento

Punti pericolosi

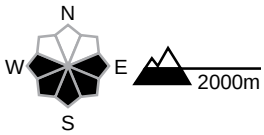

Descrizione del pericolo
Sui pendii erbosi ripidi, sono previste sempre più numerose valanghe per scivolamento di neve. Queste possono anche raggiungere grandi dimensioni. Sono possibili colate dalle scarpate.

regione K

Marcato (3-)

Neve fresca

Punti pericolosi

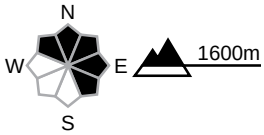

Descrizione del pericolo
La neve fresca degli ultimi giorni e gli accumuli di neve ventata sono in parte ancora instabili in quota. Un singolo appassionato di sport invernali può in alcuni punti provocare il distacco di valanghe, anche di medie dimensioni. I punti pericolosi si trovano soprattutto nelle conche, nei canaloni e dietro ai cambi di pendenza.
Le escursioni richiedono esperienza nella valutazione del pericolo di valanghe.

Moderato (2)

Valanghe di slittamento

Punti pericolosi

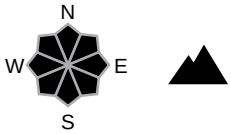

Descrizione del pericolo
Sui pendii erbosi ripidi, sono previste sempre più numerose valanghe per scivolamento di neve, soprattutto di medie dimensioni. Sono possibili colate dalle scarpate.

Bollettino valanghe sino a domenica, 22. febbraio 2026

regione L — Moderato (2+)

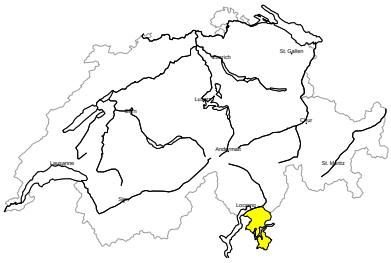

Lastroni da vento, Strati deboli persistenti

Punti pericolosi

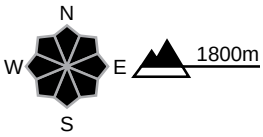

Descrizione del pericolo
Gli accumuli di neve ventata degli ultimi giorni dovrebbero essere valutati con attenzione sui pendii ripidi. Soprattutto sui pendii ombreggiati le valanghe possono coinvolgere gli strati più profondi e raggiungere dimensioni medie. È importante una prudente scelta dell'itinerario.

regione M — Moderato (2)

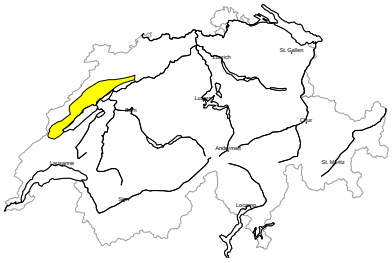

Valanghe di slittamento

Punti pericolosi

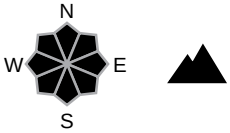

Descrizione del pericolo
Sui pendii erbosi ripidi, sono previste sempre più numerose valanghe per scivolamento di neve, soprattutto di medie dimensioni. Sono possibili colate dalle scarpate.

Manto nevoso e meteo

aggiornato al 21.2.2026, 17:00

Manto nevoso

Le abbondanti quantità di neve fresca e ventata degli ultimi giorni e settimane rimangono ancora instabili in molti punti. Nelle ultime due settimane, a nord di una linea Rodano-Reno e nel Basso Vallese occidentale estremo sono caduti dai 2 ai 3,5 m di neve. Gli strati fragili presenti nel manto di neve vecchia sono pertanto abbondantemente ricoperti e non possono praticamente più subire un distacco in seguito al passaggio di persone. A livello isolato sono tuttavia ancora possibili valanghe che coinvolgono gli strati profondi raggiungendo in quel caso dimensioni molto grandi.
A sud di una linea Rodano-Reno, il problema di neve vecchia è ancora pronunciato. La maggiore instabilità del debole manto di neve vecchia si registra in Ticino e nei Grigioni. Qui i punti pericolosi sono ancora frequenti e si rilevano tipicamente rumori di assestamento e distacchi a distanza, anche in prossimità del limite del bosco. Nel sud del Vallese i pronunciati strati fragili nella parte basale del manto sono generalmente ricoperti da una quantità di neve un po' più abbondante. I punti pericolosi in cui le valanghe possono subire un distacco nel debole manto di neve vecchia sono pertanto un po' più rari e si trovano soprattutto nelle zone scarsamente innevate.
Con le temperature miti, sui pendii erbosi ripidi situati al di sotto dei 2000 m circa si prevede un progressivo aumento delle valanghe per scivolamento di neve di medie e grandi dimensioni.

Retrospettiva meteo fino a sabato

In molti punti delle regioni settentrionali e orientali ci sono state precipitazioni, che nel corso della giornata sono risultate intense. Nelle regioni meridionali estreme il cielo è stato soleggiato. Il limite delle nevicate è salito dagli 1100 m fin verso i 1500 m.

Neve fresca
Da venerdì pomeriggio a sabato pomeriggio, al di sopra dei 1600 m:
- Versante nordalpino orientale: dai 30 ai 40 cm
- Regione dell'Aletsch, valle di Goms, versante nordalpino centrale, nord dei Grigioni, parte settentrionale della Bassa Engadina: dai 20 ai 30 cm
- Resto del versante nordalpino, restante regione del Gottardo: dai 10 ai 20 cm
- In molte altre regioni: dai 5 ai 10 cm. Regioni meridionali estreme: tempo asciutto

Temperatura
Sul mezzogiorno a 2000 m compresa tra -2 °C nelle regioni settentrionali e +2 °C in quelle meridionali

Vento
Da moderato a forte proveniente da nord ovest

Bollettino valanghe sino a domenica, 22. febbraio 2026

Previsioni meteo fino a domenica

Nella prima metà della notte, nelle regioni orientali ci saranno ancora precipitazioni. Il limite delle nevicate si collocherà intorno ai 1500 m e alla fine potrà salire ancora un po' in alcuni punti. Nel corso della giornata, in tutte le regioni il tempo sarà almeno parzialmente soleggiato con addensamenti di nubi alte.

Neve fresca
Da sabato pomeriggio a domenica mattina, al di sopra dei 1800 m:
- Versante nordalpino orientale, nord dei Grigioni, parte settentrionale della Bassa Engadina: dai 10 ai 20 cm
- Versante nordalpino centrale, resto dei Grigioni: dai 5 ai 10 cm. Altrove: meno o tempo asciutto

Temperatura
In aumento, sul mezzogiorno a 2000 m compresa fra +2 °C nelle regioni settentrionali e +4 °C in quelle meridionali

Vento
- Nella prima metà della notte, nelle regioni meridionali e in generale in quota il vento proveniente da nord ovest sarà da moderato a forte e successivamente si attenuerà.
- Nel corso della giornata spesso moderato, nelle regioni settentrionali a tratti forte nel pomeriggio, proveniente da ovest

Tendenza fino a martedì

Lunedì, nelle regioni settentrionali e orientali cadranno ancora dai 5 ai 15 cm di neve al di sopra dei 1600 m circa. Nelle regioni occidentali il cielo sarà parzialmente soleggiato, in quelle meridionali per lo più soleggiato. Il vento proveniente da nord ovest sarà moderato, nei settori in quota delle regioni meridionali a tratti forte.
Nella notte fra lunedì e martedì, nelle regioni orientali estreme cadranno ancora pochi centimetri di neve. Nel corso della giornata, nelle regioni occidentali e meridionali il tempo sarà soleggiato, verso est solo parzialmente soleggiato. Le temperature diventeranno nettamente più miti. Nel corso della giornata, nelle regioni occidentali la quota dello zero termico salirà fino ai 3000 m.
Il pericolo di valanghe diminuirà, ma nel sud del Vallese, in Ticino e nei Grigioni tale calo sarà molto lento a causa dei pronunciati strati deboli. Con il rialzo termico si prevede un progressivo aumento delle valanghe per scivolamento di neve, che nelle regioni occidentali e settentrionali potranno raggiungere grandi dimensioni a causa delle abbondanti quantità di neve.