GOBIERNO DE ESPAÑA
VICEPRESIDENCIA TERCERA DEL GOBIERNO
MINISTERIO PARA LA TRANSICIÓN ECOLÓGICA Y EL RETO DEMOGRÁFICO

Boletín de información nivológica y de peligro de aludes

Pirineo Navarro y Aragonés

aemet Agencia Estatal de Meteorología

domingo, 22 de febrero de 2026

Pronóstico hasta las 24 horas del lunes, día 23 de febrero

(Válido fuera de pistas de esquí balizadas y abiertas)

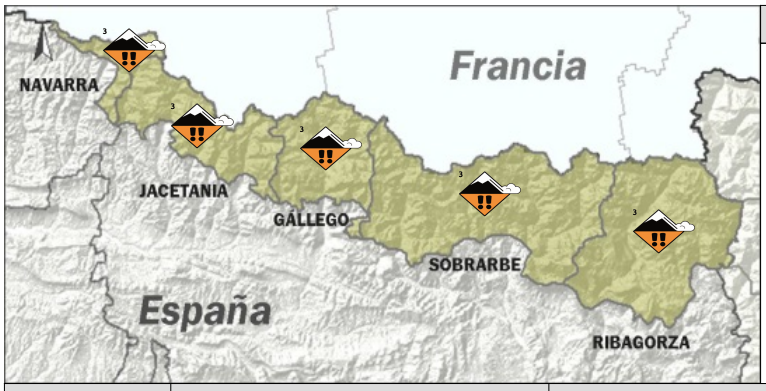

Problemas de aludes

- Placas de viento
- Nieve húmeda
- Deslizamientos basales

Macizo	Peligro	Problemas de aludes, cota, orientación, tamaño	Innivación observada (m)
Navarra	3 — 3 / 2→3 — 2300 — Durante el día — **Notable**	**Placas de viento** — 2300 — N, E, S, O — 2 **Nieve húmeda** — N, E, S, O — 2	2026-02-22 N / S — Cotas bajas
Jacetania	3 — 3 / 2→3 — 2300 — Durante el día — **Notable**	**Placas de viento** — 2300 — N, E, S, O — 2 **Nieve húmeda** — N, E, S, O — 2	2026-02-22 N / S — Cotas bajas
Gállego	3 — 3 / 2→3 — 2300 — Durante el día — **Notable**	**Placas de viento** — 2300 — N, E, S, O — 2 **Nieve húmeda** — N, E, S, O — 2	2026-02-22 N / S — Cotas bajas

AEMET. Se autoriza la reproducción de su contenido citando la fuente.

Boletín de información nivológica y de peligro de aludes

Pirineo Navarro y Aragonés

Sobrarbe	**Notable**	**Placas de viento** **Nieve húmeda** 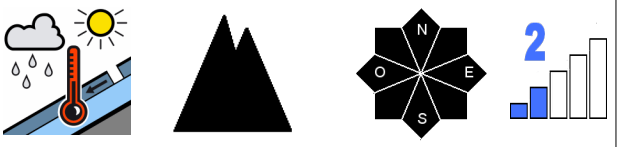	2026-02-22
Ribagorza	**Notable**	**Placas de viento** 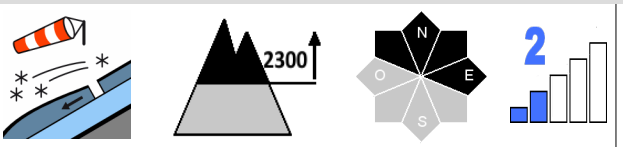 **Deslizamientos basales** 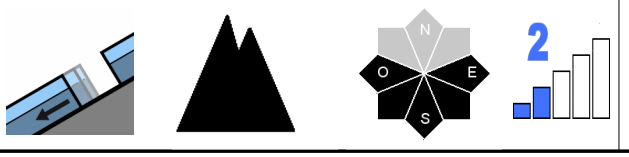	2026-02-22

Estado del manto y observaciones recientes

Continúa la presencia del anticiclón que está dejando los cielos despejados, con abundante insolación y temperaturas elevadas para la época. Así, prosigue la humidificación del manto y la disminución de su espesor varios centímetros cada día. Sin embargo, la cubierta de nieve se mantiene continua desde fondos de valle y presenta espesores muy por encima de lo que sería habitual a estas alturas de la temporada. En general es esquiable a partir de 1500 metros en las solanas y desde fondo de valle en umbrías. Por encima de 2100 metros se superan fácilmente los 150-200 cm, aún más en ventisqueros, hoyas y otras zonas propensas a la acumulación.

Salvo en algunas zonas umbrías de cotas elevadas, en general hay presencia de costra en superficie debido al ciclo de fusión diurno y rehielo nocturno, y en muchos casos no se hunde. En zonas expuestas al viento, sobretodo en orientaciones norte y oeste de cotas medias y altas, la nieve está muy erosionada, con áreas peladas. Por contra, en zonas de acumulación la nieve está venteada y en cotas altas aún pueden persistir placas de viento reactivas del episodio pasado que aún no se hayan estabilizado del todo. Además, éstas podrían descansar sobre alguna capa débil enterrada o persistente que puede seguir latente, aunque se espera que algunas puedan ir evolucionando con el débil gradiente térmico de estos días.

Un test realizado ayer en Cap de LLauset a 2500m, orientación E, presentó fractura fácil a 15cm de profundidad pero sin propagación.

En las últimas 24 horas se han reportado muchas coladas de nieve húmeda y en la Ribagorza diversos aludes de fondo de tamaño mediano, la mayoría en orientaciones este y sur y con altitudes de salida de entre 2200 y 3000 metros.

AEMET. Se autoriza la reproducción de su contenido citando la fuente.

Evolución del manto y peligro de aludes para el lunes, día 23

Mañana lunes continuará la insolación y las temperaturas altas por lo que el peligro ascenderá a partir del mediodía, cuando serán más frecuentes los aludes de nieve húmeda, con mayor probabilidad en las solanas. Por lo general serán de tamaño 1 (pequeño, riesgo de caída) o 2 (mediano, capaz de enterrar a una persona), localmente 3 (grande, capaz de enterrar a un grupo de personas). También es posible que se produzcan aludes de fondo en pendientes propensas de terreno herboso o de roca lisa, también más probables en las solanas, generalmente de tamaño 2, sin descartar alguno de tamaño 3.

En cotas altas por encima de 2300 metros (más arriba en solanas) aún podrían ser reactivas algunas placas de viento, en todas las orientaciones pero sobre todo en umbrías, pudiendo desencadenarse naturalmente o colapsar ante una sobrecarga débil (paso de un solo esquiador) o fuerte (grupo de esquiadores) ocasionando aludes de dimensión 1 o 2, localmente 3. Además, no se descarta que en umbrías por encima de 2500 metros estas sobrecargas puedan fracturar alguna capa débil en profundidad, que en el peor de los casos podría provocar un alud de dimensiones aún mayores.

Predicción meteorológica para el lunes, día 23

Poco nuboso o despejado. Temperaturas en descenso, ligero en las máximas. Algunas heladas débiles en cumbres y fondos de valle. Viento flojo del oeste y noroeste, salvo en el sector occidental donde podrá soplar inicialmente moderado.

Datos en la atmósfera libre:

Altitud de la isoterma de 0 ºC: 3300 m
Altitud de la isoterma de -10 ºC: 4800 m

Viento a 1500 m: NW 10 km/h
Viento a 3000 m: NW 20 km/h

Evolución para el martes día 24

Nivel de peligro sin cambios o en ligero descenso.

(Información elaborada a partir de los datos recibidos de los refugios de Linza, Lizara, Panticosa, Bachimaña, Góriz, Pineta, Estós, Angel Orús, La Renclusa, Cap de Llauset y Belagua, de las estaciones de esquí de Candanchú, Astún, Formigal y Panticosa (lagos), de la estación de esquí de fondo de Llanos del Hospital y de Ordesa Pradera)

Escala europea de peligro de aludes

Débil | Limitado | Notable | Fuerte | Muy Fuerte

Problemas de aludes

Nieve reciente | Placas de viento | Capas débiles persistentes | Nieve húmeda | Deslizamientos basales | Sin problema evidente

Nota1: Se recuerda que, siempre que haya nieve, la ausencia total de peligro no existe. Hay que tener presente que en circunstancias desfavorables, con aludes de tamaño 1 (alud pequeño o colada) y tamaño 2 (alud mediano), se pueden sufrir severos daños personales.

Nota2: Los BPA se elaboran en base a información meteorológica así como al estado del manto nivoso a través de sondeos puntuales. Se advierte a los usuarios de la variabilidad de esta información al extrapolarla a zonas extensas de montaña. Por ello, AEMET no se hace responsable de su uso para la toma de decisiones que conciernen a la seguridad personal, ni de los riesgos físicos o materiales de ellas derivadas.

AEMET. Se autoriza la reproducción de su contenido citando la fuente.