Montag 23.02.2026

Veröffentlicht am 22.02.2026 um 17:00

Vormittag

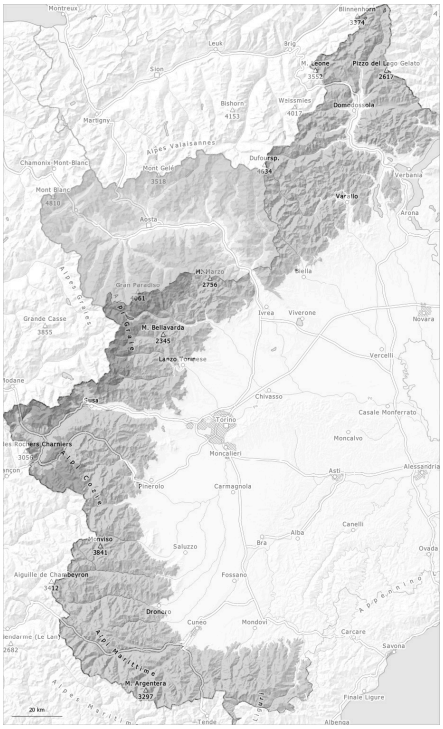

Nachmittag

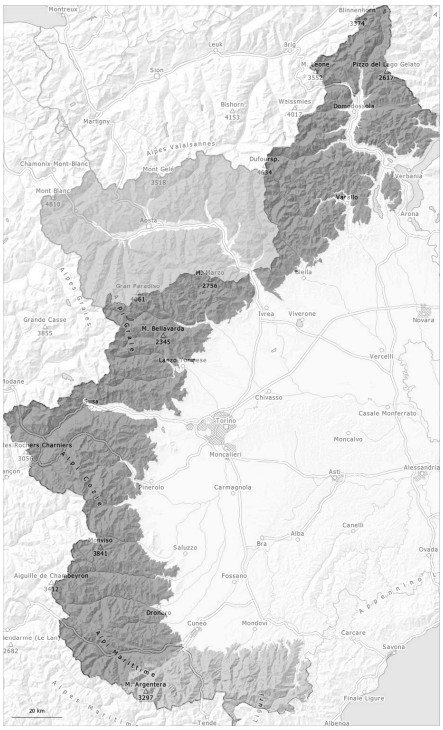

1	2	3	4	5
gering	mäßig	erheblich	groß	sehr groß

Gefahrenstufe 3 - Erheblich

AM:

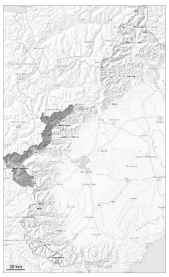

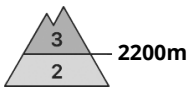

Tendenz: Lawinengefahr bleibt gleich
am Dienstag, den 24.02.2026

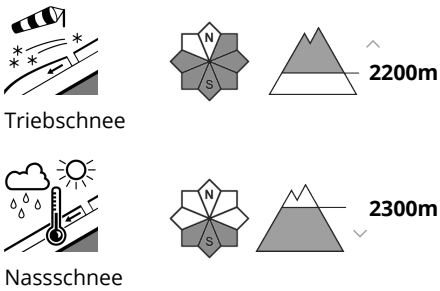

Triebschnee

Nassschnee

PM:

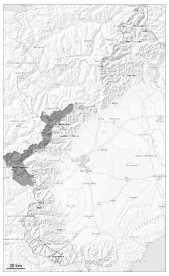

Tendenz: Lawinengefahr bleibt gleich
am Dienstag, den 24.02.2026

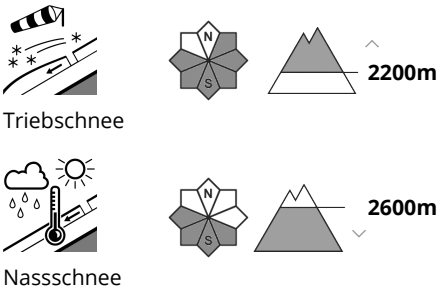

Triebschnee

Nassschnee

Die Gefahrenstellen für trockene Lawinen liegen vor allem im extremen Steilgelände. Allmählicher Anstieg der Gefahr von trockenen und feuchten Lawinen mit der tageszeitlichen Erwärmung und der Sonneneinstrahlung.

Die frischen und älteren Triebschneeansammlungen können noch ausgelöst werden. Die Lawinen sind meist mittelgroß aber oft schon von einzelnen Wintersportlern auslösbar.
Entlang der Grenze zu Frankreich sind die Gefahrenstellen weiter verbreitet und die Gefahr höher.

Es ist mild. Vor allem steile Sonnenhänge und Felswandfüße: An sehr steilen Sonnenhängen und in tiefen Lagen sind mit der Anfeuchtung mittlere und mehrfach große feuchte und nasse Lawinen möglich. Feuchte Lawinen können unterhalb von rund 2600 m bis in tiefe Schichten durchreißen und recht groß werden.

Schneedecke

Gefahrenmuster gm.6: lockerer schnee und wind | gm.10: frühjahrssituation

Mit Schneefall und teils stürmischem Nordwestwind entstanden in den letzten Tagen frische Triebschneeansammlungen. Der teilweise stürmische Wind hat viel Schnee verfrachtet.
In Gipfellagen liegen je nach Windeinfluss sehr unterschiedliche Schneehöhen.

> Dort liegt für die Jahreszeit viel Schnee. Sonne und Wärme führen ab dem Morgen vor allem an Sonnenhängen zu einer zunehmenden Anfeuchtung der Schneedecke.

Gefahrenstufe 3 - Erheblich

AM:

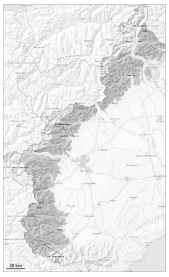

Tendenz: Lawinengefahr bleibt gleich
am Dienstag, den 24.02.2026

Triebschnee

PM:

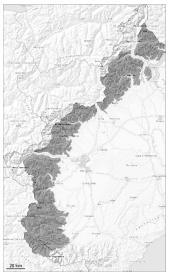

Tendenz: Lawinengefahr bleibt gleich
am Dienstag, den 24.02.2026

Nassschnee

Triebschnee

2000m

Schneebrettlawinen sind die Hauptgefahr. Allmählicher Anstieg der Gefahr von trockenen und feuchten Lawinen mit der tageszeitlichen Erwärmung und der Sonneneinstrahlung.

Die frischen und älteren Triebschneeansammlungen können noch ausgelöst werden. Die Lawinen sind meist mittelgroß aber auch von einzelnen Wintersportlern auslösbar.

Es ist mild. Vor allem steile Sonnenhänge und Felswandfüße: An sehr steilen Sonnenhängen und in tiefen Lagen sind mit der Anfeuchtung mittlere und vereinzelt große feuchte und nasse Lawinen möglich. Feuchte Lawinen können unterhalb von rund 2600 m bis in tiefe Schichten durchreißen und recht groß werden.

Schneedecke

Gefahrenmuster gm.6: lockerer schnee und wind | gm.10: frühjahrssituation

Mit Schneefall und starkem Nordwestwind entstanden in den letzten Tagen frische Triebschneeansammlungen, besonders an kammnahen Ost-, Süd- und Südwesthängen sowie an Felswandfüßen und hinter Geländekanten. In Gipfellagen liegen je nach Windeinfluss sehr unterschiedliche Schneehöhen.

In diesen Gebieten oberhalb von rund 1300 m liegt für die Jahreszeit viel Schnee.
Schattenhänge: Die Schneedecke ist trocken, mit einer lockeren Oberfläche.

Die frühlingshaften Wetterbedingungen führen ab dem Morgen vor allem an Sonnenhängen unterhalb von

> rund 2600 m zu einer zunehmenden Anfeuchtung der Schneedecke. Die Schneeoberfläche weicht schneller auf als am Vortag.

Gefahrenstufe 3 - Erheblich

AM:

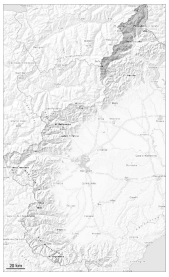

Tendenz: Lawinengefahr bleibt gleich
am Dienstag, den 24.02.2026

Triebschnee

PM:

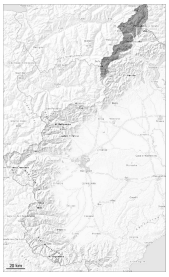

Tendenz: Lawinengefahr bleibt gleich
am Dienstag, den 24.02.2026

Nassschnee

Triebschnee

2100m

Vorsicht vor Triebschnee und Nassschnee. Allmählicher Anstieg der Gefahr von trockenen und feuchten Lawinen mit der tageszeitlichen Erwärmung und der Sonneneinstrahlung.

Die frischen und älteren Triebschneeansammlungen können noch ausgelöst werden. Die Lawinen sind meist mittelgroß aber auch von einzelnen Wintersportlern auslösbar.

Es ist mild. Tagesverlauf: An sehr steilen Sonnenhängen und in tiefen Lagen sind mit der Erwärmung mittlere und vereinzelt große feuchte und nasse Lawinen möglich. Feuchte Lawinen können vor allem unterhalb von rund 2600 m bis in tiefe Schichten durchreißen und recht groß werden.

Schneedecke

Gefahrenmuster gm.6: lockerer schnee und wind | gm.10: frühjahrssituation

Mit Schneefall und teils stürmischem Nordwestwind entstanden in den letzten Tagen frische Triebschneeansammlungen, besonders an kammnahen Nordost-, Süd- und Südwesthängen sowie an Felswandfüßen und hinter Geländekanten.
Der teilweise stürmische Wind hat viel Schnee verfrachtet. In Gipfellagen liegen je nach Windeinfluss sehr unterschiedliche Schneehöhen.

Verschiedene Triebschneeschichten liegen stellenweise auf grobkörnigem Altschnee.
Tagesverlauf: Die frühlingshaften Wetterbedingungen führen ab dem Morgen vor allem an Sonnenhängen unterhalb von rund 2500 m zu einer zunehmenden Anfeuchtung der Schneedecke. Die Schneeoberfläche

> weicht schneller auf als am Vortag.

Gefahrenstufe 2 - Mäßig

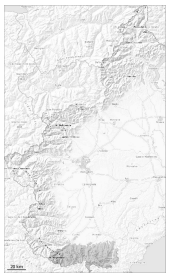

Tendenz: Lawinengefahr bleibt gleich
am Dienstag, den 24.02.2026

Triebschnee

2000m

Nassschnee

Vorsicht vor Nassschnee. Mit der Sonneneinstrahlung steigt die Auslösebereitschaft von feuchten und nassen Lawinen vor allem an Sonnenhängen an.

Vor allem mittlere und hohe Lagen sowie in windgeschützten Lagen: Weiche Triebschneeansammlungen können im Bereich der Waldgrenze von einzelnen Wintersportlern ausgelöst werden.
Vor allem steile Sonnenhänge und Felswandfüße: Mit der Erwärmung sind mittlere und vereinzelt große trockene und feuchte Lawinen möglich.

Schneedecke

Gefahrenmuster gm.6: lockerer schnee und wind | gm.10: frühjahrssituation

Mit starkem Nordwestwind entstanden in den letzten Tagen frische Triebschneeansammlungen. Der starke Wind hat Neu- und Altschnee verfrachtet.
V.a. in Gipfellagen liegen je nach Windeinfluss sehr unterschiedliche Schneehöhen.

Sonnenhänge: Sonne und Wärme führen ab dem Morgen vor allem an Sonnenhängen zu einer zunehmenden Anfeuchtung der Schneedecke.
Seit Freitag war es sehr mild. Vor allem unterhalb der Waldgrenze: Die Schneeoberfläche gefriert kaum und ist schon am Morgen aufgeweicht.