Montag 23.02.2026

Veröffentlicht am 22.02.2026 um 17:00

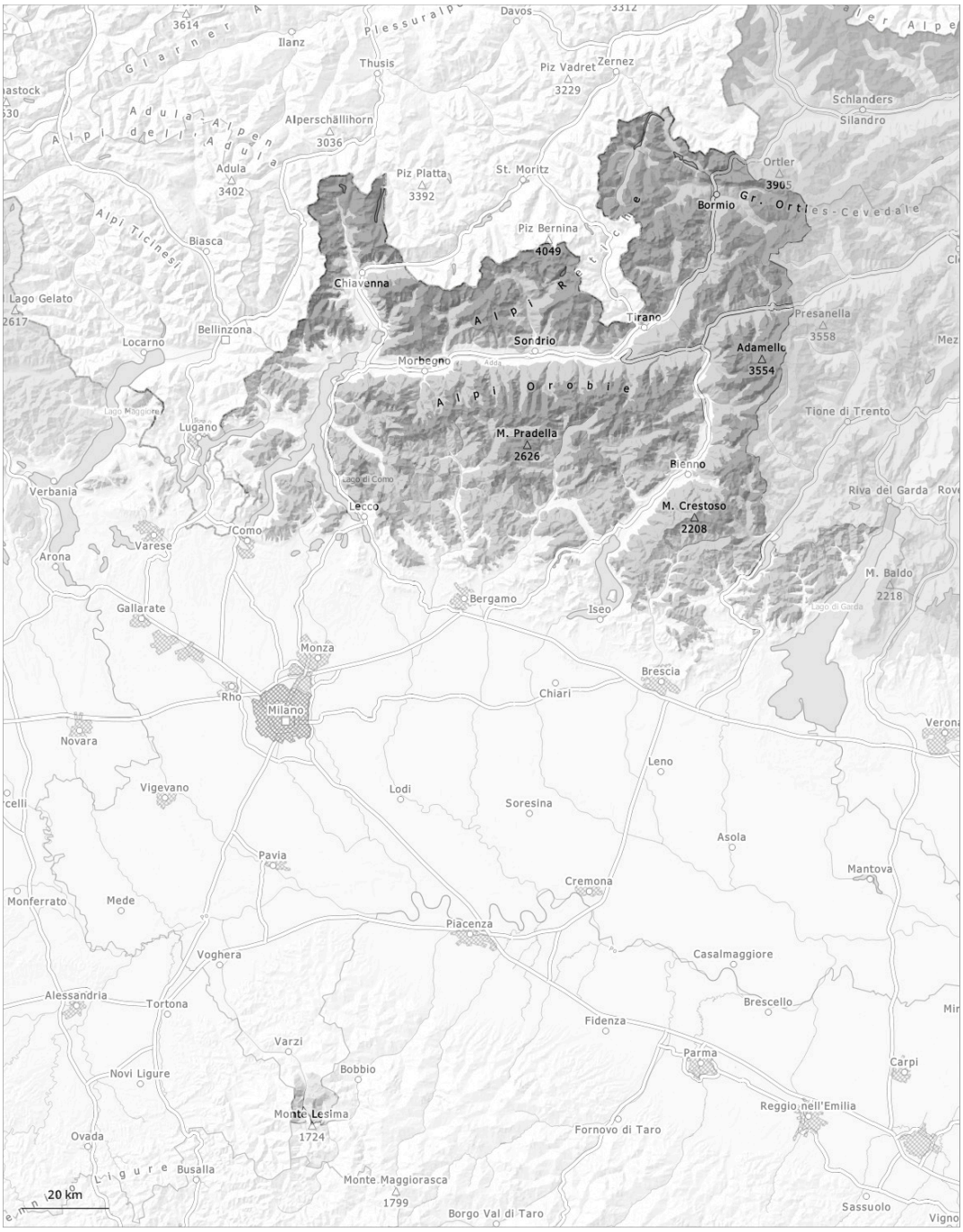

1	2	3	4	5
gering	mäßig	erheblich	groß	sehr groß

Gefahrenstufe 3 - Erheblich

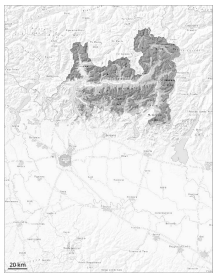

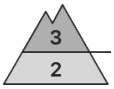

2100m

Tendenz: Lawinengefahr steigt
am Dienstag, den 24.02.2026

Altschnee

2100m

Triebschnee

Waldgrenze

Die Schneedecke ist oberhalb von rund 1700 m störanfällig. Neu- und Triebschnee sind die Hauptgefahr. Schwachschichten im Altschnee erfordern eine defensive Routenwahl.

Lawinen können leicht ausgelöst werden. Vorsicht vor Neu- und Triebschnee. Schwachschichten im Altschnee können schon von einzelnen Wintersportlern leicht ausgelöst werden, besonders an steilen West-, Nord- und Osthängen oberhalb der Waldgrenze sowie im Bereich der Waldgrenze. Lawinen können bis auf den Boden durchreißen und sehr groß werden. Die Gefahrenstellen sind zahlreich schwer zu erkennen.
Wummgeräusche und Risse beim Betreten der Schneedecke sind Alarmzeichen und weisen auf die Gefahr hin. Es besteht eine "große" Gefahr (Stufe 4) von spontanen Lawinen.

Schneedecke

Gefahrenmuster gm.6: lockerer schnee und wind | gm.1: bodennahe schwachschicht

Neu- und Triebschnee liegen vor allem an windgeschützten Schattenhängen auf Oberflächenreif. Der untere Teil der Schneedecke ist kantig aufgebaut und schwach. Lawinen können sehr leicht in tieferen Schichten ausgelöst werden.
Zudem sind die frischen Triebschneeansammlungen in Kammlagen, Rinnen und Mulden leicht auslösbar. An Triebschneehängen sind große bis sehr große spontane Lawinen möglich.

Tendenz

Mit dem Neuschnee nimmt die Anzahl der Gefahrenstellen im Tagesverlauf zu.

Gefahrenstufe 2 - Mäßig

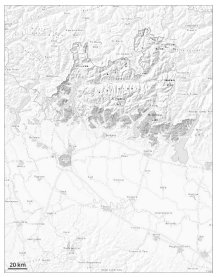

Tendenz: Lawinengefahr bleibt gleich
am Dienstag, den 24.02.2026

Triebschnee

1500m

Nassschnee

1400m

Schwachschichten im Altschnee erfordern Vorsicht und Zurückhaltung. Die Triebschneeansammlungen können vor allem an steilen Schattenhängen leicht ausgelöst werden oder spontan abgleiten.

Trockene Lawinen können auch in tieferen Schichten ausgelöst werden.
Der Neuschnee und insbesondere die teils großen Triebschneeansammlungen können von einzelnen Wintersportlern ausgelöst werden.

Schneedecke

Gefahrenmuster gm.6: lockerer schnee und wind | gm.1: bodennahe schwachschicht

In der Altschneedecke sind vor allem an steilen Nordwest-, Nord- und Nordosthängen heikle Schwachschichten vorhanden.

Gefahrenstufe 2 - Mäßig

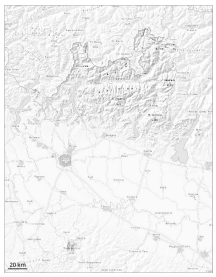

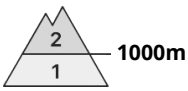

Tendenz: Lawinengefahr nimmt ab
am Dienstag, den 24.02.2026

Triebschnee

Nassschnee

Besonders in Kammlagen, Rinnen und Mulden und an Triebschneehängen sind kleine und mittlere Schneebrettlawinen möglich. Einzelne Tourengeher können stellenweise Lawinen auslösen, auch solche mittlerer Größe. Mit der Erwärmung steigt die Auslösebereitschaft von feuchten Lockerschneelawinen vor allem an steilen Südhängen in tiefen und mittleren Lagen allmählich an.

Gefahrenstellen für trockene Lawinen liegen vor allem an Triebschneehängen.

Schneedecke

Gefahrenmuster gm.6: lockerer schnee und wind | gm.10: frühjahrssituation

Tendenz

Mit milden Temperaturen verfestigt sich die Schneedecke.