Lunedì 23.02.2026

Pubblicato il 22.02.2026 alle ore 17:00

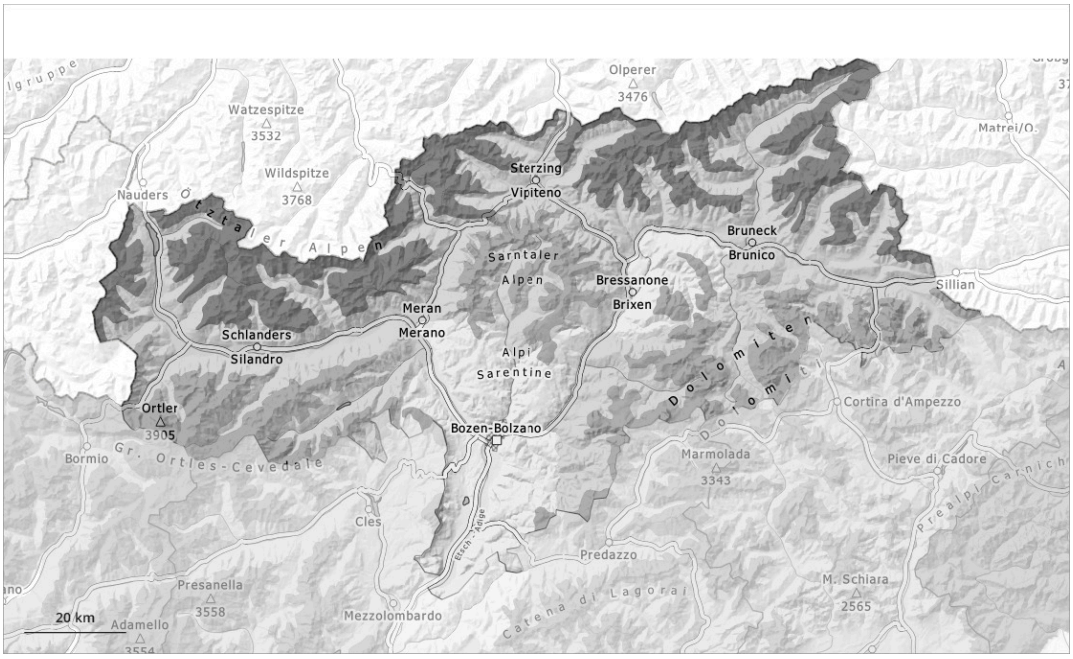

1	2	3	4	5
debole	moderato	marcato	forte	molto forte

Grado di pericolo 4 - Forte

Limite del bosco

Tendenza: pericolo valanghe in diminuzione
per Martedì il 24.02.2026

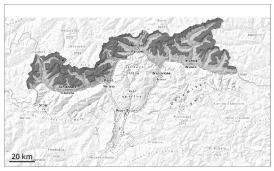

Strati deboli persistenti

Limite del bosco

Lastrone da vento

Limite del bosco

Neve bagnata

2200m

Al di fuori delle piste assicurate, la situazione valanghiva è pericolosa.

Gli accumuli di neve ventata rimangono instabili sui pendii esposti a ovest, nord ed est al di sopra del limite del bosco, attenzione, anche in prossimità del limite del bosco. Le valanghe possono distaccarsi coinvolgendo gli strati superficiali del manto.
Inoltre, le valanghe possono anche distaccarsi coinvolgendo gli strati basali del manto e, sui pendii esposti a ovest, nord ed est, raggiungere grandi dimensioni. I rumori di "whum" e la formazione di fessure quando si calpesta la coltre di neve così come nuove valanghe sono campanelli di allarme che rimandano a questo pericolo. A livello isolato sono possibili distacchi a distanza.

Con il rialzo termico e l'irradiazione solare diurni, sono possibili valanghe di neve umida a debole coesione. Ciò specialmente sui pendii soleggiati molto ripidi al di sotto dei 2200 m circa.

Manto nevoso

Situazione tipo st.1: strato debole persistente basale st.10: situazione primaverile

Il vento a tratti forte causerà il trasporto della neve. Si formeranno ulteriori accumuli di neve ventata.

Il manto nevoso è instabile in molti punti. La neve fresca e la neve ventata ricoprono un debole manto di neve vecchia. Gli accumuli di neve ventata meno recenti poggiano in parte su brina di superficie. Nella parte basale del manto di neve vecchia si trovano pronunciati strati fragili. Ciò soprattutto sui pendii esposti a ovest, nord ed est al di sopra del limite del bosco.

Nel corso della giornata le condizioni meteo causeranno un inumidimento del manto nevoso. Ciò specialmente sui pendii soleggiati molto ripidi.

Tendenza

Progressivo calo del pericolo di valanghe.

Grado di pericolo 3 - Marcato

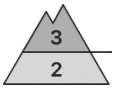

Limite del bosco

Tendenza: pericolo valanghe stabile
per Martedì il 24.02.2026

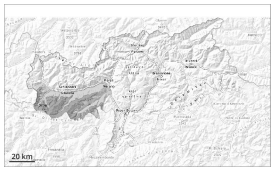

Strati deboli persistenti

Limite del bosco

Lastrone da vento

2000m

Neve bagnata

2200m

Sui pendii ombreggiati: Attenzione alla neve vecchia con strati deboli persistenti. Sui pendii molto ripidi esposti al sole: Con il rialzo termico, aumento del pericolo di valanghe di neve bagnata.

Le valanghe possono subire un distacco nella neve vecchia e, sui pendii esposti a ovest, nord ed est, raggiungere grandi dimensioni a livello isolato. Ciò da parte di un singolo appassionato di sport invernali. I punti pericolosi si trovano soprattutto al di sopra del limite del bosco. Nella zona di scorrimento le valanghe possono trascinare la neve bagnata. Ciò aumenta la distanza d'arresto delle valanghe.

Il vento ha causato il trasporto della neve. Soprattutto nelle zone in prossimità delle creste, nelle conche e nei canaloni così come in quota si sono formati accumuli di neve ventata in parte instabili.

Con il rialzo termico e l'irradiazione solare diurni, sono possibili valanghe di neve bagnata di piccole e medie dimensioni. Ciò soprattutto sui pendii soleggiati molto ripidi al di sotto dei 2200 m circa. Fare attenzione alle zone di deposito.

Manto nevoso

Situazione tipo st.1: strato debole persistente basale | st.10: situazione primaverile

Negli ultimi giorni sono caduti sino a 20 cm di neve, localmente anche di più. Il vento ha causato il trasporto della neve.
Soprattutto sui pendii esposti a ovest, nord ed est, all'interno del manto di neve vecchia si trovano pronunciati strati fragili.
L'irraggiamento notturno sarà ridotto. Nel corso della giornata le condizioni meteo causeranno un

graduale impregnamento del manto nevoso. Ciò sui pendii soleggiati molto ripidi al di sotto dei 2200 m circa.

Tendenza

L'attività di valanghe di neve bagnata aumenterà progressivamente.

Grado di pericolo 3 - Marcato

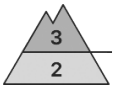

Limite del bosco

Tendenza: pericolo valanghe stabile
per Martedì il 24.02.2026

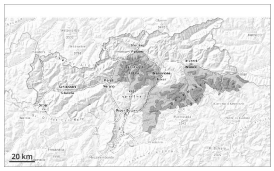

Strati deboli persistenti

Limite del bosco

Neve bagnata

2200m

Sui pendii ombreggiati: Attenzione alla neve vecchia con strati deboli persistenti. Sui pendii molto ripidi esposti al sole: Con il rialzo termico, aumento del pericolo di valanghe di neve bagnata.

Le valanghe possono subire un distacco nella neve vecchia e, sui pendii esposti a ovest, nord ed est, raggiungere grandi dimensioni a livello isolato. Ciò da parte di un singolo appassionato di sport invernali. I punti pericolosi si trovano soprattutto al di sopra del limite del bosco. Nella zona di scorrimento le valanghe possono trascinare la neve bagnata. Ciò aumenta la distanza d'arresto delle valanghe.

Con il rialzo termico e l'irradiazione solare diurni, sono possibili valanghe di neve bagnata di piccole e medie dimensioni. Ciò soprattutto sui pendii soleggiati molto ripidi al di sotto dei 2200 m circa. Fare attenzione alle zone di deposito.

Manto nevoso

Situazione tipo st.1: strato debole persistente basale | st.10: situazione primaverile

Negli ultimi giorni sono caduti da 20 a 40 cm di neve, localmente sino a 60 cm. Soprattutto sui pendii esposti a ovest, nord ed est, all'interno del manto di neve vecchia si trovano pronunciati strati fragili. L'irraggiamento notturno sarà ridotto. Nel corso della giornata le condizioni meteo causeranno un graduale impregnamento del manto nevoso. Ciò sui pendii soleggiati molto ripidi al di sotto dei 2200 m circa.

Tendenza

L'attività di valanghe di neve bagnata aumenterà progressivamente.

Grado di pericolo 3 - Marcato

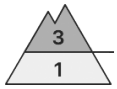

Limite del bosco

Tendenza: pericolo valanghe stabile
per Martedì il 24.02.2026

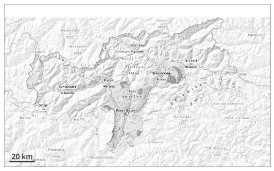

Strati deboli persistenti

Limite del bosco

Neve bagnata

2200m

La neve ventata recente deve essere valutata con spirito critico. Gli strati deboli presenti nella neve vecchia possono distaccarsi a livello isolato.

Le valanghe possono a livello isolato subire un distacco nella neve vecchia e, sui pendii esposti a ovest, nord ed est, raggiungere dimensioni medie a livello isolato. Ciò da parte di un singolo appassionato di sport invernali. Nella zona di scorrimento le valanghe possono trascinare la neve bagnata. Ciò aumenta la distanza d'arresto delle valanghe.

Con il rialzo termico e l'irradiazione solare diurni, sono possibili valanghe di neve bagnata di piccole e medie dimensioni. Ciò soprattutto sui pendii soleggiati molto ripidi al di sotto dei 2200 m circa. Fare attenzione alle zone di deposito.

Manto nevoso

Situazione tipo st.1: strato debole persistente basale | st.8: brina di superficie sepolta

Soprattutto sui pendii esposti a ovest, nord ed est, all'interno del manto di neve vecchia si trovano pronunciati strati fragili. L'irraggiamento notturno sarà ridotto. Nel corso della giornata le condizioni meteo causeranno un graduale impregnamento del manto nevoso. Ciò sui pendii soleggiati molto ripidi al di sotto dei 2200 m circa.

Tendenza

L'attività di valanghe di neve bagnata aumenterà lentamente.