BUTLLETÍ DEL PERILL D'ALLAUS DEL PRINCIPAT D'ANDORRA

Servei meteorològic nacional
Principat d'Andorra

Elaborat el 22/02/2026 16:00
Propera actualització 22/02/2026 a les 16h

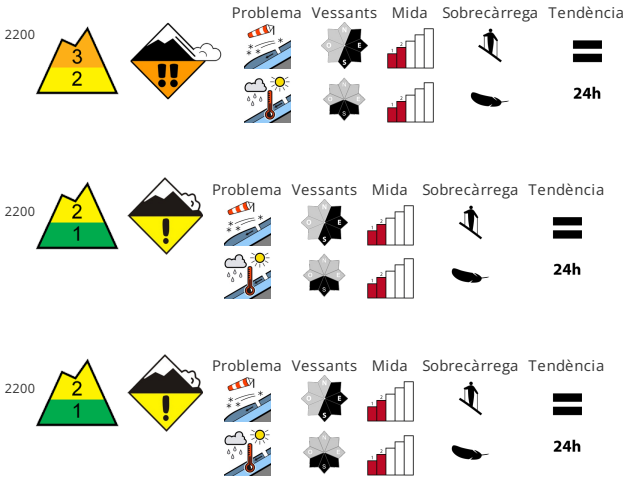

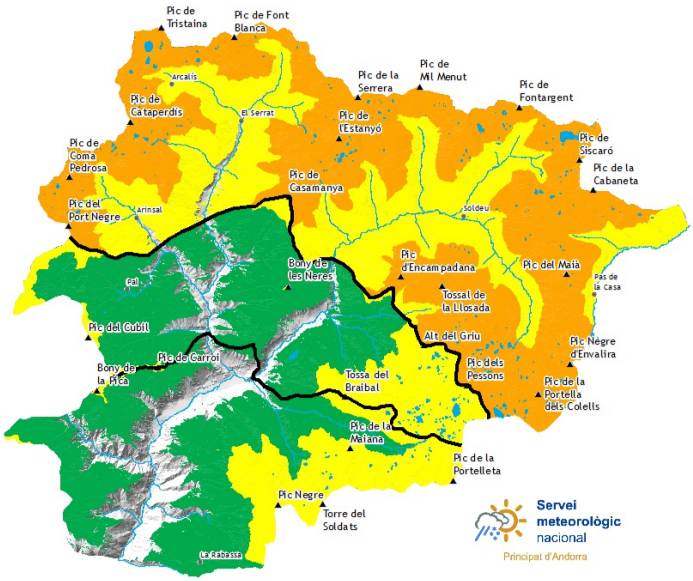

ESTABILITAT DEL MANTELL NIVAL

La neu recent i en particular les plaques de vent a vegades gruixudes poden fàcilment ser desencadenades de manera accidental o, de manera aïllada, natural en orientacions nord-est a fins al sud per l'est per sobre dels 2200 m aproximadament. Són especialment perillosos els vessants exposats a nord-est, est i sud-est , on al mantell de neu vella hi ha capes febles persistents. A més s'ha de tenir compte amb les plaques de vent tapades amb neu recent. Amb l'augment de la temperatura diürna i la radiació solar, són probables cada cop més nombroses allaus de placa humida de mida mitjana. A partir del migdia la probabilitat de desencadenament d'allaus humides augmentarà clarament sobretot als vessants assolellats inclinats. Això es dona especialment a la base de parets rocoses , i també en terreny dret i escarpat. A més, són possibles allaus de lliscament basal en qualsevol moment.

QUALITAT DE LA NEU

Els gruixos de neu varien molt per sobre dels 2500 m aproximadament per la influència del vent. Acumulacions de neu ventada més recents descansen a sobre d'una crosta. Evitar les zones amb esquerdes de lliscament basal.

GRUIXOS DEL MANTELL NIVAL FORA DE PISTA

Zona nord		Gruix neu		
Mantell Nival		1500m	2000m	2500m
N	1300 m	30 cm	150 cm	200 cm
S	1500 m	0 cm	100 cm	150 cm

Zona centre		Gruix neu		
Mantell Nival		1500m	2000m	2500m
N	1300 m	20 cm	150 cm	200 cm
S	1500 m	0 cm	100 cm	150 cm

Zona sud		Gruix neu		
Mantell Nival		1500m	2000m	2500m
N	1300 m	20 cm	120 cm	150 cm
S	1500 m	0 cm	60 cm	100 cm

Govern d'Andorra

EAWS EUROPEAN AVALANCHE WARNING SERVICES

Aquest butlletí ha estat elaborat seguint les normes i recomanacions de l'**European Avalanche Warning Services**, del qual el **Servei meteorològic Nacional** n'és membre

Informació detallada per espais naturals protegits

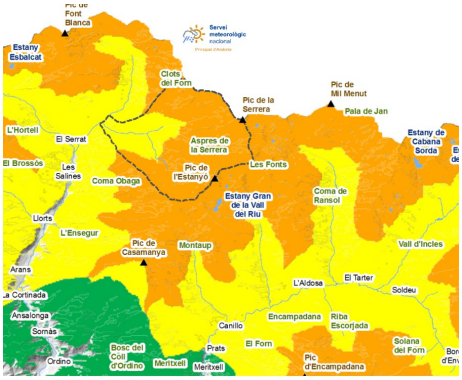

SORTENY

La nevada de dijous va afegir alguns centímetres a cotes baixes per sobre de la crosta de regel. A cotes altes es va acumular més neu, fet que farà més agradables les excursions, sobretot per sota del límit del bosc. En altura la neu estarà més ventada i amb distribucions molt irregulars, sovint encrostada. Trobem neu a tots els camins des de Llorts i l´accés amb esquís fins al Refugi es pot fer com feia anys que no es veia durant tantes setmanes seguides. Haurem de seguir les recomanacions de l´estabilitat del mantell nival per evitar posar-nos en perill als vessants est. Amb l´augment de temperatures apareixeran problemes de neu humida als vessants sud, fet que en un primer moment comportarà un augment de l´activitat d´allaus, però ajudarà a estabilitzar el mantell.

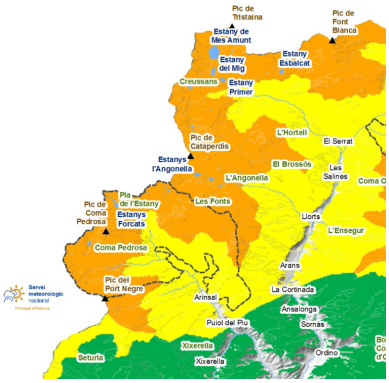

COMAPEDROSA

A cotes baixes la neu s´ha compactat i ha reduït el seu gruix a causa de l´humidificació provocada per les pluges de fa una setmana. Per sobre d´aquesta crosta, però, hi ha una mica de neu nova. A dins del bosc serà menys abundant i haurem de vigilar a no relliscar, però a les clarianes i a les parts altes aïllarà el gel. Tot i així, la distribució de la neu és molt irregular a causa del vent. Als vessants orientats a est, com pot ser l´accés des d´Arinsal pel Port Negre (Sanfons) haurem d´extremar les precaucions o evitar-los per no desencadenar les plaques de vent formades aquests darrers dies. El problema de neu humida anirà a més durant el cap de setmana.

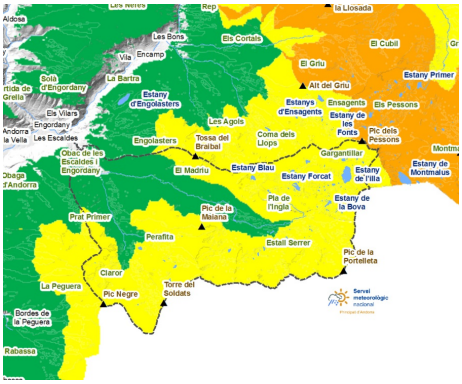

MADRIU-PERAFITA-CLAROR

Als vessants est s´hi ha de circular amb molta cautela, ja que és on hi ha les acumulacions de neu ventada més importants i perilloses. A cotes altes els vent haurà deixat la neu dura al descobert i amb condicions difícils de baixar en algunes ocasions.

BUTLLETÍ DEL PERILL D'ALLAUS DEL PRINCIPAT D'ANDORRA

Servei meteorològic nacional
Principat d'Andorra

Gruixos de neu nova dels darrers dies (de les últimes 24h mesurat a les 06:00h UTC)

	18/02/2026	19/02/2026	20/02/2026	21/02/2026
FEDA (Central)	0 cm	0 cm	0 cm	0 cm
Engolasters - FEDA	0 cm	0 cm	0 cm	0 cm
Bony de les Neres	0 cm	4 cm	0 cm	0 cm
Sorteny	3 cm	16 cm	0 cm	0 cm
Perafita	0 cm	9 cm	0 cm	0 cm
Tossa Espiolets	1 cm	0 cm	53 cm	0 cm
Grau Roig - FEDA	3 cm	1 cm	0 cm	0 cm
Fontverd	3 cm	2 cm	0 cm	0 cm
Ransol - FEDA	0 cm	0 cm	0 cm	0 cm
Setúria	2 cm	4 cm	0 cm	0 cm
Caborreu	0 cm	0 cm	0 cm	0 cm
La Solana	6 cm	0 cm	0 cm	0 cm
Envalira Antenes	2 cm	1 cm	0 cm	0 cm
Vall del Riu FEDA	2 cm	19 cm	0 cm	0 cm