MINISTERO DELLA DIFESA

meteomont
Servizio Nazionale di previsione neve e valanghe

EAWS EUROPEAN AVALANCHE WARNING SERVICES

CARABINIERI

AERONAUTICA MILITARE SERVIZIO METEOROLOGICO

ALPI RETICHE

Bollettino Valanghe N. 355/2026 del 22/02/2026 ore 14.00
Validità 48 ore prossima emissione 23/02/2026

A cura del Servizio METEOMONT dell'ARMA dei CARABINIERI
In collaborazione con Servizio Meteorologico dell'Aeronautica militare

SITUAZIONE alle 14:00 del 22/02/2026

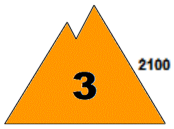

SITUAZIONE TIPO: neve a debole coesione e vento.



SITUAZIONE TIPO: strato debole persistente basale.

Quota neve (mslm)	Nord	Sud
	1100	1300

Altezza Neve (cm)	Neve al suolo	Neve Fresca	Quota (mslm)
	65	0	2582
	94	10	2150

VALANGHE OSSERVATE: Nessuna valanga.

PREVISIONI 23/02/2026

GRADO DI PERICOLO: MARCATO 3

SITUAZIONE TIPO: neve a debole coesione e vento.

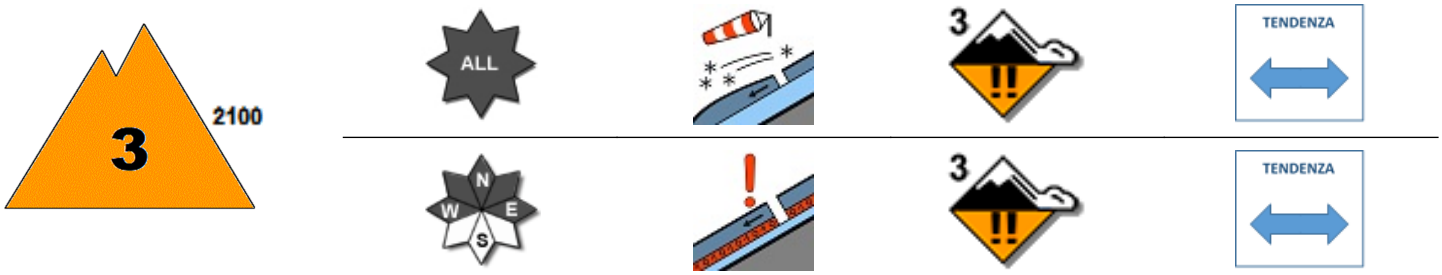

SITUAZIONE TIPO: strato debole persistente basale.

MANTO NEVOSO: La stabilità del manto nevoso è scarsa su alcuni punti (aree) per tutte le esposizioni al di sopra di 2100 mslm, possibili valanghe di dimensioni grandi.
La stabilità del manto nevoso è scarsa su molti punti (aree) per versanti da ovest a est al di sotto di 2100 mslm, possibili valanghe di dimensioni medie.

AVVERTENZE

A seguito dell'attività eolica registrata sono da evitare le zone di accumulo, conche, canaloni, cambi di pendenza e pendii sotto vento in genere.

SCALA EUROPEA DEL GRADO DI PERICOLO VALANGHE

LEGENDA PROBLEMA

Bollettino realizzato su scala sinottica-regionale (standard EAWS). La sua valutazione non può escludere in alcun modo la necessità di una seria e capace valutazione locale del pericolo (singolo pendio) che può essere anche sensibilmente diverso. Le previsioni meteorologiche sono relative all'orario UTC (per l'Italia +1 in inverno e +2 in estate).

MINISTERO DELLA DIFESA

meteomont
Servizio Nazionale di previsione neve e valanghe

EAWS EUROPEAN AVALANCHE WARNING SERVICES

CARABINIERI

ALPI RETICHE

PREVISIONE METEO

Quota		23/02/2026 h6:00	23/02/2026 h12:00	23/02/2026 h18:00
1000	Venti	03 nodi da N-Ovest	02 nodi da N-Ovest	02 nodi da N-Ovest
	Temperature	+03 °C	+03 °C	+01 °C
	Temp.percepita	2 °C	3 °C	1 °C
2000	Venti	03 nodi da N-Ovest	02 nodi da N-Ovest	02 nodi da N-Ovest
	Temperature	+03 °C	+03 °C	+01 °C
	Temp.percepita	2 °C	3 °C	1 °C
3000	Venti	14 nodi da N-Ovest	11 nodi da N-Ovest	12 nodi da N-Ovest
	Temperature	-04 °C	-05 °C	-05 °C
	Temp.percepita	-11 °C	-12 °C	-12 °C
Zero termico		2400-2600 m.	2400-2600 m.	2300-2500 m.
Fenomeno		—	—	—
Stato del cielo				

LEGENDA FENOMENI

— Assenza Fenomeni · Nebbia · Foschia · Pioggia debole · Pioggia moderata · Pioggia forte · Temporali

Nevicata debole · Nevicata moderata · Nevicata forte

STATO DEL CIELO

Sereno · Poco nuvoloso · Nuvoloso · Molto nuvoloso · Coperto

Parametri meteonivometrici registrati presso i campi di rilevamento il 22/02/2026.

Località	Comune	Quota (m.s.l.m.)	Altezza neve (cm)	Neve caduta nelle 24 ore (cm)	Temp. Min (°C)	Temp. Max (°C)	Condizioni del tempo
SPONDA	Livigno (SO)	2150	94	10	-5	0	Assenza di precipitazioni
DOSSO DEL VALLONE	Valfurva (SO)	2582	65	4	-6	-4	Assenza di precipitazioni
COLONIA VIGILI	Ponte di Legno (BS)	1640	70	0	-2	+8	Assenza di precipitazioni

(*) Rilievi fuori campo

L'INFORMAZIONE E' PREVENZIONE - LEGGI L'ATTUALE GRADO DI PERICOLO VALANGHE!

IL CAPO DEL CENTRO NAZIONALE METEOMONT
(Ten. Col. RFI Emanuela Gini)
FIRMA AUTOGRAFA OMESSA AI SENSI
DELL'ART.3 DEL D.LGS N.39/1993