# Bulletin d'estimation du risque d'avalanche

(valable en dehors des pistes balisées et ouvertes)

# MASSIF : Bauges

Rédigé le dimanche 22 février 2026 à 16h

## Estimation des risques pour le : LUNDI 23 FÉVRIER

REDOUX ET PLAQUES DE FOND

2

2

N O E S

Indice de risque limité.

**Départs spontanés :** Plaques de fond

**Déclenchements provoqués :** rares plaques à vent en ubacs d'altitude.

Indices de risque : 5 très fort - 4 fort - 3 marqué - 2 limité - 1 faible -- En noir : les pentes les plus dangereuses

## Stabilité du manteau neigeux

**Situation avalancheuse typique :** avalanches de fond

**Départs spontanés :**

* A toutes altitudes : **plaques de fond**. Tous versants, mais départs plus nombreux dans les pentes sud. Départs dans les pentes raides et lisses (pentes herbeuses, dalles rocheuses). Taille 2 (moyenne) à 3 (grande).

*** Chutes de corniches**, épaisses et volumineuses, **pouvant solliciter de très larges plaques friables.**

**Déclenchements provoqués :**

* Au-dessus de 1800 m : quelques plaques dans la neige récente. Surtout dans les ubacs des plus hauts sommets. Taille 1 à 2 (petite à moyenne).

## Qualité de la neige

Enneigement : Bon pour la saison à toutes altitudes grâce aux fréquentes chutes de neige du mois de février. On peut chausser les skis vers 1200 m dans tous les versants. L'épaisseur du manteau neigeux varie : nombreuses congères et corniches.

Qualité de la neige lundi :

- En dessous de 1800 m : crouté le matin, puis neige humide et très lourde.
- Au-dessus de 1800 m : finement crouté le matin qui s'humidifie en journée. En ubacs, proche des plus hauts sommets, neige encore froides et denses

## Aperçu météo pour le lundi 23 février

| nuit | matin | après-midi | soir |
|---|---|---|---|

Nuageux toute la journée. Températures très douces : de 1 à 8°C à 1500 m .

| Pluie-Neige | | | | |
|---|---|---|---|---|
| Iso 0 °C | 2 800 m | 2 300 m | 2 400 m | 2 600 m |
| Vent 1500 m | 15 km/h | 10 km/h | 15 km/h | 10 km/h |
| Vent 2000 m | 25 km/h | 20 km/h | 20 km/h | 20 km/h |

## Épaisseur de neige hors-piste

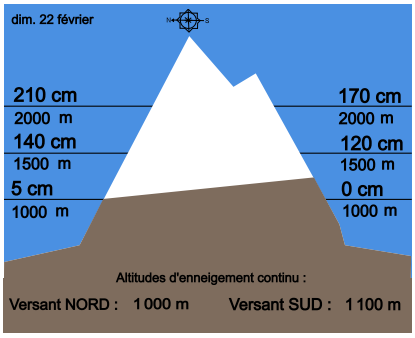


## Précipitations à 1800 m

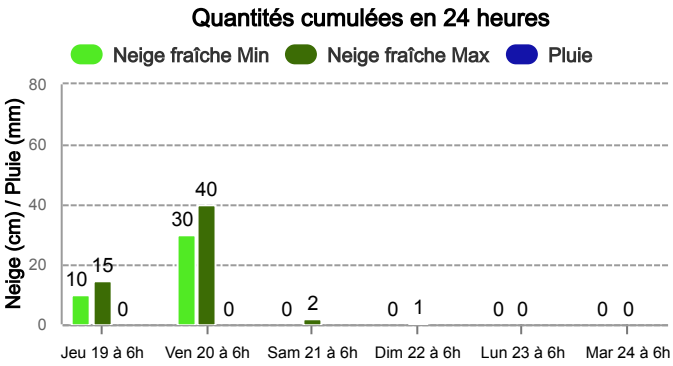


## Tendance du mardi 24 février

2

**Indice de risque limité**

Risque stationnaire. Ensoleillé et températures en hausse.

Pour consulter la vigilance en cours, veuillez vous rendre sur le site https://vigilance.meteofrance.fr/fr


Météo-France - 73 avenue de Paris, 94165 Saint-Mandé cedex - Contact : contact@meteo.fr



Rédigé par Météo-France avec la contribution des observateurs du réseau nivo-météorologiques. Partenariat : ANMSM (Maires de Stations de Montagne), DSF (Domaines Skiables de France), ADSP (Directeurs de Pistes et de la Sécurité des Stations de Sports d'Hiver) et autres acteurs de la montagne.



Bulletin neige & avalanches par téléphone au 0 892 68 10 20 Service 0,35 € / min + prix appel

RÉPUBLIQUE FRANÇAISE
*Liberté Égalité Fraternité*

METEO FRANCE
À VOS CÔTÉS, DANS UN CLIMAT QUI CHANGE

# Bulletin d'estimation du risque d'avalanche

## (valable en dehors des pistes balisées et ouvertes)

# MASSIF : Bauges

Rédigé le dimanche 22 février 2026 à 16h

## Conditions nivo-météo des 7 derniers jours

| | lun. 16/02 | | | | mar. 17/02 | | | | mer. 18/02 | | | | jeu. 19/02 | | | | ven. 20/02 | | | | sam. 21/02 | | | | dim. 22/02 | | | |
|---|---|---|---|---|---|---|---|---|---|---|---|---|---|---|---|---|---|---|---|---|---|---|---|---|---|---|---|---|
| | 03h | 09h | 15h | 21h | 03h | 09h | 15h | 21h | 03h | 09h | 15h | 21h | 03h | 09h | 15h | 21h | 03h | 09h | 15h | 21h | 03h | 09h | 15h | 21h | 03h | 09h | 15h | 21h |
| Météo | | | | | | | | | | | | | | | | | | | | | | | | | | | | |
| Vent (km/h) | 45 | 55 | 60 | 55 | 55 | 50 | 40 | 30 | 15 | 25 | 25 | 60 | 40 | 40 | 30 | 45 | 55 | 35 | 25 | 25 | 25 | 25 | 30 | 30 | 25 | 25 | 25 | 20 |
| à 2000m | | | | | | | | | | | | | | | | | | | | | | | | | | | | |
| Vent (km/h) | 30 | 45 | 50 | 40 | 40 | 40 | 25 | 20 | 10 | 20 | 20 | 40 | 25 | 30 | 25 | 30 | 40 | 25 | 20 | 15 | 20 | 15 | 15 | 10 | 10 | 5 | 15 | 10 |
| à 1500m | | | | | | | | | | | | | | | | | | | | | | | | | | | | |

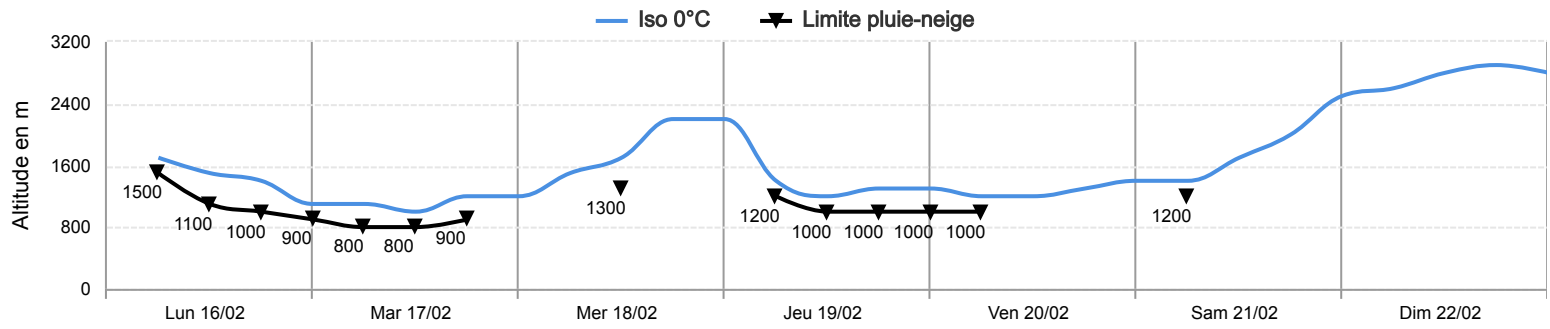


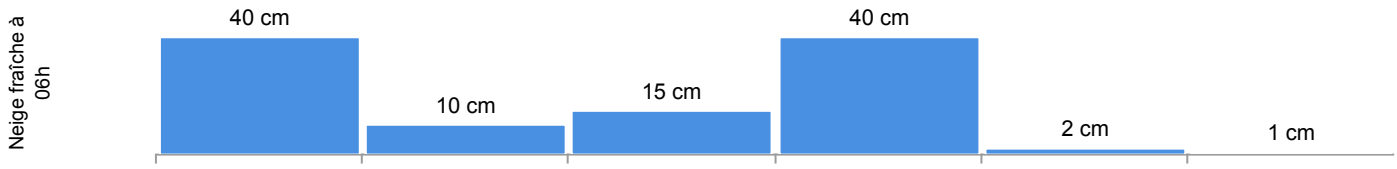


| Risque d'avalanche | lun. 16/02 | mar. 17/02 | mer. 18/02 | jeu. 19/02 | ven. 20/02 | sam. 21/02 | dim. 22/02 |
|---|---|---|---|---|---|---|---|
| | 4 | 4 | 4 | 4 | 4 | 4 | 2 |

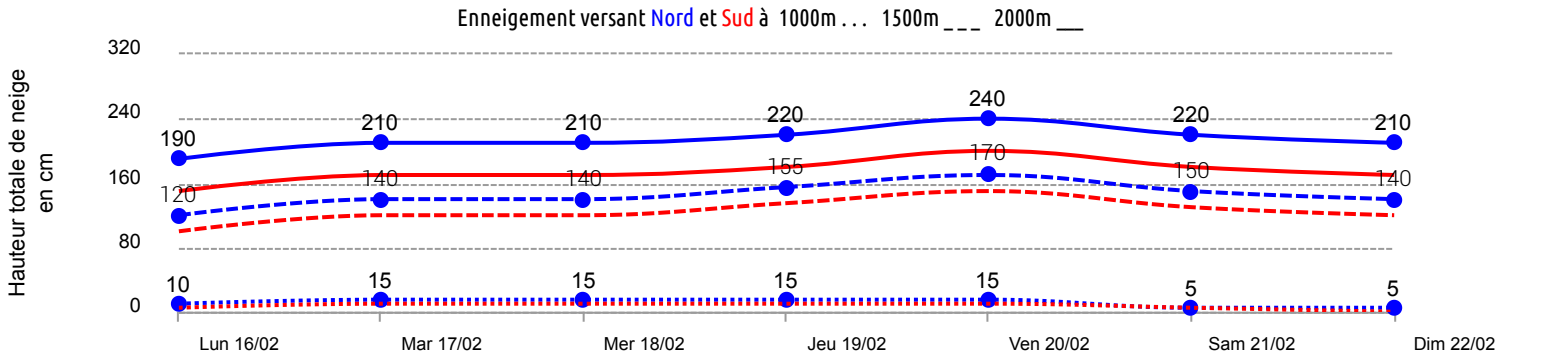


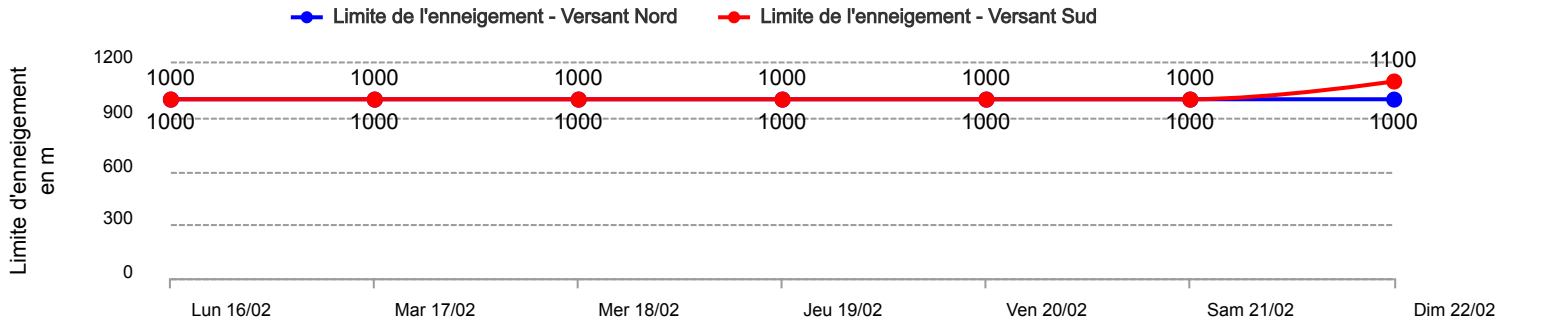


Pour consulter la vigilance en cours, veuillez vous rendre sur le site https://vigilance.meteofrance.fr/fr


**Météo-France - 73 avenue de Paris, 94165 Saint-Mandé cedex - Contact : contact@meteo.fr**



Rédigé par Météo-France avec la contribution des observateurs du réseau nivo-météorologiques. Partenariat : ANMSM (Maires de Stations de Montagne), DSF (Domaines Skiables de France), ADSP (Directeurs de Pistes et de la Sécurité des Stations de Sports d'Hiver) et autres acteurs de la montagne.



Bulletin neige & avalanches par téléphone au
0 892 68 10 20 Service 0,35 € / min + prix appel