Bulletin d'estimation du risque d'avalanche

(valable en dehors des pistes balisées et ouvertes)

MASSIF : Beaufortain

Rédigé le dimanche 22 février 2026 à 16h

Estimation des risques pour le : LUNDI 23 FÉVRIER

LE MANTEAU SE TASSE ET S'HUMIDIFIE BEAUCOUP SOUS 2300M ET SE STABILISE LENTEMENT AU DESSUS

2

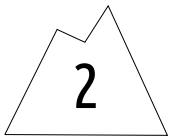

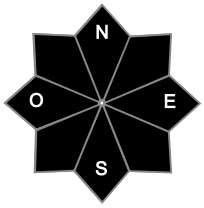

Indice de risque limité.

Départs spontanés : Plaques de fond parfois épaisses et glissement de talus sous 2300m

Déclenchements provoqués : Rares plaques encore réactives dans les secteurs restés en poudre ou en neige ventée.

Indices de risque : 5 très fort - 4 fort - 3 marqué - 2 limité - 1 faible -- En noir : les pentes les plus dangereuses

Stabilité du manteau neigeux

Situation avalancheuse typique : avalanches de fond couche fragile persistante

Départs spontanés : **Plaques de fond et glissement de talus possible en tous versants sous 2300/2400 m,** avec des températures positives sous un ciel attendu couvert le réchauffement du manteau neigeux en cours va se poursuivre ce lundi. Départ possible, surtout dans les pentes raides et herbeuses, les épaisseurs de neige étant notables dès ces moyennes altitudes (100-150 cm), **les volumes mobilisés sont conséquents** et les avalanches de taille 2 voir rare 3

Déclenchements provoqués : **Rares plaques friables ou dures encore sensibles au passage d'un ou plusieurs skieurs.** On retrouve ces plaques **dans la neige restée froide/poudreuse** (non croutée) donc dès **2100/2300 m en Nord et Nord-Est,** beaucoup **plus haut et de façon localisé dans les autres orientations.** La probabilité de déclenchement baisse de jour en jour. Ces plaques restent toutefois sensible là où elle **reposent sur des couches fragiles persistantes pas trop profondément enfouies:** donc plutôt dans les secteurs moins enneigés comme les abords des crêtes ou croupes ventées. Se méfiez aussi des zones où des départs ont déjà eu lieu et qui ne sont maintenant recouvert que par la dernière chute. Au vu des forts cumuls de neige récente encore moyennement stabilisés, les **cassures peuvent être très épaisses (jusqu'à 2m)** donnant des avalanches de **taille 2 (moyennes)** voir exceptionnellement **3 (grande avalanche).**

Qualité de la neige

Enneigement : excédentaire à toutes les altitudes et dans tous les versants. Les départs classiques de ski de randonnée sont copieusement enneigés. Les trois perturbations qui se sont succédé ont permis d'épaissir le manteau d'au moins 150 cm à partir de 2000 m.

Limite skiable : skiable dès 900 m dans les prairies orientées Nord, plutôt 1100/1200 m en Sud pas trop raide.

Qualité de la neige : Sous 2200/2300m en toute orientation neige croutée non portante le matin devenant humide et toujours assez lourde une fois la croute de surface ramollie.
Au dessus croutée en sud toute la journée avec un localement léger saupoudrage en matinée.
Il faut monter au dessus de 2300m en Nord pour trouver une neige encore froide le matin, celle ci pourrait s'humidifier et botter en journée sous les nuages qui font réchauffer la neige jusque vers 2500m. La neige ne restera poudreuse ou durcie par le vent qu'au dessus de 2500m.

Aperçu météo pour le lundi 23 février

nuit	matin	après-midi	soir

Dégagé en soirée mais couvert dès ce lundi matin, quelques flocons possible en matinée/mi-journée max 1/2cm à 2000m.

Pluie-Neige		1 900 m		
Iso 0 °C	2 700 m	2 300 m	2 400 m	2 500 m
Vent 2000 m	↘ 15 km/h	↘ 15 km/h	→ 15 km/h	↘ 10 km/h
Vent 3000 m	→ 35 km/h	↘ 30 km/h	↘ 30 km/h	↓ 35 km/h

Épaisseur de neige hors-piste

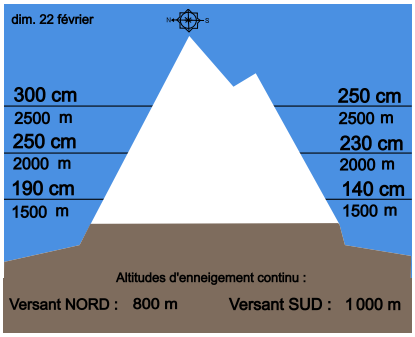

Précipitations à 1800 m

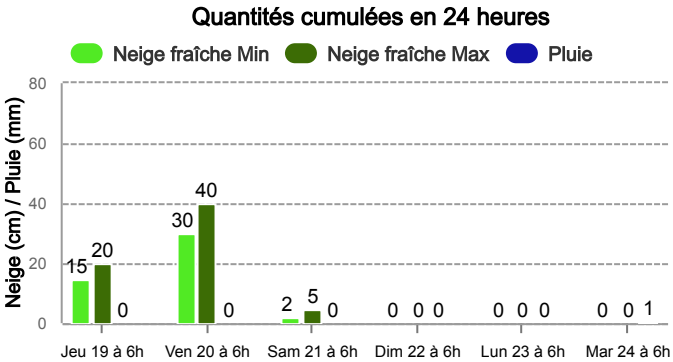

Tendance du mardi 24 février

2

Indice de risque limité

Bon regel nocturne grâce au ciel clair et forte chaleur en journée. L'humidification du manteau va, en journée, gagner en profondeur dans les pentes ensoleillées engendrant de nouvelles et parfois grandes avalanches de neige humide. Le risque de plaque se cantonne lui peu à peu aux pentes froides de haute altitude.

Pour consulter la vigilance en cours, veuillez vous rendre sur le site https://vigilance.meteofrance.fr/fr

Météo-France - 73 avenue de Paris, 94165 Saint-Mandé cedex - Contact : contact@meteo.fr

Rédigé par Météo-France avec la contribution des observateurs du réseau nivo-météorologiques. Partenariat : ANMSM (Maires de Stations de Montagne), DSF (Domaines Skiables de France), ADSP (Directeurs de Pistes et de la Sécurité des Stations de Sports d'Hiver) et autres acteurs de la montagne.

Bulletin neige & avalanches par téléphone au
0 892 68 10 20 Service 0,35 € / min + prix appel

Bulletin d'estimation du risque d'avalanche

(valable en dehors des pistes balisées et ouvertes)

MASSIF : Beaufortain

Rédigé le dimanche 22 février 2026 à 16h

Conditions nivo-météo des 7 derniers jours

	lun. 16/02				mar. 17/02				mer. 18/02				jeu. 19/02				ven. 20/02				sam. 21/02				dim. 22/02			
	03h	09h	15h	21h	03h	09h	15h	21h	03h	09h	15h	21h	03h	09h	15h	21h	03h	09h	15h	21h	03h	09h	15h	21h	03h	09h	15h	21h
Météo																												
Vent (km/h)	70	80	80	75	70	60	50	30	35	35	35	40	50	40	50	55	55	50	40	45	40	35	40	45	30	20	20	20
à 3000m																												
Vent (km/h)	35	55	60	60	60	50	40	20	15	15	15	30	40	30	35	45	45	35	25	30	25	20	25	30	20	10	10	10
à 2000m																												

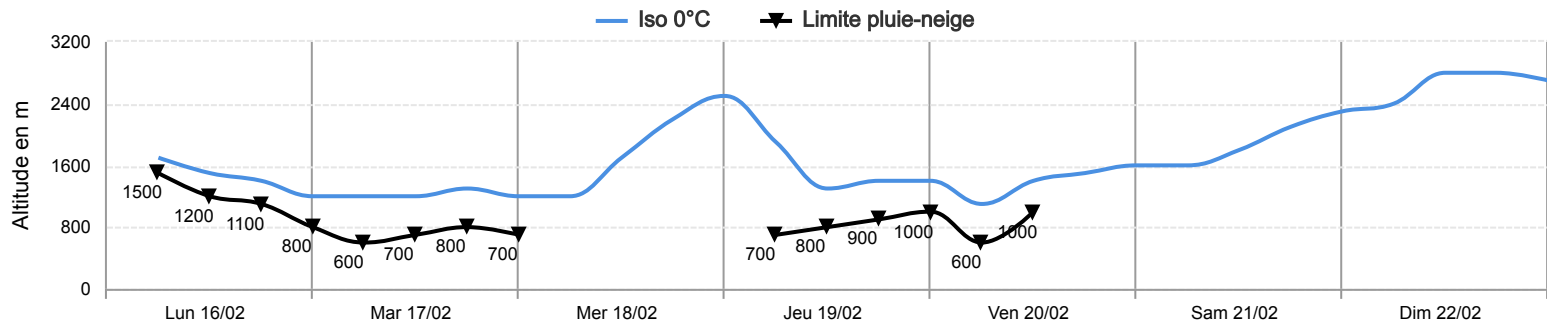

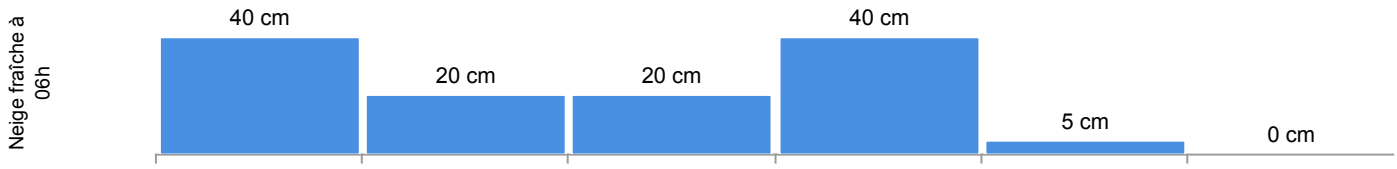

Risque d'avalanche	lun. 16/02	mar. 17/02	mer. 18/02	jeu. 19/02	ven. 20/02	sam. 21/02	dim. 22/02
	4	4	4	5	4	4	3

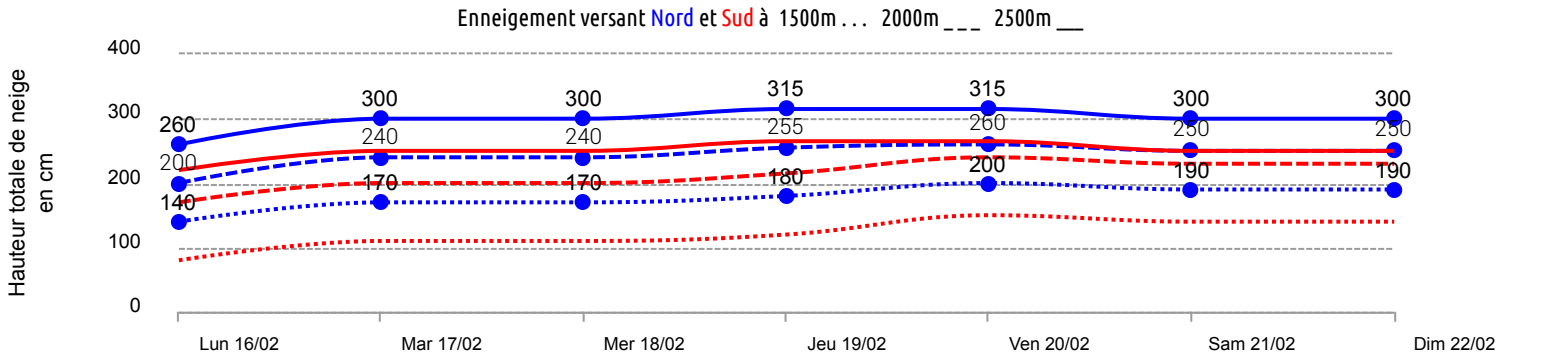

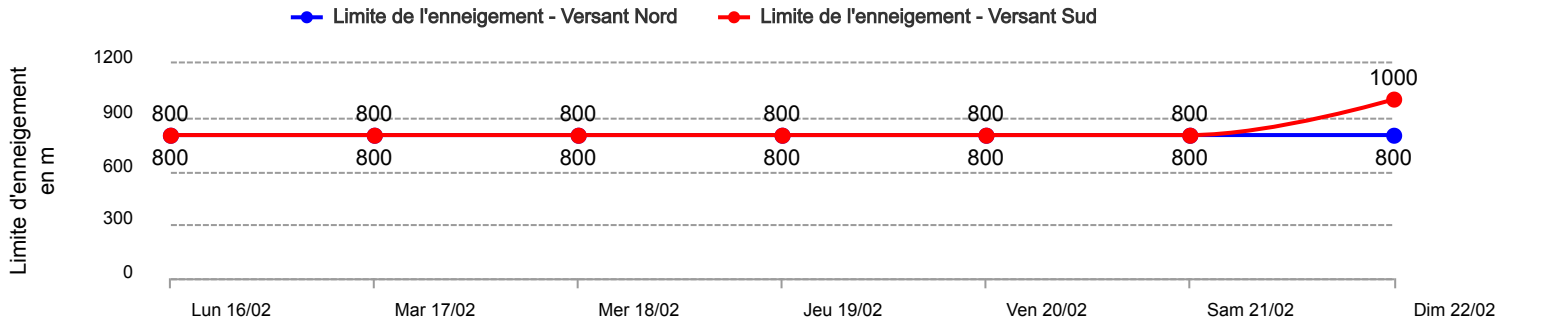

Pour consulter la vigilance en cours, veuillez vous rendre sur le site https://vigilance.meteofrance.fr/fr

Météo-France - 73 avenue de Paris, 94165 Saint-Mandé cedex - Contact : contact@meteo.fr

Rédigé par Météo-France avec la contribution des observateurs du réseau nivo-météorologiques. Partenariat : ANMSM (Maires de Stations de Montagne), DSF (Domaines Skiables de France), ADSP (Directeurs de Pistes et de la Sécurité des Stations de Sports d'Hiver) et autres acteurs de la montagne.

Bulletin neige & avalanches par téléphone au 0 892 68 10 20 Service 0,35 € / min + prix appel