RÉPUBLIQUE FRANÇAISE
Liberté Égalité Fraternité

METEO FRANCE
À VOS CÔTÉS, DANS UN CLIMAT QUI CHANGE

Bulletin d'estimation du risque d'avalanche

(valable en dehors des pistes balisées et ouvertes)

MASSIF : Cerdagne Canigou

Rédigé le dimanche 22 février 2026 à 16h

Estimation des risques pour le : LUNDI 23 FÉVRIER

PLAQUES EN ALTITUDE ET AVALANCHES DE NEIGE HUMIDE AU SOLEIL

2

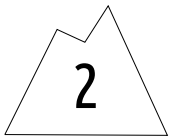

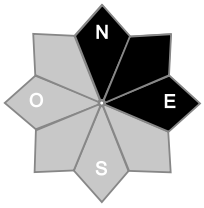

Indice de risque limité.

Départs spontanés : Au fil de l'ensoleillement

Déclenchements provoqués : Plaques encore peu stabilisées en altitude

Indices de risque : 5 très fort - 4 fort - 3 marqué - 2 limité - 1 faible -- En noir : les pentes les plus dangereuses

Stabilité du manteau neigeux

Situation avalancheuse typique : neige ventée neige humide

Déclenchements provoqués :
Nombreuses **structures de plaques** présentes dans la neige tombée en fin de semaine dernière. Certaines sont encore **facilement déclenchables** dans les secteurs où la neige est restée froide (pentes ombragées ou à haute altitude). Avec le vent qui a soufflé fort, elles sont situées parfois loin des crêtes. Des cassures au maximum de quelques dizaines de centimètres sont à attendre dans un vaste secteur nord à est. Ces plaques pourront être friables ou dures, suivant l'intensité du vent leur ayant donné naissance. La couche fragile majoritairement composée de neige moins ventée est en voie de stabilisation mais on pourra parfois trouver des grains anguleux enfouis pouvant aussi jouer ce rôle de manière plus persistante.
Observables : Fissures devant les skis, "whoomfs" au passage d'un pratiquant. Les plaques friables restent toutefois difficilement détectables, car d'aspect poudreux.

Départs spontanés :
Avalanches petites à moyennes avec des départs ponctuels en **neige humide** dans les pentes raides au fil de l'ensoleillement.
Observables : Boulettes/escargots, perte de cohésion de la neige avec l'humidification
En dessous de 2000m principalement, des avalanches de fond sont aussi possibles à toute heure, de taille petite à moyenne.
Observables : reptations, gueules de baleine

Autre : Chutes de corniches probables avec la poursuite de l'humidification.

Qualité de la neige

Enneigement :
A la faveur des multiples passages perturbés qui se sont succédé depuis le début de l'année, l'enneigement est largement supérieur à celui des cinq dernières années et se situe au plus haut par rapport aux statistiques plus anciennes. Avec le redoux, la limite d'enneigement remonte un peu mais on pourra encore chausser les skis vers 1500m dans les conditions les plus favorables.

Qualité de la neige :
En matinée, on trouvera dans de nombreux secteurs en dessous de 2100m une neige croutée plus ou moins portante. Au fil des heures et de l'ensoleillement, cette croute sera remplacée par de la neige humide et lourde. En journée, on trouvera des conditions de neige de printemps dans un vaste secteur sud et une neige qui reste froide mais bien travaillée par le vent dans les secteurs ombragés d'altitude. Certaines crêtes sont dégarnies pendant que d'autres sont couvertes de quelques cm de glace dure.

Aperçu météo pour le lundi 23 février

	nuit	matin	après-midi	soir
Grande douceur avec soleil parfois voilé				
Pluie-Neige				
Iso 0 °C	3 500 m	3 300 m	3 300 m	3 300 m
Vent 2000 m	↗ 10 km/h	← 10 km/h	→ 10 km/h	↘ 10 km/h
Vent 3000 m	↗ 20 km/h	← 20 km/h	↘ 20 km/h	↘ 15 km/h

Pour consulter la vigilance en cours, veuillez vous rendre sur le site https://vigilance.meteofrance.fr/fr

Météo-France - 73 avenue de Paris, 94165 Saint-Mandé cedex - Contact : contact@meteo.fr

Rédigé par Météo-France avec la contribution des observateurs du réseau nivo-météorologiques. Partenariat : ANMSM (Maires de Stations de Montagne), DSF (Domaines Skiables de France), ADSP (Directeurs de Pistes et de la Sécurité des Stations de Sports d'Hiver) et autres acteurs de la montagne.

Bulletin neige & avalanches par téléphone au
0 892 68 10 20 Service 0,35 € / min + prix appel

Bulletin d'estimation du risque d'avalanche

(valable en dehors des pistes balisées et ouvertes)

MASSIF : Cerdagne Canigou

Rédigé le dimanche 22 février 2026 à 16h

Épaisseur de neige hors-piste

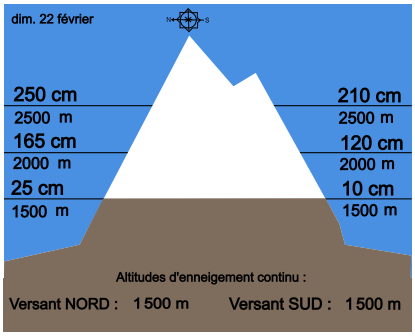

Précipitations à 1800 m

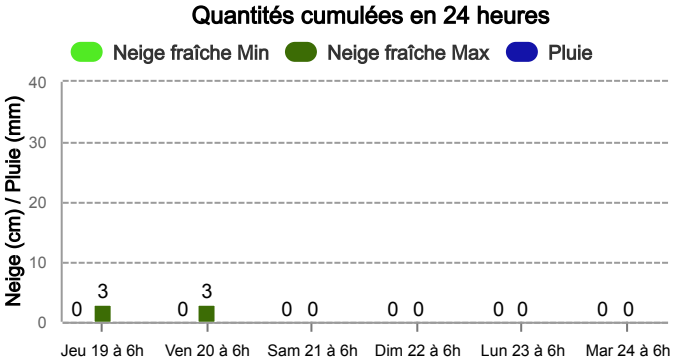

Tendance du mardi 24 février

Indice de risque limité

Stabilisation progressive des plaques, maintien de l'activité en neige humide

Pour consulter la vigilance en cours, veuillez vous rendre sur le site https://vigilance.meteofrance.fr/fr

Météo-France - 73 avenue de Paris, 94165 Saint-Mandé cedex - Contact : contact@meteo.fr

Rédigé par Météo-France avec la contribution des observateurs du réseau nivo-météorologiques. Partenariat : ANMSM (Maires de Stations de Montagne), DSF (Domaines Skiables de France), ADSP (Directeurs de Pistes et de la Sécurité des Stations de Sports d'Hiver) et autres acteurs de la montagne.

Bulletin neige & avalanches par téléphone au

0 892 68 10 20 Service 0,35 € / min + prix appel

RÉPUBLIQUE FRANÇAISE
Liberté Égalité Fraternité

METEO FRANCE
À VOS CÔTÉS, DANS UN CLIMAT QUI CHANGE

Bulletin d'estimation du risque d'avalanche

(valable en dehors des pistes balisées et ouvertes)

MASSIF : Cerdagne Canigou

Rédigé le dimanche 22 février 2026 à 16h

Conditions nivo-météo des 7 derniers jours

	lun. 16/02				mar. 17/02				mer. 18/02				jeu. 19/02				ven. 20/02				sam. 21/02				dim. 22/02			
	03h	09h	15h	21h	03h	09h	15h	21h	03h	09h	15h	21h	03h	09h	15h	21h	03h	09h	15h	21h	03h	09h	15h	21h	03h	09h	15h	21h
Météo																												
Vent (km/h)	95	100	105	120	120	110	90	75	65	55	70	80	80	70	70	75	65	65	55	50	45	35	30	25	20	15	15	15
à 3000m																												
Vent (km/h)	50	65	80	85	85	65	50	40	30	25	35	50	75	60	60	65	60	60	40	30	25	20	20	15	10	10	10	10
à 2000m																												

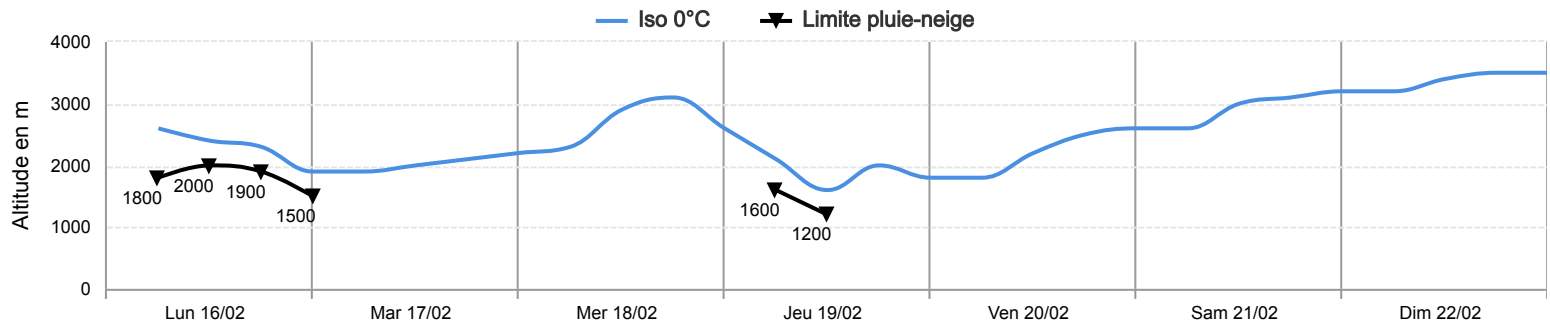

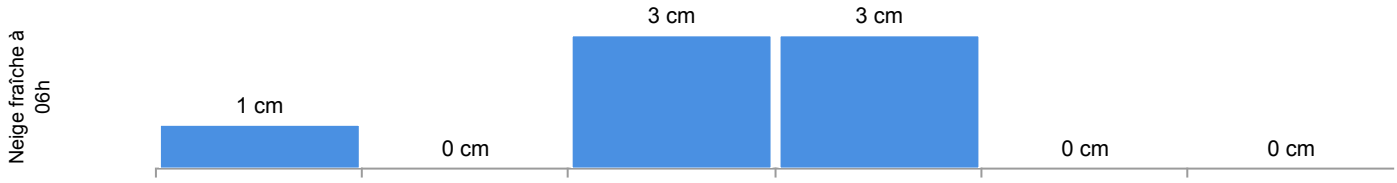

Risque d'avalanche	lun. 16/02	mar. 17/02	mer. 18/02	jeu. 19/02	ven. 20/02	sam. 21/02	dim. 22/02
	3	3	3	3	3	3	2

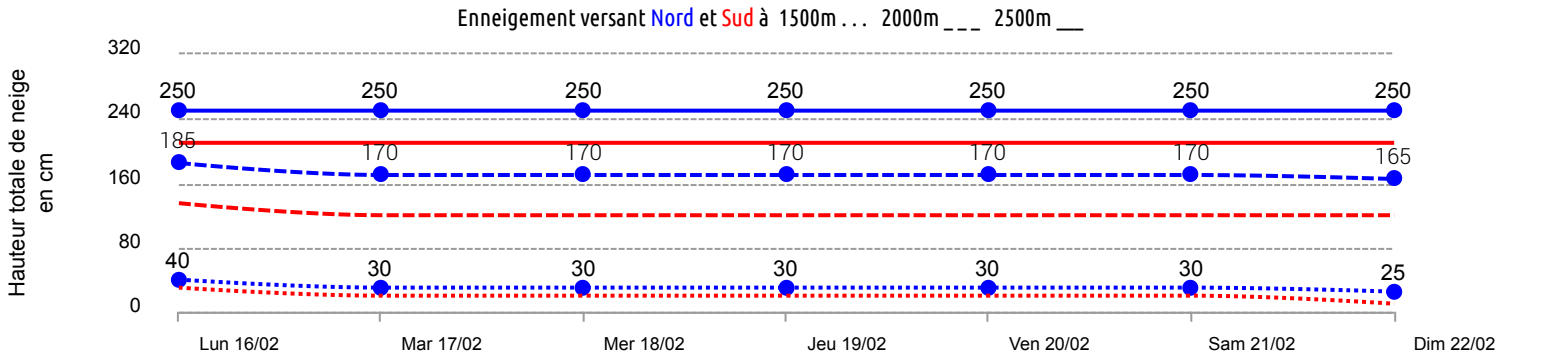

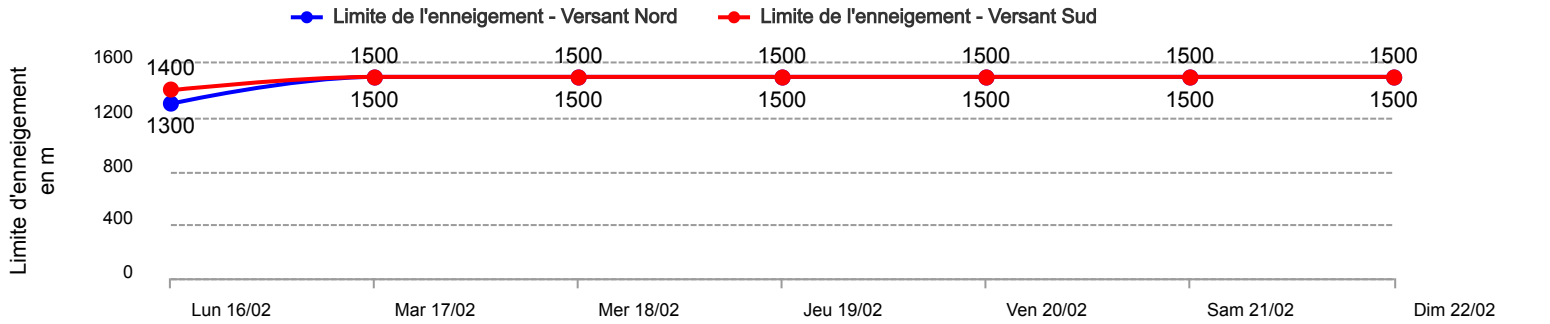

Pour consulter la vigilance en cours, veuillez vous rendre sur le site https://vigilance.meteofrance.fr/fr

Météo-France - 73 avenue de Paris, 94165 Saint-Mandé cedex - Contact : contact@meteo.fr

Bulletin neige & avalanches par téléphone au

0 892 68 10 20 Service 0,35 € / min + prix appel

Rédigé par Météo-France avec la contribution des observateurs du réseau nivo-météorologiques. Partenariat : ANMSM (Maires de Stations de Montagne), DSF (Domaines Skiables de France), ADSP (Directeurs de Pistes et de la Sécurité des Stations de Sports d'Hiver) et autres acteurs de la montagne.