Bulletin d'estimation du risque d'avalanche

(valable en dehors des pistes balisées et ouvertes)

MASSIF : Champsaur

Rédigé le dimanche 22 février 2026 à 16h

Estimation des risques pour le : LUNDI 23 FÉVRIER

MANTEAU NEIGEUX HÉBERGEANT ENCORE DES INSTABILITÉS SOUS FORME DE PLAQUES OU EN NEIGE HUMIDE AU SOLEIL

3

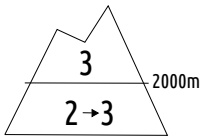

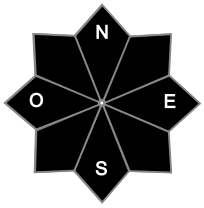

Au-dessus de 2000m indice de risque marqué, plus bas indice limité évoluant en marqué.

Départs spontanés : neige humide au soleil / plaques en altitude.

Déclenchements provoqués : plaques au-dessus de 2000 m environ, avec possibilité de cassure épaisse et large.

Indices de risque : 5 très fort - 4 fort - 3 marqué - 2 limité - 1 faible -- En noir : les pentes les plus dangereuses

Stabilité du manteau neigeux

Situation avalancheuse typique : neige ventée neige humide

Déclenchements provoqués : au-dessus de 2000 m environ, quelques plaques peuvent encore céder au passage d'un seul skieur, entretenues dans certaines parties du massif par le vent de nord-ouest qui se renforce et transporte un peu de neige en altitude. Avalanches petites à moyennes (taille 1 à 2) quand elles ne mobilisent que la neige ventée, mais la probabilité de déclencher **une plaque épaisse et large** (taille 3) reste malheureusement encore d'actualité, en cas de rupture sur la **couche fragile persistante enfouie à la base du manteau neigeux**. Déclenchement de ces plaques volumineuses plus probable sur les bords des pentes près des rochers, à proximité des croupes, là où l'épaisseur de neige est moins importante, mais aussi suite au départ d'une première avalanche de surface.

Départs spontanés : * Dans les pentes raides ensoleillées, l'activité en neige humide est à nouveau en hausse au fil de la journée. Départs essentiellement près des rochers ou des barres. Plutôt superficielles à haute altitude, ces avalanches peuvent finir par mobiliser des volumes de neige plus conséquents sous 2000/2200 m. Avalanches moyennes, voire grandes (taille 2 à 3) si topographie favorable, et pouvant descendre ponctuellement à basse altitude dans les couloirs habituels.
* Quelques départs de plaques suite au transport de neige par le vent, au passage d'une première petite avalanche de surface (boulettes, neige humidifiée), ou à la chute d'une corniche.

Qualité de la neige

L'enneigement est excédentaire pour un mois de février, mais avec la douceur bien installée, les limites d'enneigement en sud remontent progressivement.
Hauteurs de neige observées : 75 cm au hameau des Portes dans le Valgaudemar à 1270 m, 175 cm à la Nivôse d'Orcières à 2280 m, et 200 cm au-dessus de Prapic à 2480 m.

Limite d'enneigement skiable : la plupart des itinéraires sont skiables dès les fonds de vallées en ubacs, plutôt 1400 m en adrets.

État de la neige de surface : manteau neigeux souvent bien travaillé par le vent qui a cartonné ou durci de nombreuses pentes d'altitude. Enneigement hétérogène près des hautes crêtes avec d'importantes accumulations et corniches qui côtoient des secteurs décapés par le vent.
La neige de surface reste froide et plus légère dans les ubacs d'altitude abrités du vent. Elle est en cycle printanier dans les adrets jusqu'à haute altitude, ou dans les ubacs sous 1800/2000 m (croûtée le matin, puis humidification en journée).

Aperçu météo pour le lundi 23 février

nuit	matin	après-midi	soir

Quelques passages nuageux le matin, plus ensoleillé l'après-midi. Vent de nord-ouest sensible sur les sommets.

Pluie-Neige				
Iso 0 °C	3 000 m	2 900 m	2 900 m	3 200 m
Vent 2000 m	↘ 15 km/h	↓ 20 km/h	↘ 15 km/h	↓ 10 km/h
Vent 3000 m	↘ 30 km/h	↘ 40 km/h	↘ 40 km/h	↘ 40 km/h

Épaisseur de neige hors-piste

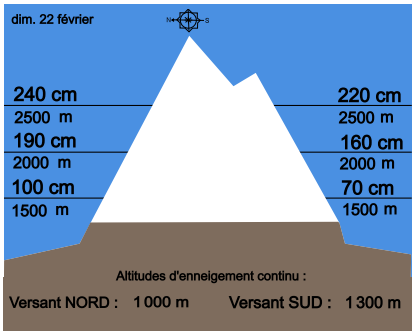

Précipitations à 1800 m

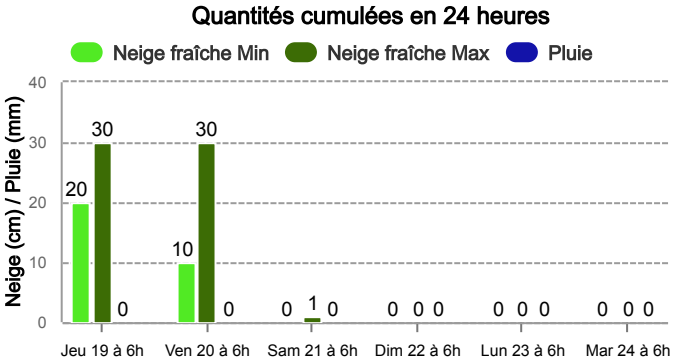

Tendance du mardi 24 février

3 **Indice de risque marqué**

Encore quelques plaques en altitude. Hausse de l'activité en neige humide au soleil et gagnant des altitudes plus élevées, avec la douceur encore plus marquée. Départ volumineux possible.
Maintien probable d'un risque marqué.

Pour consulter la vigilance en cours, veuillez vous rendre sur le site https://vigilance.meteofrance.fr/fr

Météo-France - 73 avenue de Paris, 94165 Saint-Mandé cedex - Contact : contact@meteo.fr

Rédigé par Météo-France avec la contribution des observateurs du réseau nivo-météorologiques. Partenariat : ANMSM (Maires de Stations de Montagne), DSF (Domaines Skiables de France), ADSP (Directeurs de Pistes et de la Sécurité des Stations de Sports d'Hiver) et autres acteurs de la montagne.

Bulletin neige & avalanches par téléphone au
0 892 68 10 20 Service 0,35 € / min + prix appel

Bulletin d'estimation du risque d'avalanche

(valable en dehors des pistes balisées et ouvertes)

MASSIF : Champsaur

Rédigé le dimanche 22 février 2026 à 16h

Conditions nivo-météo des 7 derniers jours

	lun. 16/02				mar. 17/02				mer. 18/02				jeu. 19/02				ven. 20/02				sam. 21/02				dim. 22/02			
	03h	09h	15h	21h	03h	09h	15h	21h	03h	09h	15h	21h	03h	09h	15h	21h	03h	09h	15h	21h	03h	09h	15h	21h	03h	09h	15h	21h
Météo																												
Vent (km/h)	80	100	130	120	105	95	80	75	45	30	25	50	45	50	65	60	75	70	70	60	60	60	60	55	45	30	30	35
à 3000m																												
Vent (km/h)	30	65	80	70	70	50	45	25	20	15	15	25	45	45	45	50	55	45	40	40	35	45	40	30	15	10	15	15
à 2000m																												

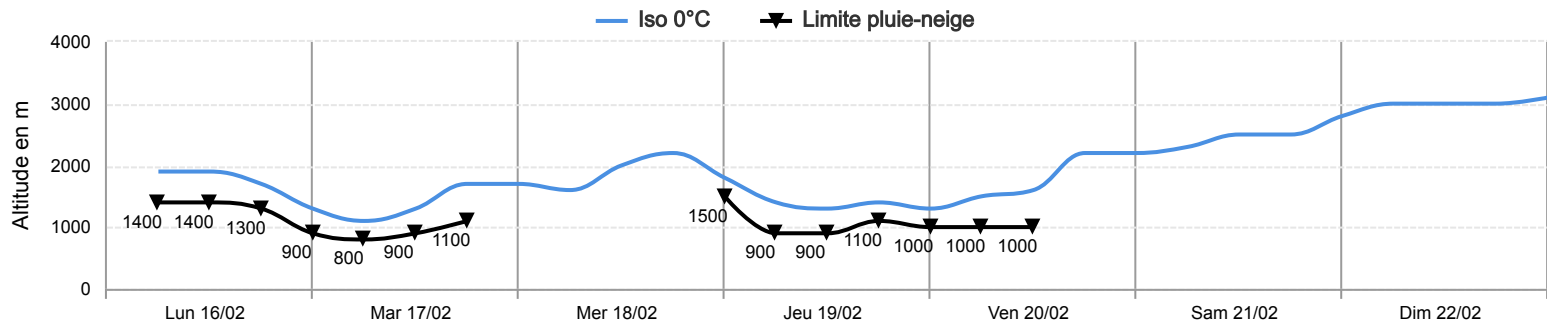

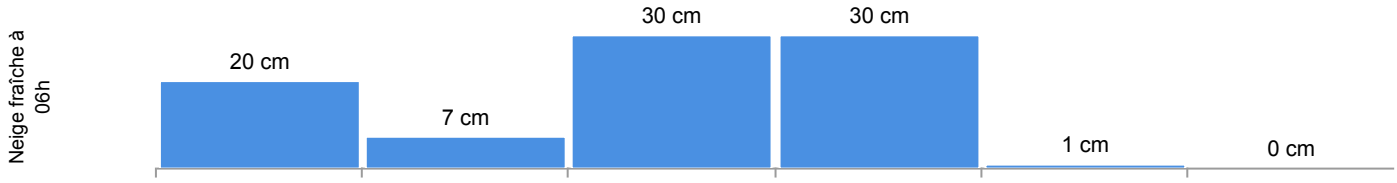

Risque d'avalanche	lun. 16/02	mar. 17/02	mer. 18/02	jeu. 19/02	ven. 20/02	sam. 21/02	dim. 22/02
	4	4	4	4	4	4	3

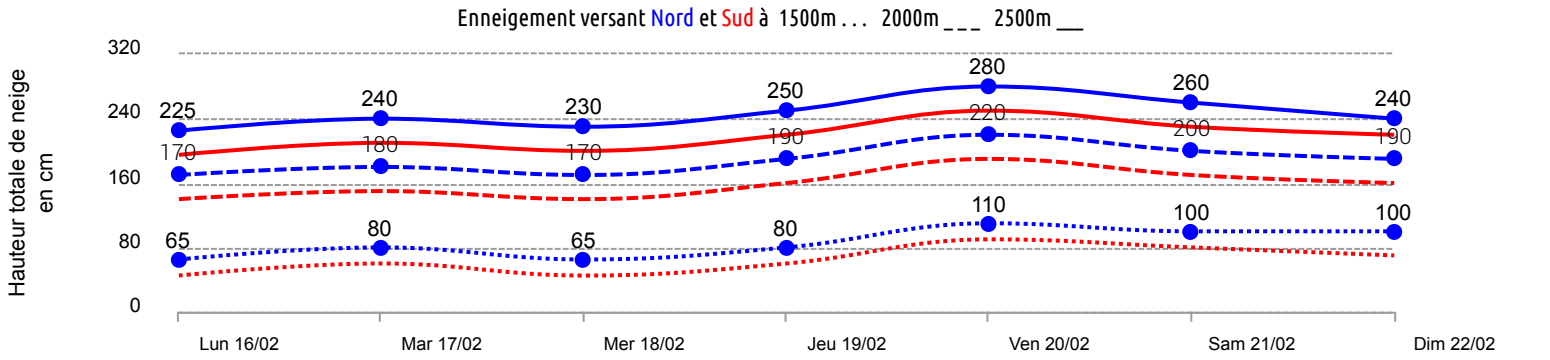

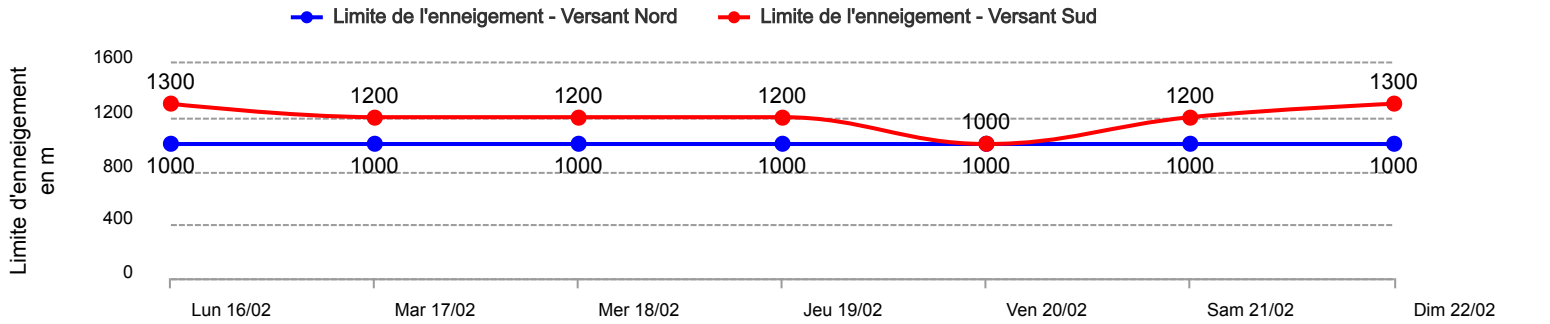

Pour consulter la vigilance en cours, veuillez vous rendre sur le site https://vigilance.meteofrance.fr/fr

Météo-France - 73 avenue de Paris, 94165 Saint-Mandé cedex - Contact : contact@meteo.fr

Rédigé par Météo-France avec la contribution des observateurs du réseau nivo-météorologiques. Partenariat : ANMSM (Maires de Stations de Montagne), DSF (Domaines Skiables de France), ADSP (Directeurs de Pistes et de la Sécurité des Stations de Sports d'Hiver) et autres acteurs de la montagne.

Bulletin neige & avalanches par téléphone au

0 892 68 10 20 Service 0,35 € / min + prix appel