Bulletin d'estimation du risque d'avalanche

(valable en dehors des pistes balisées et ouvertes)

MASSIF : Cinto Rotondo

Rédigé le dimanche 22 février 2026 à 16h

Estimation des risques pour le : LUNDI 23 FÉVRIER

INSTABILITÉS DANS LA NEIGE VENTÉE EN ALTITUDE

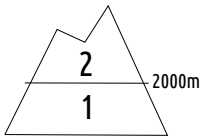

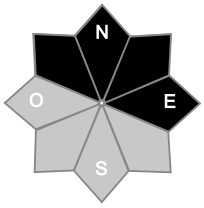

Au-dessus de 2000m indice de risque limité, plus bas indice faible.

Départs spontanés : coulées et avalanches de neige récente humidifiée au soleil

Déclenchements provoqués : plaques en alttiude

Indices de risque : 5 très fort - 4 fort - 3 marqué - 2 limité - 1 faible -- En noir : les pentes les plus dangereuses

Stabilité du manteau neigeux

Situation avalancheuse typique : neige ventée neige humide

Déclenchements provoqués : des structures de plaques sont présentes, surtout dans les pentes orientées Nord à Est. Ces plaques peuvent surtout être déclenchées par forte surcharge, plus rarement par le simple passage d'un skieur ou randonneur. Elles sont plus épaisses et plus dures en altitude, réparties de façon plus hétérogène, avec des accumulations localement épaisses. Ces plaques reposent sur des couches fragiles temporaires (neige récente moins dense ou neige roulée).

Départs spontanés : des coulées ou petites avalanches sont possibles par humidification du manteau neigeux superficiel, à plus forte raison dans les pentes raides ensoleillées.

Autres : risque de glissade en neige dure ou glacée aux abords des crêtes et sommets balayés par les vents.

Qualité de la neige

Qualification de l'enneigement : L'enneigement est excellent pour la saison à toutes altitudes. On relève près de 3 mètres dans les combes abritées.

Limite d'enneigement skiable : 1300 à 1500 m selon le versant.

État de la neige : On trouve en surface une couche de neige fraîche, 10 à 30 cm mais le fort vent d'Ouest à Nord a rendu l'enneigement très hétérogène : les orientations Nord et Est sont souvent plus garnies que les pentes Ouest rapidement pelées ou verglacées dès que l'on se rapproche des crêtes et sommets. La neige est froide et poudreuse à l'abri du vent dès 1800 à 2000 m d'altitude, elle devient plus compacte, voire cartonnée dans les secteurs ventés. On trouve localement des accumulations de neige roulée. Corniches et accumulations parfois volumineuses sont en place.

Aperçu météo pour le lundi 23 février

	nuit	matin	après-midi	soir
Temps sec et ensoleillé				
Pluie-Neige				
Iso 0 °C	3 400 m	3 400 m	3 400 m	3 400 m
Vent 1500 m	→ 40 km/h	→ 40 km/h	→ 35 km/h	→ 20 km/h
Vent 3000 m	→ 60 km/h	→ 60 km/h	→ 50 km/h	→ 30 km/h

Épaisseur de neige hors-piste

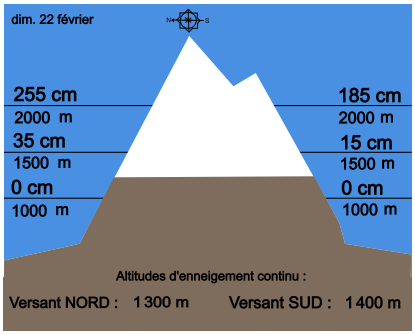

Précipitations à 1800 m

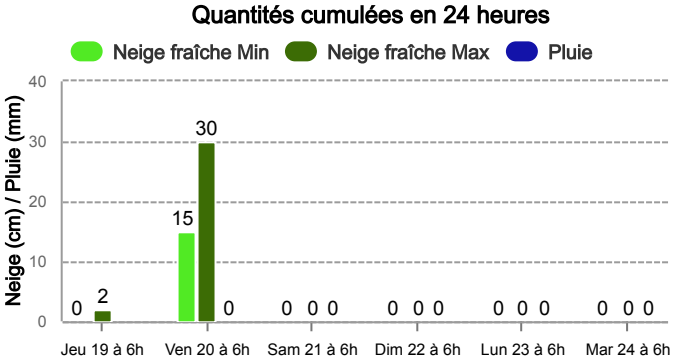

Tendance du mardi 24 février

Indice de risque limité

Poursuite d'un temps sec et ensoleillé.
Tendance du risque stationnaire ou en légère baisse.

Pour consulter la vigilance en cours, veuillez vous rendre sur le site https://vigilance.meteofrance.fr/fr

Météo-France - 73 avenue de Paris, 94165 Saint-Mandé cedex - Contact : contact@meteo.fr

Rédigé par Météo-France avec la contribution des observateurs du réseau nivo-météorologiques. Partenariat : ANMSM (Maires de Stations de Montagne), DSF (Domaines Skiables de France), ADSP (Directeurs de Pistes et de la Sécurité des Stations de Sports d'Hiver) et autres acteurs de la montagne.

Bulletin neige & avalanches par téléphone au **0 892 68 10 20** Service 0,35 € / min + prix appel

RÉPUBLIQUE FRANÇAISE
Liberté Égalité Fraternité

METEO FRANCE
À VOS CÔTÉS, DANS UN CLIMAT QUI CHANGE

Bulletin d'estimation du risque d'avalanche

(valable en dehors des pistes balisées et ouvertes)

MASSIF : Cinto Rotondo

Rédigé le dimanche 22 février 2026 à 16h

Conditions nivo-météo des 7 derniers jours

	lun. 16/02				mar. 17/02				mer. 18/02				jeu. 19/02				ven. 20/02				sam. 21/02				dim. 22/02			
	03h	09h	15h	21h	03h	09h	15h	21h	03h	09h	15h	21h	03h	09h	15h	21h	03h	09h	15h	21h	03h	09h	15h	21h	03h	09h	15h	21h
Météo																												
Vent (km/h)	80	90	120	130	100	80	70	60	60	65	55	50	75	80	95	100	80	60	60	40	40	40	30	20	20	20	45	50
à 3000m																												
Vent (km/h)	70	70	90	90	80	50	50	40	45	50	40	40	55	70	85	75	60	40	30	20	15	20	15	10	10	10	35	40
à 1500m																												

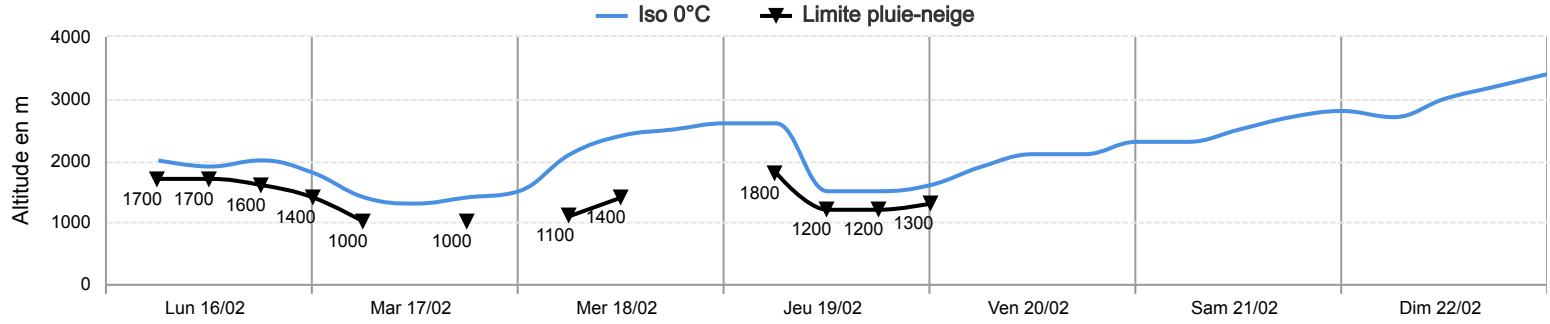

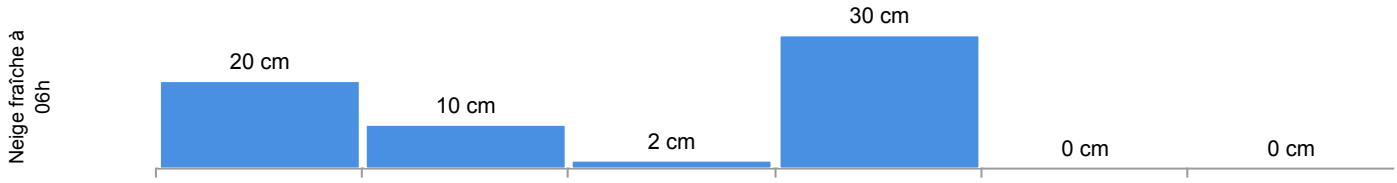

Risque d'avalanche	lun. 16/02	mar. 17/02	mer. 18/02	jeu. 19/02	ven. 20/02	sam. 21/02	dim. 22/02
	3	3	3	4	3	3	2

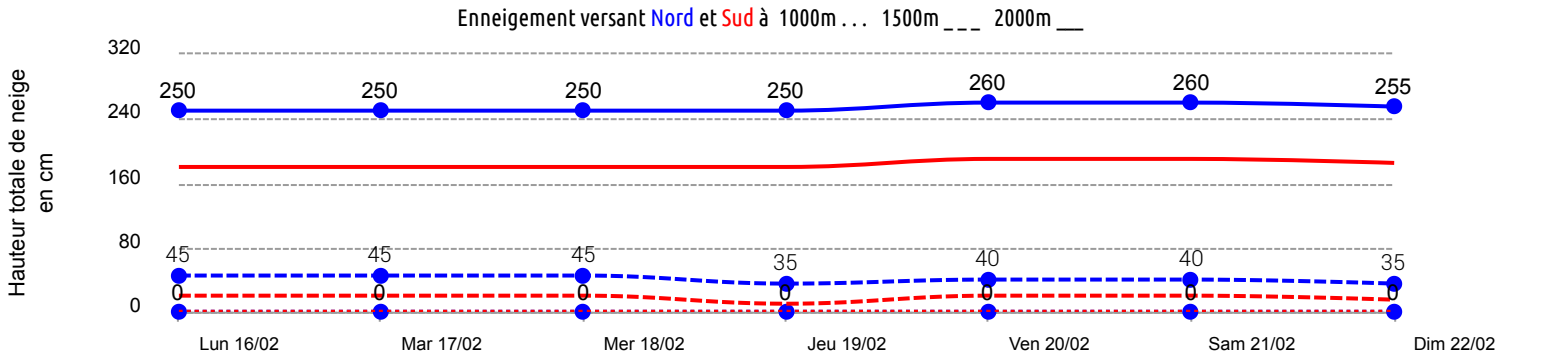

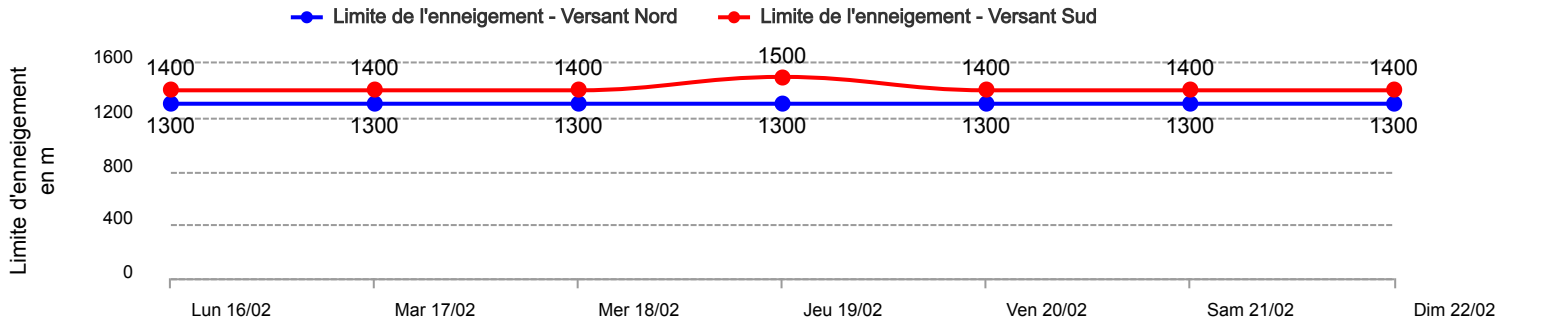

Pour consulter la vigilance en cours, veuillez vous rendre sur le site https://vigilance.meteofrance.fr/fr

Météo-France - 73 avenue de Paris, 94165 Saint-Mandé cedex - Contact : contact@meteo.fr

Rédigé par Météo-France avec la contribution des observateurs du réseau nivo-météorologiques. Partenariat : ANMSM (Maires de Stations de Montagne), DSF (Domaines Skiables de France), ADSP (Directeurs de Pistes et de la Sécurité des Stations de Sports d'Hiver) et autres acteurs de la montagne.

Bulletin neige & avalanches par téléphone au

0 892 68 10 20 Service 0,35 € / min + prix appel