Bulletin d'estimation du risque d'avalanche

(valable en dehors des pistes balisées et ouvertes)

MASSIF : Devoluy

Rédigé le dimanche 22 février 2026 à 16h

Estimation des risques pour le : LUNDI 23 FÉVRIER

MANTEAU NEIGEUX HÉBERGEANT ENCORE DES INSTABILITÉS SOUS FORME DE PLAQUES OU EN NEIGE HUMIDE AU SOLEIL

3

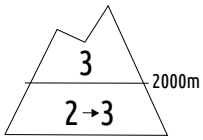

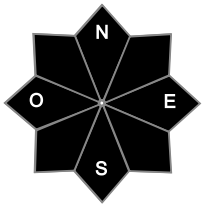

Au-dessus de 2000m indice de risque marqué, plus bas indice limité évoluant en marqué.

Départs spontanés : neige humide au soleil / plaques en altitude avec le transport par le vent.

Déclenchements provoqués : plaques au-dessus de 2000 m environ - Cassure épaisse et large non exclue.

Indices de risque : 5 très fort - 4 fort - 3 marqué - 2 limité - 1 faible -- En noir : les pentes les plus dangereuses

Stabilité du manteau neigeux

Situation avalancheuse typique : neige ventée neige humide

Déclenchements provoqués : au-dessus de 2000 m environ, des plaques sont encore sensibles au passage d'un seul skieur. Elles sont entretenues par le vent de nord à nord-ouest qui se renforce à nouveau en journée de lundi et favorise du transport de neige en altitude. Avalanches petites à moyennes en général (taille 1 à 2). Ponctuellement, une plaque épaisse et large (taille 3) reste possible en ubacs d'altitude, en cas de rupture sur la couche fragile persistante présente à la base du manteau neigeux. Déclenchement difficile en général, mais possible en passant sur les bords des pentes près des rochers, à proximité des croupes, là où l'épaisseur de neige est moins importante, mais aussi suite au départ d'une première avalanche de surface.

Départs spontanés : * Dans les pentes raides ensoleillées, l'activité en neige humide est à nouveau en hausse au fil de la journée. Départs essentiellement près des rochers ou des barres. Plutôt superficielles à haute altitude, ces avalanches peuvent finir par mobiliser des volumes de neige plus conséquents sous 2000/2200 m. Avalanches moyennes, voire grandes (taille 2 à 3) si topographie favorable, et pouvant descendre ponctuellement à basse altitude dans les couloirs habituels.
* Quelques départs de plaques suite au transport de neige par le vent, au passage d'une première petite avalanche de surface (boulettes, neige humidifiée), ou à la chute d'une corniche.

Qualité de la neige

LL'enneigement est excédentaire pour un mois de février, mais avec la douceur bien installée, les limites d'enneigement en sud remontent progressivement.

Limite d'enneigement skiable : vers 1200 m sur la plupart des itinéraires en ubacs, 1300/1400 m en adrets.

État de la neige de surface : manteau neigeux souvent bien travaillé par le vent qui a cartonné ou durci de nombreuses pentes d'altitude. Enneigement hétérogène près des hautes crêtes avec d'importantes accumulations et corniches qui côtoient des secteurs décapés par le vent.
La neige de surface reste froide et plus légère dans les ubacs d'altitude abrités du vent. Elle est en cycle printanier dans les adrets jusqu'à haute altitude, ou dans les ubacs sous 1800/2000 m (croûtée le matin, puis humidification en journée).

Aperçu météo pour le lundi 23 février

nuit	matin	après-midi	soir

Quelques passages nuageux d'altitude le matin, nuages bas de plus en plus nombreux l'après-midi.
Vent de nord à nord-ouest à nouveau assez fort en altitude.

Pluie-Neige				
Iso 0 °C	3 000 m	2 900 m	2 800 m	3 100 m
Vent 2000 m	↓ 20 km/h	↓ 40 km/h	↓ 40 km/h	↓ 30 km/h
Vent 3000 m	↘ 45 km/h	↘ 50 km/h	↘ 60 km/h	↓ 60 km/h

Épaisseur de neige hors-piste

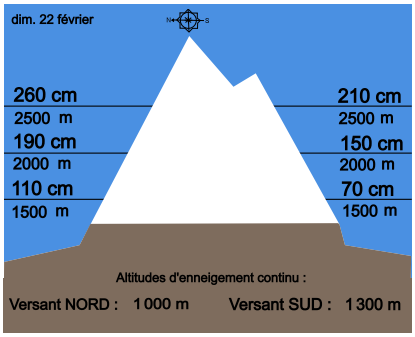

Précipitations à 1800 m

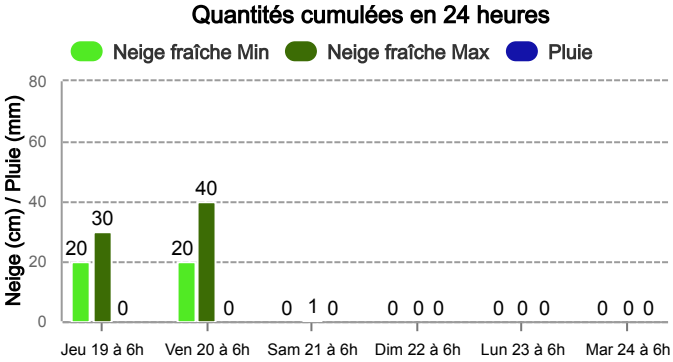

Tendance du mardi 24 février

3

Indice de risque marqué

Encore quelques plaques en altitude. Hausse de l'activité en neige humide au soleil et gagnant des altitudes plus élevées, avec la douceur encore plus marquée. Départ volumineux possible.
Maintien probable d'un risque marqué.

Pour consulter la vigilance en cours, veuillez vous rendre sur le site https://vigilance.meteofrance.fr/fr

Météo-France - 73 avenue de Paris, 94165 Saint-Mandé cedex - Contact : contact@meteo.fr

Rédigé par Météo-France avec la contribution des observateurs du réseau nivo-météorologiques. Partenariat : ANMSM (Maires de Stations de Montagne), DSF (Domaines Skiables de France), ADSP (Directeurs de Pistes et de la Sécurité des Stations de Sports d'Hiver) et autres acteurs de la montagne.

Bulletin neige & avalanches par téléphone au
0 892 68 10 20 Service 0,35 € / min + prix appel

RÉPUBLIQUE FRANÇAISE
Liberté Égalité Fraternité

METEO FRANCE
À VOS CÔTÉS, DANS UN CLIMAT QUI CHANGE

Bulletin d'estimation du risque d'avalanche

(valable en dehors des pistes balisées et ouvertes)

MASSIF : Devoluy

Rédigé le dimanche 22 février 2026 à 16h

Conditions nivo-météo des 7 derniers jours

	lun. 16/02				mar. 17/02				mer. 18/02				jeu. 19/02				ven. 20/02				sam. 21/02				dim. 22/02			
	03h	09h	15h	21h	03h	09h	15h	21h	03h	09h	15h	21h	03h	09h	15h	21h	03h	09h	15h	21h	03h	09h	15h	21h	03h	09h	15h	21h
Météo																												
Vent (km/h)	60	80	120	110	90	80	75	70	50	35	40	65	50	55	70	75	80	90	80	80	80	80	80	60	40	35	35	40
à 3000m	↘	↘	↘	↘	↘	↘	↘	↘	↘	↘	→	↑	↗	↘	↘	↓	↘	↓	↓	↓	↓	↓	↓	↓	↓	↘	↘	↘
Vent (km/h)	30	55	70	70	70	60	55	50	40	20	20	45	45	30	40	55	75	60	60	60	45	60	60	40	25	15	15	15
à 2000m	↘	↘	↘	↘	↘	↓	↓	↘	↓	↘	↑	↑	↑	↘	↘	↓	↘	↓	↓	↓	↓	↓	↓	↓	↓	↓	→	↓

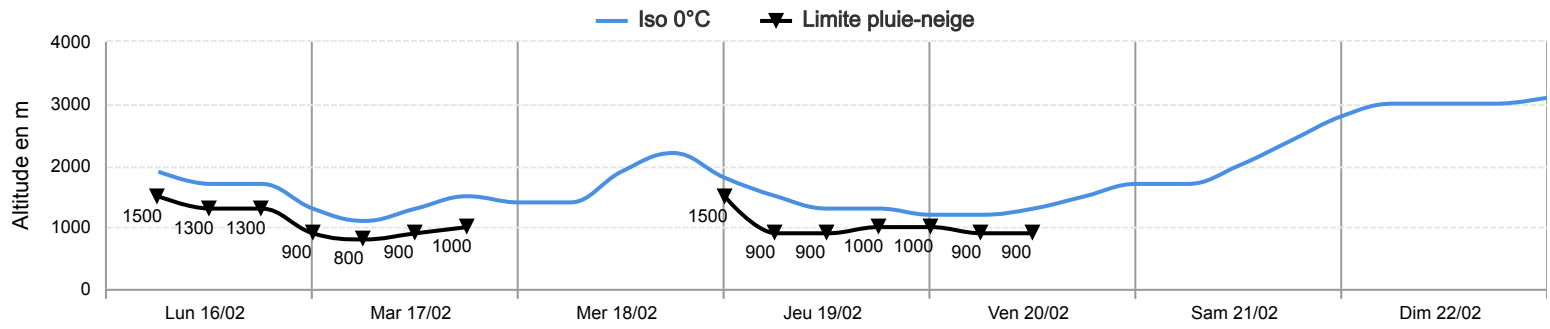

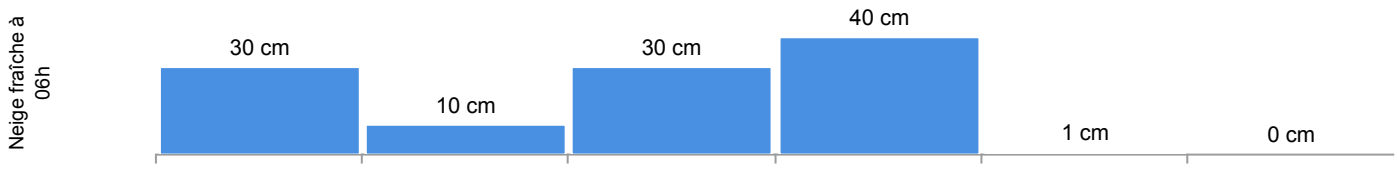

Risque d'avalanche	lun. 16/02	mar. 17/02	mer. 18/02	jeu. 19/02	ven. 20/02	sam. 21/02	dim. 22/02
	3	4	4	4	4	4	3

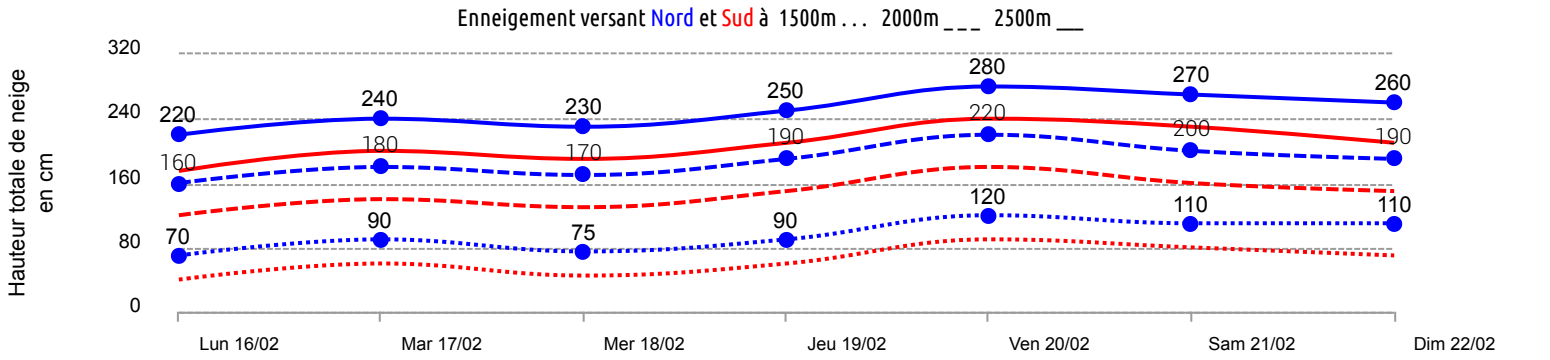

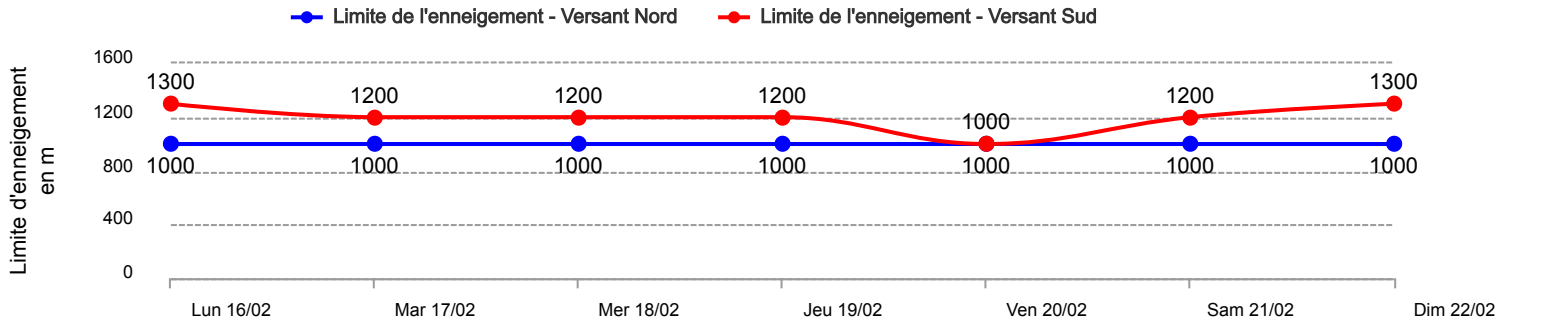

Pour consulter la vigilance en cours, veuillez vous rendre sur le site https://vigilance.meteofrance.fr/fr

Météo-France - 73 avenue de Paris, 94165 Saint-Mandé cedex - Contact : contact@meteo.fr

Rédigé par Météo-France avec la contribution des observateurs du réseau nivo-météorologiques. Partenariat : ANMSM (Maires de Stations de Montagne), DSF (Domaines Skiables de France), ADSP (Directeurs de Pistes et de la Sécurité des Stations de Sports d'Hiver) et autres acteurs de la montagne.

Bulletin neige & avalanches par téléphone au

0 892 68 10 20 Service 0,35 € / min + prix appel