Bulletin d'estimation du risque d'avalanche
(valable en dehors des pistes balisées et ouvertes)

MASSIF : Mercantour

Rédigé le dimanche 22 février 2026 à 16h

Estimation des risques pour le : LUNDI 23 FÉVRIER

QUELQUES PLAQUES DANS LA NEIGE RÉCENTE VENTÉE, DÉPARTS NATURELS EN NEIGE HUMIDE

3

2 → 3

N O E S

Indice de risque limité évoluant en marqué.

Départs spontanés : départs de neige humide devenant nombreux au soleil au fil de la journée

Déclenchements provoqués : quelques petites instabilités dans la neige récente ventée en altitude.

Indices de risque : 5 très fort - 4 fort - 3 marqué - 2 limité - 1 faible -- En noir : les pentes les plus dangereuses

Stabilité du manteau neigeux

Situation avalancheuse typique : neige humide — neige ventée

Départs spontanés :
- départs ponctuels par humidification du manteau neigeux : peu probables en début de journée, puis devenant fréquents en cours de journée, en pentes raides ensoleillées à toutes altitudes, notamment près des rochers. Avalanches de taille petite à moyenne (taille 1 à 2), rarement grande (taille 3), notamment en dessous de 2400/2600 m où le manteau est humidifié en profondeur.

- Rares avalanches possibles à la suite d'une rupture de corniches ou de reptations en cours d'ouverture. Taille moyenne à grande (taille 2 à 3).

Déclenchements provoqués :
- quelques instabilités dans la neige récente ventée, principalement en versants nord-ouest à sud-est au-dessus de 2000 m. Plaques d'aspect variable : en neige durcie par le vent proche des crêtes, parfois friables dans les zones plus abritées, voir même en neige humide en surface en versants ensoleillés d'altitude. Localement encore facile à déclencher au passage d'un skieur, elles engendrent des avalanches de taille petite à moyenne (taille 1 à 2).

- des départs sous les skis de neige fortement humidifiée sont possibles en versant raides ensoleillés en cours de journée. Avalanches de taille petite à moyenne (taille 1 à 2)

Qualité de la neige

Enneigement très excédentaire pour un mois de février.
Données observées : 151 cm à la nivôse de Millefonts à 2430 m.

Enneigement skiable dès 1300/1400 m en ubacs en terrains favorables et 1600/1800 m en adrets

État de la neige en surface : neige croutée le matin avec un regel moyen, s'humidifiant rapidement en journée au fil de l'ensoleillement. On retrouve de la neige encore poudreuse en Ubacs au-dessus de 1900/2100 m environ, souvent travaillée/durcie par le vent de nord. Zones dégarnies proches des crêtes, alternant avec des corniches parfois épaisses.

Aperçu météo pour le lundi 23 février

	nuit	matin	après-midi	soir
Temps sec et doux, soleil voilé.				
Pluie-Neige				
Iso 0 °C	3 300 m	3 000 m	3 100 m	3 400 m
Vent 2000 m	25 km/h	20 km/h	15 km/h	15 km/h
Vent 3000 m	50 km/h	45 km/h	25 km/h	20 km/h

Épaisseur de neige hors-piste

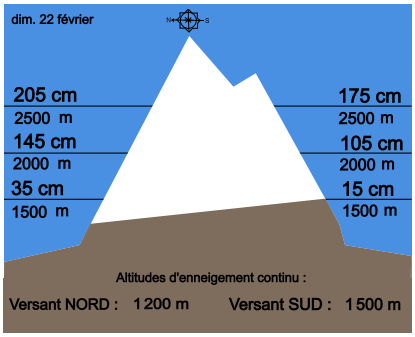

Précipitations à 1800 m

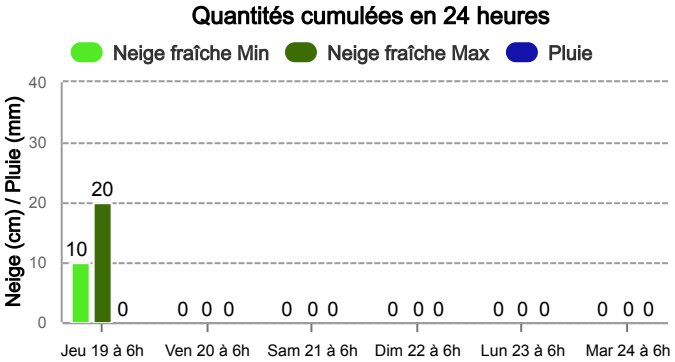

Tendance du mardi 24 février

3

Indice de risque marqué

Maintien d'un risque marqué en journée avec la poursuite de l'humidification de manteau neigeux dans les versants ensoleillé. Départs spontanés localement volumineux.

Pour consulter la vigilance en cours, veuillez vous rendre sur le site https://vigilance.meteofrance.fr/fr

Météo-France - 73 avenue de Paris, 94165 Saint-Mandé cedex - Contact : contact@meteo.fr

Rédigé par Météo-France avec la contribution des observateurs du réseau nivo-météorologiques. Partenariat : ANMSM (Maires de Stations de Montagne), DSF (Domaines Skiables de France), ADSP (Directeurs de Pistes et de la Sécurité des Stations de Sports d'Hiver) et autres acteurs de la montagne.

Bulletin neige & avalanches par téléphone au 0 892 68 10 20 Service 0,35 € / min + prix appel

RÉPUBLIQUE FRANÇAISE
Liberté Égalité Fraternité

METEO FRANCE
À VOS CÔTÉS, DANS UN CLIMAT QUI CHANGE

Bulletin d'estimation du risque d'avalanche

(valable en dehors des pistes balisées et ouvertes)

MASSIF : Mercantour

Rédigé le dimanche 22 février 2026 à 16h

Conditions nivo-météo des 7 derniers jours

	lun. 16/02				mar. 17/02				mer. 18/02				jeu. 19/02				ven. 20/02				sam. 21/02				dim. 22/02			
	03h	09h	15h	21h	03h	09h	15h	21h	03h	09h	15h	21h	03h	09h	15h	21h	03h	09h	15h	21h	03h	09h	15h	21h	03h	09h	15h	21h
Météo																												
Vent (km/h)	55	75	100	80	75	70	50	40	35	25	35	75	55	55	80	80	75	60	50	30	45	50	40	30	30	35	45	50
à 3000m																												
Vent (km/h)	30	40	65	40	60	50	20	20	15	15	20	40	30	35	35	45	45	40	15	15	15	20	15	20	15	15	20	15
à 2000m																												

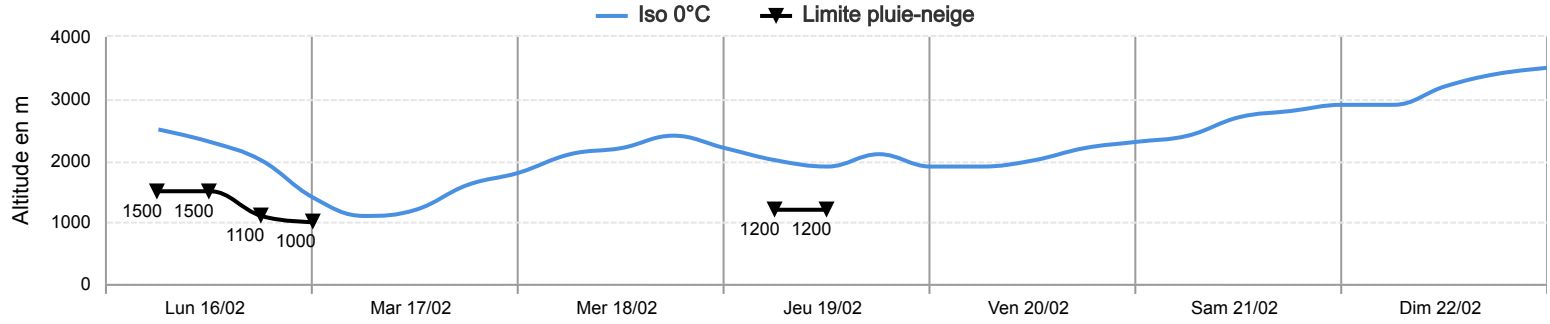

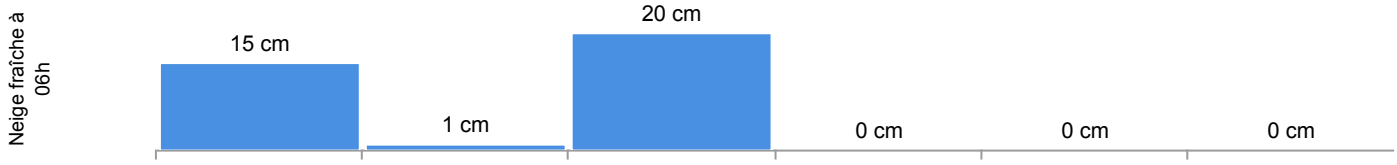

Risque d'avalanche	lun. 16/02	mar. 17/02	mer. 18/02	jeu. 19/02	ven. 20/02	sam. 21/02	dim. 22/02
	3	3	3	3	3	3	3

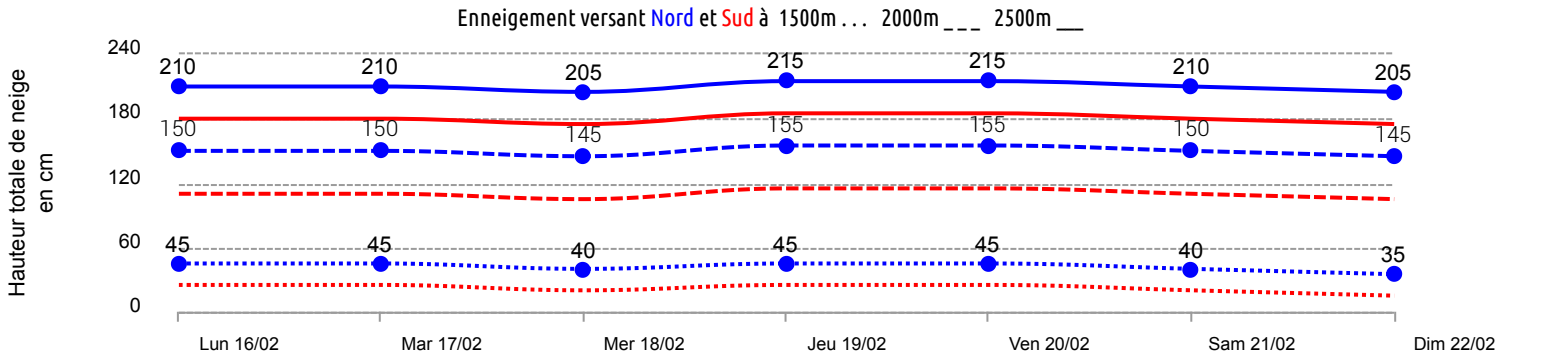

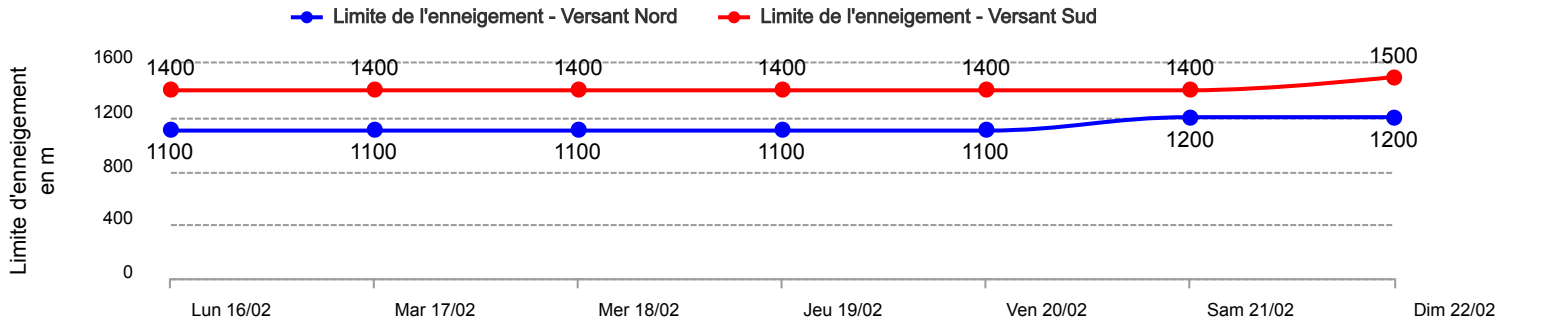

Pour consulter la vigilance en cours, veuillez vous rendre sur le site https://vigilance.meteofrance.fr/fr

Météo-France - 73 avenue de Paris, 94165 Saint-Mandé cedex - Contact : contact@meteo.fr

Rédigé par Météo-France avec la contribution des observateurs du réseau nivo-météorologiques. Partenariat : ANMSM (Maires de Stations de Montagne), DSF (Domaines Skiables de France), ADSP (Directeurs de Pistes et de la Sécurité des Stations de Sports d'Hiver) et autres acteurs de la montagne.

Bulletin neige & avalanches par téléphone au

0 892 68 10 20 Service 0,35 € / min + prix appel