Bulletin d'estimation du risque d'avalanche
(valable en dehors des pistes balisées et ouvertes)

MASSIF : Mont-Blanc

Rédigé le dimanche 22 février 2026 à 16h

Estimation des risques pour le : LUNDI 23 FÉVRIER

ENCORE DES INSTABILITÉS EN ALTITUDE.

3

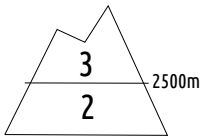

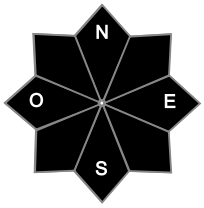

Au-dessus de 2500m indice de risque marqué, plus bas indice limité.

Départs spontanés : Plaques de fond.

Déclenchements provoqués : plaques à vent en altitude

Indices de risque : 5 très fort - 4 fort - 3 marqué - 2 limité - 1 faible -- En noir : les pentes les plus dangereuses

Stabilité du manteau neigeux

Situation avalancheuse typique : neige ventée avalanches de fond

Déclenchements provoqués :

* Au-dessus de 2400/2500 m : **plaques à vent dans la neige restée froide**. Formés par le vent d'un large secteur Sud-Ouest à Nord. **Plus nombreuses en altitude** et dans les **ubacs**. Taille 1 à 2 (petite à moyenne)

Facteur aggravant :

- en versants Est/Nord/Ouest : une couche fragile persistante enfouie peut être sollicitée en cascade et donner de grandes, voire très grandes avalanches.

Observables : accumulations, vaguelettes...

Départs spontanés :

* En dessous de 2200 m : **plaques de fond**. **Tous versants**, mais départs plus nombreux dans les pentes sud. Départs dans les pentes raides et lisses (pentes herbeuses, dalles rocheuses). Taille 2 (moyenne) à 3 (grande).

*** Chutes de corniches**, épaisses et volumineuses, **pouvant solliciter de très larges plaques friables.**

Qualité de la neige

Enneigement : Bon pour la saison à toutes altitudes grâce aux fréquentes chutes de neige du mois de février. On peut chausser les skis vers 1200 m dans tous les versants. L'épaisseur du manteau neigeux varie : nombreuses congères et corniches.

Qualité de la neige lundi :

- En dessous de 2200/2400 m : finement crouté le matin qui s'humidifie en journée.
- Entre 2200/2400 m et 2500/2700 m :
- en adrets : finement crouté
- en ubacs : neige récente dense plus ou moins ventée.
- au-dessus de 2500/2700 m : neige récente encore légère. Plus ou moins ventée en fonction de l'exposition au vent de W/SW.

Aperçu météo pour le lundi 23 février

nuit	matin	après-midi	soir

Nuageux toute la journée. Températures très douces : de -1 à 5°C à 2000 m .

Pluie-Neige				
Iso 0 °C	2 800 m	2 400 m	2 600 m	2 600 m
Vent 2000 m	↗ 25 km/h	↗ 25 km/h	↗ 25 km/h	↓ 20 km/h
Vent 4000 m	↘ 60 km/h	↘ 60 km/h	↘ 60 km/h	↘ 60 km/h

Épaisseur de neige hors-piste

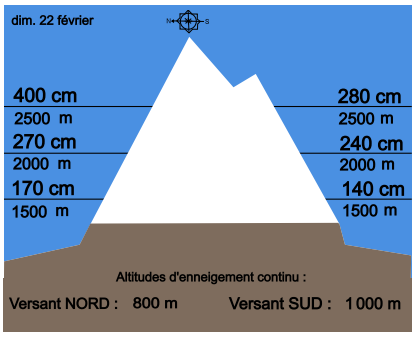

Précipitations à 1800 m

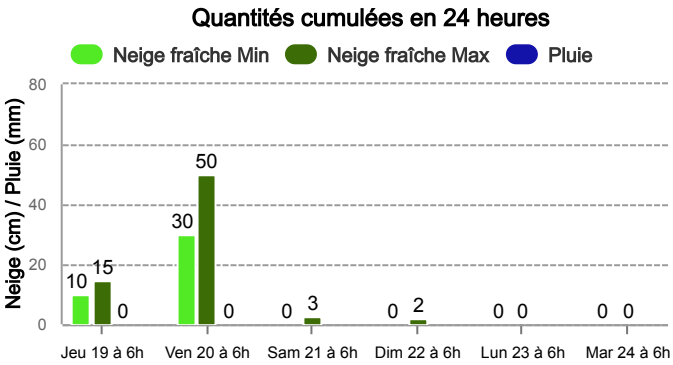

Tendance du mardi 24 février

3

Indice de risque marqué

Risque stationnaire. Ensoleillé et températures en hausse.

Pour consulter la vigilance en cours, veuillez vous rendre sur le site https://vigilance.meteofrance.fr/fr

Météo-France - 73 avenue de Paris, 94165 Saint-Mandé cedex - Contact : contact@meteo.fr

Rédigé par Météo-France avec la contribution des observateurs du réseau nivo-météorologiques. Partenariat : ANMSM (Maires de Stations de Montagne), DSF (Domaines Skiables de France), ADSP (Directeurs de Pistes et de la Sécurité des Stations de Sports d'Hiver) et autres acteurs de la montagne.

Bulletin neige & avalanches par téléphone au

0 892 68 10 20 Service 0,35 € / min + prix appel

RÉPUBLIQUE FRANÇAISE
Liberté Égalité Fraternité

METEO FRANCE
À VOS CÔTÉS, DANS UN CLIMAT QUI CHANGE

Bulletin d'estimation du risque d'avalanche

(valable en dehors des pistes balisées et ouvertes)

MASSIF : Mont-Blanc

Rédigé le dimanche 22 février 2026 à 16h

Conditions nivo-météo des 7 derniers jours

	lun. 16/02				mar. 17/02				mer. 18/02				jeu. 19/02				ven. 20/02				sam. 21/02				dim. 22/02			
	03h	09h	15h	21h	03h	09h	15h	21h	03h	09h	15h	21h	03h	09h	15h	21h	03h	09h	15h	21h	03h	09h	15h	21h	03h	09h	15h	21h
Météo																												
Vent (km/h)	95	95	100	95	95	100	100	100	80	60	60	80	60	60	80	80	90	80	80	85	70	80	100	100	75	60	60	65
à 4000m																												
Vent (km/h)	40	55	65	60	55	50	30	20	15	25	25	35	25	25	25	30	20	20	20	20	20	25	30	30	20	20	20	20
à 2000m																												

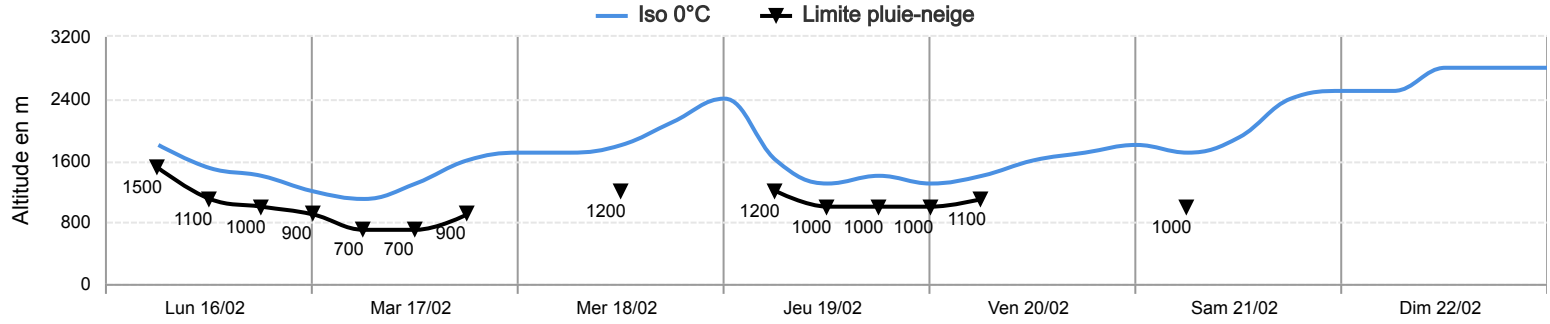

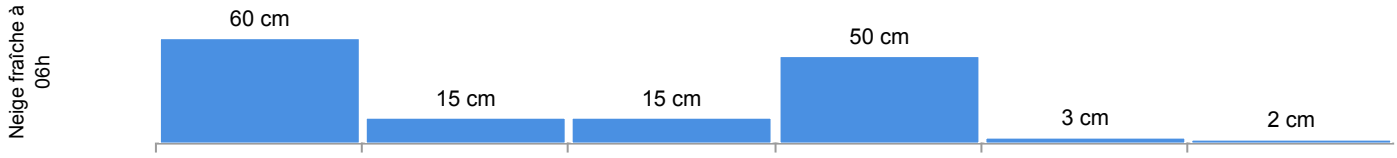

Risque d'avalanche	lun. 16/02	mar. 17/02	mer. 18/02	jeu. 19/02	ven. 20/02	sam. 21/02	dim. 22/02
	4	4	4	5	4	4	3

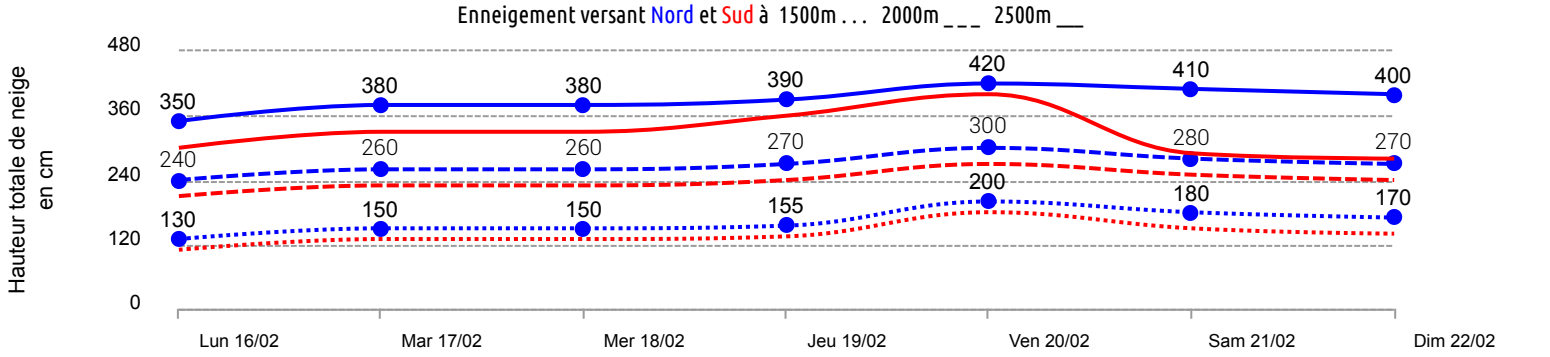

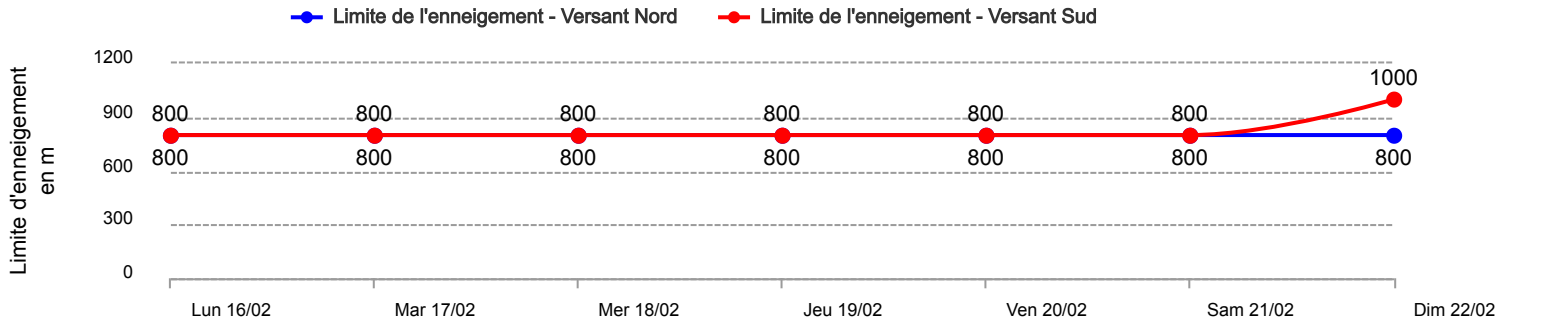

Pour consulter la vigilance en cours, veuillez vous rendre sur le site https://vigilance.meteofrance.fr/fr

Météo-France - 73 avenue de Paris, 94165 Saint-Mandé cedex - Contact : contact@meteo.fr

Rédigé par Météo-France avec la contribution des observateurs du réseau nivo-météorologiques. Partenariat : ANMSM (Maires de Stations de Montagne), DSF (Domaines Skiables de France), ADSP (Directeurs de Pistes et de la Sécurité des Stations de Sports d'Hiver) et autres acteurs de la montagne.

Bulletin neige & avalanches par téléphone au

0 892 68 10 20 Service 0,35 € / min + prix appel